BUTLLETÍ DEL PERILL D'ALLAUS DEL PRINCIPAT D'ANDORRA

Servei meteorològic nacional
Principat d'Andorra

Elaborat el 07/03/2026 16:00
Propera actualització 08/03/2026 a les 16h

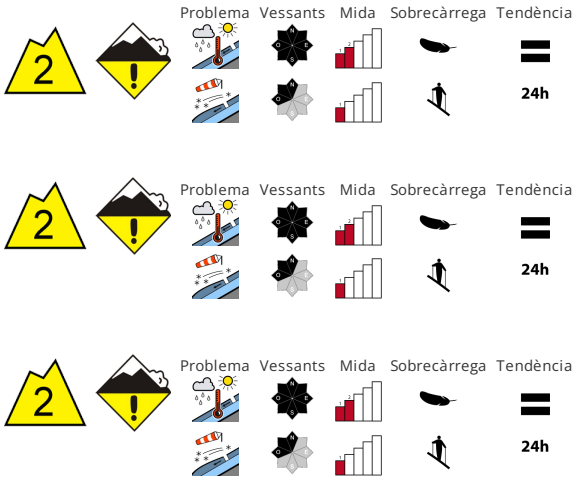

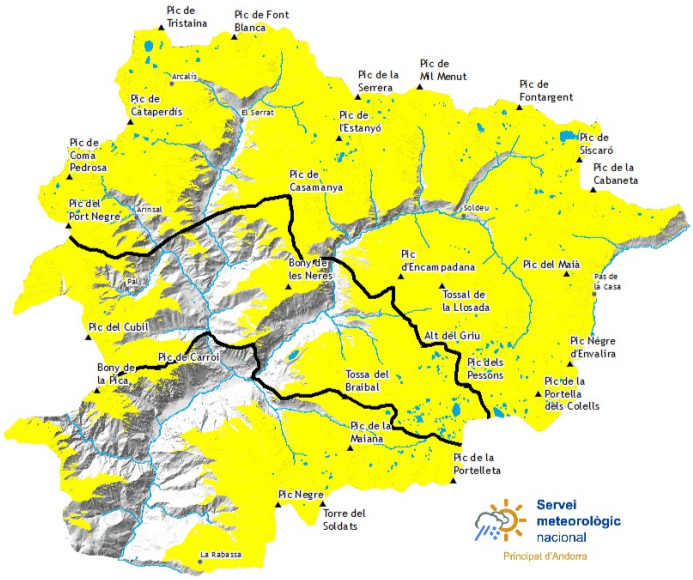

ESTABILITAT DEL MANTELL NIVAL

Amb la humidificació, per sota dels 2000 m aproximadament són d'esperar allaus de neu humida. Aquestes poden desencadenar-se de manera natural i assolir mida mitjana. A més, són d'esperar allaus de lliscament basal en qualsevol moment. A cotes altes :. El vent del sud-est transportarà la neu recent. Amb la neu recent i el vent les plaques de vent augmentaran de mida lleugerament. A més són possibles algunes allaus de placa humida de mida petita. Aquests indrets són parcialment coberts de neu recent i difícils de reconèixer. Els indrets perillosos són difícils de reconèixer amb mala visibilitat.

QUALITAT DE LA NEU

Els gruixos de neu varien molt per sobre dels 2100 m aproximadament per la influència del vent. Evitar les zones amb esquerdes de lliscament basal. El temps serà parcialment assolellat. En alguns sectors durant la tarda cauran localment fins a 5 cm de neu per sobre dels 1800 m aproximadament. A cotes baixes :. La superfície del mantell de neu es regelarà tot just i s'estovarà ràpidament. El perill d'allaus romandrà invariable.

GRUIXOS DEL MANTELL NIVAL FORA DE PISTA

Zona nord		Gruix neu		
Mantell Nival		1500m	2000m	2500m
N	1600 m	0 cm	150 cm	200 cm
S	1900 m	0 cm	100 cm	150 cm

Zona centre		Gruix neu		
Mantell Nival		1500m	2000m	2500m
N	1600 m	0 cm	150 cm	200 cm
S	1900 m	0 cm	100 cm	150 cm

Zona sud		Gruix neu		
Mantell Nival		1500m	2000m	2500m
N	1600 m	0 cm	120 cm	150 cm
S	1900 m	0 cm	60 cm	100 cm

Govern d'Andorra

EAWS EUROPEAN AVALANCHE WARNING SERVICES

Aquest butlletí ha estat elaborat seguint les normes i recomanacions de l'**European Avalanche Warning Services**, del qual el **Servei meteorològic Nacional** n'és membre

BUTLLETÍ DEL PERILL D'ALLAUS DEL PRINCIPAT D'ANDORRA

Servei meteorològic nacional
Principat d'Andorra

Informació detallada per espais naturals protegits

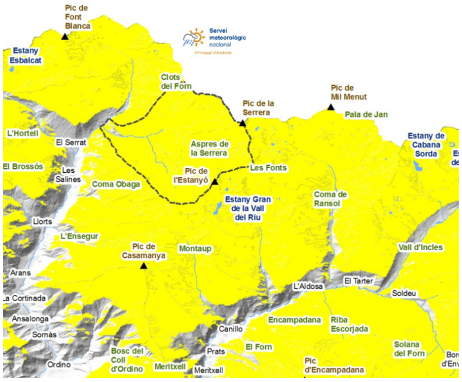

SORTENY

Continuaran les febles precipitacions amb fang i una cota de neu al voltant dels 2000 m, que humidificaran el mantell en totes les orientacions, per sota d´aquesta cota; mentre que per sobre es podran formar febles acumulacions d'uns 5 cm en aquest sector. En altura, el vent podrà transportar la poca neu disponible i formar petites acumulacions irregulars.

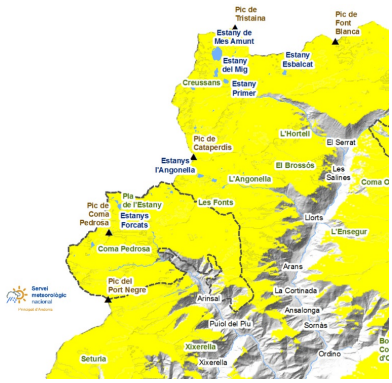

COMAPEDROSA

L´accés des d´Arinsal està quedant cada vegada amb menys neu, i la pluja prevista encara enretirarà més la línia de neu contínua. Mentre durin les precipitacions la mala visibilitat fa desaconsellar les excursions al Parc, però un cop hagin finalitzat, es podran fer nombroses excursions, sempre mantenint una elecció acurada de l´itinerari.

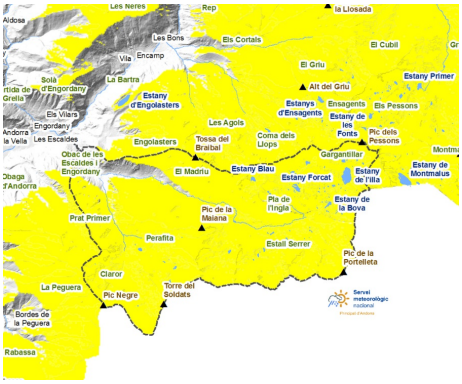

MADRIU-PERAFITA-CLAROR

El mantell és en general prim i irregular, amb millor continuïtat de neu als vessants nord i obacs. Ha estat el sector més afectat per les precipitacions, tot i que en alguns indrets elevats el vent ha deixat la neu vella al descobert. Fins dissabte continuarà essent el sector amb més precipitacions i, per tant, on preveiem la major activitat.

Govern d'Andorra

EAWS
EUROPEAN AVALANCHE WARNING SERVICES

Aquest butlletí ha estat elaborat seguint les normes i recomanacions de l'**European Avalanche Warning Services**, del qual el **Servei meteorològic Nacional** n'és membre

BUTLLETÍ DEL PERILL D'ALLAUS DEL PRINCIPAT D'ANDORRA

Servei meteorològic nacional
Principat d'Andorra

Gruixos de neu nova dels darrers dies (de les últimes 24h mesurat a les 06:00h UTC)

	03/03/2026	04/03/2026	05/03/2026	06/03/2026
FEDA (Central)	0 cm	0 cm	0 cm	0 cm
Engolasters - FEDA	0 cm	0 cm	0 cm	0 cm
Ransol - FEDA	0 cm	0 cm	0 cm	0 cm
Fontverd	0 cm	0 cm	0 cm	1 cm
Setúria	0 cm	0 cm	0 cm	0 cm
Bony de les Neres	0 cm	0 cm	0 cm	2 cm
Grau Roig - FEDA	0 cm	0 cm	3 cm	5 cm
Caborreu	0 cm	0 cm	0 cm	0 cm
Sorteny	0 cm	3 cm	10 cm	5 cm
Coll Pa	0 cm	0 cm	9 cm	9 cm
Perafita	4 cm	3 cm	26 cm	3 cm
Tossa Espiolets	2 cm	0 cm	17 cm	5 cm
La Solana	0 cm	0 cm	10 cm	4 cm
Vall del Riu FEDA	3 cm	0 cm	9 cm	5 cm
Envalira Antenes	4 cm	0 cm	1 cm	13 cm
Les Fonts d'Arinsal	4 cm	0 cm	10 cm	5 cm