# BUTLLETÍ DEL PERILL D'ALLAUS DEL PRINCIPAT D'ANDORRA

Elaborado el 07/03/2026 16:00
Proxima actualización 08/03/2026 a las 16h

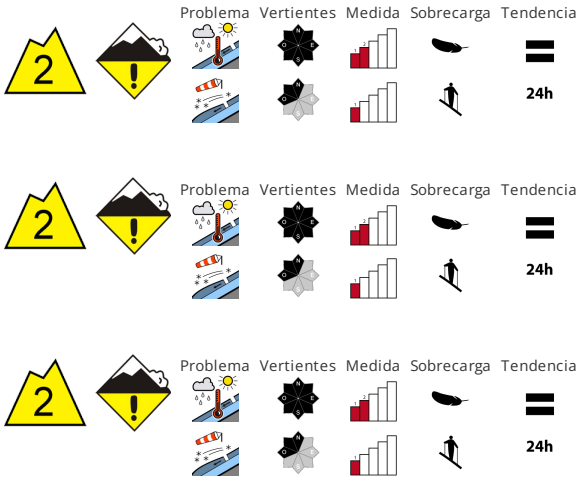


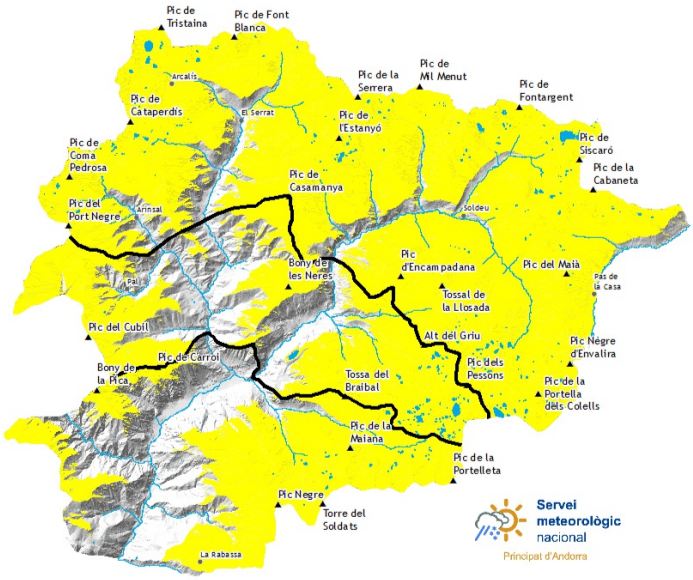


## CALIDAD DE LA NIEVE

Con la humidificación, por debajo de los 2000 m aproximadamente son probables avalanchas de nieve húmeda. Estos pueden desencadenarse de manera natural y alcanzar un tamaño mediano. Además son de esperar aludes de deslizamiento basal en cualquier momento. En cotas altas :. El viento del sudeste transportará la nieve reciente. Con la nieve reciente y el viento las placas de viento aumentarán de tamaño ligeramente. Además son posibles algunas avalanchas de placa húmeda de tamaño pequeño. Estos lugares están parcialmente cubiertos de nieve reciente y resultan difíciles de reconocer. Los lugares peligrosos son resultan difíciles de reconocer con poca visibilidad.

## ESTABILIDAD DEL MANTO NIVOSO

Los espesores de nieve varían mucho por encima de los 2100 m aproximadamente por la influencia del viento. Evitar las zonas con grietas de deslizamiento basal. El tiempo será parcialmente soleado. En algunos sectores durante la tarde caerán localmente hasta 5 cm de nieve por encima de los 1800 m aproximadamente. En cotas bajas :. La superficie del manto de nieve se volverá a helar apenas y se ablandará rápidamente. El peligro de aludes permanecerá invariable.

## ESPESORES DEL MANTO NIVOSO FUERA DE PISTA

| Zona norte | | Espesor nieve | | |
|---|---|---|---|---|
| **Manto Nival** | | 1500m | 2000m | 2500m |
| N | 1600 m | 0 cm | 150 cm | 200 cm |
| S | 1900 m | 0 cm | 100 cm | 150 cm |

| zona centro | | Espesor nieve | | |
|---|---|---|---|---|
| **Manto Nival** | | 1500m | 2000m | 2500m |
| N | 1600 m | 0 cm | 150 cm | 200 cm |
| S | 1900 m | 0 cm | 100 cm | 150 cm |

| Zona sur | | Espesor nieve | | |
|---|---|---|---|---|
| **Manto Nival** | | 1500m | 2000m | 2500m |
| N | 1600 m | 0 cm | 120 cm | 150 cm |
| S | 1900 m | 0 cm | 60 cm | 100 cm |

Govern d'Andorra

EAWS EUROPEAN AVALANCHE WARNING SERVICES

Aquest butlletí ha estat elaborat seguint les normes i recomanacions de l'**European Avalanche Warning Services**, del qual el **Servei meteorològic Nacional** n'és membre

# BUTLLETÍ DEL PERILL D'ALLAUS DEL PRINCIPAT D'ANDORRA

Servei meteorològic nacional
Principat d'Andorra

## Información detallada por espacios naturales protegidos

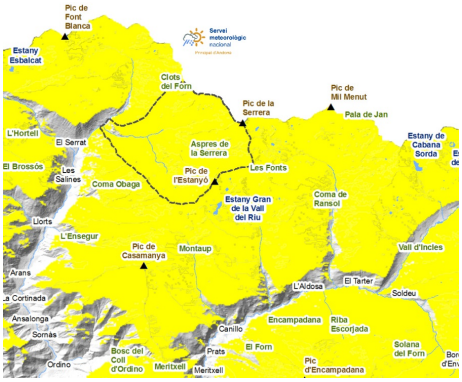


### SORTENY

Continuarán las débiles precipitaciones con barro y una cota de nieve en torno a los 2000 m, que humidificarán el manto en todas las orientaciones, por debajo de esta cota; mientras que por encima se podrán formar débiles acumulaciones de unos 5 cm en este sector. En altura, el viento podrá transportar la poca nieve disponible y formar pequeñas acumulaciones irregulares.

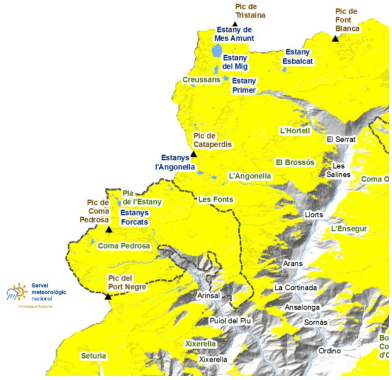


### COMAPEDROSA

El acceso desde Arinsal está quedando cada vez con menos nieve, y la lluvia prevista aún retirará más la línea de nieve continua. Mientras duren las precipitaciones la mala visibilidad hace desaconsejar las excursiones al Parque, pero una vez hayan finalizado, se podrán realizar numerosas excursiones, siempre manteniendo una cuidadosa elección del itinerario.

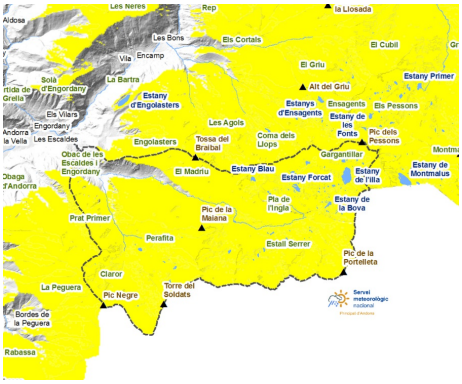


### MADRIU-PERAFITA-CLAROR

El manto es en general delgado e irregular, con mejor continuidad de nieve en las vertientes norte y umbrías. Fue el sector más afectado por las precipitaciones, aunque en algunos lugares elevados el viento dejó la nieve vieja al descubierto. Hasta el sábado continuará siendo el sector con más precipitaciones y, por tanto, donde prevemos la mayor actividad.

# BUTLLETÍ DEL PERILL D'ALLAUS DEL PRINCIPAT D'ANDORRA

Servei meteorològic nacional
Principat d'Andorra

## Espesores de nieve nueva de los últimos días (de las ultimas 24h mesurado a las 06:00h UTC)

| | 03/03/2026 | 04/03/2026 | 05/03/2026 | 06/03/2026 |
|---|---|---|---|---|
| **FEDA (Central)** | 0 cm | 0 cm | 0 cm | 0 cm |
| **Engolasters - FEDA** | 0 cm | 0 cm | 0 cm | 0 cm |
| **Ransol - FEDA** | 0 cm | 0 cm | 0 cm | 0 cm |
| **Fontverd** | 0 cm | 0 cm | 0 cm | 1 cm |
| **Setúria** | 0 cm | 0 cm | 0 cm | 0 cm |
| **Bony de les Neres** | 0 cm | 0 cm | 0 cm | 2 cm |
| **Grau Roig - FEDA** | 0 cm | 0 cm | 3 cm | 5 cm |
| **Caborreu** | 0 cm | 0 cm | 0 cm | 0 cm |
| **Sorteny** | 0 cm | 3 cm | 10 cm | 5 cm |
| **Coll Pa** | 0 cm | 0 cm | 9 cm | 9 cm |
| **Perafita** | 4 cm | 3 cm | 26 cm | 3 cm |
| **Tossa Espiolets** | 2 cm | 0 cm | 17 cm | 5 cm |
| **La Solana** | 0 cm | 0 cm | 10 cm | 4 cm |
| **Vall del Riu FEDA** | 3 cm | 0 cm | 9 cm | 5 cm |
| **Envalira Antenes** | 4 cm | 0 cm | 1 cm | 13 cm |
| **Les Fonts d'Arinsal** | 4 cm | 0 cm | 10 cm | 5 cm |