# Bulletin d'estimation du risque d'avalanche

(valable en dehors des pistes balisées et ouvertes)

# MASSIF : Aspe Ossau

Rédigé le samedi 7 mars 2026 à 16h

## Estimation des risques pour le : DIMANCHE 08 MARS

**LEGEREMENT PLUS FRAIS, ASSEZ BEAU LE MATIN, AVERSES L'APRES-MIDI.**

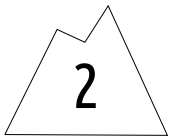


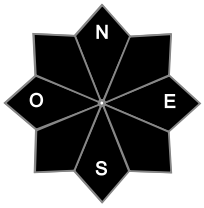


Indice de risque limité.

**Départs spontanés :** en neige humide, souvent ponctuels, avalanches de fond possibles.

**Déclenchements provoqués :** en neige humide généralement, structures de plaques difficilement sollicitables au-dessus de 2400m.

Indices de risque : 5 très fort - 4 fort - 3 marqué - 2 limité - 1 faible -- En noir : les pentes les plus dangereuses

## Stabilité du manteau neigeux

**Situation avalancheuse typique :** neige humide avalanches de fond

**Départs spontanés** : en **neige humide** et souvent sous forme de **départs ponctuels près des rochers** de la **vieille neige lourde** en place, et de la **neige récente tombée samedi au-dessus de 1900/2000m s'humidifiant** rapidement sous les **éclaircies de la matinée en pentes sud**. Avalanches généralement de **taille 1 à 2**, **localement** et **plus rarement** une avalanche de **taille 3 possible** avec le **départ d'avalanches de fond** partant des **accumulations** encore présentes en altitude, emportant la **totalité du manteau neigeux** humide et lourd encore en place en contrebas, notamment près des **ruptures de pentes ou au niveau d'une fissure**.

**Déclenchements provoqués** :
- **déclenchement aisé** pour un skieur ou randonneur d'une **coulée ou petite avalanche** (taille 1) en **neige humide** dans les **pentes raides au soleil au-dessus de 1800/1900m** en matinée; **très localement** et plutôt jusque 2200/2300m, **avalanche de taille 2 possible** au niveau d'une **accumulation** encore en place.
- **à tout moment de la journée** dans les **autres secteurs en dessous de 1800/1900m,** sans regel ou timide et en surface d'un manteau en **neige pourrie en profondeur**, déclenchement **facile à skis ou en raquettes** d'une avalanche de **taille 1** au vu de l'épaisseur du manteau neigeux encore en place.
- **au-dessus de 2400m** dans les versants **nord-ouest à nord-est**, la neige tombée vendredi et samedi en petites quantités recouvrent les **vieilles structures de plaques encore en place**; ces structures localisées dans les **pentes raides ombragées**, avec des couches plus fragiles bien enfouies maintenant et souvent isolées par des couches épaisses avec beaucoup de cohésion, sont désormais **sensibles aux fortes sollicitations**. Le **déclenchement d'une avalanche de plaque de taille 2 à localement 3**, bien que peu probable, reste donc **très localement possibles**.

**Autres** : ponts de neige fragiles. Les corniches encore présentes en altitude près des crêtes et cols au-dessus de 2000 à 2300m le sont également en matinée sous les éclaircies.

## Qualité de la neige

**Enneigement** : faible sous 1600m, bon plus haut, mais hétérogène près des sommets, cols et crêtes, dégarnis en particulier en versants Ouest. Combes plus chargées et corniches encore en place.
**Limites skiables** : à partir de 1500m en versants froids.
**État de la neige** : quelques centimètres de neige fraîche, tombée sans vent, au-dessus de 1700/1800m au petit matin ce dimanche, s'humidifiant au soleil, restant en l'état à l'ombre. Quelques centimètres de neige fraîche se rajouteront progressivement l'après-midi, s'humidifiant par la base de cette nouvelle couche entre 1700 et 1900m, restant meuble au-dessus. Sous 1900m, la neige est pourrie en profondeur, mais légèrement ressaisie en surface au petit matin, restant en l'état à l'ombre, ramollissant au soleil.

## Aperçu météo pour le dimanche 08 mars

| | nuit | matin | après-midi | soir |
|---|---|---|---|---|
| | | | | |

Matinée assez belles avant développement rapide d'averses, légèrement plus frais.

| | | | | |
|---|---|---|---|---|
| **Pluie-Neige** | | 1700 m | 1600 m | |
| **Iso 0 °C** | 1800 m | 1900 m | 1900 m | 1900 m |
| **Vent 1500 m** | ↑ 5 km/h | ↻ 5 km/h | ↑ 5 km/h | ↑ 5 km/h |
| **Vent 3000 m** | ← 20 km/h | ↑ 20 km/h | ↑ 20 km/h | ↖ 15 km/h |

## Épaisseur de neige hors-piste

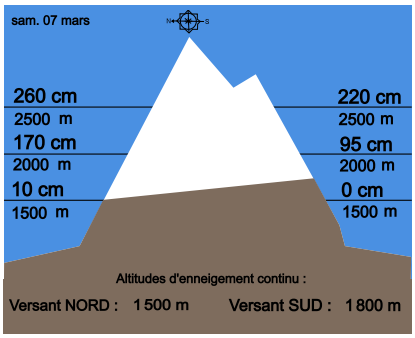


## Précipitations à 1800 m

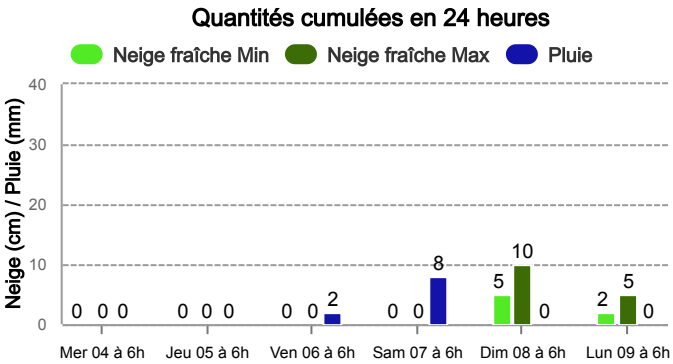


## Tendance du lundi 09 mars

**Indice de risque limité**

Même type de temps attendu mardi, le risque restera limité (activité naturelle essentiellement).

Pour consulter la vigilance en cours, veuillez vous rendre sur le site https://vigilance.meteofrance.fr/fr

Météo-France - 73 avenue de Paris, 94165 Saint-Mandé cedex - Contact : contact@meteo.fr

Rédigé par Météo-France avec la contribution des observateurs du réseau nivo-météorologiques. Partenariat : ANMSM (Maires de Stations de Montagne), DSF (Domaines Skiables de France), ADSP (Directeurs de Pistes et de la Sécurité des Stations de Sports d'Hiver) et autres acteurs de la montagne.

Bulletin neige & avalanches par téléphone au
0 892 68 10 20 Service 0,35 € / min + prix appel

RÉPUBLIQUE FRANÇAISE
*Liberté Égalité Fraternité*

METEO FRANCE
À VOS CÔTÉS, DANS UN CLIMAT QUI CHANGE

# Bulletin d'estimation du risque d'avalanche

## (valable en dehors des pistes balisées et ouvertes)

# MASSIF : Aspe Ossau

Rédigé le samedi 7 mars 2026 à 16h

## Conditions nivo-météo des 7 derniers jours

| | dim. 01/03 | | | | lun. 02/03 | | | | mar. 03/03 | | | | mer. 04/03 | | | | jeu. 05/03 | | | | ven. 06/03 | | | | sam. 07/03 | | | |
|---|---|---|---|---|---|---|---|---|---|---|---|---|---|---|---|---|---|---|---|---|---|---|---|---|---|---|---|---|
| | 03h | 09h | 15h | 21h | 03h | 09h | 15h | 21h | 03h | 09h | 15h | 21h | 03h | 09h | 15h | 21h | 03h | 09h | 15h | 21h | 03h | 09h | 15h | 21h | 03h | 09h | 15h | 21h |
| Météo | | | | | | | | | | | | | | | | | | | | | | | | | | | | |
| Vent (km/h) | 15 | 20 | 60 | 65 | 55 | 45 | 50 | 40 | 35 | 15 | 15 | 15 | 25 | 25 | 30 | 40 | 45 | 45 | 35 | 25 | 20 | 15 | 30 | 50 | 25 | 20 | 25 | 15 |
| à 3000m | | | | | | | | | | | | | | | | | | | | | | | | | | | | |
| Vent (km/h) | 10 | 15 | 35 | 45 | 40 | 35 | 30 | 30 | 25 | 10 | 10 | 10 | 15 | 10 | 15 | 20 | 25 | 25 | 20 | 10 | 10 | 10 | 15 | 10 | 10 | 15 | 10 | 5 |
| à 1500m | | | | | | | | | | | | | | | | | | | | | | | | | | | | |

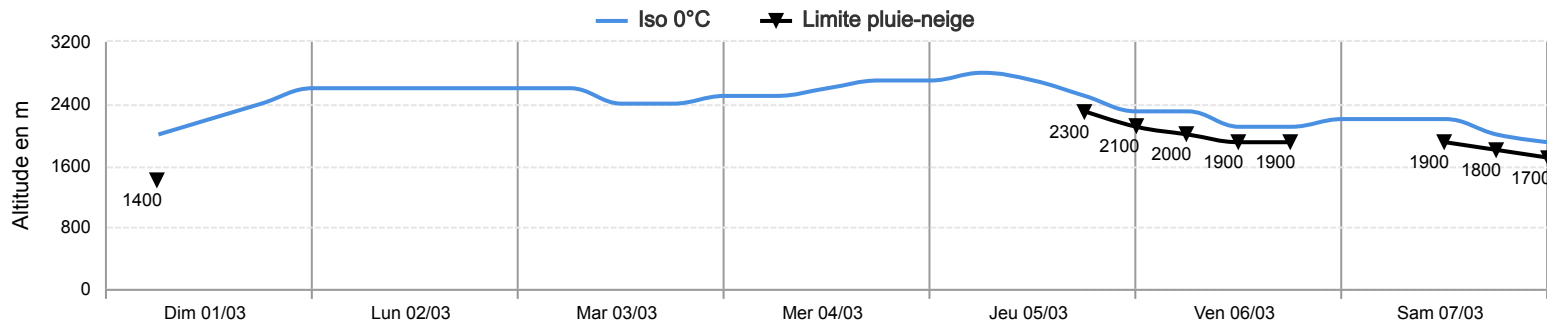


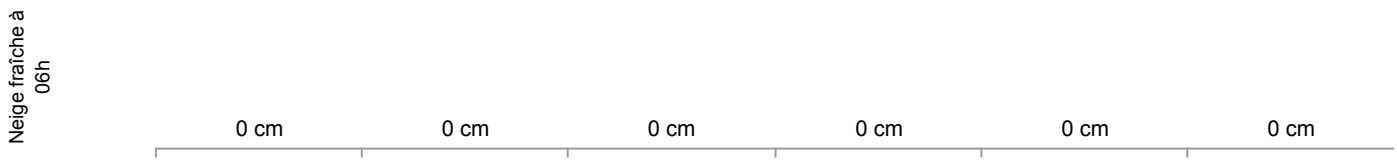


| Risque d'avalanche | dim. 01/03 | lun. 02/03 | mar. 03/03 | mer. 04/03 | jeu. 05/03 | ven. 06/03 | sam. 07/03 |
|---|---|---|---|---|---|---|---|
| | 2 | 2 | 2 | 2 | 2 | 2 | 2 |

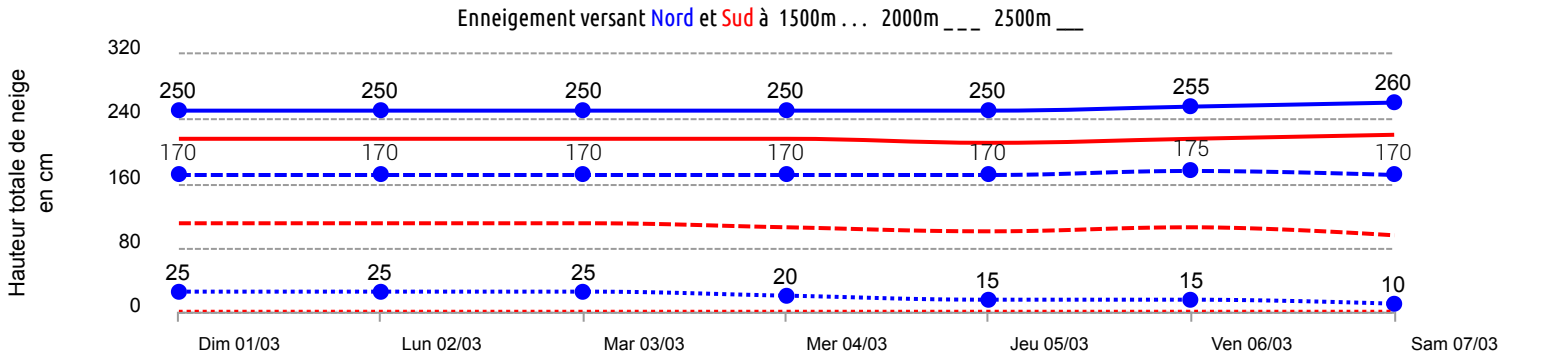


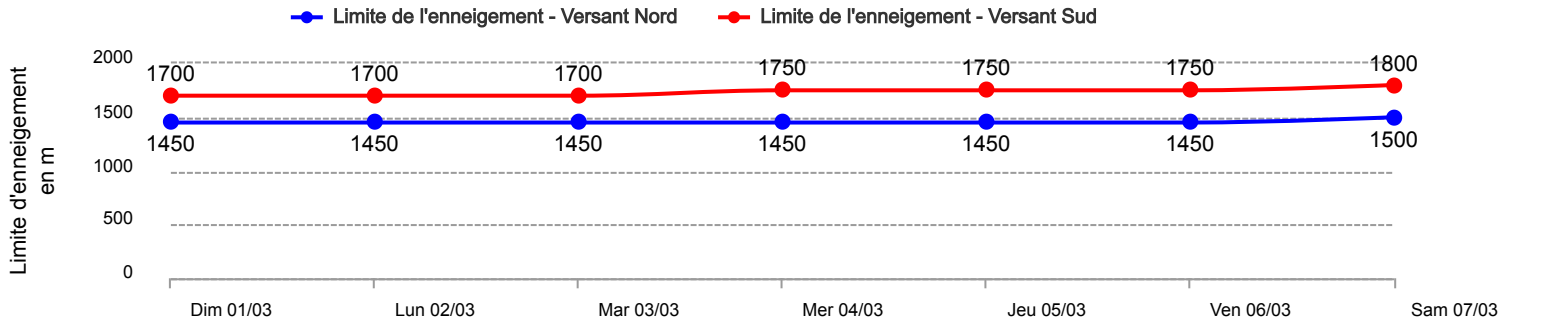


Pour consulter la vigilance en cours, veuillez vous rendre sur le site https://vigilance.meteofrance.fr/fr


**Météo-France - 73 avenue de Paris, 94165 Saint-Mandé cedex - Contact : contact@meteo.fr**


Rédigé par Météo-France avec la contribution des observateurs du réseau nivo-météorologiques. Partenariat : ANMSM (Maires de Stations de Montagne), DSF (Domaines Skiables de France), ADSP (Directeurs de Pistes et de la Sécurité des Stations de Sports d'Hiver) et autres acteurs de la montagne.

**Bulletin neige & avalanches par téléphone au**

**0 892 68 10 20** Service 0,35 € / min + prix appel