Bulletin d'estimation du risque d'avalanche
(valable en dehors des pistes balisées et ouvertes)
MASSIF : Chablais

Rédigé le samedi 7 mars 2026 à 16h

Estimation des risques pour le : DIMANCHE 08 MARS

MANTEAU NEIGEUX PRINTANIER SOUS 2200M, VOIRE PLUS HAUT EN SUD

2

1 → 2

N O E S

Indice de risque faible évoluant en limité.

Départs spontanés : plaques de fond

Déclenchements provoqués : très rares plaques difficiles à déclencher

Indices de risque : 5 très fort - 4 fort - 3 marqué - 2 limité - 1 faible -- En noir : les pentes les plus dangereuses

Stabilité du manteau neigeux

Situation avalancheuse typique : avalanches de fond — neige humide

Départs spontanés :
* quelques **plaques de fond**, de jour comme de nuit, dans les pentes lisses et raides (zones herbeuses, dalles rocheuses). Présentes dans les versants **sud sous 2300 m** et dans les versants **nord sous 2000 m**. Taille 2 (moyenne).
* **avalanches de neige humide**, dans les versants ensoleillés (ouest, sud, est), très rares en début de matinée et **plus nombreuses au fil de la course du soleil**. Taille 1 à 2 (petite à moyenne).

Observables : enfoncement piéton important, escargots.
* Une chute de grosse corniche est possible pouvant déclencher une plaque en contrebas.

Déclenchements provoqués :
* des avalanches de neige humide peuvent partir sous les skis aux heures les plus chaudes, dans les versants ensoleillés. Taille 1 (petite).
* très rares plaques dures sur sous-couche fragile persistante enfouie, au-dessus de 2200 m. Difficile à déclencher. Départ possible par chutes de corniches ou avalanches en cascade. Taille 2 (moyenne) avec d'épaisses cassures.

Qualité de la neige

Enneigement :
Pour la saison, l'enneigement est correct.
On peut chausser les skis vers 1200/1300 m en nord, est et ouest et 1400/1700 m en sud.
Grosses corniches encore présentes.
Faible dépôt de poussières désertiques en surface du manteau neigeux.

Qualité de la neige ce dimanche :
* Sous 1800 m, faible regel, neige rapidement lourde.
* Vers 1800/2200 en versant nord et au-dessus de 1800 m en sud : en début de matinée, croûte de regel portante à ski. Au cours de la journée, le manteau neigeux s'humidifie en surface.
* Au-dessus de 2200/2300 m en nord, nord-est, nord-ouest : neige froide, dense et majoritairement travaillée par le vent.

Aperçu météo pour le dimanche 08 mars

	nuit	matin	après-midi	soir
Poussières désertiques de moins en moins présentes dans l'atmosphère. Le matin, quelques nuages sous 1800 m, petits cumulus l'après-midi.				
Pluie-Neige				
Iso 0 °C	2 300 m	2 200 m	2 300 m	2 200 m
Vent 2000 m	↑ 5 km/h	↓ 5 km/h	↑ 10 km/h	↑ 5 km/h
Vent 2500 m	↑ 10 km/h	← 10 km/h	↑ 20 km/h	↑ 10 km/h

Épaisseur de neige hors-piste

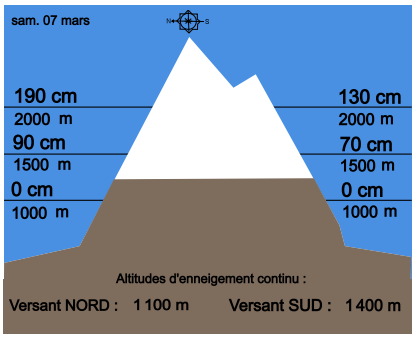

Précipitations à 1800 m

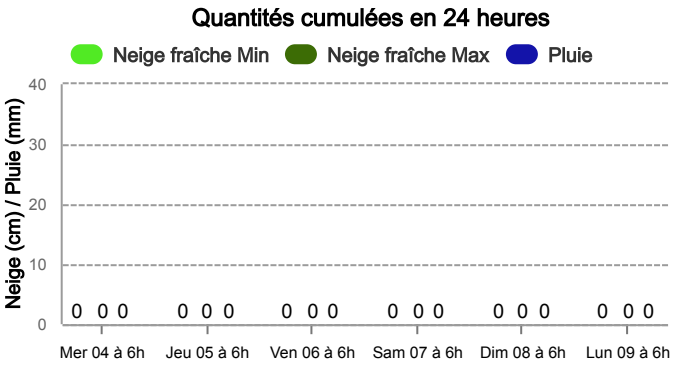

Tendance du lundi 09 mars

2

Indice de risque limité

Lundi, ensoleillé avec peu de vent et un isotherme 0°C vers 2200 m.
⇒ risque stationnaire, peu d'évolution sur le manteau neigeux.

Pour consulter la vigilance en cours, veuillez vous rendre sur le site https://vigilance.meteofrance.fr/fr

Météo-France - 73 avenue de Paris, 94165 Saint-Mandé cedex - Contact : contact@meteo.fr

Rédigé par Météo-France avec la contribution des observateurs du réseau nivo-météorologiques. Partenariat : ANMSM (Maires de Stations de Montagne), DSF (Domaines Skiables de France), ADSP (Directeurs de Pistes et de la Sécurité des Stations de Sports d'Hiver) et autres acteurs de la montagne.

Bulletin neige & avalanches par téléphone au 0 892 68 10 20 Service 0,35 € / min + prix appel

RÉPUBLIQUE FRANÇAISE
Liberté Égalité Fraternité

METEO FRANCE
À VOS CÔTÉS, DANS UN CLIMAT QUI CHANGE

Bulletin d'estimation du risque d'avalanche
(valable en dehors des pistes balisées et ouvertes)

MASSIF : Chablais

Rédigé le samedi 7 mars 2026 à 16h

Conditions nivo-météo des 7 derniers jours

	dim. 01/03				lun. 02/03				mar. 03/03				mer. 04/03				jeu. 05/03				ven. 06/03				sam. 07/03			
	03h	09h	15h	21h	03h	09h	15h	21h	03h	09h	15h	21h	03h	09h	15h	21h	03h	09h	15h	21h	03h	09h	15h	21h	03h	09h	15h	21h
Météo																												
Vent (km/h)	15	20	25	25	25	15	15	10	10	10	10	10	10	10	10	10	10	25	25	15	10	25	20	15	10	20	5	20
à 2500m																												
Vent (km/h)	5	10	20	20	20	10	10	5	5	5	5	5	5	5	5	5	5	20	10	10	5	20	15	10	5	10	5	10
à 2000m																												

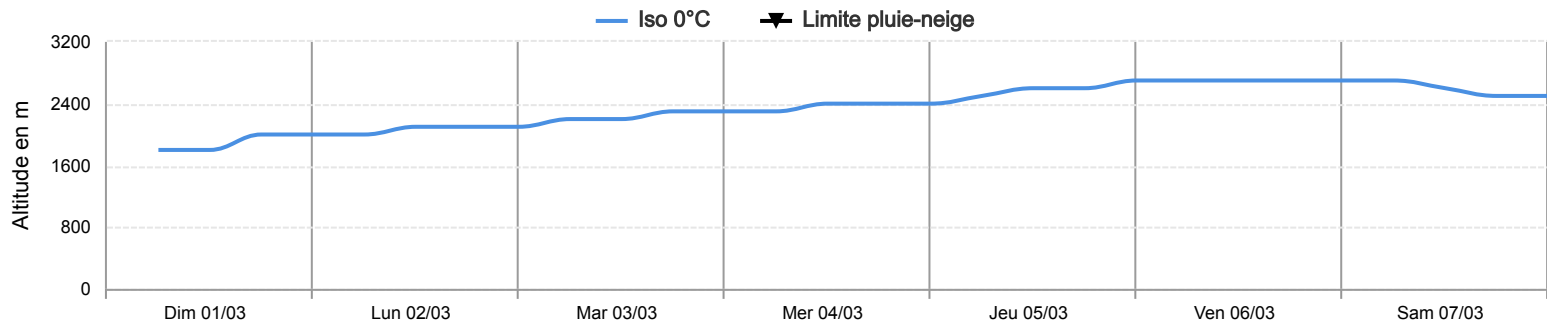

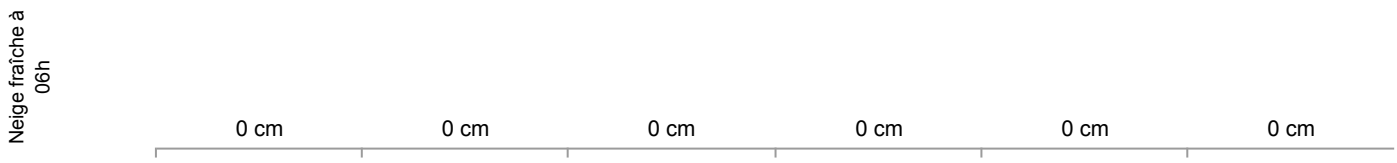

Risque d'avalanche	dim. 01/03	lun. 02/03	mar. 03/03	mer. 04/03	jeu. 05/03	ven. 06/03	sam. 07/03
	2	2	2	2	2	2	2

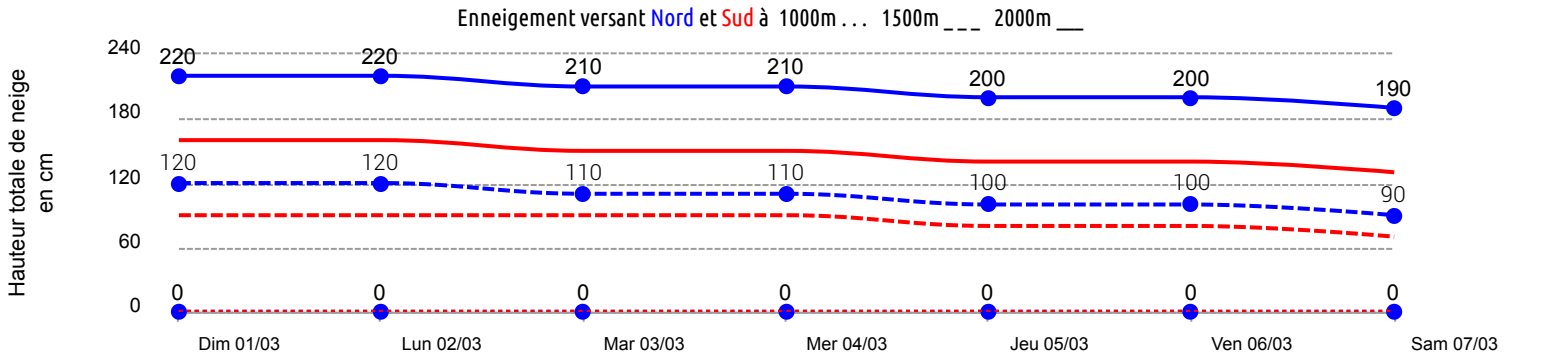

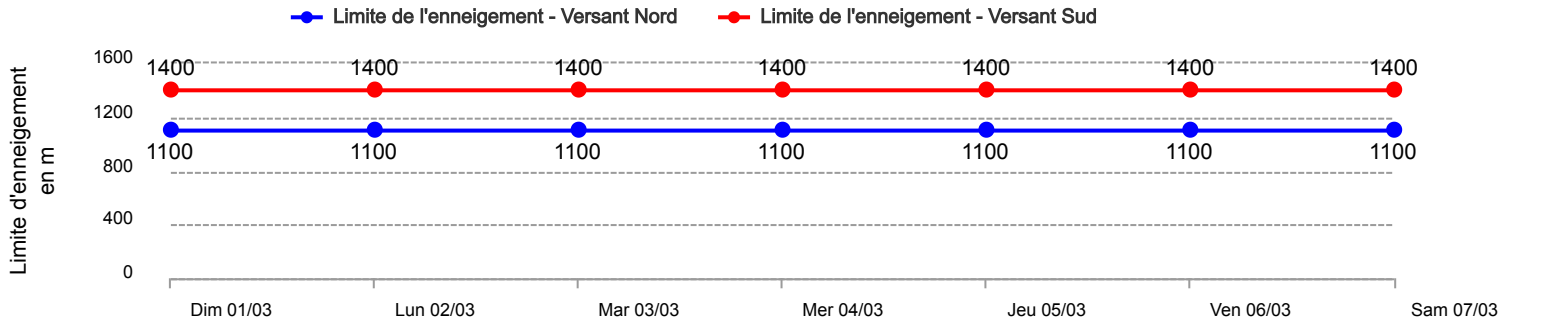

Pour consulter la vigilance en cours, veuillez vous rendre sur le site https://vigilance.meteofrance.fr/fr

Météo-France - 73 avenue de Paris, 94165 Saint-Mandé cedex - Contact : contact@meteo.fr

Rédigé par Météo-France avec la contribution des observateurs du réseau nivo-météorologiques. Partenariat : ANMSM (Maires de Stations de Montagne), DSF (Domaines Skiables de France), ADSP (Directeurs de Pistes et de la Sécurité des Stations de Sports d'Hiver) et autres acteurs de la montagne.

Bulletin neige & avalanches par téléphone au

0 892 68 10 20 Service 0,35 € / min + prix appel