RÉPUBLIQUE FRANÇAISE
*Liberté Égalité Fraternité*

METEO FRANCE
À VOS CÔTÉS, DANS UN CLIMAT QUI CHANGE

# Bulletin d'estimation du risque d'avalanche
## (valable en dehors des pistes balisées et ouvertes)
# MASSIF : Embrunais Parpaillon

Rédigé le samedi 7 mars 2026 à 16h

## Estimation des risques pour le : DIMANCHE 08 MARS

**QUELQUES INSTABILITÉS EN ALTITUDE, DIFFICILES À SOLLICITER - MAINTIEN D'UN PEU D'ACTIVITÉ EN AVALANCHES DE FOND / NEIGE HUMIDE**

2

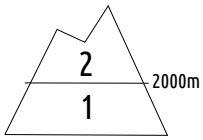


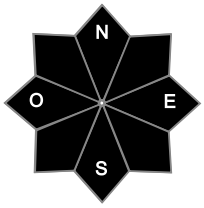


Au-dessus de 2000m indice de risque limité, plus bas indice faible.

**Départs spontanés :** quelques avalanches de fond + activité en neige humide limitée au soleil.

**Déclenchements provoqués :** quelques plaques difficiles à solliciter.

Indices de risque : 5 très fort - 4 fort - 3 marqué - 2 limité - 1 faible -- En noir : les pentes les plus dangereuses

## Stabilité du manteau neigeux

**Situation avalancheuse typique :** couche fragile persistante avalanches de fond

**Déclenchements provoqués :** * Quelques plaques sont encore en place dans le manteau neigeux, mais elles sont difficiles à solliciter. Déclenchement non exclu au passage d'un skieur, surtout dans les ubacs à partir de 2200 m, dans les zones où les épaisseurs de neige sont moins importantes (près des croupes, bords des couloirs etc.). Cassure épaisse en cas de départ, car les couches fragiles persistantes sont enfouies près du sol.
* Un skieur peut favoriser un départ superficiel de neige humide, dans une pente raide ayant bien chauffé au soleil.

**Départs spontanés :** * Quelques avalanches de fond à toute heure du jour ou de la nuit, essentiellement au-dessus de 2000 m, de taille moyenne en général (taille 2). Départ plutôt dans les pentes ouest, sud à est avec terrain favorable (pentes herbeuses, dalles rocheuses).
* Activité en neige humide selon la course du soleil, mais restant limitée. Avalanches généralement petites (taille 1).

## Qualité de la neige

**L'enneigement** est proche des normales. Les limites d'enneigement remontent dans les pentes bien exposées au soleil.

Hauteurs de neige observées : 95 cm à la Nivôse du Parpaillon à 2550 m, secteur soufflé par le vent.

**Limite d'enneigement skiable** : 1400 m en ubacs, plutôt 1700/1800 m en adrets pas trop raides.

**État de la neige de surface** : en début de journée, manteau neigeux croûté dans les adrets, et en ubacs sous 2000/2200 m. Humidification superficielle en cours de journée au soleil.
Dans les pentes nord-ouest à nord-est au-dessus de 2200 m environ, neige encore froide, travaillée par les épisodes de vent passés, ou en vieille poudreuse meuble dans les secteurs abrités.

## Aperçu météo pour le dimanche 08 mars

| | nuit | matin | après-midi | soir |
|---|---|---|---|---|
| | | | | |

Voilé à nuageux. Vent de sud-est sensible sur les crêtes.

| Pluie-Neige | | | | |
|---|---|---|---|---|
| Iso 0 °C | 2 200 m | 2 200 m | 2 300 m | 2 200 m |
| Vent 2000 m | ↖ 10 km/h | ↖ 10 km/h | ↗ 15 km/h | ↙ 10 km/h |
| Vent 3000 m | ↖ 25 km/h | ↖ 25 km/h | ↖ 25 km/h | ↖ 20 km/h |

## Épaisseur de neige hors-piste

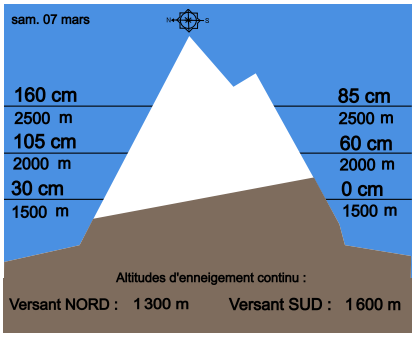


## Précipitations à 1800 m

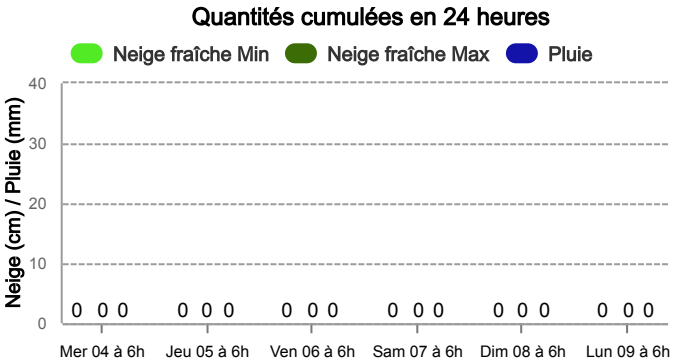


## Tendance du lundi 09 mars

2

**Indice de risque limité**

Situation nivologique similaire. Maintien d'un risque limité, avec les mêmes problématiques.

Pour consulter la vigilance en cours, veuillez vous rendre sur le site https://vigilance.meteofrance.fr/fr

Météo-France - 73 avenue de Paris, 94165 Saint-Mandé cedex - Contact : contact@meteo.fr

Rédigé par Météo-France avec la contribution des observateurs du réseau nivo-météorologiques. Partenariat : ANMSM (Maires de Stations de Montagne), DSF (Domaines Skiables de France), ADSP (Directeurs de Pistes et de la Sécurité des Stations de Sports d'Hiver) et autres acteurs de la montagne.

Bulletin neige & avalanches par téléphone au
**0 892 68 10 20** Service 0,35 € / min + prix appel

RÉPUBLIQUE FRANÇAISE
*Liberté Égalité Fraternité*

METEO FRANCE
À VOS CÔTÉS, DANS UN CLIMAT QUI CHANGE

# Bulletin d'estimation du risque d'avalanche
## (valable en dehors des pistes balisées et ouvertes)
# MASSIF : Embrunais Parpaillon

Rédigé le samedi 7 mars 2026 à 16h

## Conditions nivo-météo des 7 derniers jours

| | dim. 01/03 | | | | lun. 02/03 | | | | mar. 03/03 | | | | mer. 04/03 | | | | jeu. 05/03 | | | | ven. 06/03 | | | | sam. 07/03 | | | |
|---|---|---|---|---|---|---|---|---|---|---|---|---|---|---|---|---|---|---|---|---|---|---|---|---|---|---|---|---|
| | 03h | 09h | 15h | 21h | 03h | 09h | 15h | 21h | 03h | 09h | 15h | 21h | 03h | 09h | 15h | 21h | 03h | 09h | 15h | 21h | 03h | 09h | 15h | 21h | 03h | 09h | 15h | 21h |
| Météo | | | | | | | | | | | | | | | | | | | | | | | | | | | | |
| Vent (km/h) | 15 | 20 | 25 | 20 | 20 | 15 | 20 | 15 | 15 | 10 | 10 | 5 | 5 | 5 | 5 | 15 | 10 | 15 | 25 | 30 | 40 | 45 | 40 | 40 | 35 | 25 | 25 | 20 |
| à 3000m | | | | | | | | | | | | | | | | | | | | | | | | | | | | |
| Vent (km/h) | 5 | 5 | 15 | 10 | 10 | 10 | 15 | 10 | 10 | 10 | 10 | 5 | 10 | 5 | 10 | 10 | 10 | 15 | 20 | 20 | 25 | 25 | 25 | 25 | 25 | 20 | 15 | 10 |
| à 2000m | | | | | | | | | | | | | | | | | | | | | | | | | | | | |

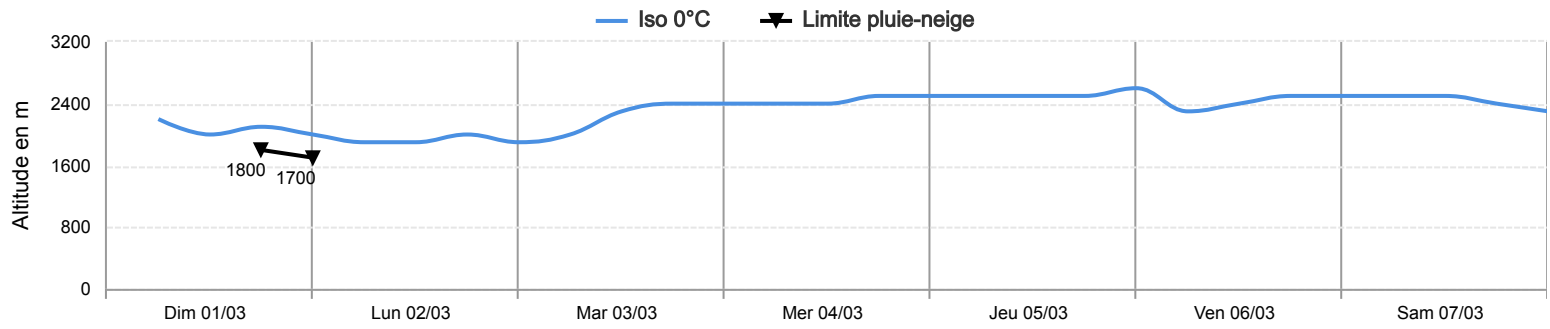


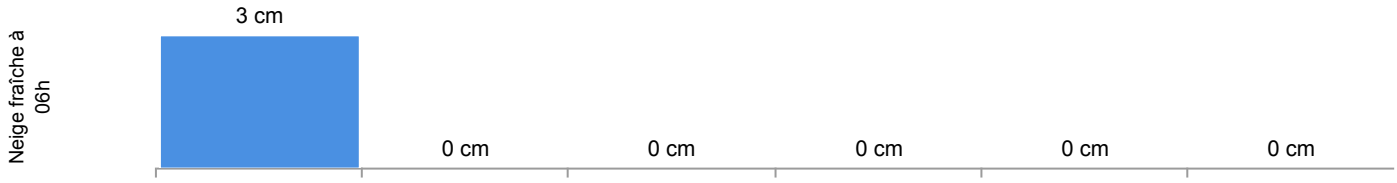


| Risque d'avalanche | dim. 01/03 | lun. 02/03 | mar. 03/03 | mer. 04/03 | jeu. 05/03 | ven. 06/03 | sam. 07/03 |
|---|---|---|---|---|---|---|---|
| | 2 | 2 | 2 | 2 | 2 | 2 | 2 |

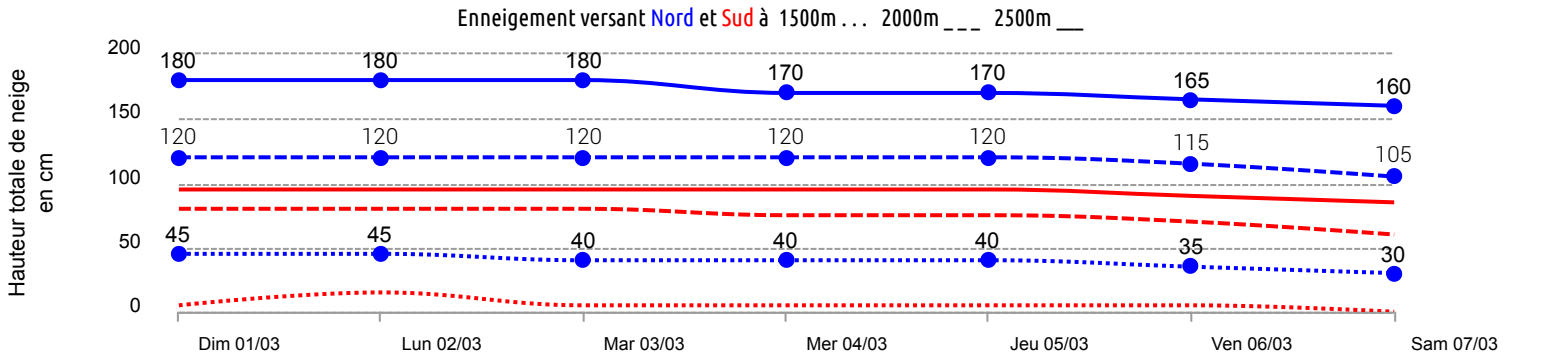


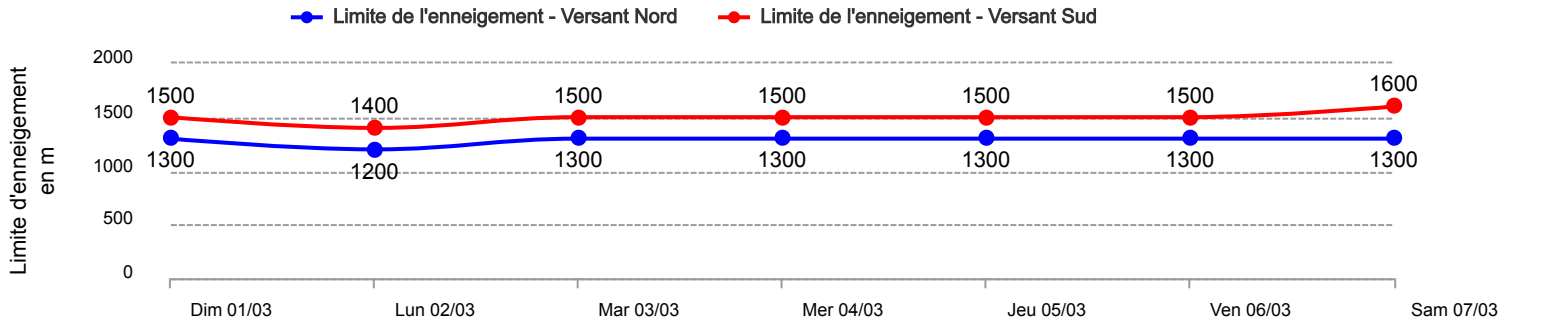


Pour consulter la vigilance en cours, veuillez vous rendre sur le site https://vigilance.meteofrance.fr/fr


Météo-France - 73 avenue de Paris, 94165 Saint-Mandé cedex - Contact : contact@meteo.fr


Bulletin neige & avalanches par téléphone au **0 892 68 10 20** Service 0,35 € / min + prix appel


Rédigé par Météo-France avec la contribution des observateurs du réseau nivo-météorologiques. Partenariat : ANMSM (Maires de Stations de Montagne), DSF (Domaines Skiables de France), ADSP (Directeurs de Pistes et de la Sécurité des Stations de Sports d'Hiver) et autres acteurs de la montagne.