Bulletin d'estimation du risque d'avalanche
(valable en dehors des pistes balisées et ouvertes)

MASSIF : Haut-Var Haut-Verdon

Rédigé le samedi 7 mars 2026 à 16h

Estimation des risques pour le : DIMANCHE 08 MARS

MANTEAU NEIGEUX BIEN STABILISÉ, SAUF ÉVENTUELLEMENT EN UBACS D'ALTITUDE

2

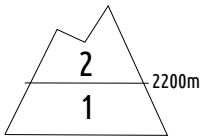

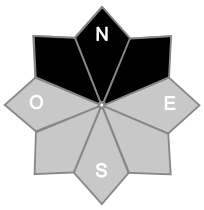

Au-dessus de 2200m indice de risque limité, plus bas indice faible.

Départs spontanés : peu probables

Déclenchements provoqués : instabilités rares et difficiles à déclencher en ubacs d'altitude, mais pouvant être volumineuses

Indices de risque : 5 très fort - 4 fort - 3 marqué - 2 limité - 1 faible -- En noir : les pentes les plus dangereuses

Stabilité du manteau neigeux

Situation avalancheuse typique : couche fragile persistante

Déclenchements provoqués : le manteau neigeux est bien stabilisé. Les instabilités se cantonnent à de rares plaques épaisses reposant sur des couches fragiles persistantes enfouies en orientations nord-ouest, nord ou nord-est au-dessus de 2200 m, surtout sur le Haut-Verdon. Difficilement déclenchables par un seul skieur, elles peuvent cependant mobiliser d'importants volumes de neige en cas de départ (taille moyenne, voire grande non exclue). Des petits départs superficiels sont possibles sous les skis dans les pentes fortement humidifiées.

Départs spontanés : peu probables, sauf éventuellement une avalanche de glissement de taille 2 en pentes d'un large secteur sud, en terrain favorable (pentes herbeuses, dalles rocheuses).

Qualité de la neige

Enneigement plutôt excédentaire pour un début mars en général, notamment dans le Haut-Verdon.
Données observées : vers 2000 m, 165 cm dans le vallon de Valdemars en Haut Verdon, 111 cm dans le vallon de Sanguinière en Haut Var.

Enneigement skiable : vers 1400/1500 m en ubacs, 1800/1900 m en adrets peu pentus.

État de la neige en surface : manteau neigeux printanier dense avec un regel médiocre le matin sous 1800/2000 m. Humidification superficielle en journée dans les pentes ensoleillées. On trouve encore localement de la neige froide en ubacs au dessus de 2200/2300 m, souvent densifiée par le vent. Sur les crêtes, d'anciennes corniches épaisses côtoient des zones dégarnies par le vent.

Aperçu météo pour le dimanche 08 mars

	nuit	matin	après-midi	soir
	Passages nuageux, avec quelques averses de neige possibles l'après-midi.			
Pluie-Neige		1 600 m	1 700 m	
Iso 0 °C	2 100 m	2 000 m	2 100 m	2 000 m
Vent 2000 m	← 15 km/h	↖ 10 km/h	↖ 15 km/h	← 10 km/h
Vent 3000 m	← 20 km/h	← 15 km/h	↖ 15 km/h	← 15 km/h

Épaisseur de neige hors-piste

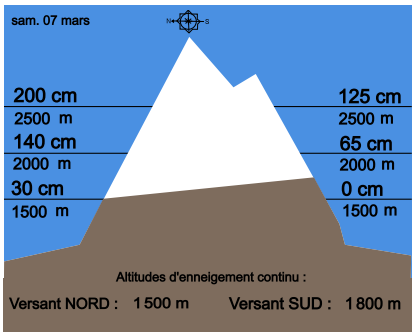

Précipitations à 1800 m

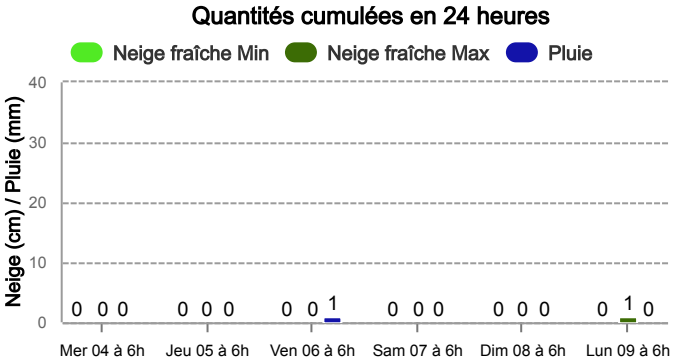

Tendance du lundi 09 mars

2

Indice de risque limité

Peu d'évolution de la situation nivologique. Risque de plaques limité aux ubacs de haute altitude.

Pour consulter la vigilance en cours, veuillez vous rendre sur le site https://vigilance.meteofrance.fr/fr

Météo-France - 73 avenue de Paris, 94165 Saint-Mandé cedex - Contact : contact@meteo.fr

Rédigé par Météo-France avec la contribution des observateurs du réseau nivo-météorologiques. Partenariat : ANMSM (Maires de Stations de Montagne), DSF (Domaines Skiables de France), ADSP (Directeurs de Pistes et de la Sécurité des Stations de Sports d'Hiver) et autres acteurs de la montagne.

Bulletin neige & avalanches par téléphone au 0 892 68 10 20 Service 0,35 € / min + prix appel

RÉPUBLIQUE FRANÇAISE
Liberté Égalité Fraternité

METEO FRANCE
À VOS CÔTÉS, DANS UN CLIMAT QUI CHANGE

Bulletin d'estimation du risque d'avalanche

(valable en dehors des pistes balisées et ouvertes)

MASSIF : Haut-Var Haut-Verdon

Rédigé le samedi 7 mars 2026 à 16h

Conditions nivo-météo des 7 derniers jours

	dim. 01/03				lun. 02/03				mar. 03/03				mer. 04/03				jeu. 05/03				ven. 06/03				sam. 07/03			
	03h	09h	15h	21h	03h	09h	15h	21h	03h	09h	15h	21h	03h	09h	15h	21h	03h	09h	15h	21h	03h	09h	15h	21h	03h	09h	15h	21h
Météo																												
Vent (km/h)	20	15	20	25	15	20	15	15	15	10	10	10	10	10	10	10	15	20	25	45	65	60	55	50	35	30	25	15
à 3000m																												
Vent (km/h)	5	5	15	10	10	10	15	10	10	5	10	10	5	5	10	5	20	20	25	40	45	40	40	35	25	20	15	10
à 2000m																												

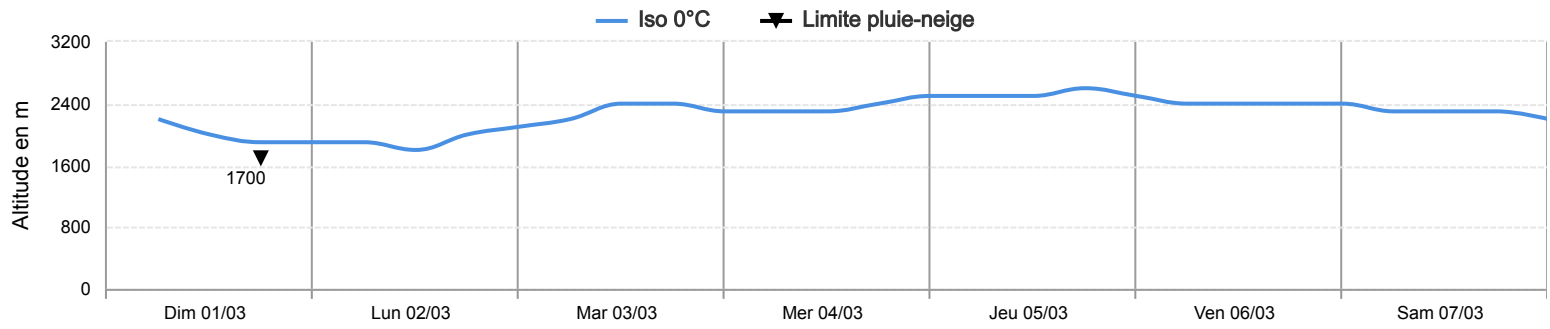

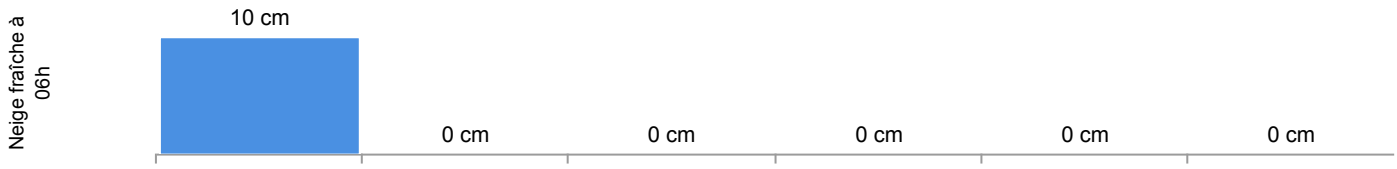

Risque d'avalanche	dim. 01/03	lun. 02/03	mar. 03/03	mer. 04/03	jeu. 05/03	ven. 06/03	sam. 07/03
	2	2	2	2	2	2	2

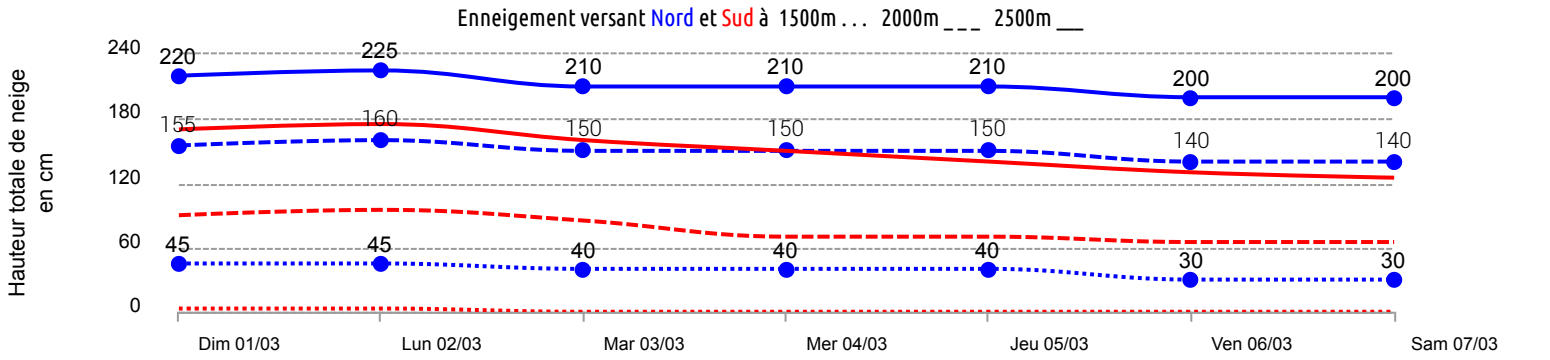

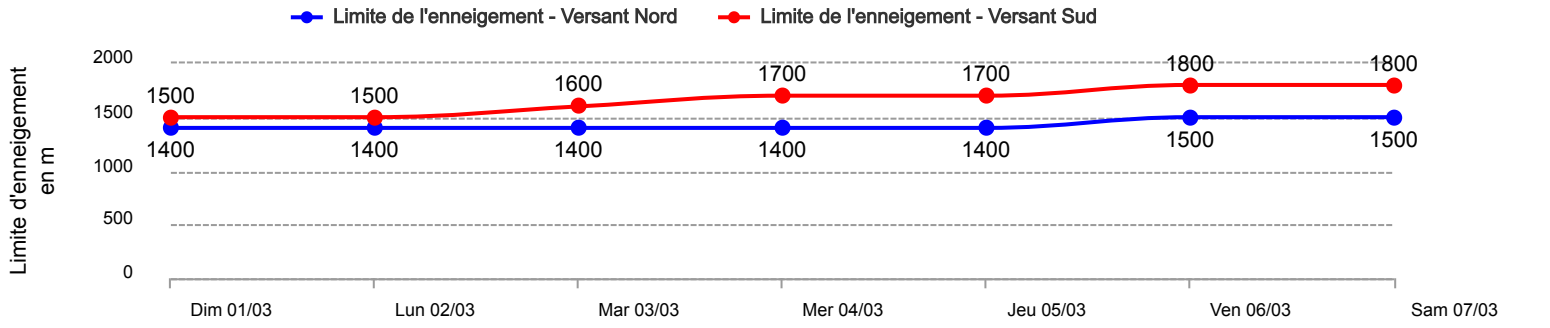

Pour consulter la vigilance en cours, veuillez vous rendre sur le site https://vigilance.meteofrance.fr/fr

Météo-France - 73 avenue de Paris, 94165 Saint-Mandé cedex - Contact : contact@meteo.fr

Rédigé par Météo-France avec la contribution des observateurs du réseau nivo-météorologiques. Partenariat : ANMSM (Maires de Stations de Montagne), DSF (Domaines Skiables de France), ADSP (Directeurs de Pistes et de la Sécurité des Stations de Sports d'Hiver) et autres acteurs de la montagne.

Bulletin neige & avalanches par téléphone au

0 892 68 10 20 Service 0,35 € / min + prix appel