Bulletin d'estimation du risque d'avalanche
(valable en dehors des pistes balisées et ouvertes)

MASSIF : Haute-Ariege

Rédigé le samedi 7 mars 2026 à 16h

Estimation des risques pour le : DIMANCHE 08 MARS

HUMIDIFICATION GÉNÉRALISÉE SOUS 2000/2200M; QUELQUES STRUCTURES DE PLAQUES EN ALTITUDE AVEC LE TRANSPORT DE NEIGE PAR LE VENT

2

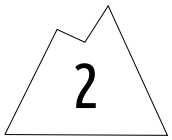

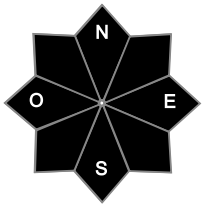

Indice de risque limité.

Départs spontanés : Quelques avalanches de neige humide

Déclenchements provoqués : Fines structures de plaques en altitude

Indices de risque : 5 très fort - 4 fort - 3 marqué - 2 limité - 1 faible -- En noir : les pentes les plus dangereuses

Stabilité du manteau neigeux

Situation avalancheuse typique : neige humide neige ventée

Départs spontanés :
Du fait des éclaircies, des avalanches de neige humide de taille petite à moyenne sont à attendre sous 2000/2200m dans les secteurs ensoleillés, voire un peu plus haut si les éclaircies se révèlent généreuses demain. De plus, des avalanches de fond en neige humide en dessous de 2000m, ainsi que leur signe précurseur que sont les gueules de baleine, ont été signalées et sont à nouveau susceptibles de se produire d'ici demain soir. Enfin, une chute de corniche reste une éventualité.

Déclenchements provoqués :
Dans les secteurs restés froids, avalanches de plaques facilement déclenchables dans la neige récente au-dessus de 2000/2200m. Ces plaques sont généralement assez fines et localisées, plutôt proche des crêtes. On trouve aussi localement des couches fragiles plus enfouies dans les secteurs nord d'altitude, mais sont difficilement déclenchables.
Observables : neige travaillée par le vent en surface, corniches surplombant la pente.

Qualité de la neige

Enneigement :
L'enneigement est encore excédentaire dès la moyenne montagne grâce aux perturbations neigeuses qui se sont succédé depuis le début de l'année.
La limite skiable se situe vers 1600m plein sud alors que certaines vallées ombragées sont encore enneigées dès 1300/1400m. Sur les parties hautes du massif, les pentes ouest ont souvent été rabotées par le vent.

Qualité de la neige :
Au petit matin, dès 1600/1800m, on pourra trouver une fine couche de neige aux quelques endroits où les averses de ce samedi se seront produites. Elle repose sur une couche de neige humidifiée en profondeur jusqu'à 2000/2200m en nord et encore plus haut en secteurs ensoleillés. Là où cette couche humidifiée est directement en surface, le regel est assez incertain, dépendant des éclaircies qui pourraient se produire en cours de nuit. Plus haut, on trouvera une petite couche de neige récente, fréquemment compacte sous 2500 m, plus froide en altitude et restant poudreuse dans les combes abritées de haute montagne.

Aperçu météo pour le dimanche 08 mars

	nuit	matin	après-midi	soir
	Eclaircies le matin, puis quelques averses l'après-midi			
Pluie-Neige			1 700 m	1 600 m
Iso 0 °C	2 200 m	1 900 m	2 000 m	2 000 m
Vent 2000 m	↑ 25 km/h	↑ 20 km/h	↑ 20 km/h	↗ 15 km/h
Vent 3000 m	↑ 30 km/h	↑ 25 km/h	↗ 25 km/h	↗ 20 km/h

Épaisseur de neige hors-piste

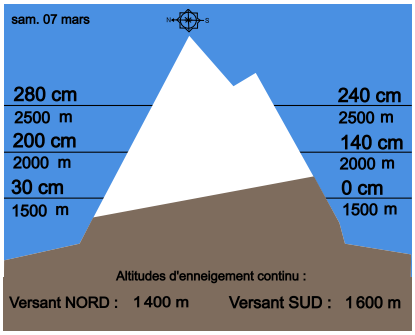

Précipitations à 1800 m

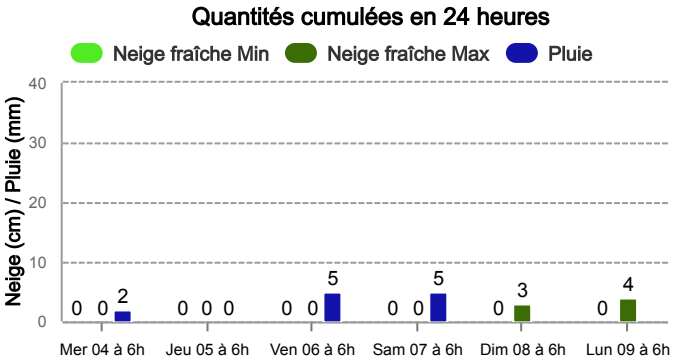

Tendance du lundi 09 mars

2

Indice de risque limité

Peu d'évolution du scenario nivo-météorologique

Pour consulter la vigilance en cours, veuillez vous rendre sur le site https://vigilance.meteofrance.fr/fr

Météo-France - 73 avenue de Paris, 94165 Saint-Mandé cedex - Contact : contact@meteo.fr

Rédigé par Météo-France avec la contribution des observateurs du réseau nivo-météorologiques. Partenariat : ANMSM (Maires de Stations de Montagne), DSF (Domaines Skiables de France), ADSP (Directeurs de Pistes et de la Sécurité des Stations de Sports d'Hiver) et autres acteurs de la montagne.

Bulletin neige & avalanches par téléphone au
0 892 68 10 20 Service 0,35 € / min + prix appel

RÉPUBLIQUE FRANÇAISE
Liberté Égalité Fraternité

METEO FRANCE
À VOS CÔTÉS, DANS UN CLIMAT QUI CHANGE

Bulletin d'estimation du risque d'avalanche

(valable en dehors des pistes balisées et ouvertes)

MASSIF : Haute-Ariege

Rédigé le samedi 7 mars 2026 à 16h

Conditions nivo-météo des 7 derniers jours

	dim. 01/03				lun. 02/03				mar. 03/03				mer. 04/03				jeu. 05/03				ven. 06/03				sam. 07/03			
	03h	09h	15h	21h	03h	09h	15h	21h	03h	09h	15h	21h	03h	09h	15h	21h	03h	09h	15h	21h	03h	09h	15h	21h	03h	09h	15h	21h
Météo																												
Vent (km/h)	20	25	30	40	40	50	50	45	35	25	20	20	25	25	30	40	40	35	30	30	40	25	25	25	40	45	45	40
à 3000m																												
Vent (km/h)	10	20	25	30	30	35	35	30	35	25	20	15	20	20	25	30	35	30	20	20	25	15	20	20	20	40	35	30
à 2000m																												

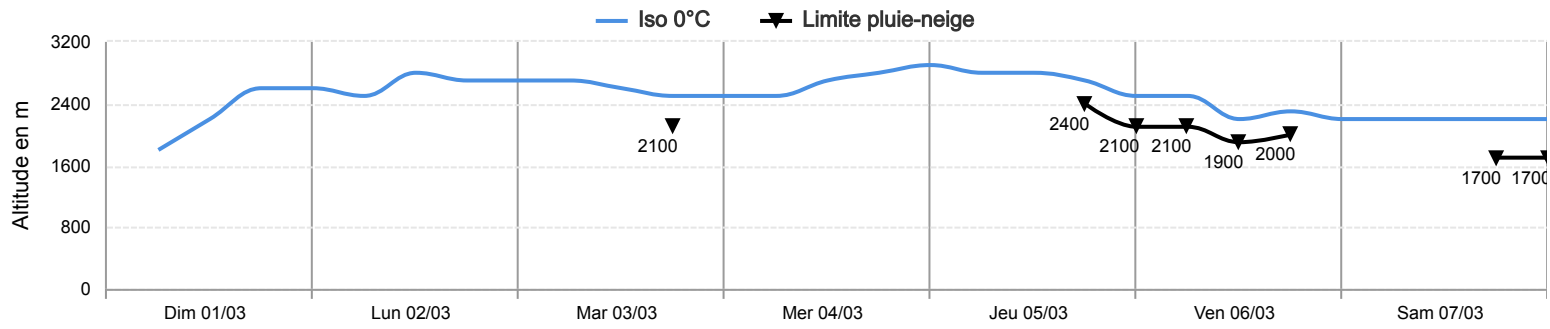

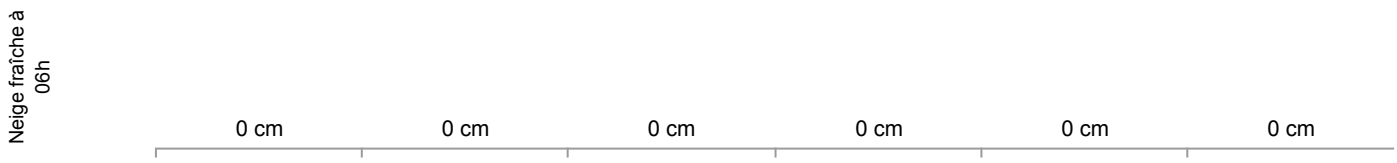

Risque d'avalanche	dim. 01/03	lun. 02/03	mar. 03/03	mer. 04/03	jeu. 05/03	ven. 06/03	sam. 07/03
	2	2	2	2	2	2	2

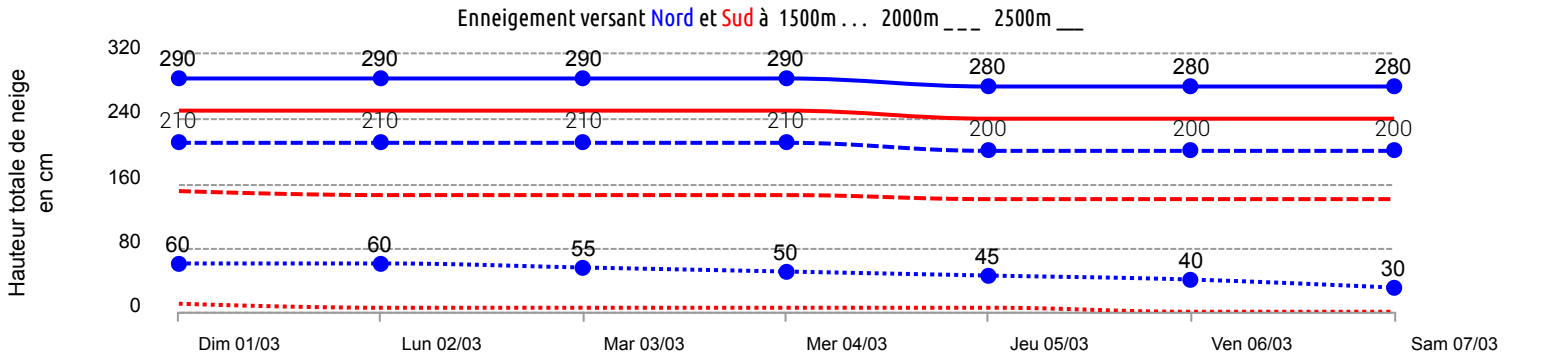

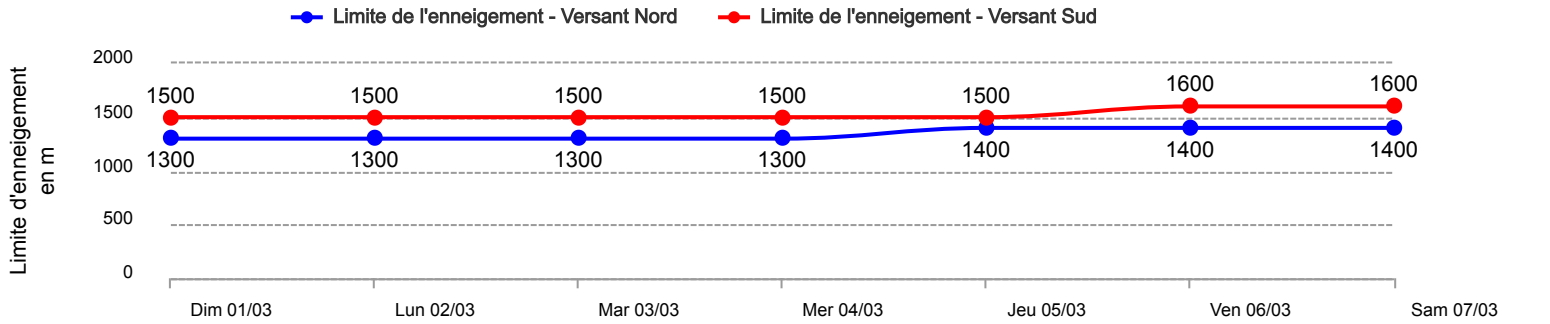

Pour consulter la vigilance en cours, veuillez vous rendre sur le site https://vigilance.meteofrance.fr/fr

Météo-France - 73 avenue de Paris, 94165 Saint-Mandé cedex - Contact : contact@meteo.fr

Rédigé par Météo-France avec la contribution des observateurs du réseau nivo-météorologiques. Partenariat : ANMSM (Maires de Stations de Montagne), DSF (Domaines Skiables de France), ADSP (Directeurs de Pistes et de la Sécurité des Stations de Sports d'Hiver) et autres acteurs de la montagne.

Bulletin neige & avalanches par téléphone au
0 892 68 10 20 Service 0,35 € / min + prix appel