Bulletin d'estimation du risque d'avalanche

(valable en dehors des pistes balisées et ouvertes)

MASSIF : Pays-Basque

Rédigé le samedi 7 mars 2026 à 16h

Estimation des risques pour le : DIMANCHE 08 MARS

LEGEREMENT PLUS FRAIS, ASSEZ BEAU LE MATIN, AVERSES L'APRES-MIDI.

2

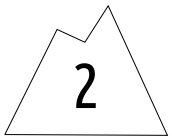

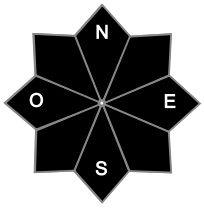

Indice de risque limité.

Départs spontanés : en neige humide, souvent ponctuels, avalanches de fond possibles.

Déclenchements provoqués : en neige humide.

Indices de risque : 5 très fort - 4 fort - 3 marqué - 2 limité - 1 faible -- En noir : les pentes les plus dangereuses

Stabilité du manteau neigeux

Situation avalancheuse typique : neige humide avalanches de fond

Départs spontanés : en **neige humide** et souvent sous forme de **départs ponctuels près des rochers** de la **vieille neige lourde** en place, et de la **neige récente tombée samedi au-dessus de 1900/2000m s'humidifiant** rapidement sous les **éclaircies de la matinée en pentes sud**. Avalanches généralement de **taille 1 à 2**, **très localement** et **plus rarement** une avalanche de **taille 3 possible** avec le **départ d'une avalanche de fond** partant d'une **accumulation** présente en altitude, emportant la **totalité du manteau neigeux** humide et lourd encore en place en contrebas, notamment près des **ruptures de pentes ou au niveau d'une fissure**.

Déclenchements provoqués :
- **déclenchement aisé** pour un skieur ou randonneur d'une **coulée ou petite avalanche** (taille 1) en **neige humide** dans les **pentes raides au soleil au-dessus de 1800/1900m** en matinée; **très localement** et plutôt sur le **haut du massif, avalanche de taille 2 possible** au niveau d'une **accumulation** encore en place.
- **à tout moment de la journée** dans les **autres secteurs en dessous de 1800/1900m,** sans regel ou timide et en surface d'un manteau en **neige pourrie en profondeur**, déclenchement **facile à skis ou en raquettes** d'une avalanche de **taille 1** au vu de l'épaisseur du manteau neigeux encore en place.

Autres : ponts de neige fragiles. Les corniches encore présentes sur le haut du massif le sont également en matinée sous les éclaircies.

Qualité de la neige

Enneigement : faible sous 1600m, bon plus haut, mais hétérogène près des sommets, cols et crêtes, dégarnis en particulier en versants Ouest. Combes plus chargées et corniches encore en place.
Limites skiables : à partir de 1500/1600m en versants froids.
État de la neige : quelques centimètres de neige fraîche, tombée sans vent, au-dessus de 1700/1800m au petit matin ce dimanche, s'humidifiant au soleil, restant en l'état à l'ombre. Quelques centimètres de neige fraîche se rajouteront progressivement l'après-midi, s'humidifiant par la base de cette nouvelle couche entre 1700 et 1900m, restant meuble au-dessus. Sous 1900m, la neige est pourrie en profondeur, mais légèrement ressaisie en surface au petit matin, restant en l'état à l'ombre, ramollissant au soleil.

Aperçu météo pour le dimanche 08 mars

	nuit	matin	après-midi	soir
Pluie-Neige		1 700 m	1 600 m	
Iso 0 °C	1 800 m	1 900 m	1 900 m	1 900 m
Vent 1000 m	10 km/h	5 km/h	5 km/h	5 km/h
Vent 2000 m	25 km/h	20 km/h	15 km/h	15 km/h

Matinée assez belles avant développement rapide d'averses, légèrement plus frais.

Épaisseur de neige hors-piste

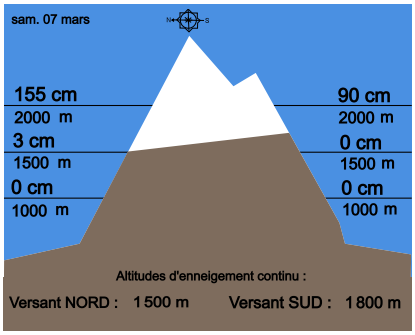

Précipitations à 1800 m

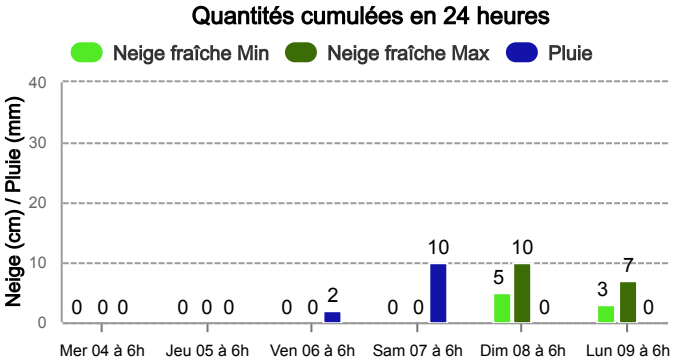

Tendance du lundi 09 mars

2

Indice de risque limité

Même type de temps attendu mardi, le risque restera limité (activité naturelle essentiellement).

Pour consulter la vigilance en cours, veuillez vous rendre sur le site https://vigilance.meteofrance.fr/fr

Météo-France - 73 avenue de Paris, 94165 Saint-Mandé cedex - Contact : contact@meteo.fr

Rédigé par Météo-France avec la contribution des observateurs du réseau nivo-météorologiques. Partenariat : ANMSM (Maires de Stations de Montagne), DSF (Domaines Skiables de France), ADSP (Directeurs de Pistes et de la Sécurité des Stations de Sports d'Hiver) et autres acteurs de la montagne.

Bulletin neige & avalanches par téléphone au

0 892 68 10 20 Service 0,35 € / min + prix appel

RÉPUBLIQUE FRANÇAISE
Liberté Égalité Fraternité

METEO FRANCE
À VOS CÔTÉS, DANS UN CLIMAT QUI CHANGE

Bulletin d'estimation du risque d'avalanche
(valable en dehors des pistes balisées et ouvertes)
MASSIF : Pays-Basque

Rédigé le samedi 7 mars 2026 à 16h

Conditions nivo-météo des 7 derniers jours

	dim. 01/03				lun. 02/03				mar. 03/03				mer. 04/03				jeu. 05/03				ven. 06/03				sam. 07/03			
	03h	09h	15h	21h	03h	09h	15h	21h	03h	09h	15h	21h	03h	09h	15h	21h	03h	09h	15h	21h	03h	09h	15h	21h	03h	09h	15h	21h
Météo																												
Vent (km/h)	30	50	75	85	85	80	80	70	50	25	15	20	25	25	55	70	70	60	45	35	30	25	25	15	20	25	25	20
à 2000m	↑	↑	↑	↑	↑	↑	↑	↑	↑	↑	↙	↑	↑	↑	↑	↑	↑	↑	↓	↙	↙	↓	↓	↙	↓	↖	↙	↑
Vent (km/h)	15	25	50	55	60	55	45	40	35	20	15	10	15	15	25	50	50	35	25	20	15	15	15	5	5	10	10	10
à 1000m	↙	↑	↑	↑	↑	↑	↑	↑	↑	↑	←	↑	↑	↑	↖	↑	↑	↑	↓	↓	↘	↓	↓	↻	↻	↓	↻	↑

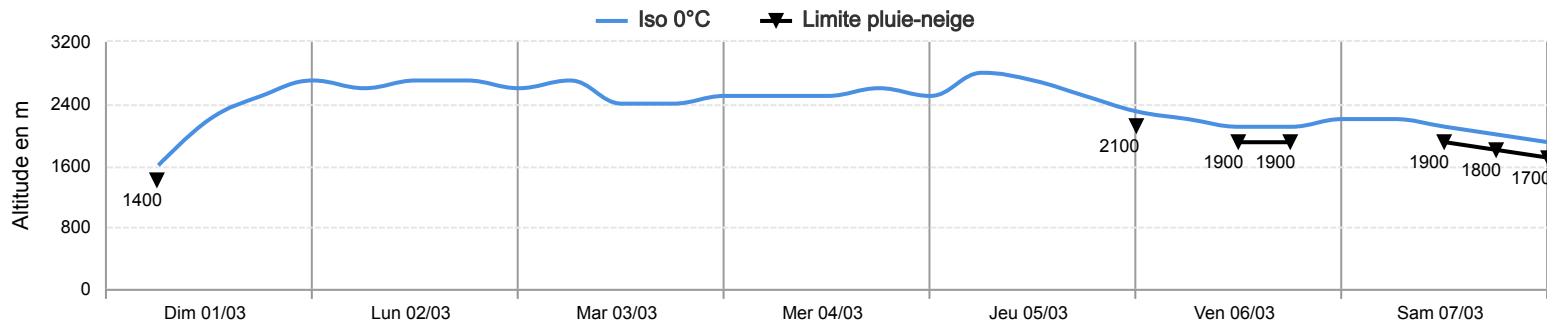

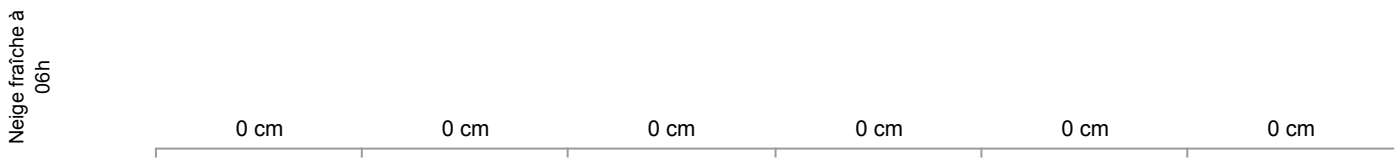

Risque d'avalanche	dim. 01/03	lun. 02/03	mar. 03/03	mer. 04/03	jeu. 05/03	ven. 06/03	sam. 07/03
	1	1	2	2	2	2	2

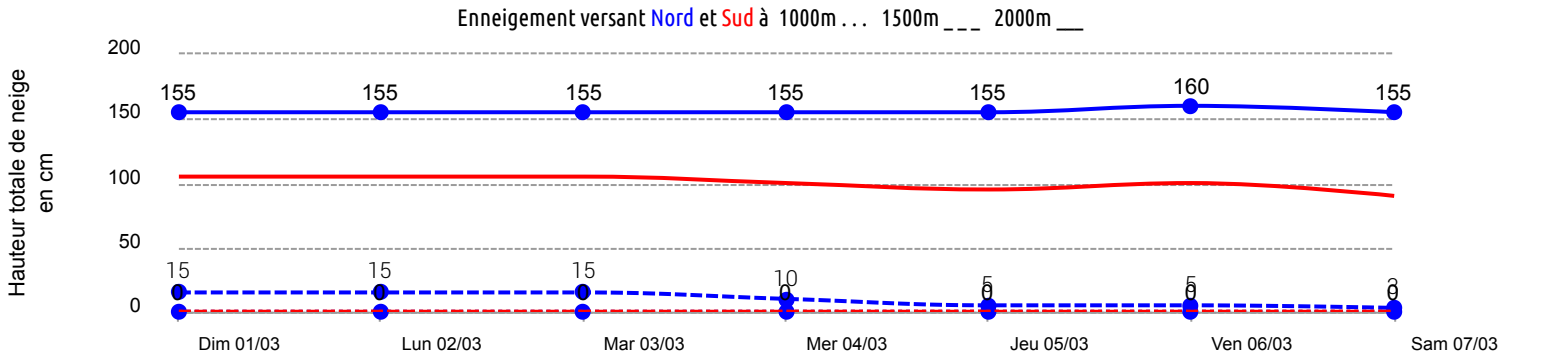

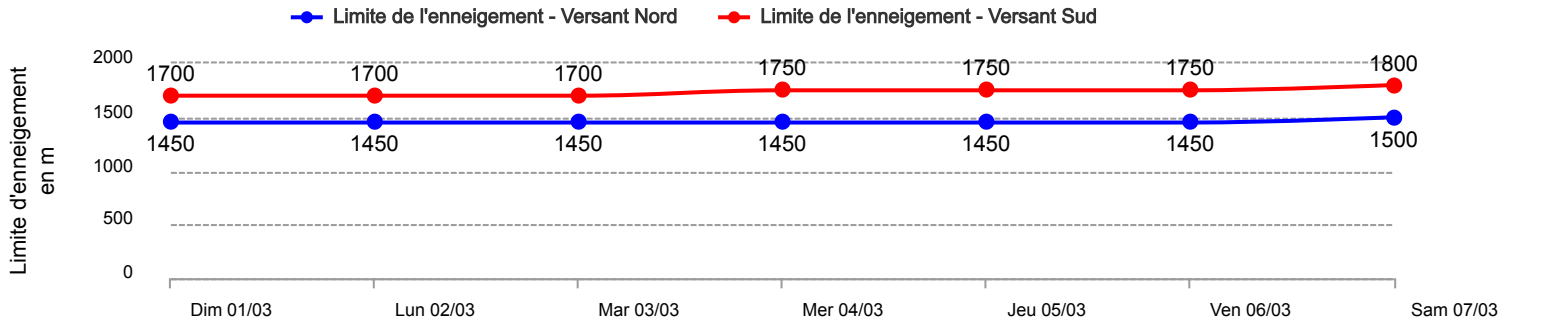

Pour consulter la vigilance en cours, veuillez vous rendre sur le site https://vigilance.meteofrance.fr/fr

Météo-France - 73 avenue de Paris, 94165 Saint-Mandé cedex - Contact : contact@meteo.fr

Rédigé par Météo-France avec la contribution des observateurs du réseau nivo-météorologiques. Partenariat : ANMSM (Maires de Stations de Montagne), DSF (Domaines Skiables de France), ADSP (Directeurs de Pistes et de la Sécurité des Stations de Sports d'Hiver) et autres acteurs de la montagne.

Bulletin neige & avalanches par téléphone au
0 892 68 10 20 Service 0,35 € / min + prix appel