RÉPUBLIQUE FRANÇAISE
Liberté Égalité Fraternité

METEO FRANCE
À VOS CÔTÉS, DANS UN CLIMAT QUI CHANGE

Bulletin d'estimation du risque d'avalanche
(valable en dehors des pistes balisées et ouvertes)

MASSIF : Queyras

Rédigé le samedi 7 mars 2026 à 16h

Estimation des risques pour le : DIMANCHE 08 MARS

QUELQUES INSTABILITÉS EN ALTITUDE, DIFFICILES À SOLLICITER - MAINTIEN D'UN PEU D'ACTIVITÉ EN AVALANCHES DE FOND / NEIGE HUMIDE

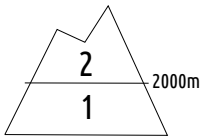

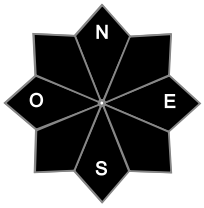

Au-dessus de 2000m indice de risque limité, plus bas indice faible.

Départs spontanés : quelques avalanches de fond + activité en neige humide limitée au soleil.

Déclenchements provoqués : quelques plaques difficiles à solliciter.

Indices de risque : 5 très fort - 4 fort - 3 marqué - 2 limité - 1 faible -- En noir : les pentes les plus dangereuses

Stabilité du manteau neigeux

Situation avalancheuse typique : couche fragile persistante avalanches de fond

Déclenchements provoqués : * Quelques plaques sont encore en place dans le manteau neigeux, mais elles sont difficiles à solliciter. Déclenchement non exclu au passage d'un skieur, surtout dans les ubacs à partir de 2200 m, dans les zones où les épaisseurs de neige sont moins importantes (près des croupes, bords des couloirs etc.). Cassure épaisse en cas de départ, car les couches fragiles persistantes sont enfouies près du sol.
* Un skieur peut favoriser un départ superficiel de neige humide, dans une pente raide ayant bien chauffé au soleil.

Départs spontanés : * Quelques avalanches de fond à toute heure du jour ou de la nuit, essentiellement au-dessus de 2000 m, de taille moyenne en général (taille 2). Départ plutôt dans les pentes ouest, sud à est avec terrain favorable (pentes herbeuses, dalles rocheuses).
* Activité en neige humide selon la course du soleil, mais restant limitée. Avalanches généralement petites (taille 1).

Qualité de la neige

L'enneigement est proche des normales en ubacs, mais déficitaire en adrets. Les limites d'enneigement remontent dans les pentes bien exposées au soleil.
Hauteurs de neige observées : 150 cm en versant nord du col Izoard à 2300 m, 76 cm à Cervières à 1610 m, 89 cm à le Nivôse du Col Agnel à 2630 m, 50 cm à Ristolas à 1670 m.

Limite d'enneigement skiable : 1400 m en ubacs, mais au mieux 1900/2000 m en adrets.

État de la neige de surface : en début de journée, manteau neigeux croûté dans les adrets, et en ubacs sous 2000/2200 m. Humidification superficielle en cours de journée au soleil.
Dans les pentes nord-ouest à nord-est au-dessus de 2200 m environ, neige encore froide, travaillée par les épisodes de vent passés, ou en vieille poudreuse meuble dans les secteurs abrités.

Aperçu météo pour le dimanche 08 mars

	nuit	matin	après-midi	soir
Voilé à nuageux. Lombarde sensible.				
Pluie-Neige				
Iso 0 °C	2 100 m	2 100 m	2 300 m	2 100 m
Vent 2000 m	15 km/h	20 km/h	20 km/h	10 km/h
Vent 3000 m	20 km/h	25 km/h	25 km/h	20 km/h

Épaisseur de neige hors-piste

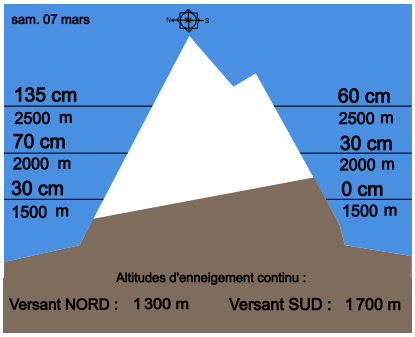

Précipitations à 1800 m

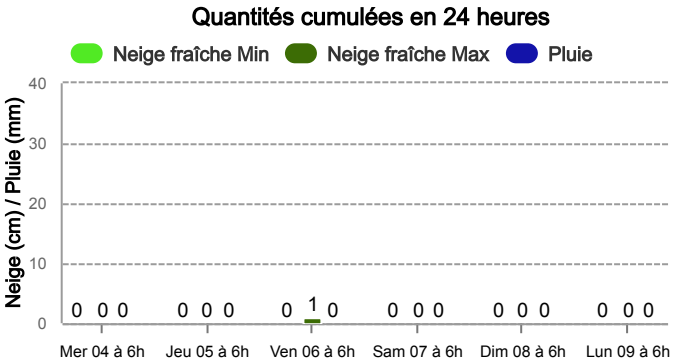

Tendance du lundi 09 mars

Indice de risque limité

Situation nivologique similaire. Maintien d'un risque limité, avec les mêmes problématiques.

Pour consulter la vigilance en cours, veuillez vous rendre sur le site https://vigilance.meteofrance.fr/fr

Météo-France - 73 avenue de Paris, 94165 Saint-Mandé cedex - Contact : contact@meteo.fr

Rédigé par Météo-France avec la contribution des observateurs du réseau nivo-météorologiques. Partenariat : ANMSM (Maires de Stations de Montagne), DSF (Domaines Skiables de France), ADSP (Directeurs de Pistes et de la Sécurité des Stations de Sports d'Hiver) et autres acteurs de la montagne.

Bulletin neige & avalanches par téléphone au
0 892 68 10 20 Service 0,35 € / min + prix appel

RÉPUBLIQUE FRANÇAISE
Liberté Égalité Fraternité

METEO FRANCE
À VOS CÔTÉS, DANS UN CLIMAT QUI CHANGE

Bulletin d'estimation du risque d'avalanche
(valable en dehors des pistes balisées et ouvertes)

MASSIF : Queyras

Rédigé le samedi 7 mars 2026 à 16h

Conditions nivo-météo des 7 derniers jours

	dim. 01/03				lun. 02/03				mar. 03/03				mer. 04/03				jeu. 05/03				ven. 06/03				sam. 07/03			
	03h	09h	15h	21h	03h	09h	15h	21h	03h	09h	15h	21h	03h	09h	15h	21h	03h	09h	15h	21h	03h	09h	15h	21h	03h	09h	15h	21h
Météo																												
Vent (km/h)	15	15	20	15	15	15	15	15	15	10	10	10	10	10	10	5	15	20	30	40	40	30	30	25	30	30	30	25
à 3000m																												
Vent (km/h)	5	10	15	10	5	10	15	10	10	5	10	5	5	5	10	5	10	15	20	15	20	20	25	20	20	20	20	15
à 2000m																												

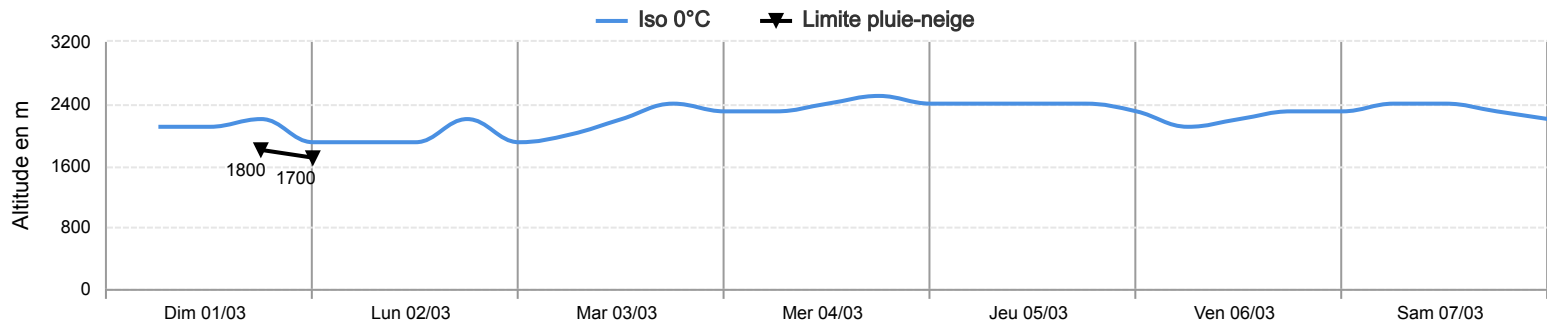

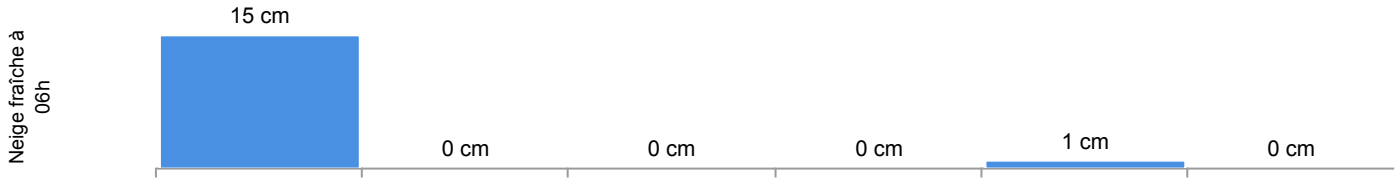

Risque d'avalanche	dim. 01/03	lun. 02/03	mar. 03/03	mer. 04/03	jeu. 05/03	ven. 06/03	sam. 07/03
	3	3	2	2	2	2	2

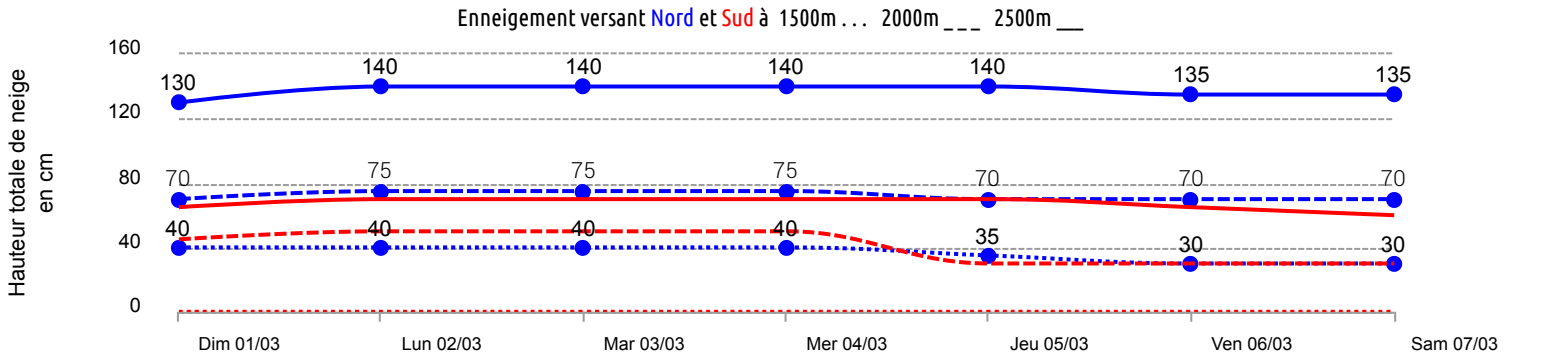

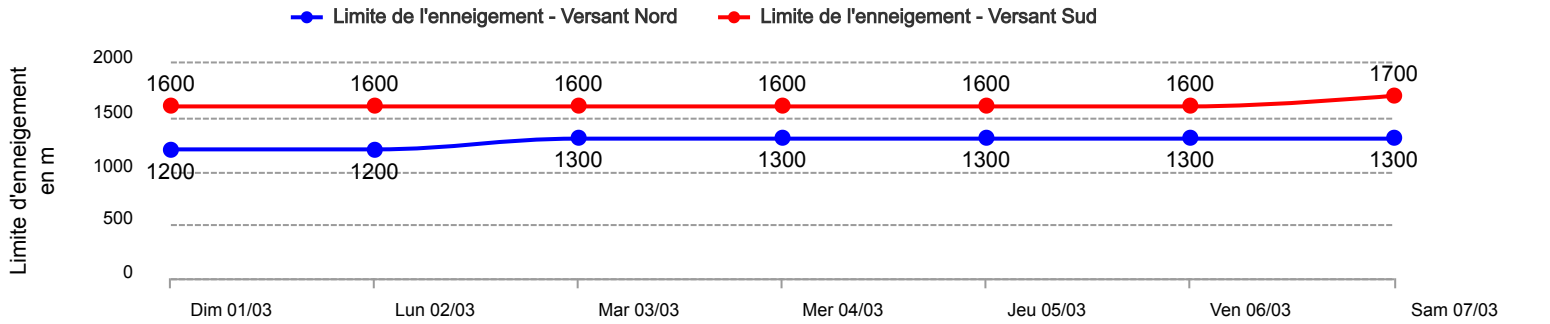

Pour consulter la vigilance en cours, veuillez vous rendre sur le site https://vigilance.meteofrance.fr/fr

Météo-France - 73 avenue de Paris, 94165 Saint-Mandé cedex - Contact : contact@meteo.fr

Bulletin neige & avalanches par téléphone au **0 892 68 10 20** Service 0,35 € / min + prix appel

Rédigé par Météo-France avec la contribution des observateurs du réseau nivo-météorologiques. Partenariat : ANMSM (Maires de Stations de Montagne), DSF (Domaines Skiables de France), ADSP (Directeurs de Pistes et de la Sécurité des Stations de Sports d'Hiver) et autres acteurs de la montagne.