Bulletin d'estimation du risque d'avalanche

(valable en dehors des pistes balisées et ouvertes)

MASSIF : Vanoise

Rédigé le samedi 7 mars 2026 à 16h

Estimation des risques pour le : DIMANCHE 08 MARS

MANTEAU PRINTANIER : STABLE LE MATIN, HUMIDIFICATION MARQUÉE ENSUITE FACILITANT UN DÉPART

2

1 → 2

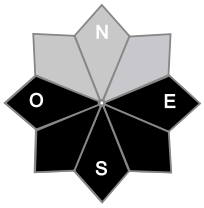

Indice de risque faible évoluant en limité.

Départs spontanés : avalanches humides avec le réchauffement.

Déclenchements provoqués : rares plaques sur couches fragiles persistantes.

Indices de risque : 5 très fort - 4 fort - 3 marqué - 2 limité - 1 faible -- En noir : les pentes les plus dangereuses

Stabilité du manteau neigeux

Situation avalancheuse typique : neige humide — couche fragile persistante

Déclenchements provoqués : **des couches fragiles persistantes** (grains anguleux) **sont enfouies de manière généralisée dans le manteau** (en tous versants, même en Sud de haute altitude). Leur sollicitation est très peu probable la majorité du temps mais devient possible :

- en **E à S à W, après plusieurs heures de soleil**, lorsque l'enfoncement dans la neige humide devient important, facilitant la sollicitation d'une couche fragile enfouie. Taille 2 (moyenne), plus rarement 3 (grande).
- en **NW/N/NE, au-dessus de 2000 m** (neige froide en surface), dans les zones moins enneigées (abords de crête, croupes dégarnis) où **une rare petite plaque** peut subsister. Taille 1 à 2 (petite à moyenne).

Départs spontanés : **Rare avalanche de neige humide** dans les **pentes ayant chauffées plusieurs heures au soleil**. Avalanche de taille 1 à 2 (petite à moyenne), exceptionnellement 3 (grande) avec cassure linéaire si l'humidification atteint une vielle couche fragile de grains anguleux (plutôt en E/O mais aussi en S de haute altitude).

Qualité de la neige

Enneigement : en général légèrement excédentaire pour la saison, mais en train de devenir déficitaire en basse montagne et en versant Sud.

Limite skiable : encore skiable dès 1100/1200 m dans les prairies orientées nord, plutôt 1500/1600 m en sud pas trop raide.

Qualité de la neige :

- Sud/Est/Ouest : conditions de printemps avec un bon regel le matin, ensuite la neige "décaille" rapidement en suivant la course du soleil, offrant du bon ski lorsque l'horaire est adapté à l'orientation.
- Nord suffisamment haut ou pentu (à partir de 2000/2200 m) : on peut trouver de la vieille poudre (grain à face plane) agréable à skier, parfois densifiée voire localement cartonnée par le vent.

Aperçu météo pour le dimanche 08 mars

nuit	matin	après-midi	soir

Grand beau et douceur. Rares nuages. Brume de poussière désertique s'attenuant progressivement.

Pluie-Neige				
Iso 0 °C	2 200 m	2 400 m	2 500 m	2 200 m
Vent 2500 m	↖ 10 km/h	↖ 10 km/h	↑ 10 km/h	↖ 10 km/h
Vent 3500 m	↖ 25 km/h	↖ 20 km/h	↖ 15 km/h	↑ 20 km/h

Épaisseur de neige hors-piste

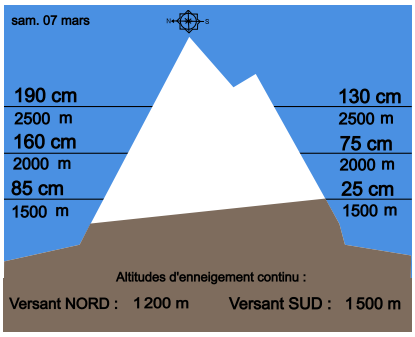

Précipitations à 1800 m

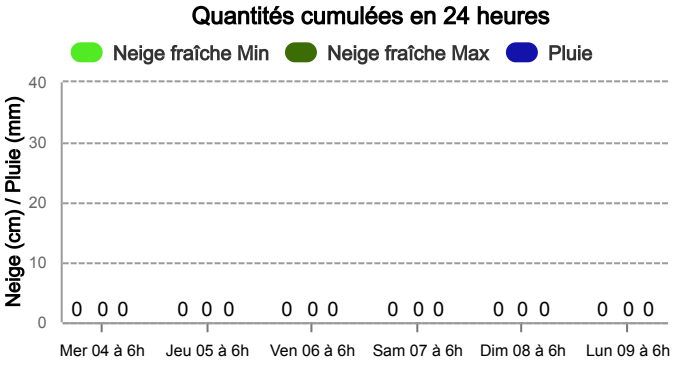

Tendance du lundi 09 mars

2

Indice de risque limité

Risque stationnaire. Poursuite des conditions printanières.

Pour consulter la vigilance en cours, veuillez vous rendre sur le site https://vigilance.meteofrance.fr/fr

Météo-France - 73 avenue de Paris, 94165 Saint-Mandé cedex - Contact : contact@meteo.fr

Rédigé par Météo-France avec la contribution des observateurs du réseau nivo-météorologiques. Partenariat : ANMSM (Maires de Stations de Montagne), DSF (Domaines Skiables de France), ADSP (Directeurs de Pistes et de la Sécurité des Stations de Sports d'Hiver) et autres acteurs de la montagne.

Bulletin neige & avalanches par téléphone au **0 892 68 10 20** Service 0,35 € / min + prix appel

RÉPUBLIQUE FRANÇAISE
Liberté Égalité Fraternité

METEO FRANCE
À VOS CÔTÉS, DANS UN CLIMAT QUI CHANGE

Bulletin d'estimation du risque d'avalanche
(valable en dehors des pistes balisées et ouvertes)

MASSIF : Vanoise

Rédigé le samedi 7 mars 2026 à 16h

Conditions nivo-météo des 7 derniers jours

	dim. 01/03				lun. 02/03				mar. 03/03				mer. 04/03				jeu. 05/03				ven. 06/03				sam. 07/03			
	03h	09h	15h	21h	03h	09h	15h	21h	03h	09h	15h	21h	03h	09h	15h	21h	03h	09h	15h	21h	03h	09h	15h	21h	03h	09h	15h	21h
Météo																												
Vent (km/h)	25	20	20	15	15	20	25	25	20	15	10	10	10	10	15	10	15	20	20	30	40	50	40	30	15	20	20	25
à 3500m																												
Vent (km/h)	5	10	10	10	10	15	20	20	15	10	5	5	5	5	5	5	10	15	20	30	40	40	30	20	10	15	15	20
à 2500m																												

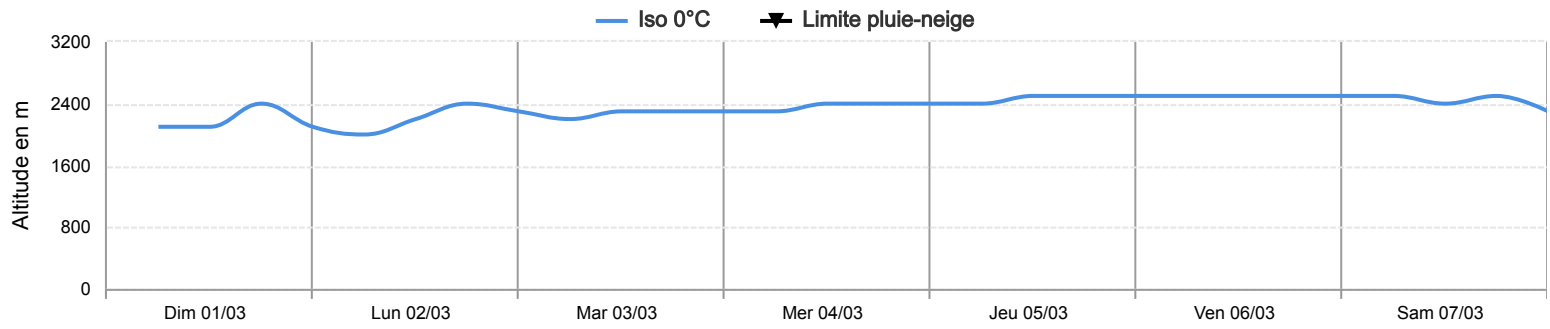

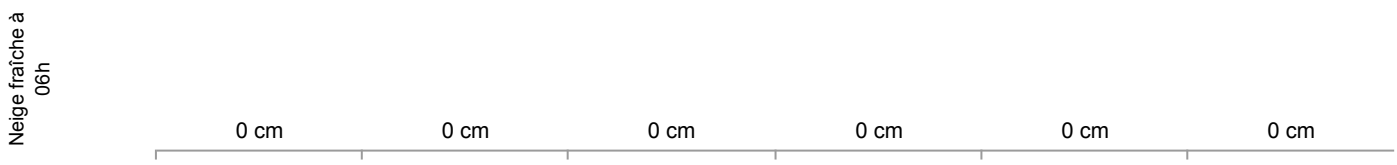

Risque d'avalanche	dim. 01/03	lun. 02/03	mar. 03/03	mer. 04/03	jeu. 05/03	ven. 06/03	sam. 07/03
	2	2	2	2	2	2	2

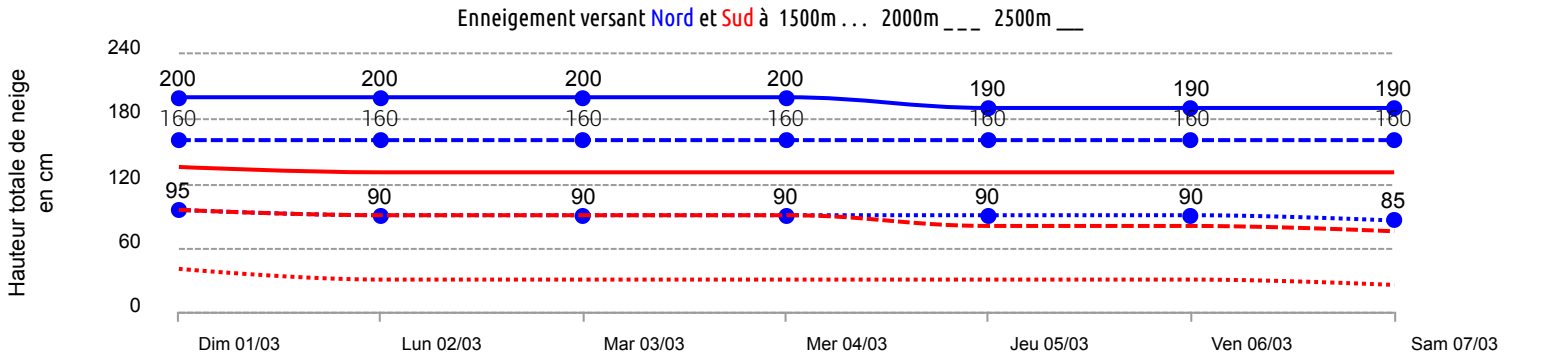

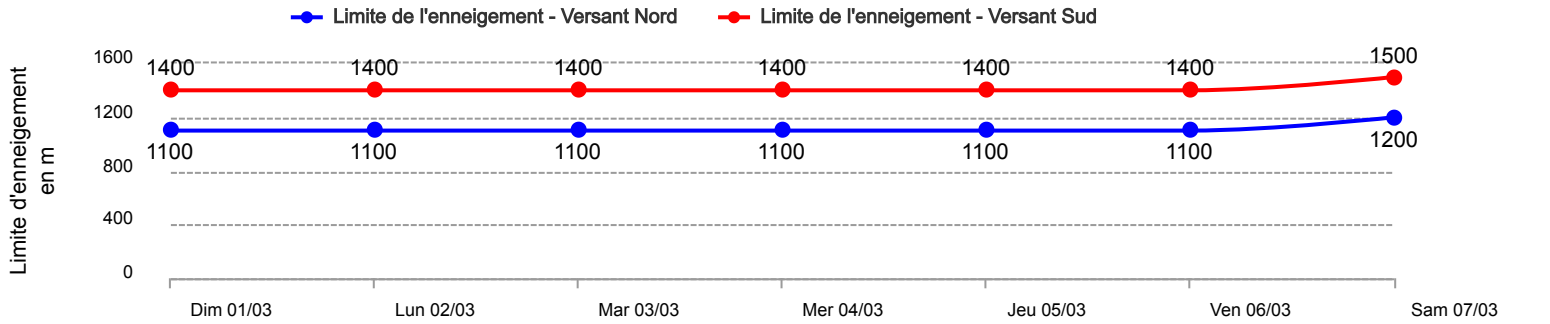

Pour consulter la vigilance en cours, veuillez vous rendre sur le site https://vigilance.meteofrance.fr/fr

Météo-France - 73 avenue de Paris, 94165 Saint-Mandé cedex - Contact : contact@meteo.fr

Rédigé par Météo-France avec la contribution des observateurs du réseau nivo-météorologiques. Partenariat : ANMSM (Maires de Stations de Montagne), DSF (Domaines Skiables de France), ADSP (Directeurs de Pistes et de la Sécurité des Stations de Sports d'Hiver) et autres acteurs de la montagne.

Bulletin neige & avalanches par téléphone au

0 892 68 10 20 Service 0,35 € / min + prix appel