Bulletin d'estimation du risque d'avalanche

(valable en dehors des pistes balisées et ouvertes)

MASSIF : Cinto Rotondo

Rédigé le samedi 7 mars 2026 à 17h

Estimation des risques pour le : DIMANCHE 08 MARS

DÉPARTS POSSIBLES EN NEIGE HUMIDE, QUELQUES PETITES INSTABILITÉS EN NEIGE FRAÎCHE EN ALTITUDE

1

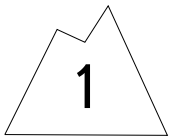

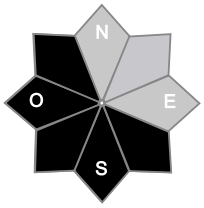

Indice de risque faible.

Départs spontanés : Sous les précipitations, départs en neige fraîche au-dessus de 2000m, ou en neige humide en dessous de 2000m

Déclenchements provoqués : Présence de petites plaques à vent en altitude, risque de départs ponctuels sous les skis en neige humide

Indices de risque : 5 très fort - 4 fort - 3 marqué - 2 limité - 1 faible -- En noir : les pentes les plus dangereuses

Stabilité du manteau neigeux

Situation avalancheuse typique : neige humide

Départs spontanés : En dessous de 2000 m, sous les précipitations de ce samedi soir puis dimanche après-midi, des coulées de neige humide (taille 1) se produisent, rarement des avalanches de taille moyenne (taille 2). Par ailleurs, une avalanche de fond de taille moyenne (taille 2), emportant la totalité du manteau neigeux sur les dalles rocheuses, reste possible. Au-dessus de 2000 m, quelques coulées de neige fraîche sont possibles au fil des chutes de neige, dans les pentes raides. La sous-couche étant bien dense ou dure, seule cette neige récente (5 à 10 cm au plus) est mobilisable (taille 1).

Déclenchements provoqués : Les récentes petites plaques à vent formées dans les pentes orientées Ouest à Nord-Ouest, au-dessus de 2000 m, plus présentes sur le massif du Rotondo, sont recouvertes par les nouvelles chutes de neige. Déclenchement possible au passage d'un skieur, pouvant engendrer des coulées ou petites avalanches ne mobilisant pas beaucoup de neige (taille 1). Départs ponctuels sous les skis ou raquettes en neige humide, notamment en versants Sud (taille 1 à 2 suivant l'altitude).

Autres : Nombreuses surfaces glacées.

Qualité de la neige

Qualification de l'enneigement : L'enneigement est excellent pour la saison au-dessus de 1600 m. Sur la Maniccia, à 2400 m d'altitude dans le massif du Rotondo, on mesure 2m82 de hauteur totale de neige.

Limite d'enneigement skiable : autour de 1500 m.

État de la neige : Sous l'effet de plus d'une semaine de soleil et de douceur, le manteau neigeux s'est considérablement tassé et il est bien consolidé malgré un regel nocturne faible et ne concernant souvent que les pentes Nord et les hauts sommets. L'humidification est fortement accélérée sous 2000m avec les pluies. La neige y devient rapidement lourde et humide. En Nord, l'humidification est plus lente, elle ne se produit qu'en dessous de 2000m. Au-dessus de 2000 m, la neige reste dure ou cartonnée parfois avec quelques cm de neige récente. Le refroidissement récent fait apparaitre des surfaces glacées. Nombreuses zones de neige colorée avec les dernières remontées de sable. À noter la présence de corniches parfois volumineuses.

Aperçu météo pour le dimanche 08 mars

	nuit	matin	après-midi	soir
Risque d'averses ce samedi soir puis à nouveau dimanche après-midi.				
Pluie-Neige			1 900 m	
Iso 0 °C	2 100 m	2 200 m	2 200 m	2 300 m
Vent 1500 m	10 km/h	0 km/h	5 km/h	0 km/h
Vent 3000 m	15 km/h	10 km/h	15 km/h	10 km/h

Épaisseur de neige hors-piste

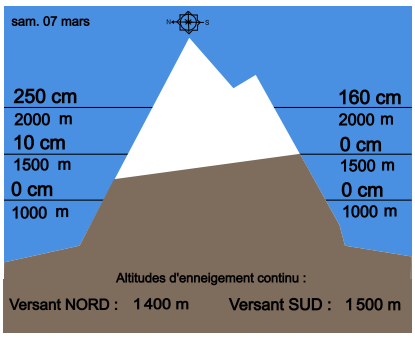

Précipitations à 1800 m

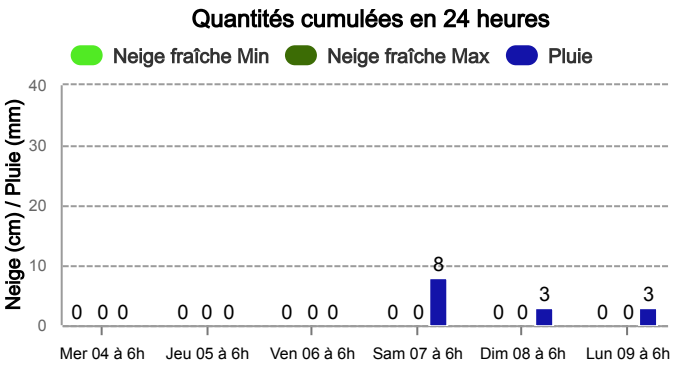

Tendance du lundi 09 mars

1

Indice de risque faible

Peu de précipitations et peu de départs à attendre.

Pour consulter la vigilance en cours, veuillez vous rendre sur le site https://vigilance.meteofrance.fr/fr

Météo-France - 73 avenue de Paris, 94165 Saint-Mandé cedex - Contact : contact@meteo.fr

Rédigé par Météo-France avec la contribution des observateurs du réseau nivo-météorologiques. Partenariat : ANMSM (Maires de Stations de Montagne), DSF (Domaines Skiables de France), ADSP (Directeurs de Pistes et de la Sécurité des Stations de Sports d'Hiver) et autres acteurs de la montagne.

Bulletin neige & avalanches par téléphone au 0 892 68 10 20 Service 0,35 € / min + prix appel

RÉPUBLIQUE FRANÇAISE
Liberté Égalité Fraternité

METEO FRANCE
À VOS CÔTÉS, DANS UN CLIMAT QUI CHANGE

Bulletin d'estimation du risque d'avalanche

(valable en dehors des pistes balisées et ouvertes)

MASSIF : Cinto Rotondo

Rédigé le samedi 7 mars 2026 à 17h

Conditions nivo-météo des 7 derniers jours

	dim. 01/03				lun. 02/03				mar. 03/03				mer. 04/03				jeu. 05/03				ven. 06/03				sam. 07/03			
	03h	09h	15h	21h	03h	09h	15h	21h	03h	09h	15h	21h	03h	09h	15h	21h	03h	09h	15h	21h	03h	09h	15h	21h	03h	09h	15h	21h
Météo																												
Vent (km/h)	10	10	10	10	15	25	25	15	15	10	10	10	10	10	10	5	10	15	15	30	45	60	50	40	30	30	15	15
à 3000m																												
Vent (km/h)	5	5	10	5	10	15	20	10	10	15	20	15	10	10	15	10	10	20	25	20	30	40	35	25	20	20	10	10
à 1500m																												

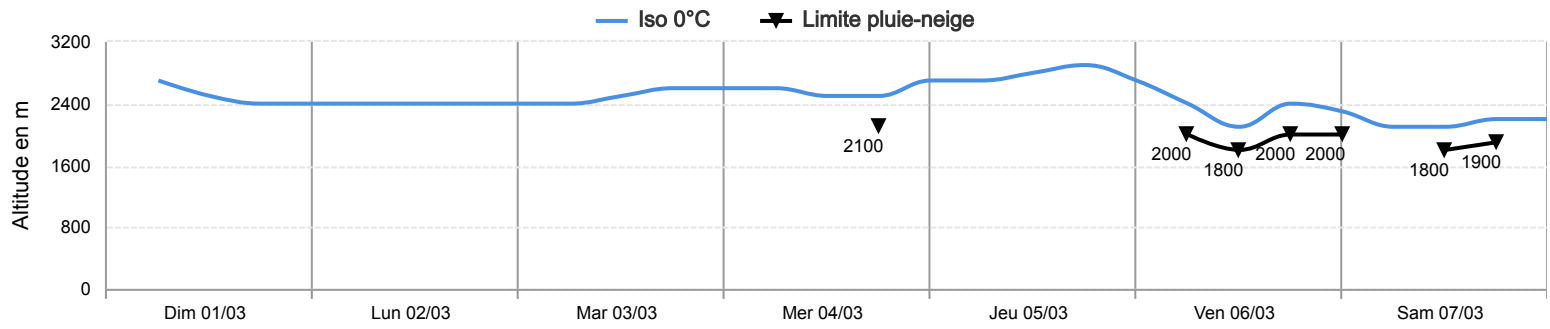

Neige fraîche à 06h

0 cm	0 cm	0 cm	0 cm	0 cm	0 cm

Risque d'avalanche	dim. 01/03	lun. 02/03	mar. 03/03	mer. 04/03	jeu. 05/03	ven. 06/03	sam. 07/03
	2	2	2	2	2	2	2

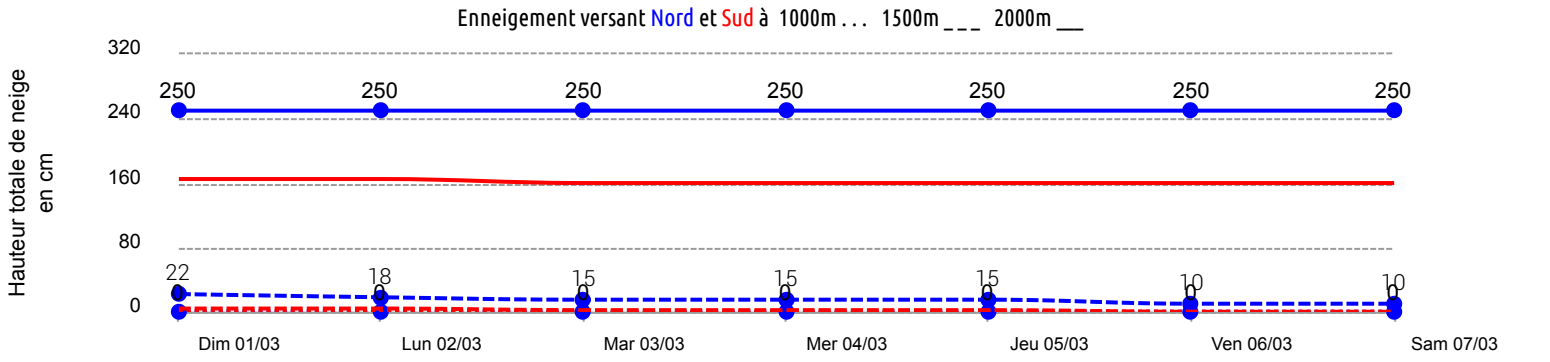

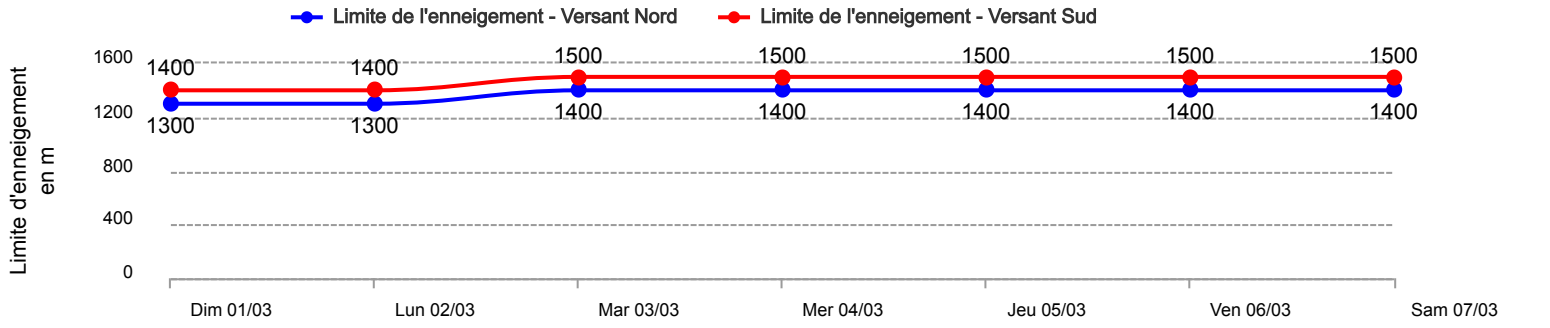

Pour consulter la vigilance en cours, veuillez vous rendre sur le site https://vigilance.meteofrance.fr/fr

Météo-France - 73 avenue de Paris, 94165 Saint-Mandé cedex - Contact : contact@meteo.fr

Rédigé par Météo-France avec la contribution des observateurs du réseau nivo-météorologiques. Partenariat : ANMSM (Maires de Stations de Montagne), DSF (Domaines Skiables de France), ADSP (Directeurs de Pistes et de la Sécurité des Stations de Sports d'Hiver) et autres acteurs de la montagne.

Bulletin neige & avalanches par téléphone au

0 892 68 10 20 Service 0,35 € / min + prix appel