GOBIERNO DE ESPAÑA
VICEPRESIDENCIA TERCERA DEL GOBIERNO
MINISTERIO PARA LA TRANSICIÓN ECOLÓGICA Y EL RETO DEMOGRÁFICO

Boletín de información nivológica y de peligro de aludes

Pirineo Navarro y Aragonés

aemet Agencia Estatal de Meteorología

domingo, 8 de marzo de 2026

Pronóstico hasta las 24 horas del lunes, día 9 de marzo

(Válido fuera de pistas de esquí balizadas y abiertas)

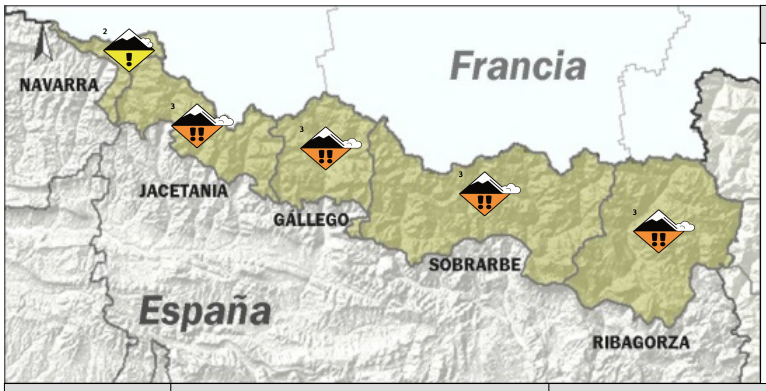

Problemas de aludes

- Nieve reciente
- Placas de viento
- Nieve húmeda

Macizo	Peligro	Problemas de aludes, cota, orientación, tamaño	Innivación observada (m)
Navarra	2 / 2 — Limitado	Nieve reciente: 2100; N O E S; 2 Nieve húmeda: 2100; N O E S; 2	2026-03-08 N S Cotas bajas
Jacetania	3 / 3 2200 / 2 — Notable	Nieve reciente: 2100; N O E S; 2 Placas de viento: 2400; N O E S; 2	2026-03-08 N S Cotas bajas
Gállego	3 / 3 2200 / 2 — Notable	Nieve reciente: 2100; N O E S; 2 Placas de viento: 2400; N O E S; 2	2026-03-08 N S Cotas bajas

AEMET. Se autoriza la reproducción de su contenido citando la fuente.

Boletín de información nivológica y de peligro de aludes

Pirineo Navarro y Aragonés

Sobrarbe	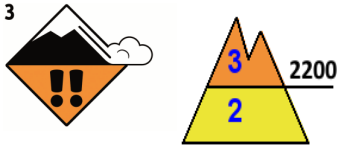 **Notable**	**Nieve reciente** 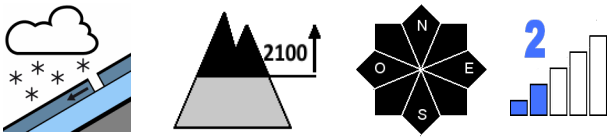 **Placas de viento**	2026-03-08	Cota más baja caras N
Ribagorza	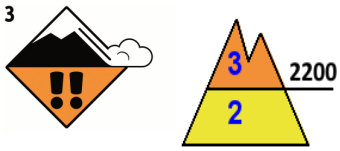 **Notable**	**Nieve reciente** 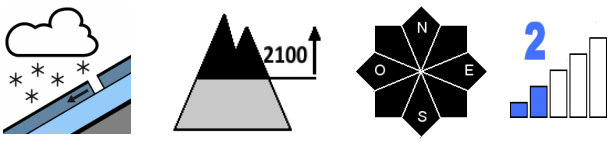 **Placas de viento**	2026-03-08	Cota más baja caras N

Estado del manto y observaciones recientes

Durante las últimas 24 horas se han registrado precipitaciones, más cuantiosas en el Pirineo navarro y Jacetania, depositando cantidades de entre 2 y 15 cm de nieve nueva, lo que ha ocasionado que el manto vuelva a presentar continuidad desde cotas bajas en algunas áreas, sobre todo de los macizos occidentales. En medianías la nieve es abundante, con espesores que se van incrementando conforme ascendemos, de tal manera que siguen superándose los 120 a 200 cm por encima de 2.100 metros, cantidades que pueden verse incrementadas notablemente en ventisqueros, hoyas y otras zonas propensas a la acumulación.

El manto está humedecido hasta su base en cotas medias y bajas. Por encima de unos 2.100 ó 2.200 metros la nieve se presenta generalmente más seca y venteada, y aún podemos encontrar en umbrías de la alta montaña estratos débiles ubicados a considerable profundidad, y que se encuentran, por lo general, inactivos. En capas superficiales se depositó algo de polvo sahariano que ha podido quedar enterrado por las últimas nevadas.

Evolución del manto y peligro de aludes para el lunes, día 9

Situación de nieve reciente, y placas de viento en la alta montaña.

Durante las próximas 24 horas se prevén nevadas en la cordillera, que irán depositando nuevos espesores de nieve reciente sobre los ya acumulados en jornadas previas, principalmente en cotas altas, donde es probable que puedan darse algunas purgas espontáneas en pendientes con suficiente inclinación y sin orientación preferente, siendo, por lo general, de tamaño pequeño o mediano, sin descartarse tampoco alguna salida local de nieve húmeda en medianías y zonas bajas.

AEMET. Se autoriza la reproducción de su contenido citando la fuente.

En la alta montaña se formarán nuevas placas de viento en orientaciones oeste y norte, principalmente en las cercanías de crestas y collados, que vendrán a sumarse a las que ya existen en diferentes orientaciones y que permanecen aún activas. Estas estructuras podrán fracturarse ante sobrecargas débiles, como es el paso de un esquiador, dando lugar a aludes de dimensiones medianas, tamaño más que suficiente para enterrar a una persona, por lo que se recomienda tomar precauciones si se va a transitar por la zona.

Predicción meteorológica para el lunes, día 9

Predominarán los cielos nubosos o muy nubosos, aunque podrán abrirse grandes claros durante algunos periodos. Se esperan precipitaciones ocasionales, débiles o localmente moderadas, más probables de madrugada y durante la segunda mitad del día. Cota de nieve: 1.400 a 1.600 metros. Temperaturas con pocos cambios en el Pirineo aragonés, subiendo las máximas algún grado en el sector navarro. Heladas débiles, moderadas y persistentes en cotas altas. Vientos flojos de componentes este y sur, moderados durante algunos intervalos.

Datos en la atmósfera libre:

Altitud de la isoterma de 0 ºC: 1.900 m
Altitud de la isoterma de -10 ºC: 3.400 m

Viento a 1500 m: S 10 km/h
Viento a 3000 m: S 10 km/h

Evolución para el martes día 10

Nivel de peligro sin grandes cambios.

(Información elaborada a partir de los datos recibidos de los refugios de Linza, Lizara, Panticosa, Góriz, Pineta, Estós, Angel Orús, Cap de Llauset y Belagua, de las estaciones de esquí de Formigal y Panticosa (lagos), de la estación de esquí de fondo de Llanos del Hospital y de Ordesa Pradera)

Escala europea de peligro de aludes

Débil Limitado Notable Fuerte Muy Fuerte

Problemas de aludes

Nieve reciente Placas de viento Capas débiles persistentes Nieve húmeda Deslizamientos basales Sin problema evidente

Nota1: Se recuerda que, siempre que haya nieve, la ausencia total de peligro no existe. Hay que tener presente que en circunstancias desfavorables, con aludes de tamaño 1 (alud pequeño o colada) y tamaño 2 (alud mediano), se pueden sufrir severos daños personales.

Nota2: Los BPA se elaboran en base a información meteorológica así como al estado del manto nivoso a través de sondeos puntuales. Se advierte a los usuarios de la variabilidad de esta información al extrapolarla a zonas extensas de montaña. Por ello, AEMET no se hace responsable de su uso para la toma de decisiones que conciernen a la seguridad personal, ni de los riesgos físicos o materiales de ellas derivadas.

AEMET. Se autoriza la reproducción de su contenido citando la fuente.