Montag 09.03.2026

Veröffentlicht am 08.03.2026 um 17:00

Vormittag

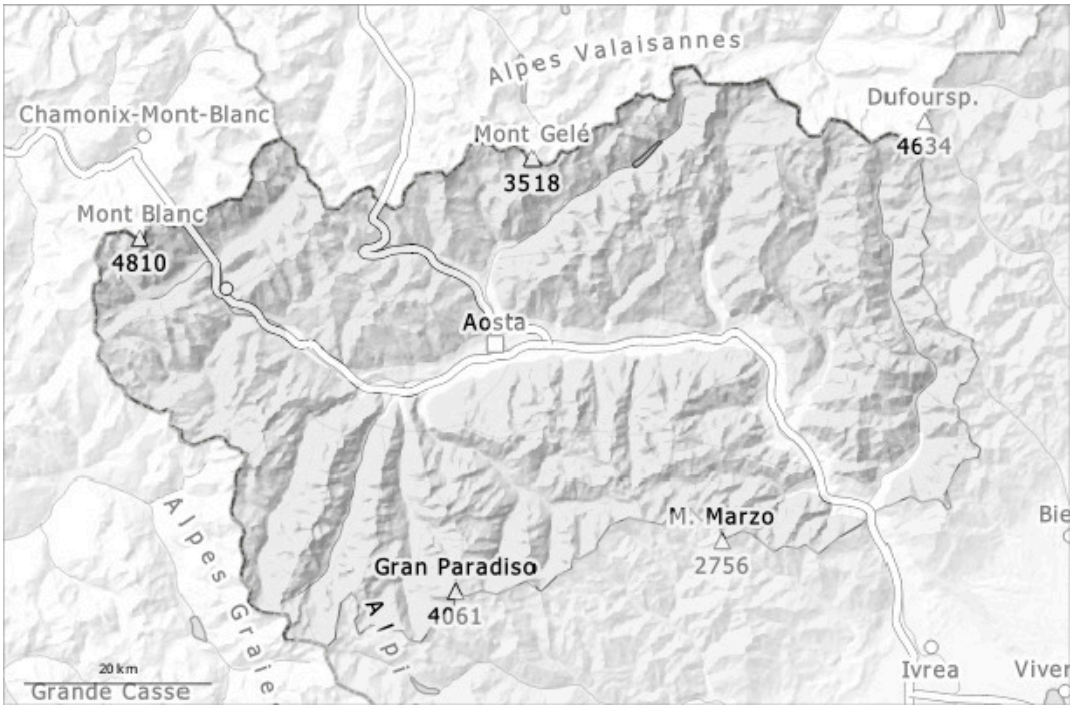

Nachmittag

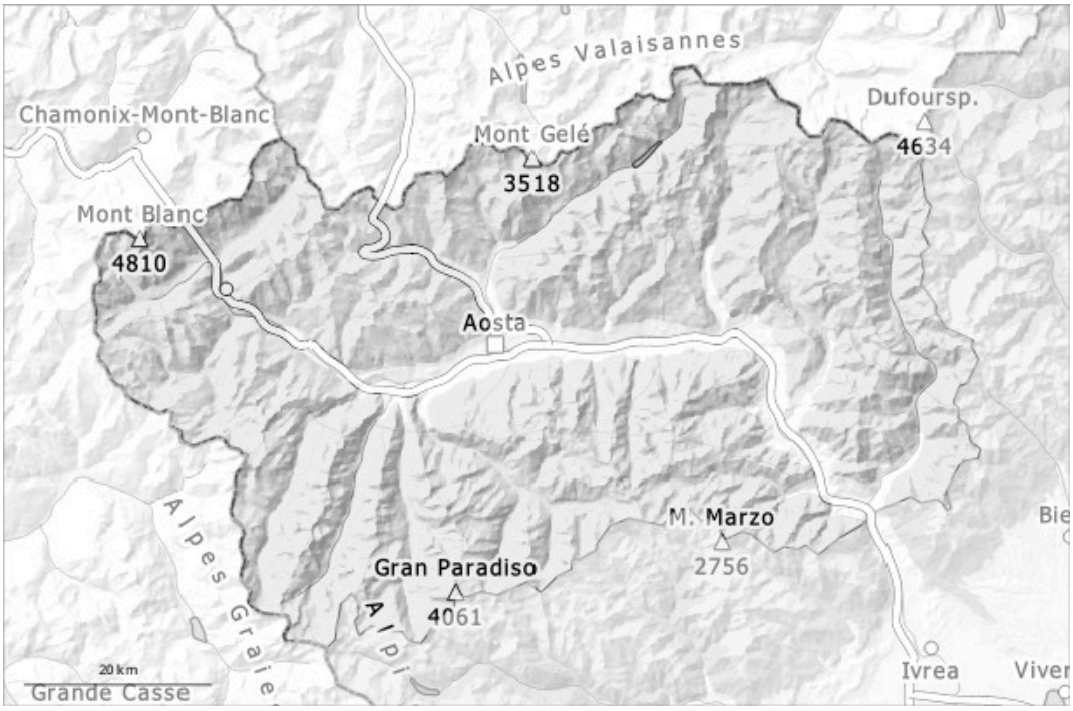

1	2	3	4	5
gering	mäßig	erheblich	groß	sehr groß

Gefahrenstufe 1 - Gering

AM:

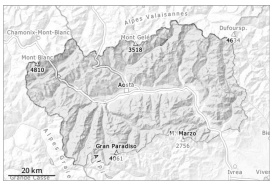

1

Tendenz: Lawinengefahr bleibt gleich
am Dienstag, den 10.03.2026

Altschnee

2400m

PM:

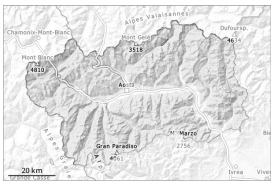

1

Tendenz: Lawinengefahr bleibt gleich
am Dienstag, den 10.03.2026

Nassschnee

2300m
2000m

Altschnee

2400m

Die Tourenverhältnisse sind mehrheitlich günstig. Leichter Anstieg der Gefahr mit der tageszeitlichen Erwärmung.

Die Schneeoberfläche gefriert tragfähig weicht später auf als am Vortag, v.a. unterhalb von rund 2300 m. Vor allem in mittleren Lagen sind im Tagesverlauf nur noch vereinzelt meist kleine feuchte und nasse Lawinen möglich. Dies vor allem mit großer Belastung, v.a. aus extrem steilen Einzugsgebieten.
Tiefer in der Schneedecke sind Schwachschichten vorhanden. Lawinen können sehr vereinzelt in tiefen Schichten ausgelöst werden und vereinzelt mittlere Größe erreichen. Diese Gefahrenstellen liegen vor allem an extrem steilen Schattenhängen oberhalb von rund 2400 m sowie an Übergängen von wenig zu viel Schnee.

Schneedecke

Gefahrenmuster gm.1: bodennahe schwachschicht | gm.10: frühjahrssituation

Die Wetterbedingungen begünstigten v.a. an Sonnenhängen eine Verfestigung der Schneedecke. Der obere Teil der Schneedecke ist weitgehend stabil, mit einer oft tragfähigen Schmelzharschkruste an der Oberfläche. Dort besteht im Steilgelände Absturzgefahr.
Besonders steile Schattenhänge hohe Lagen und Hochgebirge: Schnee, der oberflächlich sehr kompakt ist und durch die stürmischen Winde Ende Februar stabilisiert wurde, oder der aus facettierten Kristallen und stellenweise aus locker gepacktem Schnee besteht. In der Altschneedecke sind dort Schwachschichten vorhanden. Der obere Teil der Schneedecke ist aufbauend umgewandelt, mit einer Oberfläche aus kantig aufgebauten Kristallen.
In Kamm- und Passlagen sowie in hohen Lagen liegen je nach Windeinfluss sehr unterschiedliche

Schneehöhen.
In den letzten Tagen wurden kaum mehr Lawinen gemeldet.

Tendenz

Allmählicher Rückgang der Gefahr von feuchten und nassen Lawinen mit der Abkühlung. Gebietsweise wenig Neuschnee bis über 1500 m: Er wird oberhalb von rund 2000 m auf Oberflächenreif abgelagert.