# BUTLLETÍ DEL PERILL D'ALLAUS DEL PRINCIPAT D'ANDORRA

Servei meteorològic nacional
Principat d'Andorra

Elaborado el 08/03/2026 16:00
Proxima actualización 08/03/2026 a las 16h

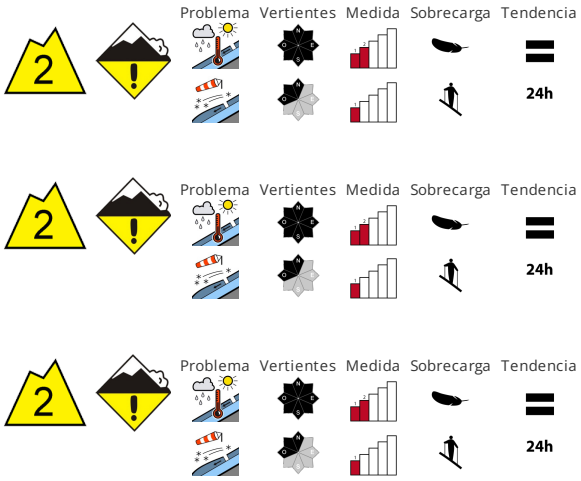


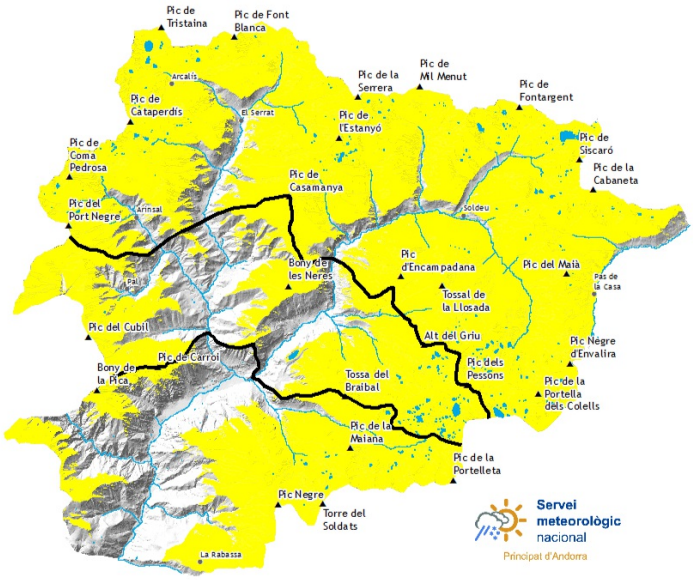


## CALIDAD DE LA NIEVE

Con la humidificación, por debajo de los 2000 m aproximadamente son probables avalanchas de nieve húmeda. Estos pueden desencadenarse de manera natural y alcanzar un tamaño mediano. Además son de esperar aludes de deslizamiento basal en cualquier momento. En cotas altas :. El viento del sudeste transportará la nieve reciente. Con la nieve reciente y el viento las placas de viento aumentarán de tamaño ligeramente. Estos lugares están parcialmente cubiertos de nieve reciente y resultan difíciles de reconocer.

## ESTABILIDAD DEL MANTO NIVOSO

Los espesores de nieve varían mucho por encima de los 2100 m aproximadamente por la influencia del viento. Evitar las zonas con grietas de deslizamiento basal. El tiempo será parcialmente soleado. En algunos sectores durante la tarde caerán localmente hasta 5 cm de nieve por encima de los 1800 m aproximadamente. El peligro de aludes permanecerá invariable. Debido a la superficie dura del manto de nieve hay el peligro de resbalar y caer en las laderas inclinadas.

## ESPESORES DEL MANTO NIVOSO FUERA DE PISTA

| Zona norte | | Espesor nieve | | |
|---|---|---|---|---|
| **Manto Nival** | | 1500m | 2000m | 2500m |
| N | 1600 m | 0 cm | 150 cm | 200 cm |
| S | 1900 m | 0 cm | 100 cm | 150 cm |

| zona centro | | Espesor nieve | | |
|---|---|---|---|---|
| **Manto Nival** | | 1500m | 2000m | 2500m |
| N | 1600 m | 0 cm | 150 cm | 200 cm |
| S | 1900 m | 0 cm | 100 cm | 150 cm |

| Zona sur | | Espesor nieve | | |
|---|---|---|---|---|
| **Manto Nival** | | 1500m | 2000m | 2500m |
| N | 1600 m | 0 cm | 120 cm | 150 cm |
| S | 1900 m | 0 cm | 60 cm | 100 cm |

Govern d'Andorra

EAWS EUROPEAN AVALANCHE WARNING SERVICES

Aquest butlletí ha estat elaborat seguint les normes i recomanacions de l'**European Avalanche Warning Services**, del qual el **Servei meteorològic Nacional** n'és membre

# BUTLLETÍ DEL PERILL D'ALLAUS DEL PRINCIPAT D'ANDORRA

Servei meteorològic nacional
Principat d'Andorra

## Información detallada por espacios naturales protegidos

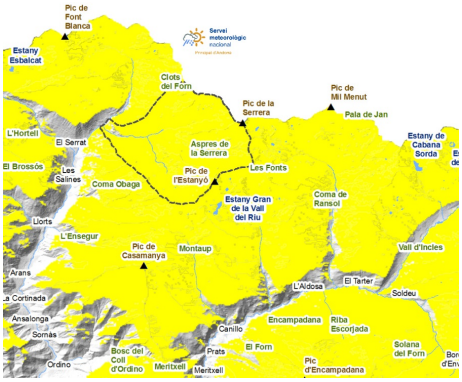


### SORTENY

Continuarán las débiles precipitaciones con una cota de nieve en torno a los 1800 m, que humidificarán el manto en todas las orientaciones, por debajo de esta cota; mientras que por encima se podrán formar débiles acumulaciones de unos 5 cm en este sector. En altura, el viento podrá transportar la poca nieve disponible y formar pequeñas acumulaciones irregulares. La poca nieve nueva, no cambiará las condiciones de estabilidad

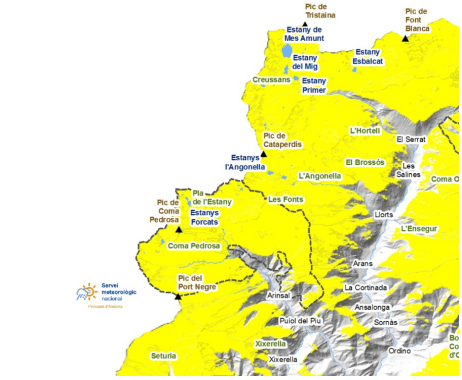


### COMAPEDROSA

El acceso desde Arinsal está quedando cada vez con menos nieve, y la poca lluvia prevista aún retirará más la línea de nieve continua. En las partes altas del Parque, se podrán realizar numerosas excursiones, siempre manteniendo una elección cuidadosa del itinerario. Deberemos vigilar a no resbalar debido a la corteza de rehielo en las laderas sur o en cotas bajas, pero también en las laderas\r\n umbrías, donde la nieve polvo esconde una costra ventolera dura

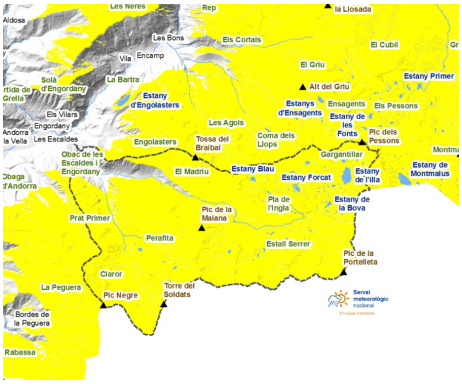


### MADRIU-PERAFITA-CLAROR

El manto es en general delgado e irregular, con mejor continuidad de nieve en las vertientes norte y umbrías. Fue el sector más afectado por las precipitaciones, aunque en algunos lugares elevados el viento dejó la nieve vieja, dura, al descubierto.

Govern d'Andorra

EAWS
EUROPEAN AVALANCHE WARNING SERVICES

Aquest butlletí ha estat elaborat seguint les normes i recomanacions de l'**European Avalanche Warning Services**, del qual el **Servei meteorològic Nacional** n'és membre

# BUTLLETÍ DEL PERILL D'ALLAUS DEL PRINCIPAT D'ANDORRA

Servei meteorològic nacional
Principat d'Andorra

## Espesores de nieve nueva de los últimos días (de las ultimas 24h mesurado a las 06:00h UTC)

| | 04/03/2026 | 05/03/2026 | 06/03/2026 | 07/03/2026 |
|---|---|---|---|---|
| **FEDA (Central)** | 0 cm | 0 cm | 0 cm | 0 cm |
| **Engolasters - FEDA** | 0 cm | 0 cm | 0 cm | 0 cm |
| **Bony de les Neres** | 0 cm | 0 cm | 2 cm | 0 cm |
| **Sorteny** | 3 cm | 10 cm | 5 cm | 2 cm |
| **Les Fonts d'Arinsal** | 0 cm | 10 cm | 5 cm | 0 cm |
| **Perafita** | 3 cm | 26 cm | 3 cm | 0 cm |
| **Tossa Espiolets** | 0 cm | 17 cm | 5 cm | 0 cm |
| **Grau Roig - FEDA** | 0 cm | 3 cm | 5 cm | 0 cm |
| **Fontverd** | 0 cm | 0 cm | 1 cm | 0 cm |
| **Ransol - FEDA** | 0 cm | 0 cm | 0 cm | 0 cm |
| **Setúria** | 0 cm | 0 cm | 0 cm | 0 cm |
| **Caborreu** | 0 cm | 17 cm | 12 cm | 0 cm |
| **La Solana** | 0 cm | 10 cm | 4 cm | 1 cm |
| **Coll Pa** | 0 cm | 9 cm | 9 cm | 0 cm |
| **Envalira Antenes** | 0 cm | 1 cm | 13 cm | 0 cm |
| **Vall del Riu FEDA** | 0 cm | 9 cm | 5 cm | 3 cm |