BUTLLETÍ DEL PERILL D'ALLAUS DEL PRINCIPAT D'ANDORRA

Préparé le 08/03/2026 16:00
Prochaine mise à jour le 08/03/2026 à 16h

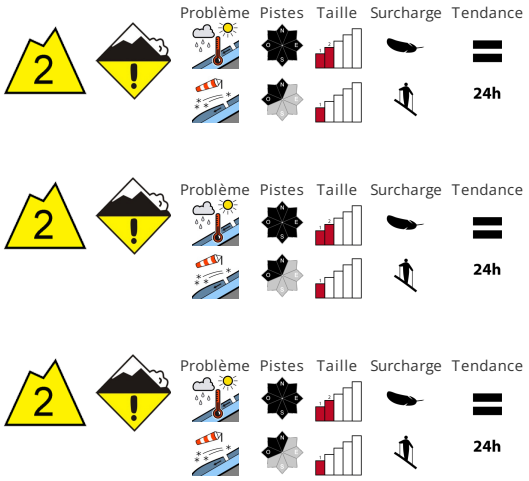

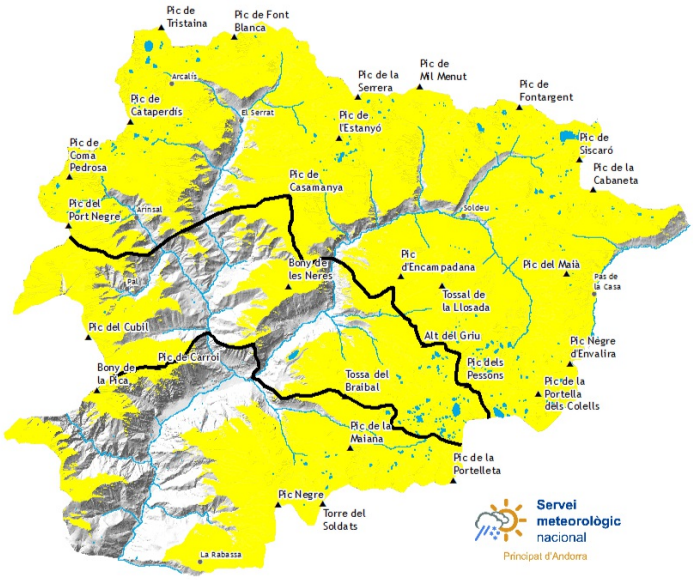

STABILITÉ DU MANTEAU NEIGEUX

Avec l'humidification des avalanches humides sont à attendre en dessous d'environ 2000 m. Explication: celles-ci ne peut signifier que celles-ci avalanches peuvent se déclencher spontanément et atteindre une taille moyenne.. En outre, des avalanches de glissement sont à attendre à tout moment.. À haute altitude (-):. Le vent du sud-est transporte la neige fraîche.. Les accumulations de neige soufflée se développent encore un peu avec la neige fraîche et le vent. Ces endroits sont en partie couverts de neige fraîche, et difficilement identifiables..

QUALITÈ DE LA NEIGE

On trouve suivant l'influence du vent des hauteurs de neiges très différentes au-dessus d'environ 2100 m. Les zones présentant des fissures de glissement doivent être évitées.. Il fait un temps partiellement ensoleillé. L'après-midi il tombera dans certaines régions au-dessus d'environ 1800 m localement jusqu'à 5 cm de neige. Le danger d'avalanches subsiste. Sur la surface de neige dure il existe en terrain raide un risque de chute..

EPAISSEUR DE NEIGE HORS PISTE

Zone nord		Epaisseur de neige		
Nival manteau		1500m	2000m	2500m
N	1600 m	0 cm	150 cm	200 cm
S	1900 m	0 cm	100 cm	150 cm

Zone centre		Epaisseur de neige		
Nival manteau		1500m	2000m	2500m
N	1600 m	0 cm	150 cm	200 cm
S	1900 m	0 cm	100 cm	150 cm

Zone sud		Epaisseur de neige		
Nival manteau		1500m	2000m	2500m
N	1600 m	0 cm	120 cm	150 cm
S	1900 m	0 cm	60 cm	100 cm

Govern d'Andorra

EAWS EUROPEAN AVALANCHE WARNING SERVICES

Aquest butlletí ha estat elaborat seguint les normes i recomanacions de l'**European Avalanche Warning Services**, del qual el **Servei meteorològic Nacional** n'és membre

BUTLLETÍ DEL PERILL D'ALLAUS DEL PRINCIPAT D'ANDORRA

Servei meteorològic nacional
Principat d'Andorra

Des informations détaillées par espace naturel protégé

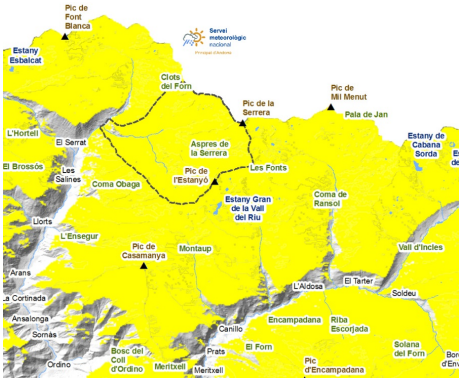

SORTENY

De faibles précipitations se poursuivront avec un niveau de neige autour de 1800 m, qui humidifiera le manteau dans toutes les directions, en dessous de ce niveau ; tandis que de faibles accumulations d'environ 5 cm pourraient se former en amont dans ce secteur. En altitude, le vent pourra transporter le peu de neige disponible et former de petites accumulations irrégulières. Le peu de neige fraîche ne changera pas les conditions de stabilité , , , , , , ,

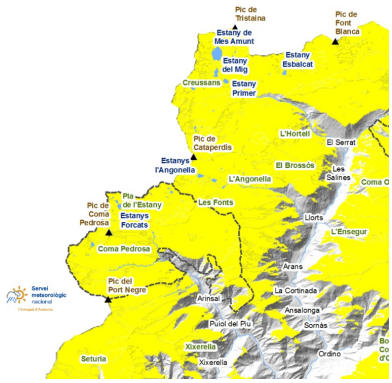

COMAPEDROSA

L'accès depuis Arinsal reçoit de moins en moins de neige, et le peu de pluie attendue retardera encore davantage la ligne de neige continue. Dans les parties supérieures du Parc, de nombreuses excursions peuvent être réalisées, en choisissant toujours avec soin l'itinéraire. Il faudra faire attention à ne pas glisser à cause de la croûte de glace sur les versants sud ou à basse altitude, mais aussi sur les pistes\r\nobacs, où la neige poudreuse cache une croûte dure et venteuse , , , , , , ,

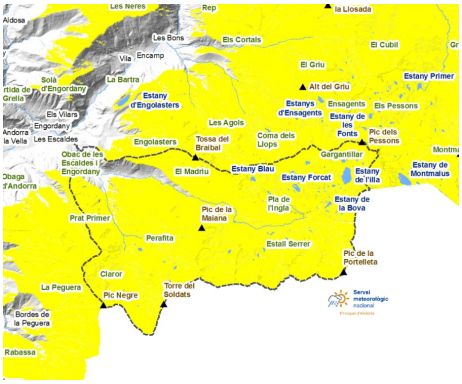

MADRIU-PERAFITA-CLAROR

Le manteau est généralement mince et irrégulier, avec une meilleure continuité neigeuse sur les versants nord et obscurs. C'est le secteur le plus touché par les précipitations, même si dans certains endroits élevés, le vent a laissé à découvert la vieille neige dure. , , ,

Govern d'Andorra

EAWS
EUROPEAN AVALANCHE WARNING SERVICES

Aquest butlletí ha estat elaborat seguint les normes i recomanacions de l'**European Avalanche Warning Services**, del qual el **Servei meteorològic Nacional** n'és membre

BUTLLETÍ DEL PERILL D'ALLAUS DEL PRINCIPAT D'ANDORRA

Servei meteorològic nacional
Principat d'Andorra

Couche de neige fraiche des derniers jours (De 24 h mesurée à 06:00 h UTC)

	04/03/2026	05/03/2026	06/03/2026	07/03/2026
FEDA (Central)	0 cm	0 cm	0 cm	0 cm
Engolasters - FEDA	0 cm	0 cm	0 cm	0 cm
Bony de les Neres	0 cm	0 cm	2 cm	0 cm
Sorteny	3 cm	10 cm	5 cm	2 cm
Les Fonts d'Arinsal	0 cm	10 cm	5 cm	0 cm
Perafita	3 cm	26 cm	3 cm	0 cm
Tossa Espiolets	0 cm	17 cm	5 cm	0 cm
Grau Roig - FEDA	0 cm	3 cm	5 cm	0 cm
Fontverd	0 cm	0 cm	1 cm	0 cm
Ransol - FEDA	0 cm	0 cm	0 cm	0 cm
Setúria	0 cm	0 cm	0 cm	0 cm
Caborreu	0 cm	17 cm	12 cm	0 cm
La Solana	0 cm	10 cm	4 cm	1 cm
Coll Pa	0 cm	9 cm	9 cm	0 cm
Envalira Antenes	0 cm	1 cm	13 cm	0 cm
Vall del Riu FEDA	0 cm	9 cm	5 cm	3 cm