Bulletin d'estimation du risque d'avalanche

(valable en dehors des pistes balisées et ouvertes)

MASSIF : Cinto Rotondo

Rédigé le dimanche 8 mars 2026 à 15h

Estimation des risques pour le : LUNDI 09 MARS

DÉPARTS POSSIBLES EN NEIGE HUMIDE, QUELQUES PETITES INSTABILITÉS EN NEIGE FRAÎCHE EN ALTITUDE

1

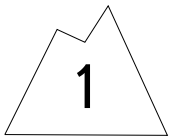

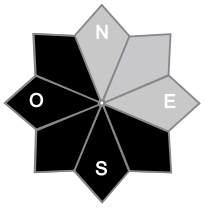

Indice de risque faible.

Départs spontanés : Sous les précipitations, départs en neige fraîche au-dessus de 2000m, ou en neige humide en dessous de 2000m

Déclenchements provoqués : Présence de petites plaques à vent en altitude, risque de départs ponctuels sous les skis en neige humide

Indices de risque : 5 très fort - 4 fort - 3 marqué - 2 limité - 1 faible -- En noir : les pentes les plus dangereuses

Stabilité du manteau neigeux

Situation avalancheuse typique : neige humide

Départs spontanés : En dessous de 2000 m, sous les plus fortes averses de ce dimanche après-midi / soir, puis à nouveau lundi après-midi, des coulées de neige humide (taille 1) se produisent, rarement une avalanche de taille moyenne (taille 2). Par ailleurs, une avalanche de fond de taille moyenne (taille 2) reste possible, emportant la totalité du manteau neigeux sur les dalles rocheuses. Au-dessus de 2000 m, quelques coulées de neige fraîche sont possibles sous les averses de neige, dans les pentes raides. La sous-couche étant bien dense ou dure, seule la neige récente est mobilisable (taille 1).

Déclenchements provoqués : Départs ponctuels sous les skis ou raquettes en neige humide, notamment dans les pentes raides et ensoleillés (taille 1 à 2 suivant l'altitude). Les récentes petites plaques à vent formées dans les pentes orientées Ouest à Nord-Ouest, au-dessus de 2000 m, plus présentes sur le massif du Rotondo, sont recouvertes par les nouvelles chutes de neige. Déclenchement possible surtout par forte surcharge, pouvant engendrer une coulée ne mobilisant pas beaucoup de neige (taille 1).

Autres : Nombreuses surfaces glacées.

Qualité de la neige

Qualification de l'enneigement : L'enneigement est excellent pour la saison au-dessus de 1600 m. Sur la Maniccia, à 2400 m d'altitude dans le massif du Rotondo, on mesure 2m80 de hauteur totale de neige.

Limite d'enneigement skiable : 1500 à 1600 m selon le versant.

État de la neige : Sous l'effet de plus d'une semaine de soleil et de douceur, le manteau neigeux s'est considérablement tassé et il est bien consolidé. En dessous de 2000 m, les récentes pluies ont humidifié le manteau neigeux sur toute son épaisseur, la neige y est souvent lourde et humide. Au-dessus de 2000 à 2100 m, l'humidification est plus limitée. Dans les pentes Nord, la neige reste dure ou cartonnée, parfois recouverte d'une petite couche de neige récente. Le refroidissement récent peut faire apparaitre une petite croûte de regel le matin. Dans les pentes ombragées, les surfaces glacées peuvent persister toute la journée. Nombreuses zones de neige colorée avec les dernières remontées de sable. À noter la présence de corniches parfois volumineuses.

Aperçu météo pour le lundi 09 mars

	nuit	matin	après-midi	soir
Averses orageuses ce dimanche après-midi jusqu'en début de soirée. Quelques averses plus faibles lundi après-midi.				
Pluie-Neige	1 900 m			
Iso 0 °C	2 200 m	2 200 m	2 200 m	2 200 m
Vent 1500 m	5 km/h	5 km/h	10 km/h	15 km/h
Vent 3000 m	10 km/h	10 km/h	15 km/h	25 km/h

Épaisseur de neige hors-piste

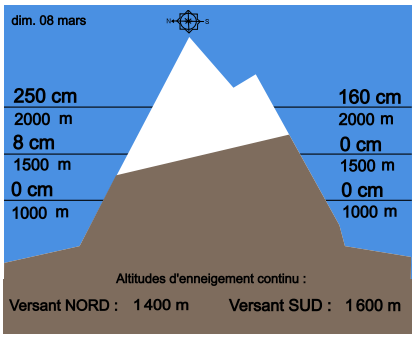

Précipitations à 1800 m

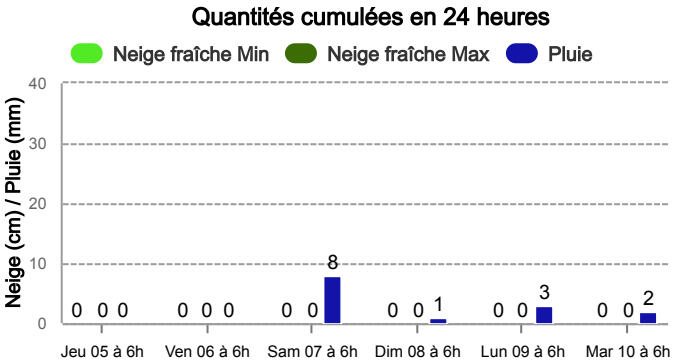

Tendance du mardi 10 mars

1

Indice de risque faible

Quelques départs se produisent en neige humide. Quelques départs possibles également dans la neige récente qui s'est posée en altitude. Les quantités mobilisables sont généralement limitées. Maintien d'un risque faible.

Pour consulter la vigilance en cours, veuillez vous rendre sur le site https://vigilance.meteofrance.fr/fr

Météo-France - 73 avenue de Paris, 94165 Saint-Mandé cedex - Contact : contact@meteo.fr

Rédigé par Météo-France avec la contribution des observateurs du réseau nivo-météorologiques. Partenariat : ANMSM (Maires de Stations de Montagne), DSF (Domaines Skiables de France), ADSP (Directeurs de Pistes et de la Sécurité des Stations de Sports d'Hiver) et autres acteurs de la montagne.

Bulletin neige & avalanches par téléphone au 0 892 68 10 20 Service 0,35 € / min + prix appel

RÉPUBLIQUE FRANÇAISE
Liberté Égalité Fraternité

METEO FRANCE
À VOS CÔTÉS, DANS UN CLIMAT QUI CHANGE

Bulletin d'estimation du risque d'avalanche

(valable en dehors des pistes balisées et ouvertes)

MASSIF : Cinto Rotondo

Rédigé le dimanche 8 mars 2026 à 15h

Conditions nivo-météo des 7 derniers jours

	lun. 02/03				mar. 03/03				mer. 04/03				jeu. 05/03				ven. 06/03				sam. 07/03				dim. 08/03			
	03h	09h	15h	21h	03h	09h	15h	21h	03h	09h	15h	21h	03h	09h	15h	21h	03h	09h	15h	21h	03h	09h	15h	21h	03h	09h	15h	21h
Météo																												
Vent (km/h)	15	25	25	15	15	10	10	10	10	10	10	5	10	15	15	30	45	60	50	40	30	30	20	15	15	10	15	10
à 3000m																												
Vent (km/h)	10	15	20	10	10	15	20	15	10	10	15	10	10	20	25	20	30	40	35	25	20	20	10	10	10	5	10	0
à 1500m																												

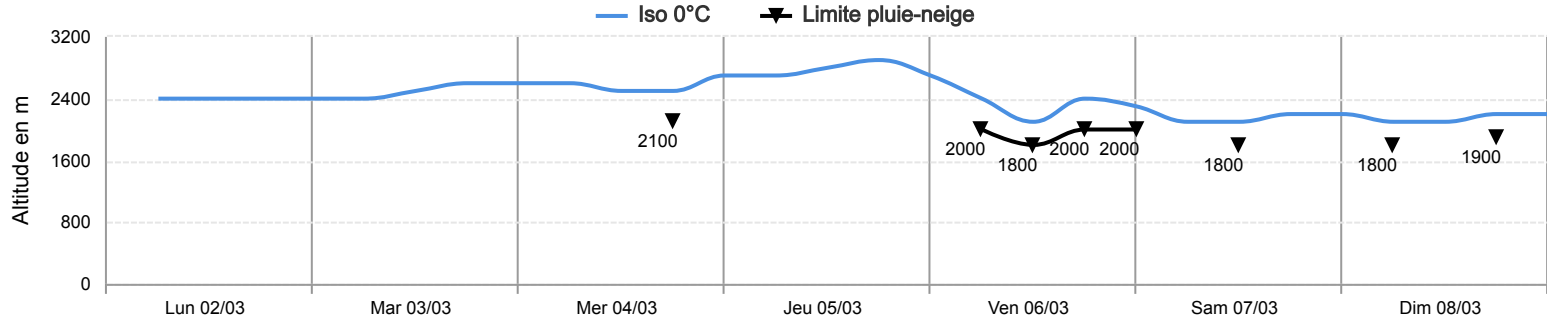

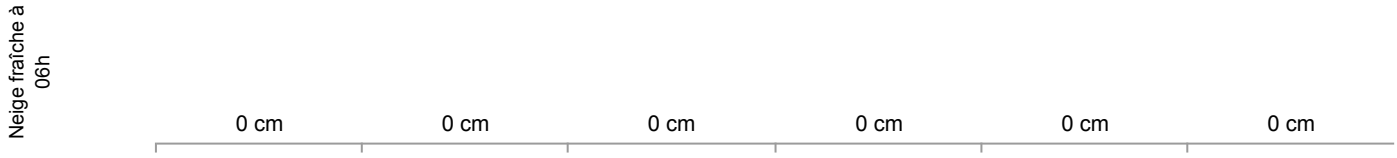

Risque d'avalanche	lun. 02/03	mar. 03/03	mer. 04/03	jeu. 05/03	ven. 06/03	sam. 07/03	dim. 08/03
	2	2	2	2	2	2	1

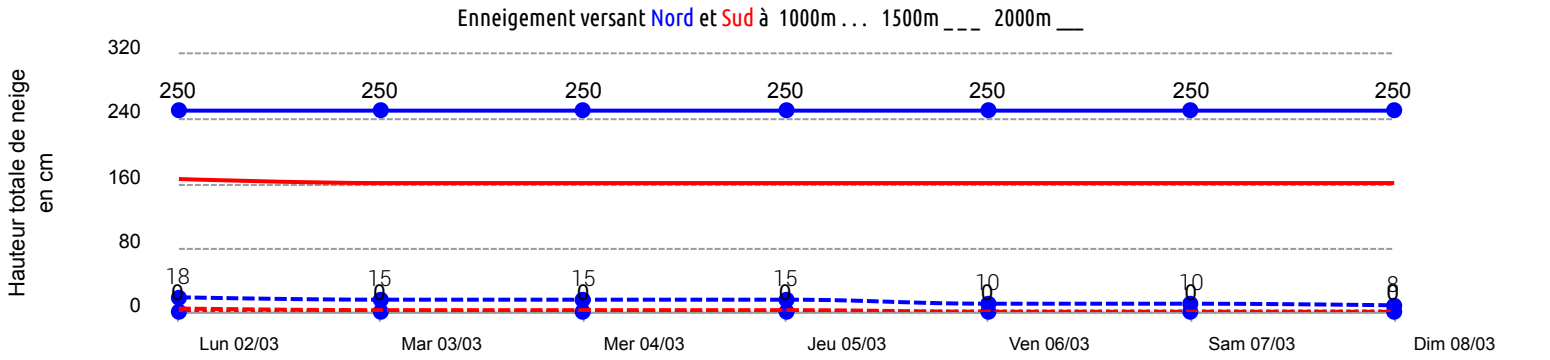

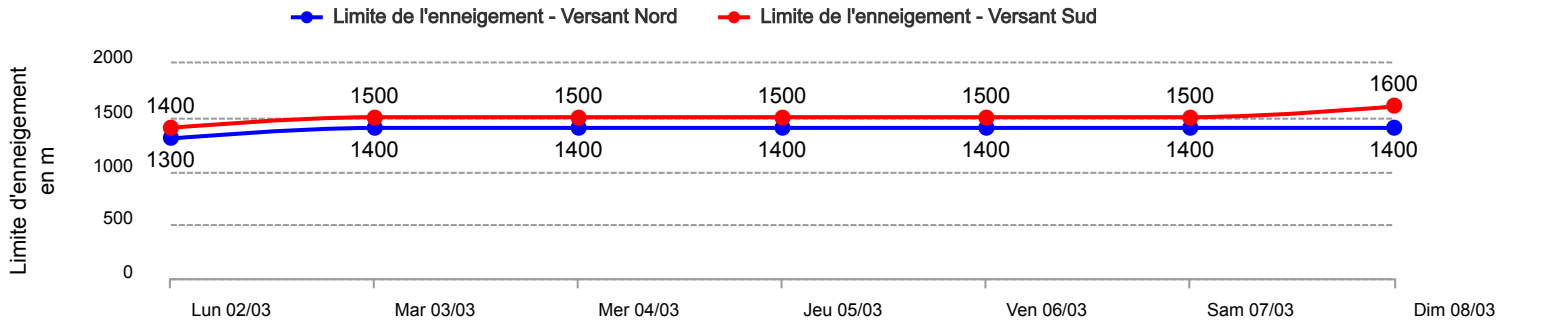

Pour consulter la vigilance en cours, veuillez vous rendre sur le site https://vigilance.meteofrance.fr/fr

Météo-France - 73 avenue de Paris, 94165 Saint-Mandé cedex - Contact : contact@meteo.fr

Bulletin neige & avalanches par téléphone au

0 892 68 10 20 Service 0,35 € / min + prix appel

Rédigé par Météo-France avec la contribution des observateurs du réseau nivo-météorologiques. Partenariat : ANMSM (Maires de Stations de Montagne), DSF (Domaines Skiables de France), ADSP (Directeurs de Pistes et de la Sécurité des Stations de Sports d'Hiver) et autres acteurs de la montagne.