Bulletin d'estimation du risque d'avalanche
(valable en dehors des pistes balisées et ouvertes)

MASSIF : Haut-Var Haut-Verdon

Rédigé le dimanche 8 mars 2026 à 15h

Estimation des risques pour le : LUNDI 09 MARS

MANTEAU NEIGEUX BIEN STABILISÉ

1

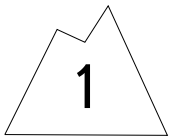

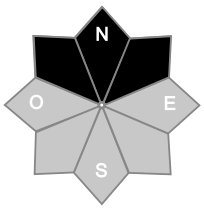

Indice de risque faible.

Départs spontanés : peu probables

Déclenchements provoqués : très rares

Indices de risque : 5 très fort - 4 fort - 3 marqué - 2 limité - 1 faible -- En noir : les pentes les plus dangereuses

Stabilité du manteau neigeux

Situation avalancheuse typique : couche fragile persistante

Déclenchements provoqués : le manteau neigeux est bien stabilisé. Les instabilités se cantonnent à de rares plaques épaisses reposant sur des couches fragiles persistantes enfouies profondément en orientations nord-ouest, nord ou nord-est au-dessus de 2200 m, plutôt sur le Haut-Verdon. Plaques très difficiles à déclencher, mais pouvant être volumineuses.

Départs spontanés : peu probables, sauf éventuellement une avalanche de glissement en pentes d'un large secteur sud, en terrain favorable (pentes herbeuses, dalles rocheuses).

Qualité de la neige

Enneigement plutôt excédentaire pour un début mars en général, notamment dans le Haut-Verdon.
Données observées : vers 2000 m, 160 cm dans le vallon de Valdemars en Haut Verdon, 110 cm dans le vallon de Sanguinière en Haut Var.

Enneigement skiable : vers 1400/1500 m en ubacs, 1800/1900 m en adrets peu pentus.

État de la neige en surface : manteau neigeux printanier dense avec un bon regel nocturne en général. Humidification superficielle en journée dans les pentes ensoleillées. On trouve encore localement de la neige froide en ubacs au-dessus de 2200/2300 m, parfois densifiée par le vent. Sur les crêtes, d'anciennes corniches épaisses côtoient des zones dégarnies par le vent.

Aperçu météo pour le lundi 09 mars

	nuit	matin	après-midi	soir

Belles éclaircies le matin, puis ciel se couvrant en journée, avant l'arrivée de chute de neige en cours d'après-midi.

Pluie-Neige			1 800 m	1 600 m
Iso 0 °C	2 000 m	2 100 m	2 100 m	1 900 m
Vent 2000 m	← 20 km/h	↖ 30 km/h	↖ 40 km/h	← 30 km/h
Vent 3000 m	← 30 km/h	↖ 45 km/h	← 55 km/h	← 45 km/h

Épaisseur de neige hors-piste

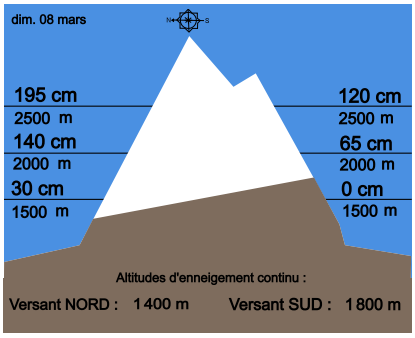

Précipitations à 1800 m

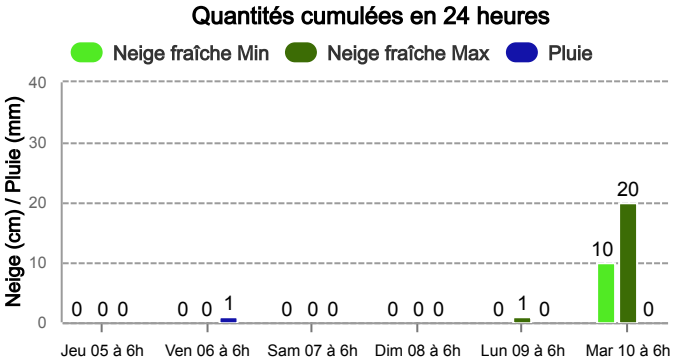

Tendance du mardi 10 mars

2

Indice de risque limité

Risque en hausse avec les chutes de neige dans la nuit de lundi à mardi, qui donneront 10 à 20 cm au-dessus de 1500/1600 m.

Pour consulter la vigilance en cours, veuillez vous rendre sur le site https://vigilance.meteofrance.fr/fr

Météo-France - 73 avenue de Paris, 94165 Saint-Mandé cedex - Contact : contact@meteo.fr

Rédigé par Météo-France avec la contribution des observateurs du réseau nivo-météorologiques. Partenariat : ANMSM (Maires de Stations de Montagne), DSF (Domaines Skiables de France), ADSP (Directeurs de Pistes et de la Sécurité des Stations de Sports d'Hiver) et autres acteurs de la montagne.

Bulletin neige & avalanches par téléphone au
0 892 68 10 20 Service 0,35 € / min + prix appel

Bulletin d'estimation du risque d'avalanche

(valable en dehors des pistes balisées et ouvertes)

MASSIF : Haut-Var Haut-Verdon

Rédigé le dimanche 8 mars 2026 à 15h

Conditions nivo-météo des 7 derniers jours

	lun. 02/03				mar. 03/03				mer. 04/03				jeu. 05/03				ven. 06/03				sam. 07/03				dim. 08/03			
	03h	09h	15h	21h	03h	09h	15h	21h	03h	09h	15h	21h	03h	09h	15h	21h	03h	09h	15h	21h	03h	09h	15h	21h	03h	09h	15h	21h
Météo																												
Vent (km/h)	15	20	15	15	15	10	10	10	10	10	10	10	15	20	25	45	65	60	55	50	35	30	25	15	20	15	15	15
à 3000m																												
Vent (km/h)	10	10	15	10	10	5	10	10	5	5	10	5	20	20	25	40	45	40	40	35	25	20	15	10	15	10	15	10
à 2000m																												

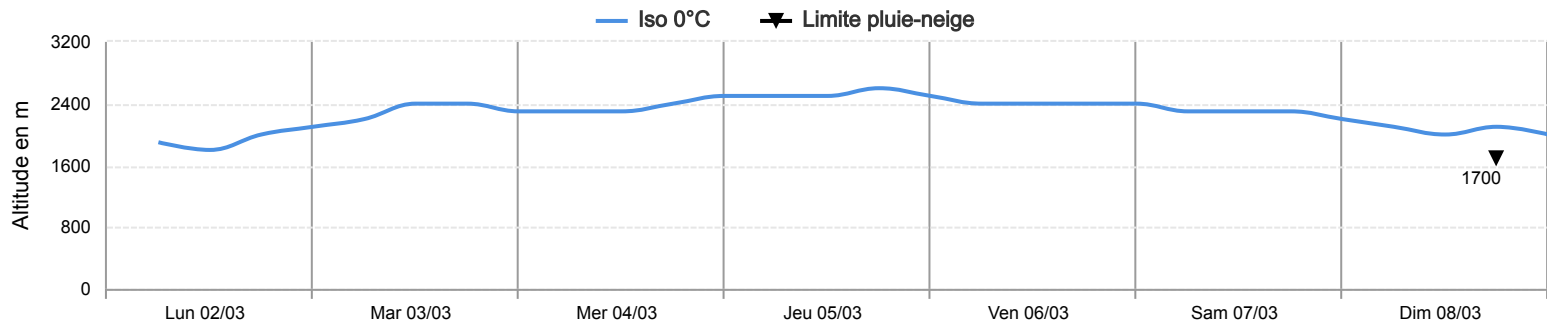

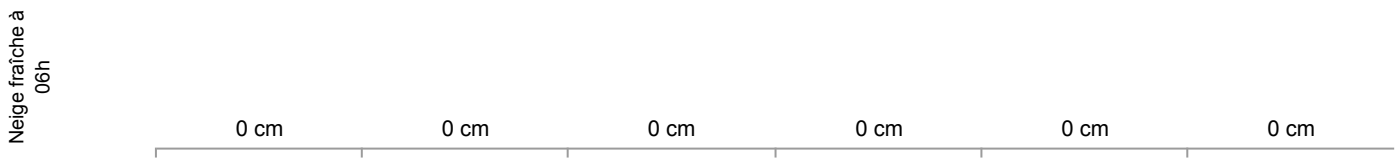

Risque d'avalanche	lun. 02/03	mar. 03/03	mer. 04/03	jeu. 05/03	ven. 06/03	sam. 07/03	dim. 08/03
	2	2	2	2	2	2	2

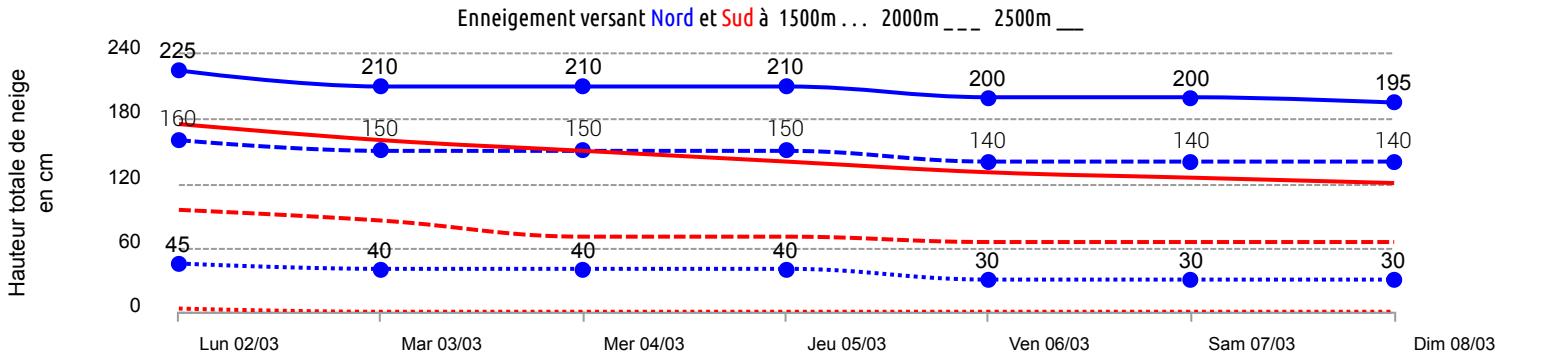

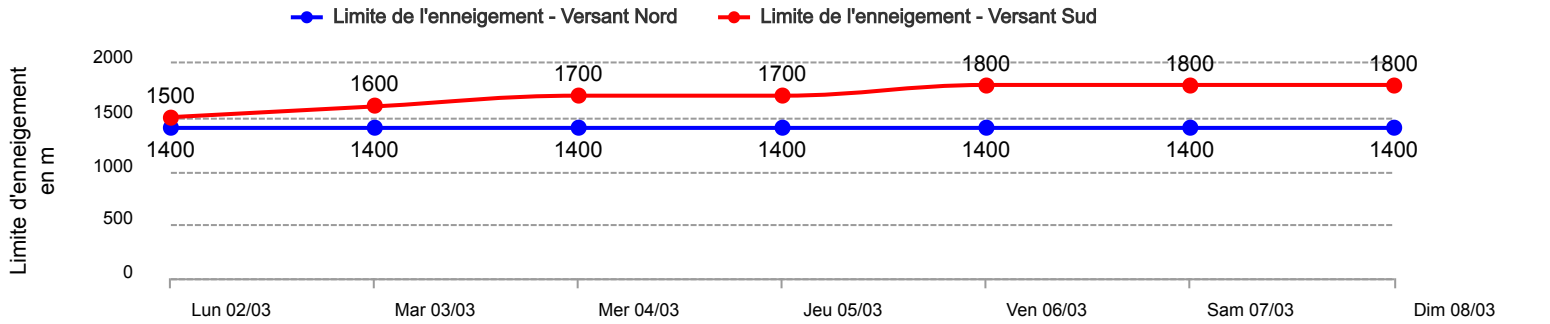

Pour consulter la vigilance en cours, veuillez vous rendre sur le site https://vigilance.meteofrance.fr/fr

Météo-France - 73 avenue de Paris, 94165 Saint-Mandé cedex - Contact : contact@meteo.fr

Rédigé par Météo-France avec la contribution des observateurs du réseau nivo-météorologiques. Partenariat : ANMSM (Maires de Stations de Montagne), DSF (Domaines Skiables de France), ADSP (Directeurs de Pistes et de la Sécurité des Stations de Sports d'Hiver) et autres acteurs de la montagne.

Bulletin neige & avalanches par téléphone au

0 892 68 10 20 Service 0,35 € / min + prix appel