Bulletin d'estimation du risque d'avalanche
(valable en dehors des pistes balisées et ouvertes)

MASSIF : Ubaye

Rédigé le dimanche 8 mars 2026 à 15h

Estimation des risques pour le : LUNDI 09 MARS

MANTEAU NEIGEUX BIEN STABILISÉ, SAUF ÉVENTUELLEMENT EN UBACS D'ALTITUDE

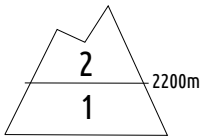

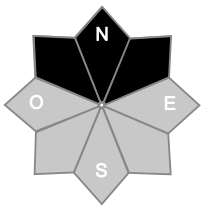

Au-dessus de 2200m indice de risque limité, plus bas indice faible.

Départs spontanés : peu probables

Déclenchements provoqués : instabilités rares et difficiles à déclencher en ubacs d'altitude, mais pouvant être volumineuses

Indices de risque : 5 très fort - 4 fort - 3 marqué - 2 limité - 1 faible -- En noir : les pentes les plus dangereuses

Stabilité du manteau neigeux

Situation avalancheuse typique : couche fragile persistante

Déclenchements provoqués : le manteau neigeux est bien stabilisé. Les instabilités se cantonnent à de rares plaques épaisses reposant sur des couches fragiles persistantes enfouies en orientations nord-ouest, nord ou nord-est au-dessus de 2200 m, surtout en Haute-Ubaye. Difficilement déclenchables par un seul skieur, elles peuvent cependant mobiliser d'importants volumes de neige en cas de départ (taille moyenne, voire grande non exclue).

Départs spontanés : peu probables, sauf éventuellement une avalanche de glissement de taille 2 en pentes d'un large secteur sud, en terrain favorable (pentes herbeuses, dalles rocheuses).

Qualité de la neige

Enneigement proche des normales pour un début mars.
Données observées : 59 cm à la Nivôse de Restefond à 2550 m (secteur venté), 85 cm au-dessus de Larche à 2270 m en adret.

Enneigement skiable : vers 1500 m en ubacs, 1900/2000 m en adrets peu pentus.

État de la neige en surface : manteau neigeux printanier dense avec un bon regel nocturne en général. Humidification superficielle en journée dans les pentes ensoleillées. On trouve encore localement de la neige froide en ubacs au-dessus de 2200/2300 m, parfois densifiée par le vent. Sur les crêtes, d'anciennes corniches épaisses côtoient des zones dégarnies par le vent.

Aperçu météo pour le lundi 09 mars

	nuit	matin	après-midi	soir

Belles éclaircies le matin, puis ciel se couvrant en journée, avant l'arrivée de chute de neige en fin d'après-midi.

	nuit	matin	après-midi	soir
Pluie-Neige			1 800 m	1 600 m
Iso 0 °C	2 100 m	2 200 m	2 100 m	1 900 m
Vent 2000 m	↖ 15 km/h	← 25 km/h	← 30 km/h	← 20 km/h
Vent 3000 m	← 25 km/h	← 35 km/h	↖ 40 km/h	← 35 km/h

Épaisseur de neige hors-piste

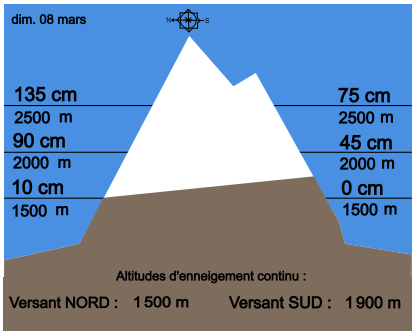

Précipitations à 1800 m

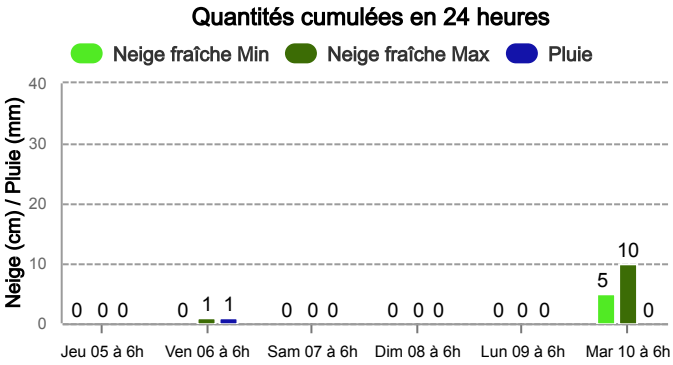

Tendance du mardi 10 mars

Indice de risque limité

Risque restant limité mais en hausse avec les chutes de neige dans la nuit de lundi à mardi, qui donneront une 5 à 10 centimètres au-dessus de 1500/1600 m.

Pour consulter la vigilance en cours, veuillez vous rendre sur le site https://vigilance.meteofrance.fr/fr

Météo-France - 73 avenue de Paris, 94165 Saint-Mandé cedex - Contact : contact@meteo.fr

Rédigé par Météo-France avec la contribution des observateurs du réseau nivo-météorologiques. Partenariat : ANMSM (Maires de Stations de Montagne), DSF (Domaines Skiables de France), ADSP (Directeurs de Pistes et de la Sécurité des Stations de Sports d'Hiver) et autres acteurs de la montagne.

Bulletin neige & avalanches par téléphone au
0 892 68 10 20 Service 0,35 € / min + prix appel

RÉPUBLIQUE FRANÇAISE
Liberté Égalité Fraternité

METEO FRANCE
À VOS CÔTÉS, DANS UN CLIMAT QUI CHANGE

Bulletin d'estimation du risque d'avalanche

(valable en dehors des pistes balisées et ouvertes)

MASSIF : Ubaye

Rédigé le dimanche 8 mars 2026 à 15h

Conditions nivo-météo des 7 derniers jours

	lun. 02/03				mar. 03/03				mer. 04/03				jeu. 05/03				ven. 06/03				sam. 07/03				dim. 08/03			
	03h	09h	15h	21h	03h	09h	15h	21h	03h	09h	15h	21h	03h	09h	15h	21h	03h	09h	15h	21h	03h	09h	15h	21h	03h	09h	15h	21h
Météo																												
Vent (km/h)	10	15	15	10	10	10	10	10	10	10	10	10	20	20	30	45	60	60	50	45	40	30	25	20	25	15	15	15
à 3000m																												
Vent (km/h)	10	15	15	10	10	5	10	10	5	5	10	10	25	30	35	40	35	30	30	30	25	25	20	15	15	15	15	10
à 2000m																												

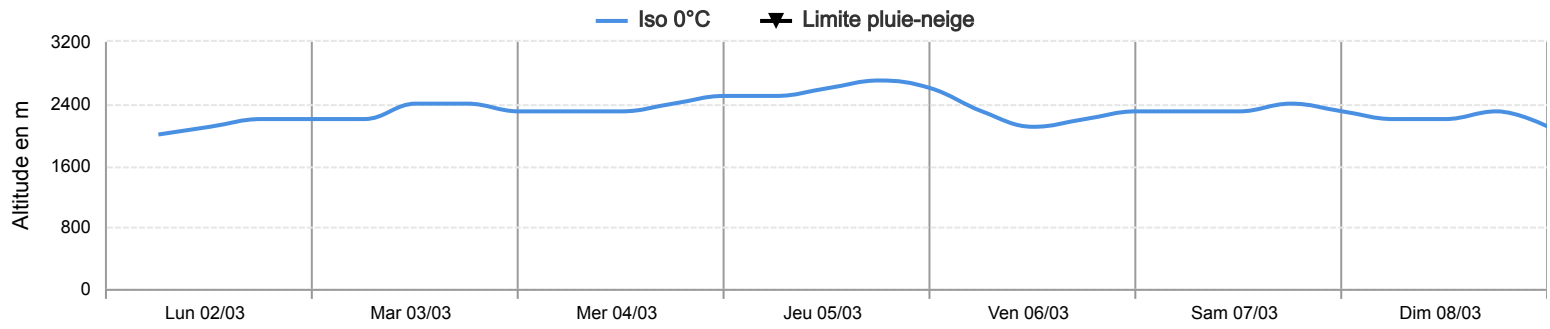

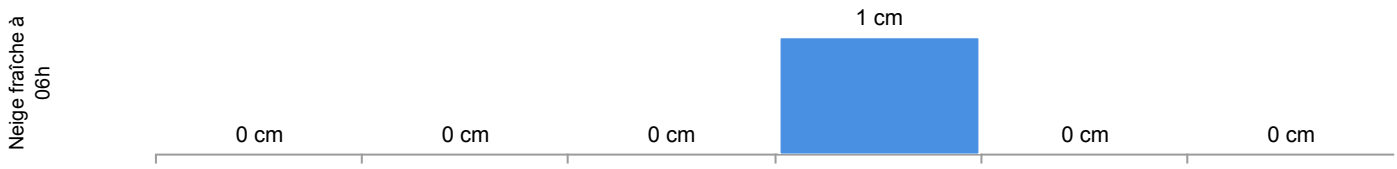

Risque d'avalanche	lun. 02/03	mar. 03/03	mer. 04/03	jeu. 05/03	ven. 06/03	sam. 07/03	dim. 08/03
	2	2	2	2	2	2	2

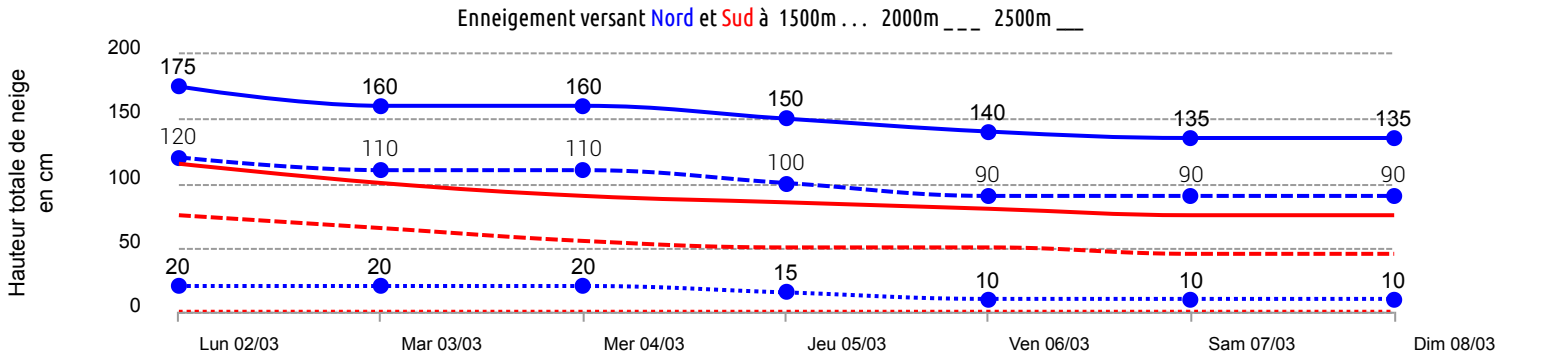

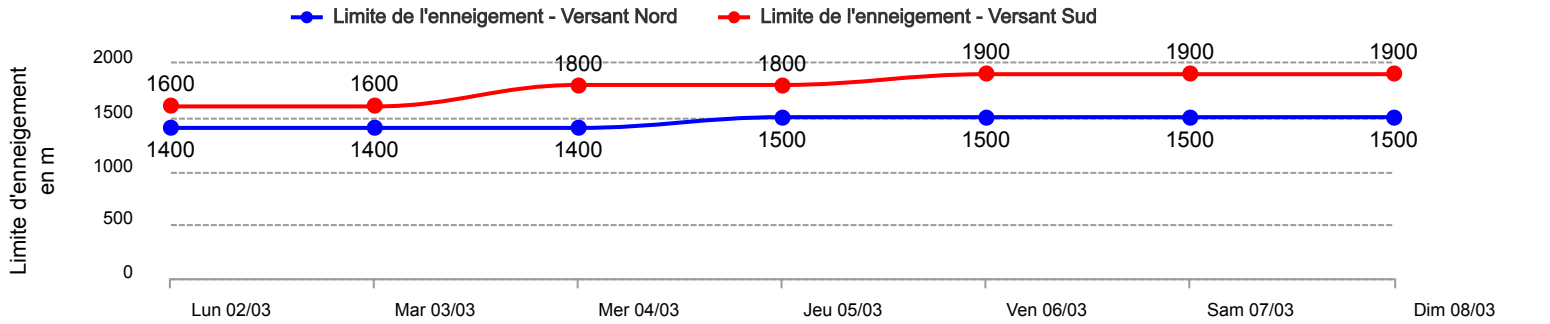

Pour consulter la vigilance en cours, veuillez vous rendre sur le site https://vigilance.meteofrance.fr/fr

Météo-France - 73 avenue de Paris, 94165 Saint-Mandé cedex - Contact : contact@meteo.fr

Rédigé par Météo-France avec la contribution des observateurs du réseau nivo-météorologiques. Partenariat : ANMSM (Maires de Stations de Montagne), DSF (Domaines Skiables de France), ADSP (Directeurs de Pistes et de la Sécurité des Stations de Sports d'Hiver) et autres acteurs de la montagne.

Bulletin neige & avalanches par téléphone au
0 892 68 10 20 Service 0,35 € / min + prix appel