Bulletin d'estimation du risque d'avalanche

(valable en dehors des pistes balisées et ouvertes)

MASSIF : Aspe Ossau

Rédigé le dimanche 8 mars 2026 à 16h

Estimation des risques pour le : LUNDI 09 MARS

CONJUGAISON DE NEIGE HUMIDE ET DE NEIGE RECENTE.

2

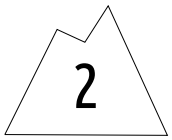

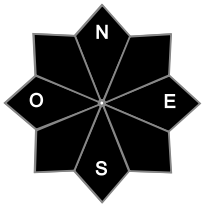

Indice de risque limité.

Départs spontanés : en neige récente et en neige humide.

Déclenchements provoqués : en neige humide au soleil, en neige récente à l'ombre, structures de plaques difficilement sollicitables au-dessus de 2400m.

Indices de risque : 5 très fort - 4 fort - 3 marqué - 2 limité - 1 faible -- En noir : les pentes les plus dangereuses

Stabilité du manteau neigeux

Situation avalancheuse typique : neige humide avalanches de fond

Départs spontanés :
- en **neige récente** : départs ponctuels près des rochers de coulées ou petites avalanches en pentes raides, en neige récente tombée ce dimanche et celle attendue lundi après-midi.
- en **neige humide** et souvent sous forme de **départs ponctuels près des rochers** de la **vieille neige lourde** en place, et de la **neige récente tombée dimanche s'humidifiant** rapidement dans les pentes ensoleillées de la matinée. Avalanches généralement de **taille 1 à 2.**

Plus localement, principalement dans les pentes sud raides, une avalanche de **taille 3 possible** avec le **départ linéaire d'une avalanche de fond** partant des **accumulations** encore présentes au-dessus de 2000m, emportant la **totalité du manteau neigeux** humide et lourd encore en place en contrebas, notamment près des **ruptures de pentes ou au niveau d'une fissure**.

Déclenchements provoqués : déclenchement **aisé pour un skieur ou randonneur** de **coulée ou petite avalanche** :
- de neige récente en **pentes raides**, plutôt **versants ombragés en matinée**, **tous versants l'après-midi avec les nouvelles averses de neige**,
- de la neige récente s'**alourdissant dans les pentes raides ensoleillées de la matinée**.

Cependant, **au-dessus de 2400m** dans les versants **nord-ouest à nord-est**, la neige tombée en fin de semaine dernière recouvrent de **vieilles structures de plaques encore en place**; ces structures localisées, constituées des couches plus fragiles bien enfouies et isolées par des couches assez épaisses avec beaucoup de cohésion, sont désormais **sensibles aux fortes sollicitations**. Le **déclenchement d'une avalanche de plaque de taille 2 à localement 3**, bien que peu probable, reste donc **très localement possibles**.

Autres : ponts de neige et corniches encore en place fragiles au soleil de la matinée.

Qualité de la neige

Enneigement : aspect plus hivernal ce lundi matin sur l'ensemble du massif, avec un saupoudrage dès 1500/1600m, couche plus épaisse au-dessus, mais restant hétérogène près des sommets, cols et crêtes, dégarnis en particulier en versants Ouest. Combes plus chargées et corniches encore en place.
Limites skiables : à partir de 1500m en versants froids, plutôt 1700m en versants Sud, mais sans sous-couche en dessous de 1800/1900m.
État de la neige : couche de neige fraîche au petit matin, tombée sans vent au-dessus de 1500m ce dimanche, s'humidifiant au soleil, restant sèche et meuble à l'ombre.
Quelques centimètres de neige fraîche, restant sèche et meuble, se rajouteront sous les averses de l'après-midi à partir de 1700m.

Aperçu météo pour le lundi 09 mars

	nuit	matin	après-midi	soir

Beau temps sec et ensoleillé le matin, averses de neige l'après-midi, vent faible.

Pluie-Neige			1700 m	
Iso 0 °C	1800 m	1900 m	2000 m	2000 m
Vent 1500 m	0 km/h	5 km/h	5 km/h	5 km/h
Vent 3000 m	10 km/h	15 km/h	20 km/h	15 km/h

Épaisseur de neige hors-piste

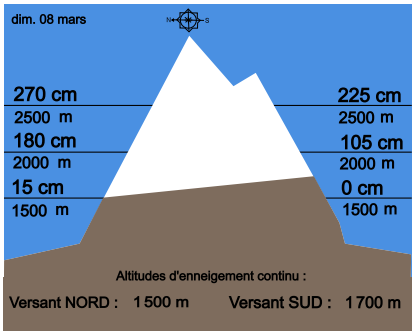

Précipitations à 1800 m

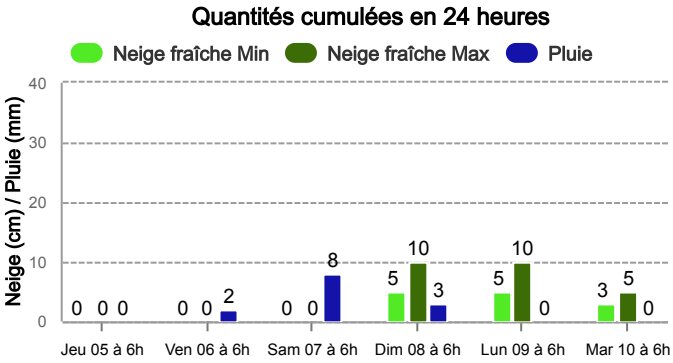

Tendance du mardi 10 mars

2

Indice de risque limité

Cycle gel/dégel plus efficace dans la nuit de lundi à mardi, beau mardi matin, quelques averses mardi après-midi : sans changement notable des conditions nivo-météorologiques, le risque restera limité.

Pour consulter la vigilance en cours, veuillez vous rendre sur le site https://vigilance.meteofrance.fr/fr

Météo-France - 73 avenue de Paris, 94165 Saint-Mandé cedex - Contact : contact@meteo.fr

Rédigé par Météo-France avec la contribution des observateurs du réseau nivo-météorologiques. Partenariat : ANMSM (Maires de Stations de Montagne), DSF (Domaines Skiables de France), ADSP (Directeurs de Pistes et de la Sécurité des Stations de Sports d'Hiver) et autres acteurs de la montagne.

Bulletin neige & avalanches par téléphone au

0 892 68 10 20 Service 0,35 € / min + prix appel

RÉPUBLIQUE FRANÇAISE
Liberté Égalité Fraternité

METEO FRANCE
À VOS CÔTÉS, DANS UN CLIMAT QUI CHANGE

Bulletin d'estimation du risque d'avalanche

(valable en dehors des pistes balisées et ouvertes)

MASSIF : Aspe Ossau

Rédigé le dimanche 8 mars 2026 à 16h

Conditions nivo-météo des 7 derniers jours

	lun. 02/03				mar. 03/03				mer. 04/03				jeu. 05/03				ven. 06/03				sam. 07/03				dim. 08/03			
	03h	09h	15h	21h	03h	09h	15h	21h	03h	09h	15h	21h	03h	09h	15h	21h	03h	09h	15h	21h	03h	09h	15h	21h	03h	09h	15h	21h
Météo																												
Vent (km/h)	55	45	50	40	35	15	15	15	25	25	30	40	45	45	35	25	20	15	30	50	25	20	40	50	30	20	20	15
à 3000m																												
Vent (km/h)	40	35	30	30	25	10	10	10	15	10	15	20	25	25	20	10	10	10	15	10	10	15	10	10	10	5	5	5
à 1500m																												

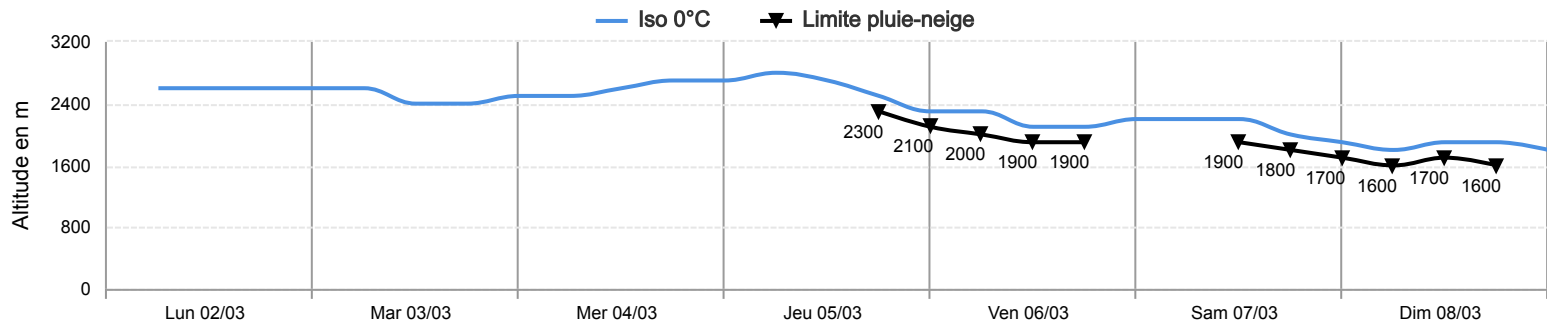

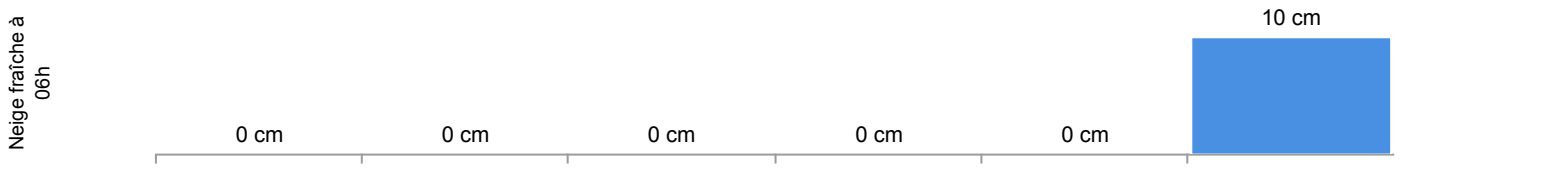

Risque d'avalanche	lun. 02/03	mar. 03/03	mer. 04/03	jeu. 05/03	ven. 06/03	sam. 07/03	dim. 08/03
	2	2	2	2	2	2	2

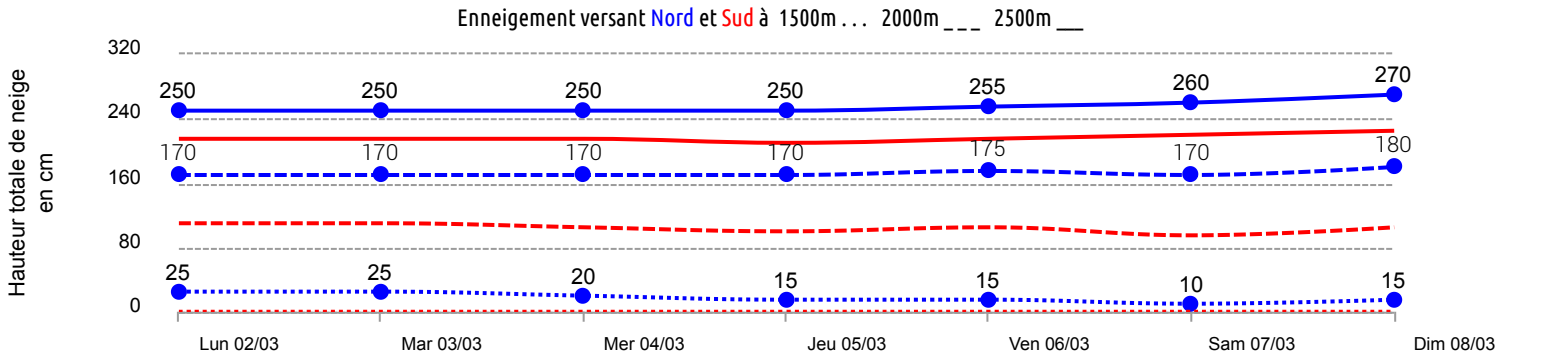

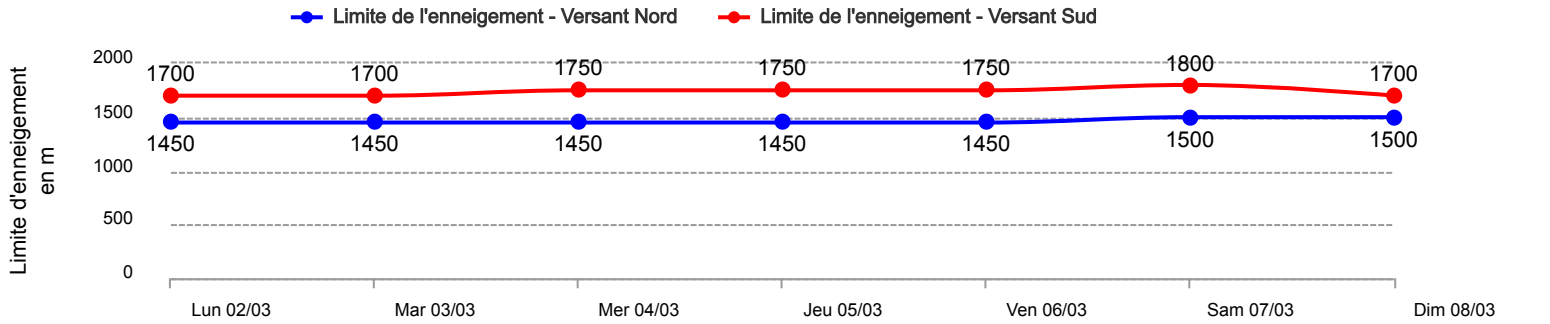

Pour consulter la vigilance en cours, veuillez vous rendre sur le site https://vigilance.meteofrance.fr/fr

Météo-France - 73 avenue de Paris, 94165 Saint-Mandé cedex - Contact : contact@meteo.fr

Rédigé par Météo-France avec la contribution des observateurs du réseau nivo-météorologiques. Partenariat : ANMSM (Maires de Stations de Montagne), DSF (Domaines Skiables de France), ADSP (Directeurs de Pistes et de la Sécurité des Stations de Sports d'Hiver) et autres acteurs de la montagne.

Bulletin neige & avalanches par téléphone au
0 892 68 10 20 Service 0,35 € / min + prix appel