RÉPUBLIQUE FRANÇAISE
Liberté Égalité Fraternité

METEO FRANCE
À VOS CÔTÉS, DANS UN CLIMAT QUI CHANGE

Bulletin d'estimation du risque d'avalanche
(valable en dehors des pistes balisées et ouvertes)
MASSIF : Cerdagne Canigou

Rédigé le dimanche 8 mars 2026 à 16h

Estimation des risques pour le : LUNDI 09 MARS

MANTEAU NEIGEUX INSTABLE DU FAIT DES CUMULS DE NEIGE FRAÎCHE CONSÉQUENTS EN ALTITUDE ET D'UN MANTEAU PROFONDÉMENT HUMIDIFIÉ AUX ALTITUDES INFÉRIEURES

3

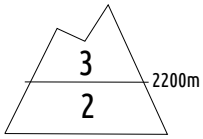

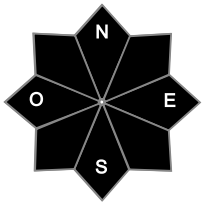

Au-dessus de 2200m indice de risque marqué, plus bas indice limité.

Départs spontanés : Quelques avalanches de neige humide parfois jusqu'au sol

Déclenchements provoqués : Structures de plaques dans la neige fraîche en cours de stabilisation

Indices de risque : 5 très fort - 4 fort - 3 marqué - 2 limité - 1 faible -- En noir : les pentes les plus dangereuses

Stabilité du manteau neigeux

Situation avalancheuse typique : neige fraîche neige humide

Déclenchements provoqués :

* En tous versants, mais surtout sous le vent d'est à sud-est au-dessus de 2200/2300m, des déclenchements d'avalanches sont encore possibles au passage d'un pratiquant. Les avalanches sont de taille moyenne à grande, selon l'épaisseur de neige fraîche. En effet, des structures de plaques se sont formées pendant les fortes chutes de neige de jeudi et vendredi qui se sont produites sous un vent d'est à sud-est. Ces plaques sont en cours de stabilisation. Elles sont difficilement détectables.
* Sous 2200/2300m un skieur peut facilement provoquer des coulées de neige humide sous les skis dans la neige récente gorgée d'eau sans cohésion, pouvant provoquer la chute du skieur. Selon la configuration du terrain, un skieur peut se retrouver enseveli.

Observables: en altitude quantités critiques de neige fraiche (30/50 cm et localement plus), fissures sous les skis, observation alentours d'avalanche dans la neige récente en pente raide ; plus bas neige humide sans cohésion partant sous les skis

Départs spontanés :

Du fait des éclaircies, des avalanches de neige humide de taille petite à moyenne sont à attendre sous 2200m dans les secteurs ensoleillés, voire un peu plus haut si les éclaircies se révèlent généreuses demain. De plus, des avalanches de fond en neige humide en dessous de 2000m sont susceptibles de se produire d'ici demain soir. Enfin, une chute de corniche reste une éventualité.

Qualité de la neige

Enneigement :

L'enneigement est nettement excédentaire dès la moyenne montagne grâce à la succession de nombreuses perturbations neigeuses depuis le début de l'année, avec un nouvel apport jeudi et vendredi de l'ordre de 50 cm à 1m de neige fraîche en haute-montagne. Les vallons ombragés sont encore bien enneigés notamment en versant est et nord.

Malgré la relative douceur, il est en général possible de chausser dès 1600/1800m d'altitude. La limite skiable remonte toutefois dans les pentes ensoleillées. Le manteau neigeux atteint rapidement 1m d'épaisseur et dépasse encore les 2m au-dessus de 2200m avec localement en haute-montagne plus d'un mètre de neige fraîche notamment sur le massif du Canigou.

Qualité de la neige :

Au petit matin, dès 1600/1800m, on pourra trouver une fine couche de neige aux quelques endroits où les averses de ce dimanche se seront produites. Elle repose sur une couche de neige humidifiée en profondeur jusqu'à 2000/2200m en nord et encore plus haut en secteurs ensoleillés. Là où cette couche humidifiée est directement en surface, le regel devrait être assez bon à la faveur des éclaircies nocturnes. Plus haut, on trouvera une couche de neige fraiche importante, notamment dans les secteurs à l'abri du vent d'est à sud-est.

Aperçu météo pour le lundi 09 mars

	nuit	matin	après-midi	soir
	Assez beau le matin puis averses l'après-midi			
Pluie-Neige	1 600 m		1 700 m	
Iso 0 °C	2 000 m	2 300 m	2 200 m	2 100 m
Vent 2000 m	↑ 10 km/h	↑ 10 km/h	↑ 10 km/h	↑ 5 km/h
Vent 3000 m	↑ 20 km/h	↑ 15 km/h	↑ 15 km/h	↑ 10 km/h

Pour consulter la vigilance en cours, veuillez vous rendre sur le site https://vigilance.meteofrance.fr/fr

Météo-France - 73 avenue de Paris, 94165 Saint-Mandé cedex - Contact : contact@meteo.fr

Rédigé par Météo-France avec la contribution des observateurs du réseau nivo-météorologiques. Partenariat : ANMSM (Maires de Stations de Montagne), DSF (Domaines Skiables de France), ADSP (Directeurs de Pistes et de la Sécurité des Stations de Sports d'Hiver) et autres acteurs de la montagne.

Bulletin neige & avalanches par téléphone au
0 892 68 10 20 Service 0,35 € / min + prix appel

RÉPUBLIQUE FRANÇAISE
Liberté Égalité Fraternité

METEO FRANCE
À VOS CÔTÉS, DANS UN CLIMAT QUI CHANGE

Bulletin d'estimation du risque d'avalanche

(valable en dehors des pistes balisées et ouvertes)

MASSIF : Cerdagne Canigou

Rédigé le dimanche 8 mars 2026 à 16h

Épaisseur de neige hors-piste

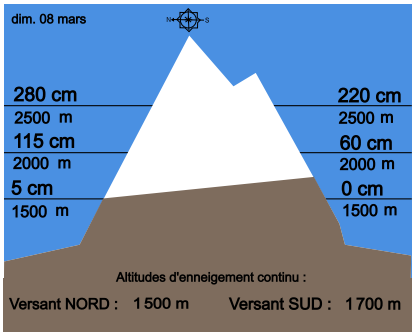

Précipitations à 1800 m

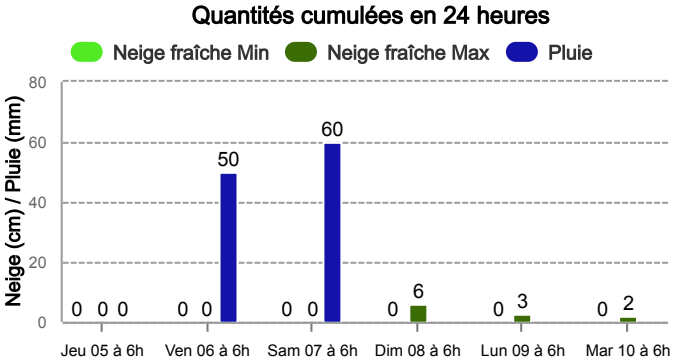

Tendance du mardi 10 mars

Indice de risque limité

Baisse probable du risque avalancheux avec la stabilisation du manteau neigeux en altitude

Pour consulter la vigilance en cours, veuillez vous rendre sur le site https://vigilance.meteofrance.fr/fr

Météo-France - 73 avenue de Paris, 94165 Saint-Mandé cedex - Contact : contact@meteo.fr

Rédigé par Météo-France avec la contribution des observateurs du réseau nivo-météorologiques. Partenariat : ANMSM (Maires de Stations de Montagne), DSF (Domaines Skiables de France), ADSP (Directeurs de Pistes et de la Sécurité des Stations de Sports d'Hiver) et autres acteurs de la montagne.

Bulletin neige & avalanches par téléphone au

0 892 68 10 20 Service 0,35 € / min + prix appel

Bulletin d'estimation du risque d'avalanche

(valable en dehors des pistes balisées et ouvertes)

MASSIF : Cerdagne Canigou

Rédigé le dimanche 8 mars 2026 à 16h

Conditions nivo-météo des 7 derniers jours

	lun. 02/03				mar. 03/03				mer. 04/03				jeu. 05/03				ven. 06/03				sam. 07/03				dim. 08/03			
	03h	09h	15h	21h	03h	09h	15h	21h	03h	09h	15h	21h	03h	09h	15h	21h	03h	09h	15h	21h	03h	09h	15h	21h	03h	09h	15h	21h
Météo																												
Vent (km/h)	40	50	50	40	45	35	25	25	40	35	40	25	45	50	50	50	45	50	55	40	40	40	30	25	30	25	25	20
à 3000m																												
Vent (km/h)	20	30	30	25	30	25	20	15	25	20	25	15	30	30	30	30	25	35	35	30	25	30	20	15	20	20	15	10
à 2000m																												

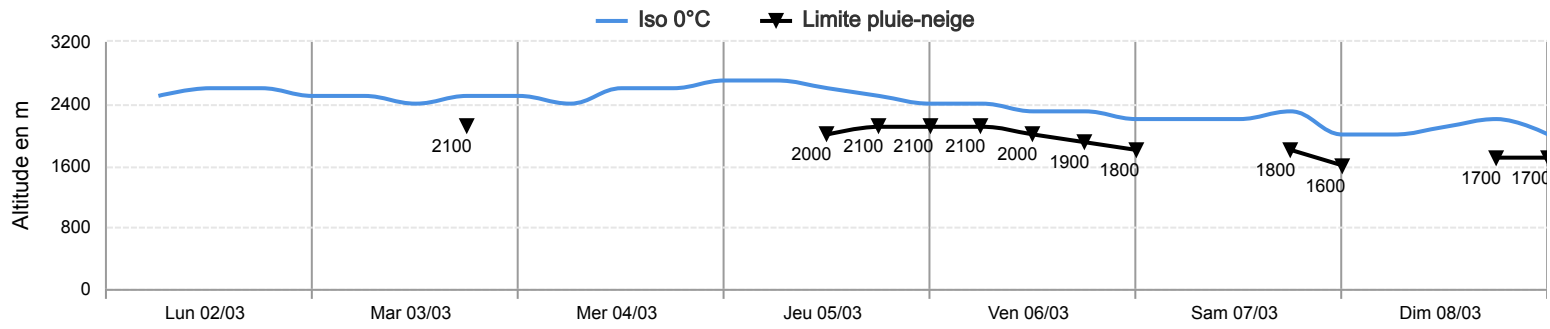

Risque d'avalanche	lun. 02/03	mar. 03/03	mer. 04/03	jeu. 05/03	ven. 06/03	sam. 07/03	dim. 08/03
	2	2	2	3	3	3	3

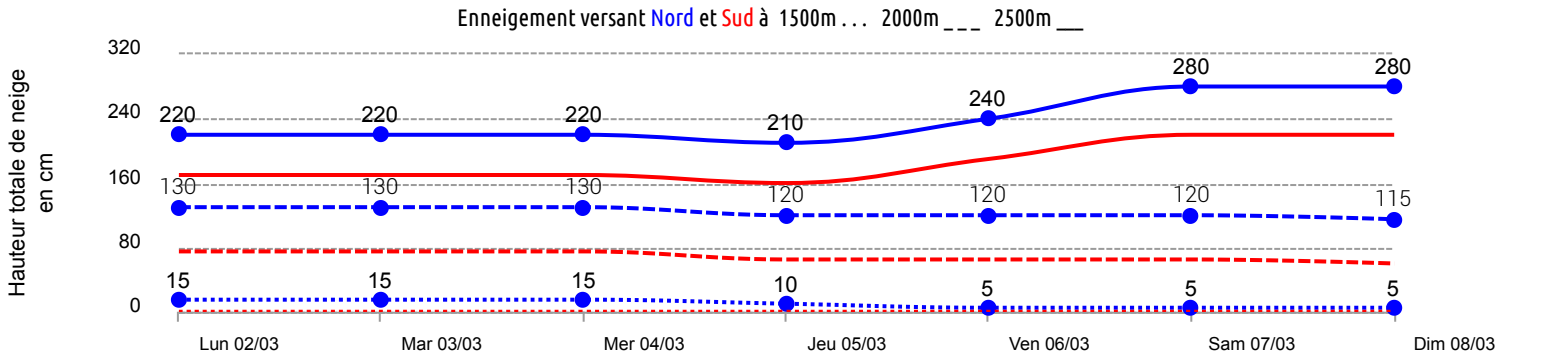

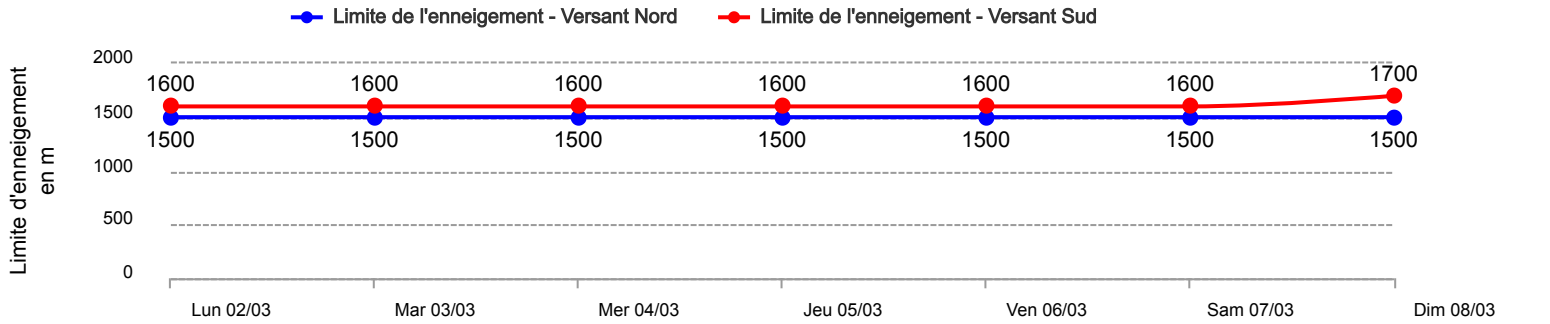

Pour consulter la vigilance en cours, veuillez vous rendre sur le site https://vigilance.meteofrance.fr/fr

Météo-France - 73 avenue de Paris, 94165 Saint-Mandé cedex - Contact : contact@meteo.fr

Rédigé par Météo-France avec la contribution des observateurs du réseau nivo-météorologiques. Partenariat : ANMSM (Maires de Stations de Montagne), DSF (Domaines Skiables de France), ADSP (Directeurs de Pistes et de la Sécurité des Stations de Sports d'Hiver) et autres acteurs de la montagne.

Bulletin neige & avalanches par téléphone au

0 892 68 10 20 Service 0,35 € / min + prix appel