Bulletin d'estimation du risque d'avalanche

(valable en dehors des pistes balisées et ouvertes)

MASSIF : Champsaur

Rédigé le dimanche 8 mars 2026 à 16h

Estimation des risques pour le : LUNDI 09 MARS

MAINTIEN D'UN PEU D'ACTIVITÉ NATURELLE EN AVALANCHES DE FOND / NEIGE HUMIDE - QUELQUES INSTABILITÉS EN ALTITUDE, DIFFICILES À SOLLICITER

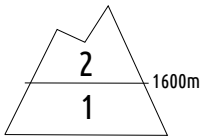

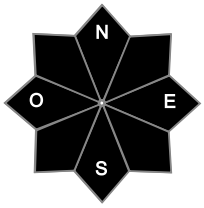

Au-dessus de 1600m indice de risque limité, plus bas indice faible.

Départs spontanés : quelques avalanches de fond ou de neige humide.

Déclenchements provoqués : quelques plaques en altitude, difficiles à déclencher.

Indices de risque : 5 très fort - 4 fort - 3 marqué - 2 limité - 1 faible -- En noir : les pentes les plus dangereuses

Stabilité du manteau neigeux

Situation avalancheuse typique : avalanches de fond couche fragile persistante

Départs spontanés : * Quelques avalanches de fond à toute heure du jour ou de la nuit, sur les secteurs avec un sol favorable (pentes herbeuses, dalles rocheuses). Départ en général sous 1800/2000 m en ubacs, sous 2400/2500 m en adrets. Avalanches souvent de taille moyenne (taille 2), avec un dépôt souvent épais.
* Activité naturelle en neige humide selon la course du soleil, mais restant limitée. Avalanches généralement petites (taille 1).

Déclenchements provoqués : * Quelques plaques reposant sur des couches fragiles persistantes sont encore en place dans le manteau neigeux, mais elles sont difficiles à solliciter. Déclenchement non exclu au passage d'un skieur, plutôt dans les ubacs au-dessus de 2200 m, dans les secteurs où les épaisseurs de neige sont moins importantes (près des croupes, bords des couloirs etc.). Cassure épaisse en cas de départ, emportant une grande partie du manteau neigeux.
* Un skieur peut favoriser un départ superficiel de neige humide, dans une pente très raide ayant suffisamment chauffé au soleil.

Qualité de la neige

L'enneigement est encore excédentaire ou se rapproche des normales selon les secteurs. Les limites d'enneigement remontent dans les pentes bien exposées au soleil.
Hauteurs de neige observées : 42 cm au hameau des Portes dans le Valgaudemar à 1270 m, 132 cm à la Nivôse d'Orcières à 2280 m, et 173 cm au-dessus de Prapic à 2480 m.

Limite d'enneigement skiable : vers 1300 m en ubacs, 1600/1700 m en adrets pas trop raides.

État de la neige de surface : en début de journée, manteau neigeux croûté dans les adrets, ainsi qu'en ubacs sous 2000/2200 m. Humidification au soleil en cours de journée.
Dans les pentes nord-ouest à nord-est au-dessus de 2200 m environ, neige encore froide, travaillée par les épisodes de vent passés, ou en neige ancienne meuble dans les secteurs abrités.

Aperçu météo pour le lundi 09 mars

nuit	matin	après-midi	soir

Soleil dominant le matin, de plus en plus nuageux l'après-midi. Arrivée d'une perturbation dans la nuit de lundi à mardi.

Pluie-Neige				1 400 m
Iso 0 °C	2 100 m	2 100 m	2 200 m	1 800 m
Vent 2000 m	← 10 km/h	← 15 km/h	← 20 km/h	← 25 km/h
Vent 3000 m	← 20 km/h	← 25 km/h	← 30 km/h	← 40 km/h

Épaisseur de neige hors-piste

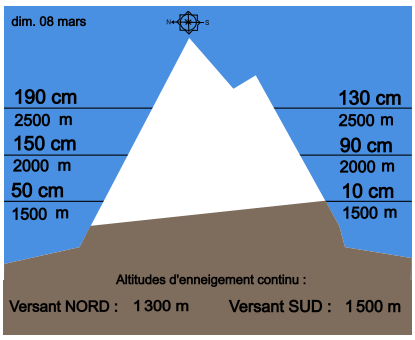

Précipitations à 1800 m

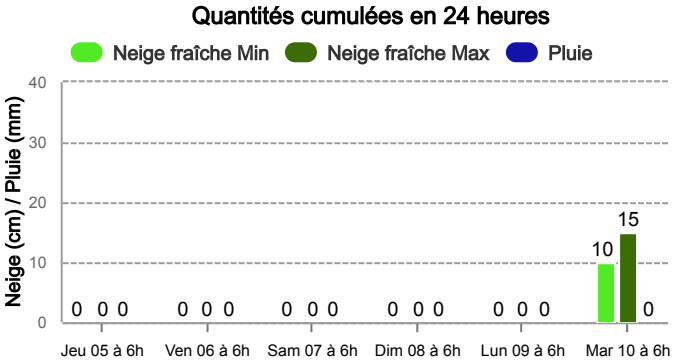

Tendance du mardi 10 mars

Indice de risque limité

- Quelques plaques dans la neige fraîche faciles à déclencher dans les ubacs d'altitude, mais de dimensions limitées.
- La probabilité d'un départ "en cascade" suite à une première avalanche superficielle, et sollicitant la couche fragile persistante enfouie à la base du manteau neigeux, est en légère hausse.
- Départs spontanés de neige fraîche s'humidifiant au soleil, avec le retour des éclaircies.

Pour consulter la vigilance en cours, veuillez vous rendre sur le site https://vigilance.meteofrance.fr/fr

Météo-France - 73 avenue de Paris, 94165 Saint-Mandé cedex - Contact : contact@meteo.fr

Rédigé par Météo-France avec la contribution des observateurs du réseau nivo-météorologiques. Partenariat : ANMSM (Maires de Stations de Montagne), DSF (Domaines Skiables de France), ADSP (Directeurs de Pistes et de la Sécurité des Stations de Sports d'Hiver) et autres acteurs de la montagne.

Bulletin neige & avalanches par téléphone au
0 892 68 10 20 Service 0,35 € / min + prix appel

RÉPUBLIQUE FRANÇAISE
Liberté Égalité Fraternité

METEO FRANCE
À VOS CÔTÉS, DANS UN CLIMAT QUI CHANGE

Bulletin d'estimation du risque d'avalanche

(valable en dehors des pistes balisées et ouvertes)

MASSIF : Champsaur

Rédigé le dimanche 8 mars 2026 à 16h

Conditions nivo-météo des 7 derniers jours

	lun. 02/03				mar. 03/03				mer. 04/03				jeu. 05/03				ven. 06/03				sam. 07/03				dim. 08/03			
	03h	09h	15h	21h	03h	09h	15h	21h	03h	09h	15h	21h	03h	09h	15h	21h	03h	09h	15h	21h	03h	09h	15h	21h	03h	09h	15h	21h
Météo																												
Vent (km/h)	15	15	15	15	15	10	10	10	10	5	10	10	15	20	30	30	35	40	30	35	35	20	30	30	30	20	25	30
à 3000m																												
Vent (km/h)	10	10	10	10	10	5	10	10	5	5	10	10	10	15	15	20	25	25	20	25	20	0	10	15	15	10	15	20
à 2000m																												

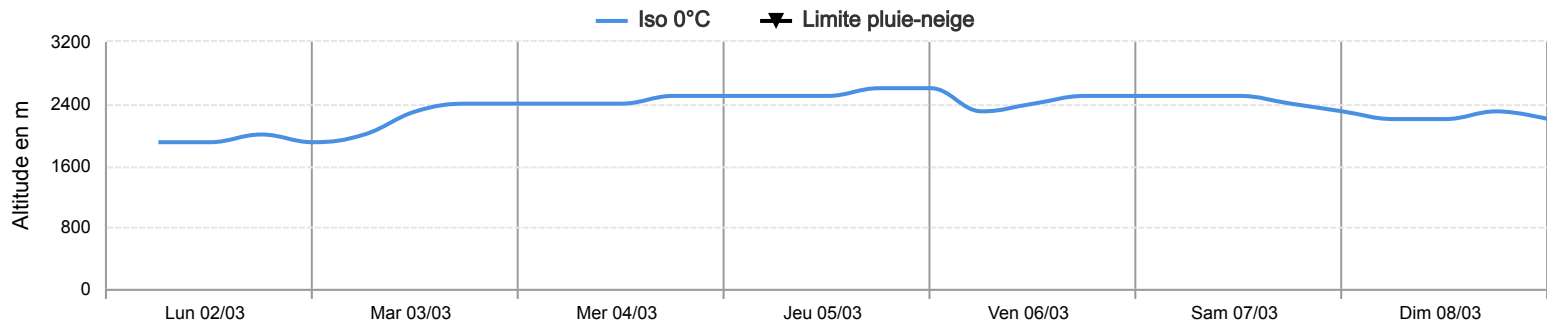

Neige fraîche à 06h

lun. 02/03	mar. 03/03	mer. 04/03	jeu. 05/03	ven. 06/03	sam. 07/03
0 cm	0 cm	0 cm	0 cm	0 cm	0 cm

Risque d'avalanche	lun. 02/03	mar. 03/03	mer. 04/03	jeu. 05/03	ven. 06/03	sam. 07/03	dim. 08/03
	2	2	2	2	2	2	2

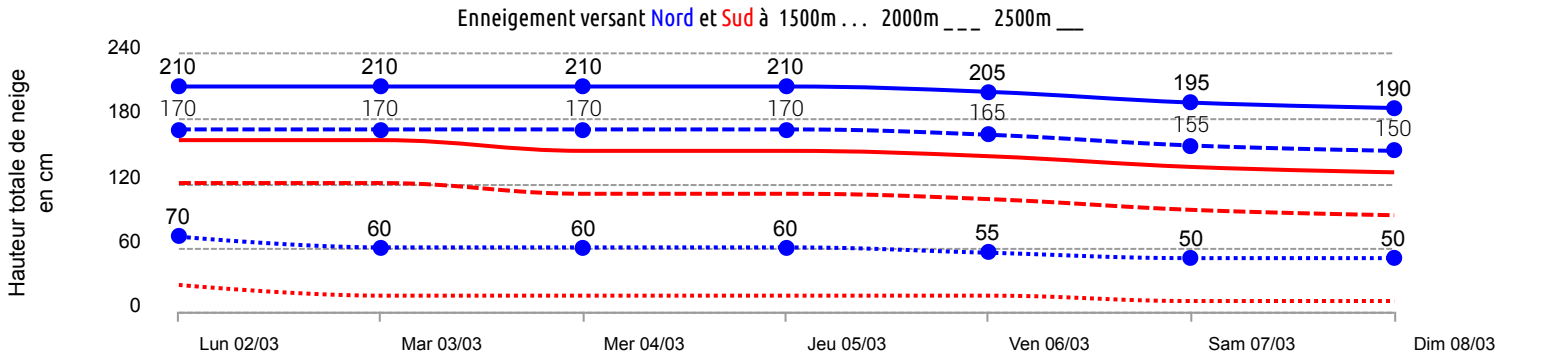

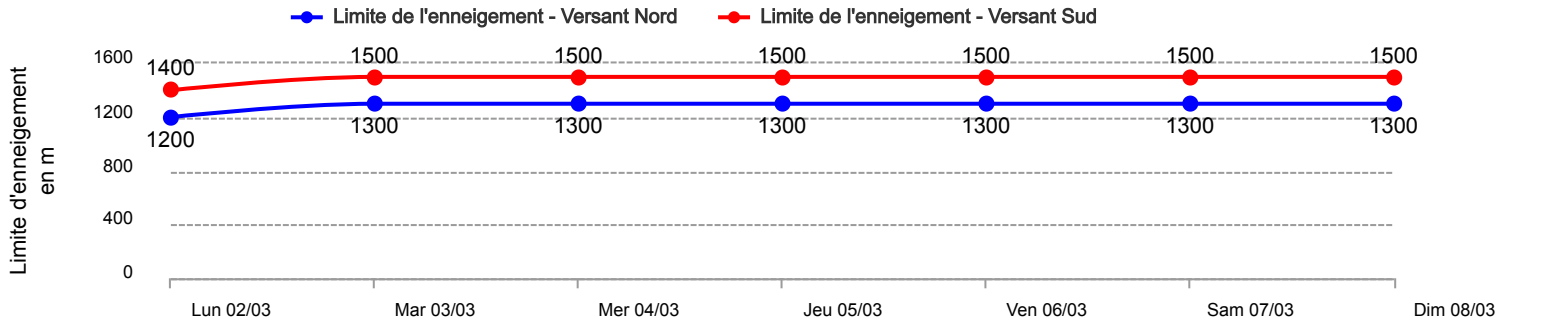

Pour consulter la vigilance en cours, veuillez vous rendre sur le site https://vigilance.meteofrance.fr/fr

Météo-France - 73 avenue de Paris, 94165 Saint-Mandé cedex - Contact : contact@meteo.fr

Rédigé par Météo-France avec la contribution des observateurs du réseau nivo-météorologiques. Partenariat : ANMSM (Maires de Stations de Montagne), DSF (Domaines Skiables de France), ADSP (Directeurs de Pistes et de la Sécurité des Stations de Sports d'Hiver) et autres acteurs de la montagne.

Bulletin neige & avalanches par téléphone au
0 892 68 10 20 Service 0,35 € / min + prix appel