Bulletin d'estimation du risque d'avalanche
(valable en dehors des pistes balisées et ouvertes)

MASSIF : Haute-Maurienne

Rédigé le dimanche 8 mars 2026 à 16h

Estimation des risques pour le : LUNDI 09 MARS

MANTEAU PRINTANIER : PLUTÔT STABLE LE MATIN, HUMIDIFICATION MARQUÉE ENSUITE FACILITANT UN DÉPART

2

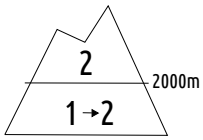

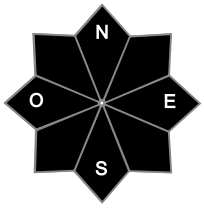

Au-dessus de 2000m indice de risque limité, plus bas indice faible évoluant en limité.

Départs spontanés : avalanches humides avec le réchauffement.

Déclenchements provoqués : rares plaques sur couches fragiles persistantes.

Indices de risque : 5 très fort - 4 fort - 3 marqué - 2 limité - 1 faible -- En noir : les pentes les plus dangereuses

Stabilité du manteau neigeux

Situation avalancheuse typique : neige humide couche fragile persistante

Déclenchements provoqués : **des couches fragiles persistantes** (grains anguleux) **sont enfouies de manière généralisée dans le manteau** (en tous versants, même en Sud de haute altitude). Leur **sollicitation est très peu probable** la majorité du temps mais devient possible :
- en **NW/N/NE, au-dessus de 2000 m** (neige froide en surface), dans quelques unes des zones moins enneigées (abords de crête/col, croupes dégarnis) car la couche fragile est alors plus proche de la surface. Taille 1 à 2 (petite à moyenne).
- en **E à S à W, après plusieurs heures de soleil**, lorsque l'enfoncement dans la neige humide devient important, facilitant la sollicitation d'une couche fragile enfouie. Taille 2 (moyenne), plus rarement 3 (grande).

Départs spontanés : **Rare avalanche de neige humide** dans les **pentes ayant chauffées plusieurs heures au soleil**. Avalanche de taille 1 à 2 (petite à moyenne), rarement 3 (grande) avec cassure linéaire si l'humidification atteint une vielle couche fragile de grains anguleux (plutôt en E/O mais aussi en S de haute altitude).

Qualité de la neige

Enneigement : légèrement excédentaire pour la saison en moyenne montagne, mais en train de devenir déficitaire en basse montagne et en versant Sud. Et très déficitaire en haute montagne près de la crête frontalière, voire carrément absent de certains cols ou faces très exposées au vent.
Limite skiable : encore skiable dès 1100/1200 m dans les prairies orientées nord, plutôt 1500/1600 m en sud pas trop raide.
Qualité de la neige :
- Sud/Est/Ouest : conditions de printemps avec un bon regel le matin, ensuite la neige "décaille" en suivant la course du soleil (parfois lentement voire mal dans les secteurs soumis au foehn), offrant du bon ski lorsque l'horaire est adapté à l'orientation.
- Nord suffisamment haut ou pentu (à partir de 2000/2100 m) : on peut trouver de la vieille poudre (grain à face plane) agréable à skier aux moyennes altitudes. En haute montagne et particulièrement dans les secteurs frontaliers, le vent a fortement travaillé le manteau, où la neige est dure (glissante) et les rochers affleurent souvent.

Aperçu météo pour le lundi 09 mars

nuit	matin	après-midi	soir

Beau en début de journée, se couvrant en cours d'après-midi. Lombarde se levant timidement dans les secteurs exposés.

Pluie-Neige				1 400 m
Iso 0 °C	1 900 m	2 000 m	2 200 m	1 700 m
Vent 2500 m	← 15 km/h	↖ 15 km/h	← 20 km/h	← 20 km/h
Vent 3500 m	↖ 15 km/h	↖ 10 km/h	↖ 15 km/h	↖ 25 km/h

Épaisseur de neige hors-piste

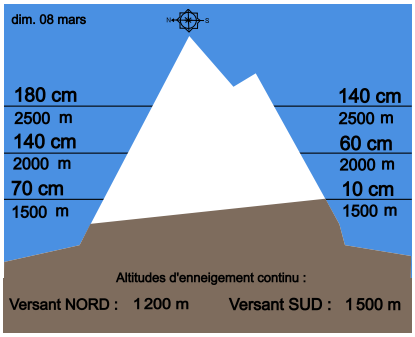

Précipitations à 1800 m

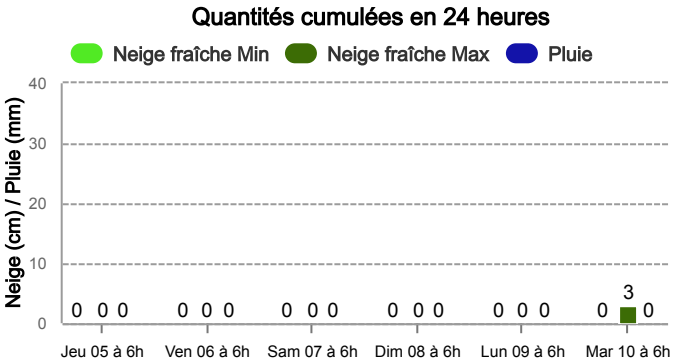

Tendance du mardi 10 mars

2 **Indice de risque limité**

Risque stationnaire. Mauvais regel puis journée voilée à nuageuse (et rares averses), quelques départs humides possibles.

Pour consulter la vigilance en cours, veuillez vous rendre sur le site https://vigilance.meteofrance.fr/fr

Météo-France - 73 avenue de Paris, 94165 Saint-Mandé cedex - Contact : contact@meteo.fr

Rédigé par Météo-France avec la contribution des observateurs du réseau nivo-météorologiques. Partenariat : ANMSM (Maires de Stations de Montagne), DSF (Domaines Skiables de France), ADSP (Directeurs de Pistes et de la Sécurité des Stations de Sports d'Hiver) et autres acteurs de la montagne.

Bulletin neige & avalanches par téléphone au
0 892 68 10 20 Service 0,35 € / min + prix appel

RÉPUBLIQUE FRANÇAISE
Liberté Égalité Fraternité

METEO FRANCE
À VOS CÔTÉS, DANS UN CLIMAT QUI CHANGE

Bulletin d'estimation du risque d'avalanche
(valable en dehors des pistes balisées et ouvertes)
MASSIF : Haute-Maurienne

Rédigé le dimanche 8 mars 2026 à 16h

Conditions nivo-météo des 7 derniers jours

	lun. 02/03				mar. 03/03				mer. 04/03				jeu. 05/03				ven. 06/03				sam. 07/03				dim. 08/03			
	03h	09h	15h	21h	03h	09h	15h	21h	03h	09h	15h	21h	03h	09h	15h	21h	03h	09h	15h	21h	03h	09h	15h	21h	03h	09h	15h	21h
Météo																												
Vent (km/h)	20	25	25	20	15	10	10	10	10	10	10	10	15	20	20	25	30	35	30	30	25	30	25	25	20	15	15	15
à 3500m																												
Vent (km/h)	15	20	20	15	10	5	5	5	5	5	5	5	15	20	20	25	30	30	25	25	20	25	20	15	20	15	15	15
à 2500m																												

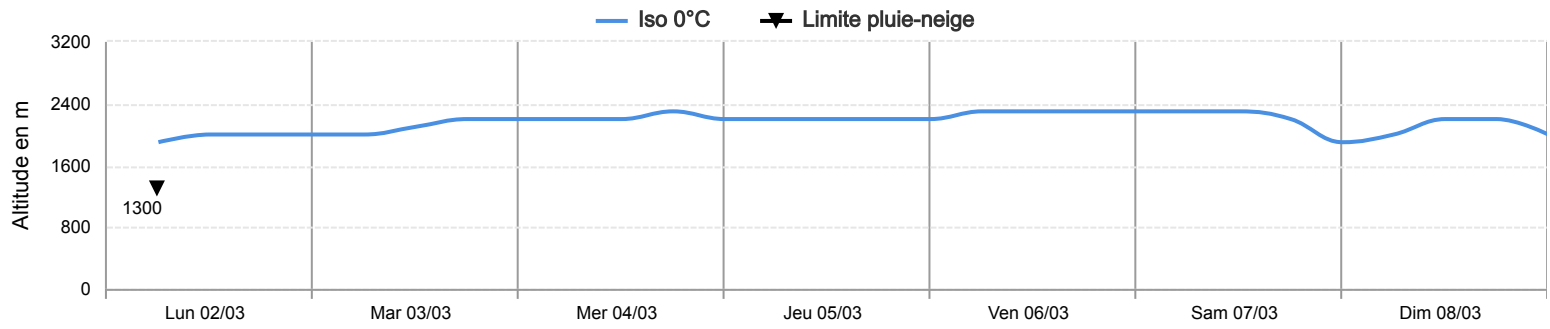

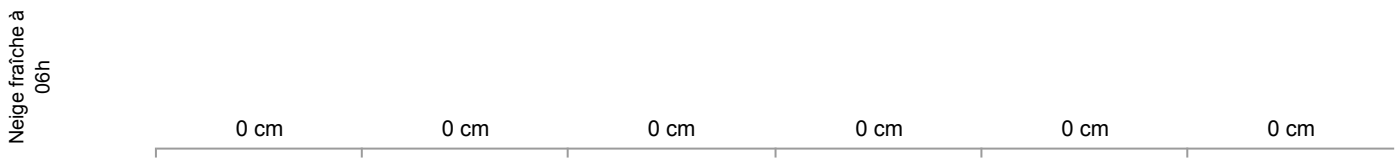

Risque d'avalanche	lun. 02/03	mar. 03/03	mer. 04/03	jeu. 05/03	ven. 06/03	sam. 07/03	dim. 08/03
	3	3	2	2	2	2	2

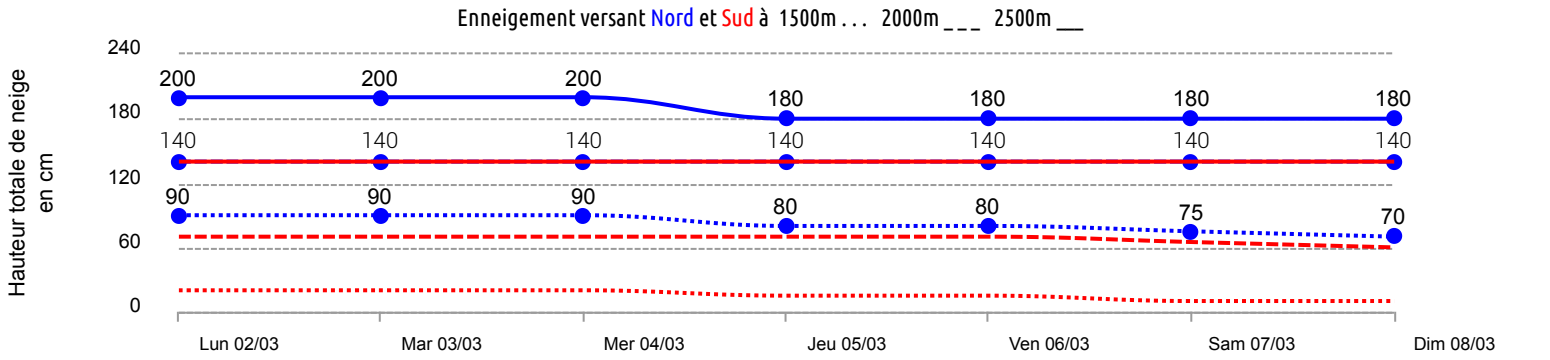

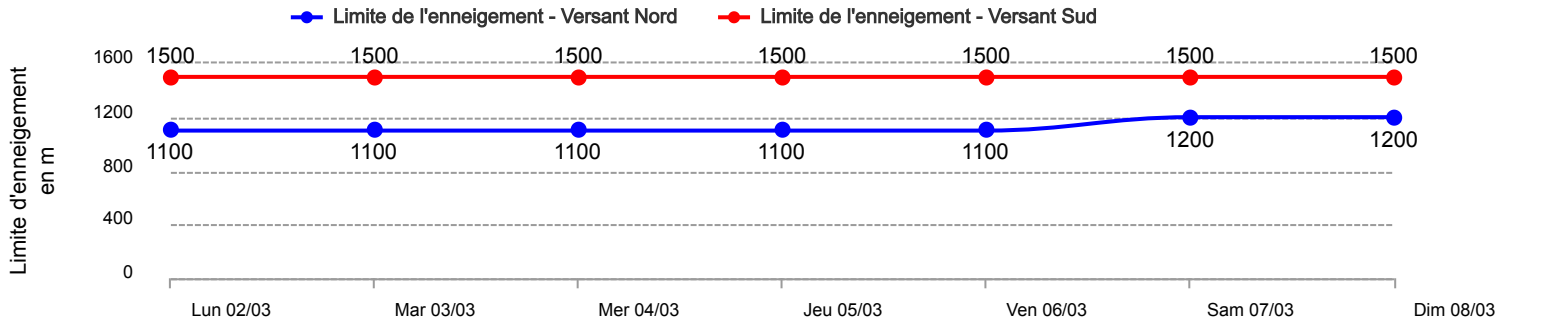

Pour consulter la vigilance en cours, veuillez vous rendre sur le site https://vigilance.meteofrance.fr/fr

Météo-France - 73 avenue de Paris, 94165 Saint-Mandé cedex - Contact : contact@meteo.fr

Rédigé par Météo-France avec la contribution des observateurs du réseau nivo-météorologiques. Partenariat : ANMSM (Maires de Stations de Montagne), DSF (Domaines Skiables de France), ADSP (Directeurs de Pistes et de la Sécurité des Stations de Sports d'Hiver) et autres acteurs de la montagne.

Bulletin neige & avalanches par téléphone au
0 892 68 10 20 Service 0,35 € / min + prix appel