Bulletin d'estimation du risque d'avalanche
(valable en dehors des pistes balisées et ouvertes)

MASSIF : Pays-Basque

Rédigé le dimanche 8 mars 2026 à 16h

Estimation des risques pour le : LUNDI 09 MARS

CONJUGAISON DE NEIGE HUMIDE ET DE NEIGE RECENTE.

2

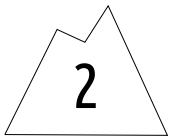

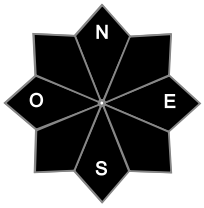

Indice de risque limité.

Départs spontanés : en neige récente et en neige humide.

Déclenchements provoqués : dans la neige récente.

Indices de risque : 5 très fort - 4 fort - 3 marqué - 2 limité - 1 faible -- En noir : les pentes les plus dangereuses

Stabilité du manteau neigeux

Situation avalancheuse typique : neige humide avalanches de fond

Départs spontanés :
- en **neige récente** : départs ponctuels près des rochers de coulées ou petites avalanches en pentes raides, en neige récente tombée ce dimanche et celle attendue lundi après-midi.
- en **neige humide** et souvent sous forme de **départs ponctuels près des rochers** de la **vieille neige lourde** en place, et de la **neige récente tombée dimanche s'humidifiant** rapidement dans les pentes ensoleillées de la matinée. Avalanches généralement de **taille 1 à 2.**

Plus rares et très localisée, une avalanche de **taille 2 à 3 possible** avec le **départ d'une avalanche de fond** partant d'une **accumulation** présente en altitude, emportant la **totalité du manteau neigeux** humide et lourd encore en place en contrebas, notamment près des **ruptures de pentes ou au niveau d'une fissure**.

Déclenchements provoqués : déclenchement **aisé pour un skieur ou randonneur** de **coulée ou petite avalanche** :
- de neige récente en **pentes raides**, plutôt **versants ombragés en matinée**, **tous versants l'après-midi avec les nouvelles averses de neige**,
- de la neige récente s'**alourdissant dans les pentes raides ensoleillées de la matinée**.

Très localement et sur le **haut du massif** (secteur Pic d'Anie notamment), déclenchement possible d'une **avalanche de taille 2** au niveau d'une **accumulation** encore en place (combe encore chargée par exemple).

Autres : ponts de neige et corniches encore en place fragiles au soleil de la matinée.

Qualité de la neige

Enneigement : aspect hivernal ce lundi matin sur l'ensemble du massif, avec un saupoudrage dès 1400/1500m, plus épais au-dessus, mais restant hétérogène près des sommets, cols et crêtes, dégarnis en particulier en versants Ouest. Combes plus chargées et corniches encore en place.
Limites skiables : à partir de 1500/1600m en versants froids, plutôt 1700m en versants Sud, mais sans sous-couche en dessous de 1800/1900m.
État de la neige : couche de neige fraîche au petit matin, tombée sans vent au-dessus de 1400/1500m ce dimanche, s'humidifiant au soleil, restant sèche et meuble à l'ombre.
Quelques centimètres de neige fraîche, restant sèche et meuble, se rajouteront sous les averses de l'après-midi à partir de 1700m.

Aperçu météo pour le lundi 09 mars

	nuit	matin	après-midi	soir

Beau temps sec et ensoleillé le matin, averses de neige l'après-midi, vent faible.

Pluie-Neige	1 700 m			
Iso 0 °C	2 000 m	1 900 m	2 000 m	1 900 m
Vent 1000 m	↑ 10 km/h	↑ 10 km/h	↻ 5 km/h	↑ 5 km/h
Vent 2000 m	↗ 25 km/h	↑ 25 km/h	↑ 20 km/h	↑ 20 km/h

Épaisseur de neige hors-piste

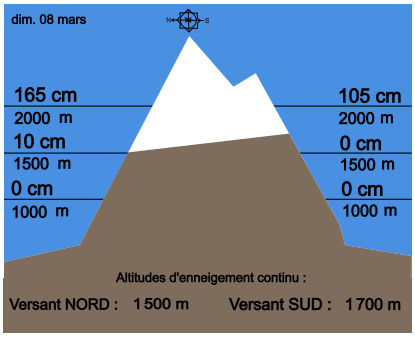

Précipitations à 1800 m

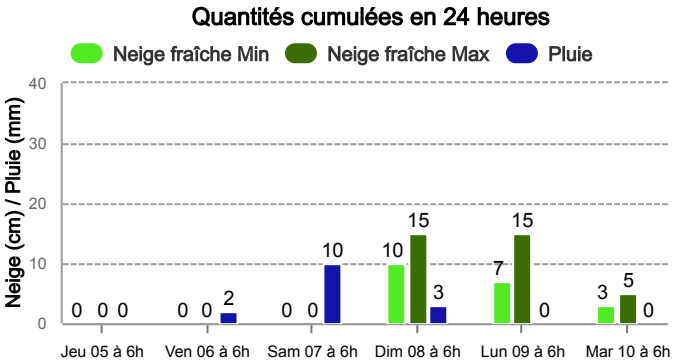

Tendance du mardi 10 mars

1

Indice de risque faible

Cycle gel/dégel plus efficace dans la nuit de lundi à mardi, beau mardi matin, rares averses mardi après-midi : le niveau de risque devrait décroître.

Pour consulter la vigilance en cours, veuillez vous rendre sur le site https://vigilance.meteofrance.fr/fr

Météo-France - 73 avenue de Paris, 94165 Saint-Mandé cedex - Contact : contact@meteo.fr

Rédigé par Météo-France avec la contribution des observateurs du réseau nivo-météorologiques. Partenariat : ANMSM (Maires de Stations de Montagne), DSF (Domaines Skiables de France), ADSP (Directeurs de Pistes et de la Sécurité des Stations de Sports d'Hiver) et autres acteurs de la montagne.

Bulletin neige & avalanches par téléphone au
0 892 68 10 20 Service 0,35 € / min + prix appel

RÉPUBLIQUE FRANÇAISE
Liberté Égalité Fraternité

METEO FRANCE
À VOS CÔTÉS, DANS UN CLIMAT QUI CHANGE

Bulletin d'estimation du risque d'avalanche
(valable en dehors des pistes balisées et ouvertes)

MASSIF : Pays-Basque

Rédigé le dimanche 8 mars 2026 à 16h

Conditions nivo-météo des 7 derniers jours

	lun. 02/03				mar. 03/03				mer. 04/03				jeu. 05/03				ven. 06/03				sam. 07/03				dim. 08/03			
	03h	09h	15h	21h	03h	09h	15h	21h	03h	09h	15h	21h	03h	09h	15h	21h	03h	09h	15h	21h	03h	09h	15h	21h	03h	09h	15h	21h
Météo																												
Vent (km/h)	85	80	80	70	50	25	15	20	25	25	55	70	70	60	45	35	30	25	25	15	20	25	30	25	40	35	30	15
à 2000m	↑	↑	↑	↑	↑	↑	↙	↑	↑	↑	↑	↑	↑	↑	↓	↙	↙	↓	↓	↙	↓	↖	↙	↑	↑	↑	↑	↑
Vent (km/h)	60	55	45	40	35	20	15	10	15	15	25	50	50	35	25	20	15	15	15	5	5	10	10	5	10	5	5	5
à 1000m	↑	↑	↑	↑	↑	↑	←	↑	↑	↑	↖	↑	↑	↑	↓	↓	↘	↓	↓	↻	↻	↓	↻	↑	↑	↻	↻	↑

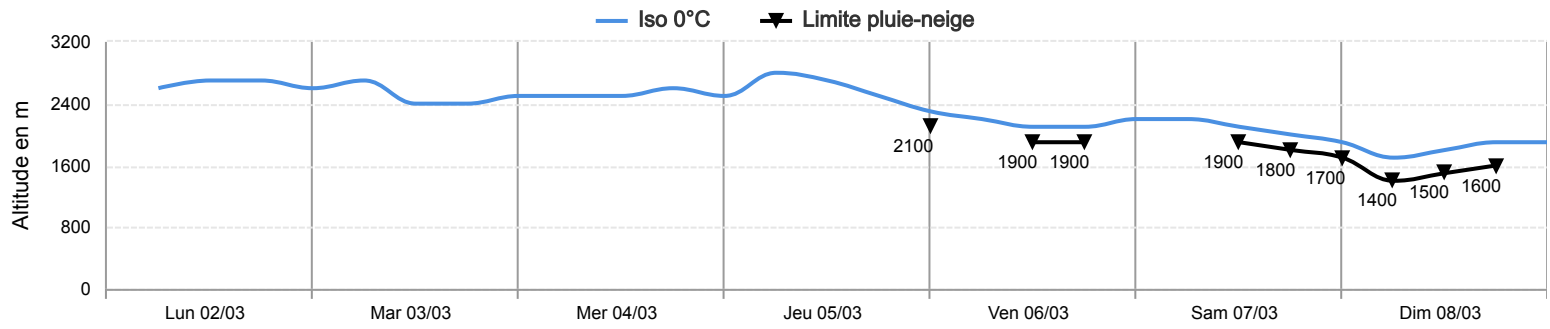

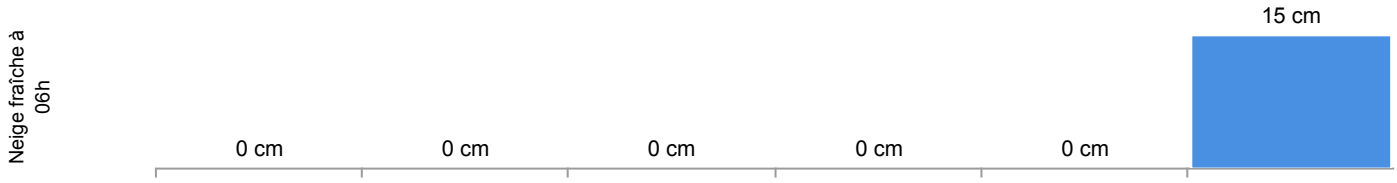

Risque d'avalanche	lun. 02/03	mar. 03/03	mer. 04/03	jeu. 05/03	ven. 06/03	sam. 07/03	dim. 08/03
	1	2	2	2	2	2	2

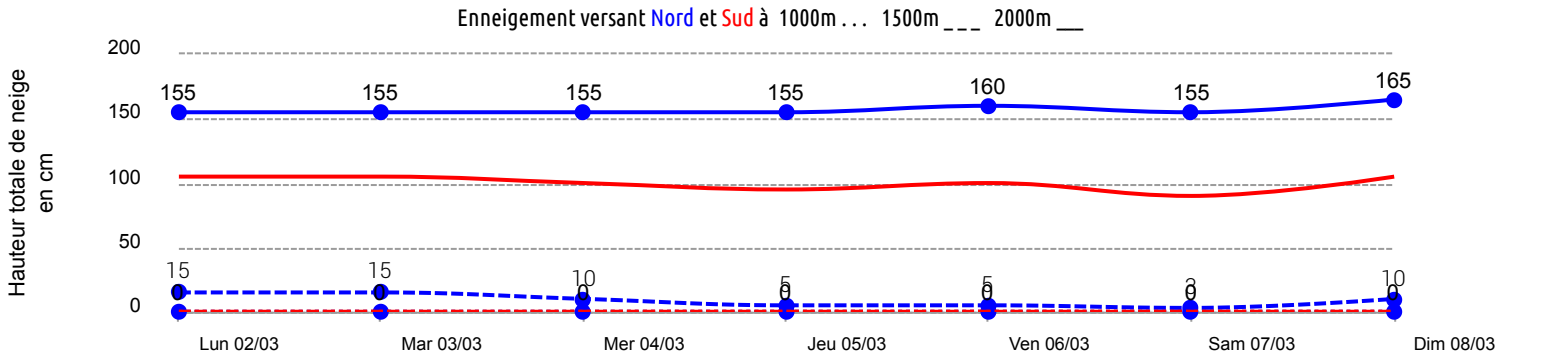

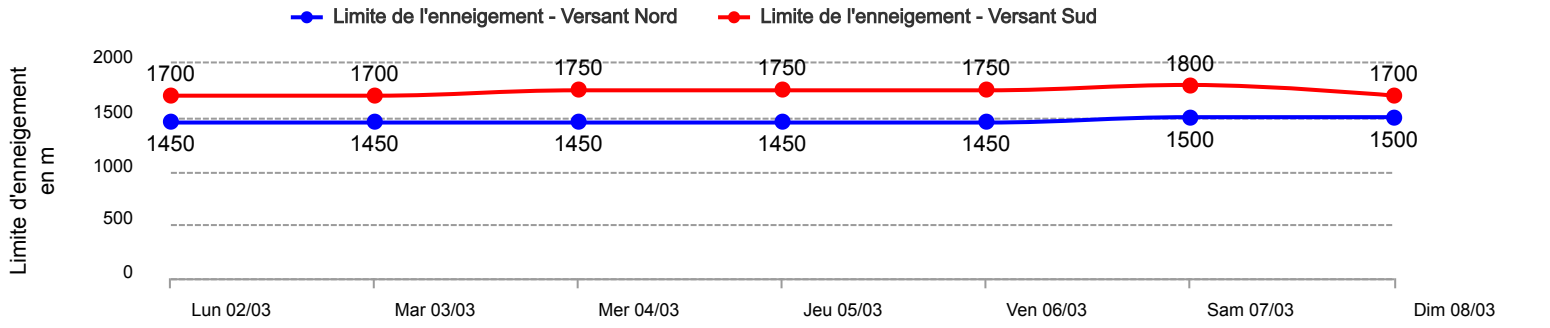

Pour consulter la vigilance en cours, veuillez vous rendre sur le site https://vigilance.meteofrance.fr/fr

Météo-France - 73 avenue de Paris, 94165 Saint-Mandé cedex - Contact : contact@meteo.fr

Rédigé par Météo-France avec la contribution des observateurs du réseau nivo-météorologiques. Partenariat : ANMSM (Maires de Stations de Montagne), DSF (Domaines Skiables de France), ADSP (Directeurs de Pistes et de la Sécurité des Stations de Sports d'Hiver) et autres acteurs de la montagne.

Bulletin neige & avalanches par téléphone au
0 892 68 10 20 Service 0,35 € / min + prix appel