Bulletin d'estimation du risque d'avalanche
(valable en dehors des pistes balisées et ouvertes)

MASSIF : Vercors

Rédigé le dimanche 8 mars 2026 à 16h

Estimation des risques pour le : LUNDI 09 MARS

MANTEAU NEIGEUX BIEN STABILISÉ.

1

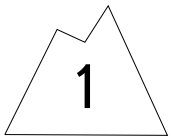

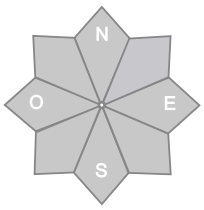

Indice de risque faible.

Départs spontanés : Rare plaque de fond.

Déclenchements provoqués : Rares.

Indices de risque : 5 très fort - 4 fort - 3 marqué - 2 limité - 1 faible -- En noir : les pentes les plus dangereuses

Stabilité du manteau neigeux

Situation avalancheuse typique : avalanches de fond

Les dernières chutes de neige sont déjà loin. Le manteau neigeux a beaucoup évolué et s'est fortement consolidé depuis.
Départs spontanés : après un bon regel nocturne, l'humidification du manteau neigeux ne devrait être que superficielle lundi. Malgré tout, on ne peut pas exclure le risque qu'une fissure de reptation vienne à céder, emportant toute la neige en place jusqu'au sol (avalanche de taille 1 à 2).
Déclenchements provoqués : Peu probables, sauf éventuellement une coulée de neige humide partant sous les skis en cas d'horaire tardif.

Qualité de la neige

Qualification de l'enneigement : L'enneigement est très bon dans les versants ombragés au dessus de 1600 m

Limites skiables : vers 1300/1700 m.

Qualité de la neige lundi : Manteau neigeux de type printanier avec une neige durcie par le regel nocturne, s'humidifiant assez superficiellement en journée.

Aperçu météo pour le lundi 09 mars

	nuit	matin	après-midi	soir
Pluie-Neige	1 800 m			
Iso 0 °C	2 100 m	2 100 m	2 100 m	2 000 m
Vent 1500 m	↑ 20 km/h	↑ 20 km/h	↑ 25 km/h	↖ 20 km/h
Vent 2000 m	↑ 25 km/h	↑ 25 km/h	↑ 25 km/h	↑ 25 km/h

Épaisseur de neige hors-piste

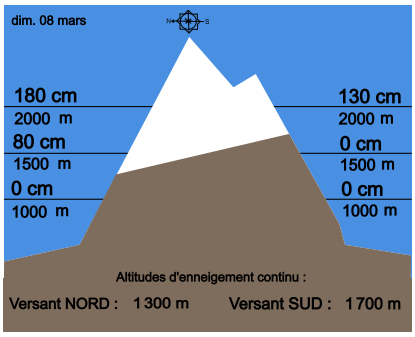

Précipitations à 1800 m

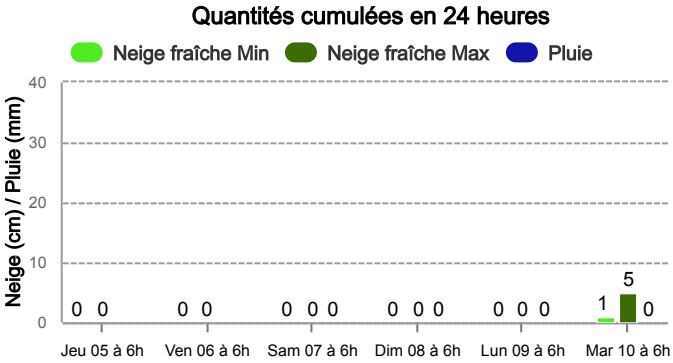

Tendance du mardi 10 mars

1

Indice de risque faible

Les faibles quantités de neige attendues mardi ne devraient pas modifier significativement le risque d'avalanche.

Pour consulter la vigilance en cours, veuillez vous rendre sur le site https://vigilance.meteofrance.fr/fr

Météo-France - 73 avenue de Paris, 94165 Saint-Mandé cedex - Contact : contact@meteo.fr

Rédigé par Météo-France avec la contribution des observateurs du réseau nivo-météorologiques. Partenariat : ANMSM (Maires de Stations de Montagne), DSF (Domaines Skiables de France), ADSP (Directeurs de Pistes et de la Sécurité des Stations de Sports d'Hiver) et autres acteurs de la montagne.

Bulletin neige & avalanches par téléphone au 0 892 68 10 20 Service 0,35 € / min + prix appel

RÉPUBLIQUE FRANÇAISE
Liberté Égalité Fraternité

METEO FRANCE
À VOS CÔTÉS, DANS UN CLIMAT QUI CHANGE

Bulletin d'estimation du risque d'avalanche
(valable en dehors des pistes balisées et ouvertes)

MASSIF : Vercors

Rédigé le dimanche 8 mars 2026 à 16h

Conditions nivo-météo des 7 derniers jours

	lun. 02/03				mar. 03/03				mer. 04/03				jeu. 05/03				ven. 06/03				sam. 07/03				dim. 08/03			
	03h	09h	15h	21h	03h	09h	15h	21h	03h	09h	15h	21h	03h	09h	15h	21h	03h	09h	15h	21h	03h	09h	15h	21h	03h	09h	15h	21h
Météo																												
Vent (km/h)	55	55	50	45	25	15	15	5	10	15	15	10	15	25	20	15	25	20	20	15	20	5	10	10	10	20	20	15
à 2000m																												
Vent (km/h)	50	45	35	20	20	15	15	5	10	10	15	10	10	15	10	10	15	5	10	5	5	5	5	5	10	10	20	15
à 1500m																												

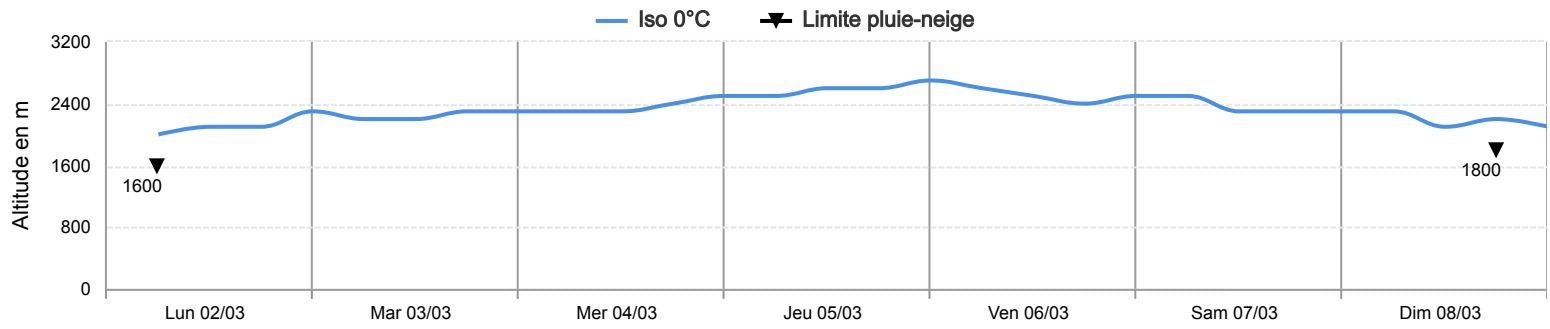

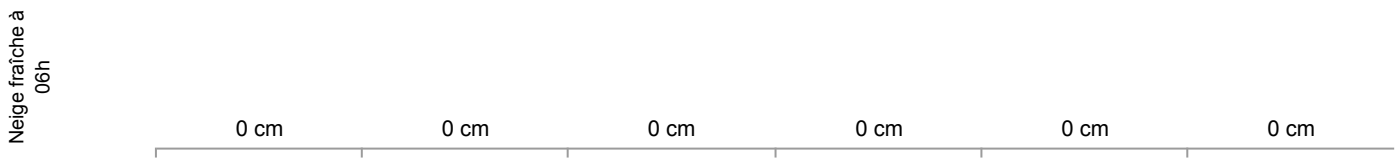

Risque d'avalanche	lun. 02/03	mar. 03/03	mer. 04/03	jeu. 05/03	ven. 06/03	sam. 07/03	dim. 08/03
	2	2	2	2	2	2	1

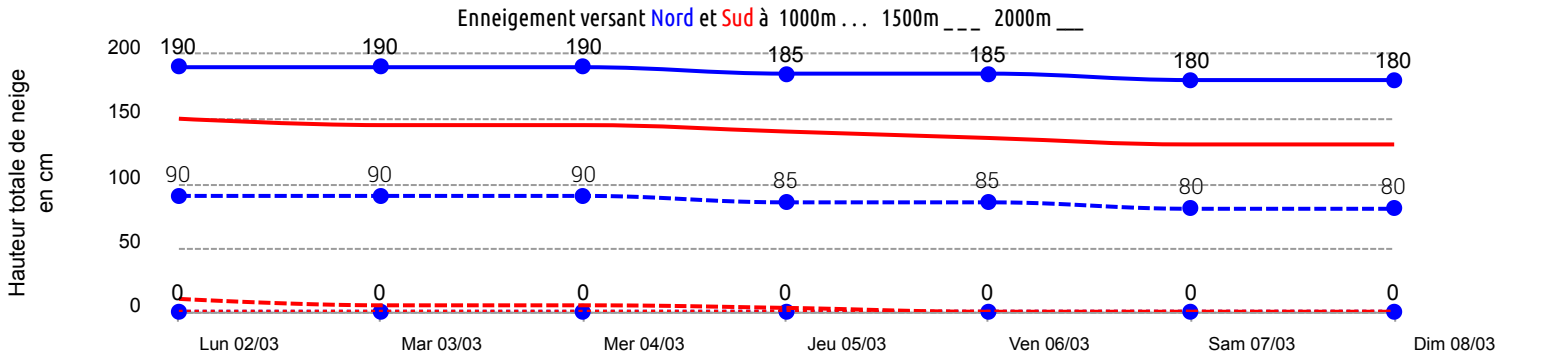

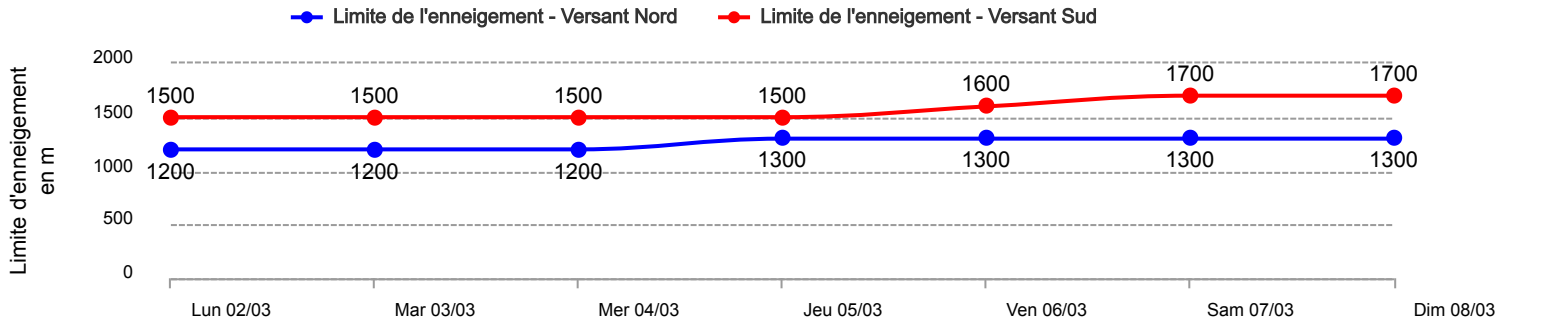

Pour consulter la vigilance en cours, veuillez vous rendre sur le site https://vigilance.meteofrance.fr/fr

Météo-France - 73 avenue de Paris, 94165 Saint-Mandé cedex - Contact : contact@meteo.fr

Rédigé par Météo-France avec la contribution des observateurs du réseau nivo-météorologiques. Partenariat : ANMSM (Maires de Stations de Montagne), DSF (Domaines Skiables de France), ADSP (Directeurs de Pistes et de la Sécurité des Stations de Sports d'Hiver) et autres acteurs de la montagne.

Bulletin neige & avalanches par téléphone au
0 892 68 10 20 Service 0,35 € / min + prix appel