GOBIERNO DE ESPAÑA
VICEPRESIDENCIA TERCERA DEL GOBIERNO
MINISTERIO PARA LA TRANSICIÓN ECOLÓGICA Y EL RETO DEMOGRÁFICO

Boletín de información nivológica y de peligro de aludes

Pirineo Catalán

aemet Agencia Estatal de Meteorología

lunes, 9 de marzo de 2026

Pronóstico hasta las 24 horas del martes, día 10 de marzo

(Válido fuera de pistas de esquí balizadas y abiertas)

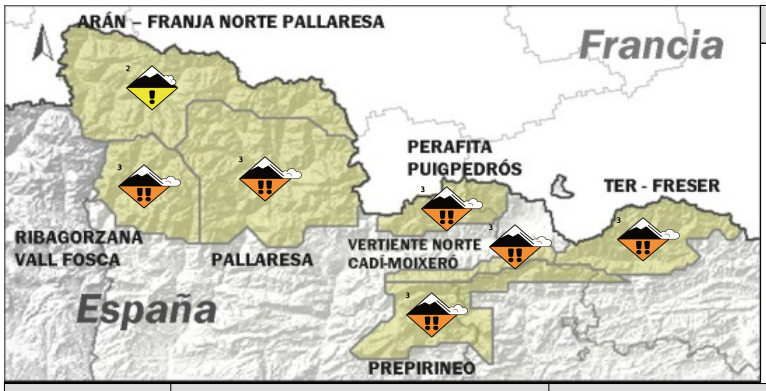

Problemas de aludes

- Nieve reciente
- Nieve húmeda
- Placas de viento

Macizo	Peligro	Problemas de aludes, cota, orientación, tamaño	Innivación observada (m)
Arán - Franja norte Pallaresa	2 / 2 **Limitado**	**Nieve húmeda** 2200 N O E S 2 **Placas de viento** 2200 N O E S 2	2026-03-09 N S Cota más baja caras N
Ribagorzana - Vall Fosca	3 / 3 2200 / 2 **Notable**	**Nieve húmeda** 2200 N O E S 2 **Placas de viento** 2200 N O E S 2	2026-03-09 N S Cotas medias
Pallaresa	3 / 3 2200 / 2 **Notable**	**Nieve húmeda** 2200 N O E S 2 **Placas de viento** 2200 N O E S 2	2026-03-09 N S Cotas medias

AEMET. Se autoriza la reproducción de su contenido citando la fuente.

Boletín de información nivológica y de peligro de aludes

Pirineo Catalán

Perafita - Puigpedrós	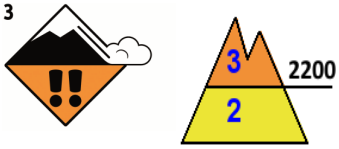 **Notable**	**Nieve reciente**	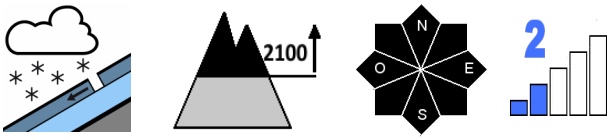	2026-03-09
		Placas de viento	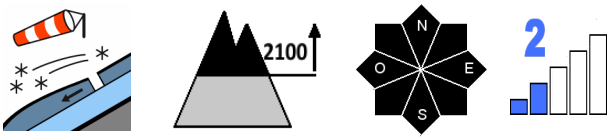	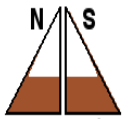 Cotas medias
Ter - Freser	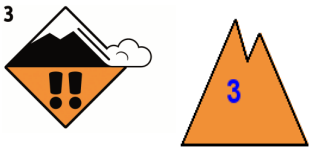 **Notable**	**Nieve reciente**	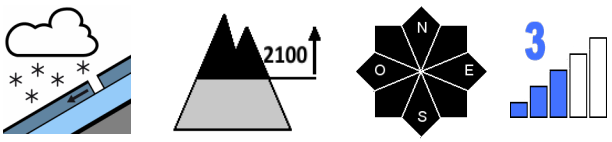	2026-03-09
		Placas de viento	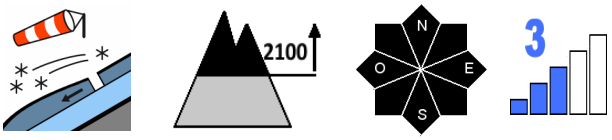	 Cotas medias
Vertiente norte Cadí - Moixeró	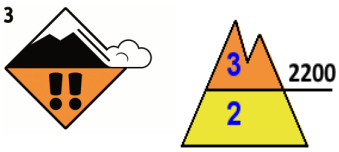 **Notable**	**Nieve reciente**	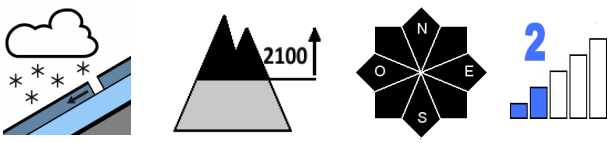	2026-03-09
		Placas de viento	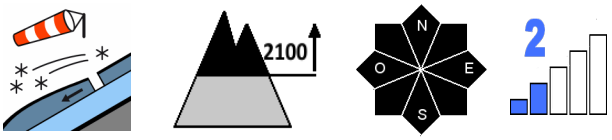	 Cotas medias
Prepirineo	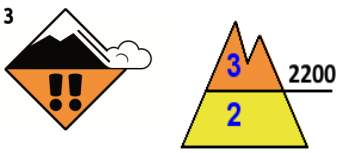 **Notable**	**Nieve reciente**	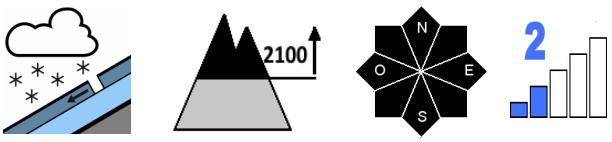	2026-03-09
		Placas de viento	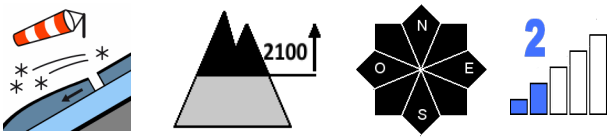	 Cotas medias

Estado del manto y observaciones recientes

Ayer se registraron algunas precipitaciones, que han sido en forma de nieve a partir de unos 1400 metros aproximadamente, depositando desde unos pocos centímetros hasta unos 10-15 cm de nieve nueva en algunos enclaves de cotas altas. Estas nevadas se han añadido a las de días pasados, que depositaron cantidades importantes de nieve reciente en cotas altas del área oriental, siendo más modestas en el resto de los macizos. El manto es continuo desde medianías en toda el área, aunque localmente, en enclaves menos soleados, la nieve sigue presente desde cotas bajas. Pese a estos condicionantes la situación sigue siendo

AEMET. Se autoriza la reproducción de su contenido citando la fuente.

excepcional en cuanto a cobertura nivosa, con espesores en máximos de la serie en numerosas zonas, superando los 120 a 200 cm por encima de los 2100 metros.

En cotas medias y bajas, así como en solanas a mayor altitud, el manto presenta características primaverales y está humedecido en profundidad, y las heladas tienden a encostrarlo durante las primeras horas. En altitudes superiores, la nieve se mantiene más seca, venteada y aún podríamos encontrar en umbrías de la alta montaña estratos débiles enterrados a gran profundidad, generalmente inactivos.

Evolución del manto y peligro de aludes para el martes, día 10

Problema de nieve reciente y de placas de viento en cotas altas. Problema de nieve húmeda y deslizamientos basales en medianías y cotas bajas.

A lo largo de la tarde de hoy y del día de mañana se espera alguna precipitación débil y ocasional, que en todo caso podría sumar algún centímetro de nieve reciente en algunos enclaves de cotas altas. Este cese en las precipitaciones, llevará a que las purgas de nieve reciente sean cada vez menos probables y frecuentes con el transcurso del día, estabilizándose progresivamente dicho problema. Cabe destacar que en los macizos orientales, donde las acumulaciones de nieve reciente son muy significativas, todavía podrá darse algún alud de este tipo, de tamaño pequeño (1, capaz de desestabilizar a una persona) o mediano (2, capaz de enterrar a una persona), sin descartar todavía alguno de dimensiones localmente mayores en el Ripollès.

En la alta montaña se seguirán formando algunas nuevas placas de viento, preferentemente en orientaciones oeste, norte y este, que vendrán a sumarse a otras ya existentes en todas las orientaciones y que permanecen aún activas. Estas estructuras podrán fracturarse ante sobrecargas débiles, como es el paso de un esquiador, dando lugar a aludes de dimensiones pequeñas o medianas en los macizos occidentales, y pudiendo alcanzar el tamaño grande en los macizos orientales (3, capaz de enterrar a un grupo de personas). Tampoco se descarta que pueda reactivarse alguna capa débil persistente, especialmente en zonas de manto más delgado o erosionado, en cuyo caso también sería posible el desencadenamiento de aludes de tamaño localmente grande.

En cotas medias y bajas el manto se encuentra muy húmedo hasta la base, por lo que serán muy probables los aludes de nieve húmeda, de tamaño pequeño o mediano, preferentemente en las solanas. La formación de costras de rehielo podrá aportar al manto cierta estabilidad temporal a primeras horas, que desaparecerá con la insolación y el calentamiento diurno. En superficies herbosas o de roca lisa serán probables los deslizamientos basales, capaces de arrastrar una gran cantidad de nieve y alcanzar el tamaño grande.

Predicción meteorológica para el martes, día 10

Nuboso o intervalos nubosos, con nubosidad baja, que podrá reducir localmente la visibilidad, y formación de nubosidad de evolución diurna desde las horas centrales. No se descartan lluvias o chubascos ocasionales, generalmente débiles, que serán más probables a partir del mediodía. Cota de nieve en torno a unos 1600-1800 metros, aproximadamente. Temperaturas mínimas con pocos cambios. Máximas sin cambios o en ligero ascenso. Heladas débiles o moderadas, que podrán ser localmente fuertes en cotas altas. Soplarán vientos generalmente flojos de dirección variable, predominando la componente sur en cotas altas.

AEMET. Se autoriza la reproducción de su contenido citando la fuente.

Datos en la atmósfera libre:

Altitud de la isoterma de 0 ºC: 2200 m
Altitud de la isoterma de -10 ºC: 3700 m

Viento a 1500 m: VRB 5 km/h
Viento a 3000 m: S 10 km/h

Evolución para el miércoles día 11

Nivel de peligro con pocos cambios.

Escala europea de peligro de aludes

Débil | Limitado | Notable | Fuerte | Muy Fuerte

Problemas de aludes

Nieve reciente | Placas de viento | Capas débiles persistentes | Nieve húmeda | Deslizamientos basales | Sin problema evidente

Nota1: Se recuerda que, siempre que haya nieve, la ausencia total de peligro no existe. Hay que tener presente que en circunstancias desfavorables, con aludes de tamaño 1 (alud pequeño o colada) y tamaño 2 (alud mediano), se pueden sufrir severos daños personales.

Nota2: Los BPA se elaboran en base a información meteorológica así como al estado del manto nivoso a través de sondeos puntuales. Se advierte a los usuarios de la variabilidad de esta información al extrapolarla a zonas extensas de montaña. Por ello, AEMET no se hace responsable de su uso para la toma de decisiones que conciernen a la seguridad personal, ni de los riesgos físicos o materiales de ellas derivadas.

AEMET. Se autoriza la reproducción de su contenido citando la fuente.