GOBIERNO DE ESPAÑA
VICEPRESIDENCIA TERCERA DEL GOBIERNO
MINISTERIO PARA LA TRANSICIÓN ECOLÓGICA Y EL RETO DEMOGRÁFICO

Boletín de información nivológica y de peligro de aludes

Pirineo Navarro y Aragonés

aemet Agencia Estatal de Meteorología

lunes, 9 de marzo de 2026 (corrección)

Pronóstico hasta las 24 horas del martes, día 10 de marzo

(Válido fuera de pistas de esquí balizadas y abiertas)

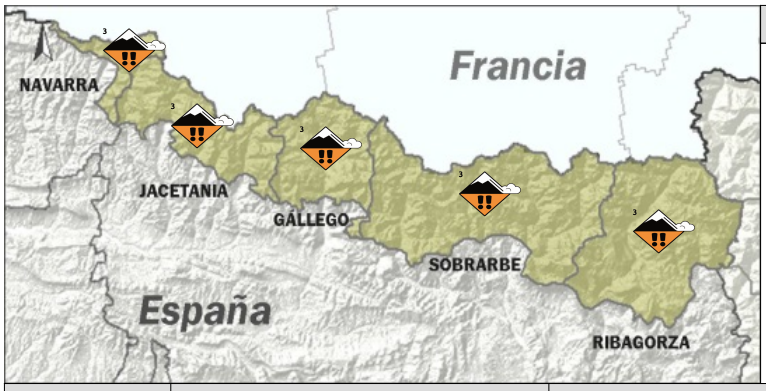

Problemas de aludes

Placas de viento

Deslizamientos basales

Macizo	Peligro	Problemas de aludes, cota, orientación, tamaño	Innivación observada (m)
Navarra	3 / 3 (2000) / 2 Notable	Placas de viento: 2200, N O E S, 2 Deslizamientos basales: 2200, N O E S, 2	2026-03-09 N S Cotas bajas
Jacetania	3 / 3 (2000) / 2 Notable	Placas de viento: 2200, N O E S, 2 Deslizamientos basales: 2200, N O E S, 2	2026-03-09 N S Cotas bajas
Gállego	3 / 3 (2000) / 2 Notable	Placas de viento: 2200, N O E S, 2 Deslizamientos basales: 2200, N O E S, 2	2026-03-09 N S Cotas bajas

AEMET. Se autoriza la reproducción de su contenido citando la fuente.

Boletín de información nivológica y de peligro de aludes

Pirineo Navarro y Aragonés

Sobrarbe	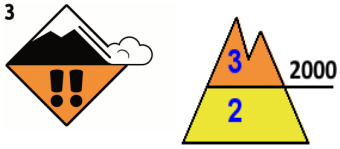 **Notable**	**Placas de viento** **Deslizamientos basales** 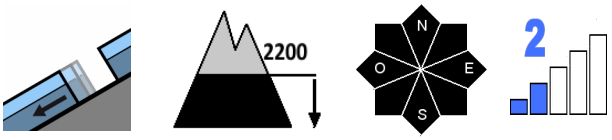	2026-03-09 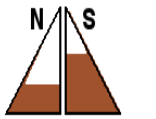 Cota más baja caras N
Ribagorza	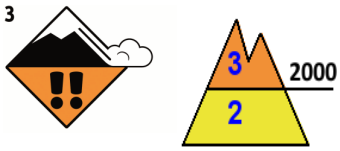 **Notable**	**Placas de viento** 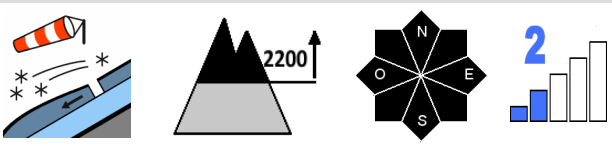 **Deslizamientos basales** 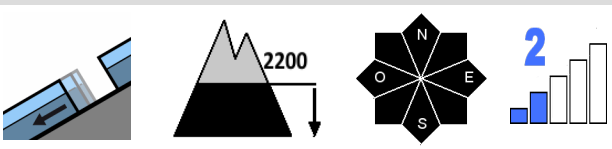	2026-03-09 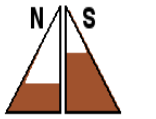 Cota más baja caras N

Estado del manto y observaciones recientes

Ayer se registraron algunas precipitaciones, que han sido en forma de nieve a partir de unos 1300-1400 metros aproximadamente, depositando desde unos pocos centímetros hasta unos 10-15 cm de nieve nueva en algunos enclaves. El manto vuelve a presentar algo de continuidad desde cotas bajas en algunas áreas. En medianías la nieve es abundante, con espesores que van incrementando conforme ascendemos, rondando los 120-160 cm a unos 1700- 1800 metros y pudiendo superar los 200 cm a unos 2100 metros, cantidades que pueden ser notablemente mayores en ventisqueros, hoyas y otras zonas propensas a la acumulación, donde se pueden llegar a alcanzar los 4 metros.

El manto está humedecido hasta su base en cotas medias y bajas, hasta los 2200 metros aproximadamente, normalmente con una capa de nieve reciente en superficie depositada durante las últimas nevadas, que ya se está humedeciendo. En cotas superiores, la nieve se presenta generalmente más seca y está muy venteada, observándose la presencia de placas de viento que descansan sobre los estratos de polvo sahariano depositados durante el episodio de calima de días pasados, a la vez que aflora la nieve marrón en las zonas erosionadas por el viento. En algunos casos existen capas de graupel acompañando a los estratos de polvo, como consecuencia de los chubascos de días pasados. Aún podemos encontrar en umbrías de la alta montaña estratos débiles ubicados a considerable profundidad, y que se encuentran, por lo general, inactivos.

Se han observado algunos deslizamientos basales de tamaño 2-2.5 por debajo de unos 2200 metros, así como algunos aludes de nieve húmeda de tamaño generalmente pequeño. También se han reportado purgas puntuales de nieve reciente en todas las orientaciones, y algunos aludes de placa pequeños en cotas altas.

AEMET. Se autoriza la reproducción de su contenido citando la fuente.

Evolución del manto y peligro de aludes para el martes, día 10

Problema de nieve reciente y de placas de viento en cotas altas. Problema de nieve húmeda y deslizamientos basales en medianías y cotas bajas.

A lo largo de la tarde de hoy y del día de mañana se espera alguna precipitación débil y ocasional, que en todo caso podría sumar algún centímetro de nieve reciente en algunos enclaves de cotas altas. Este cese en las precipitaciones, llevará a que las purgas de nieve reciente sean cada vez menos probables y frecuentes con el transcurso del día, estabilizándose progresivamente dicho problema.

En la alta montaña, los vientos de componente sur seguirán formando nuevas placas de viento, preferentemente en orientaciones oeste, norte y este, que vendrán a sumarse a otras ya existentes en todas las orientaciones y que permanecen aún activas. Estas estructuras podrán fracturarse ante sobrecargas débiles, como es el paso de un esquiador, dando lugar a aludes de dimensiones pequeñas (1, capaz de desestabilizar a una persona) o medianas (2, capaz de enterrar a una persona), por lo que se recomienda tomar precauciones si se va a transitar por la zona. Tampoco se descarta que pueda reactivarse alguna capa débil persistente, especialmente en zonas de manto más delgado o erosionado, en cuyo caso sería posible el desencadenamiento de aludes de tamaño localmente grande (3, capaz de enterrar a un grupo de personas).

En cotas medias y bajas, el manto se encuentra muy húmedo hasta la base, por lo que serán muy probables los aludes de nieve húmeda, de tamaño pequeño o mediano, preferentemente en las solanas. La formación de costras de rehielo podrá aportar al manto cierta estabilidad temporal, que desaparecerá con la insolación y el calentamiento diurno. En superficies herbosas o de roca lisa serán probables los deslizamientos basales, capaces de arrastrar una gran cantidad de nieve y alcanzar el tamaño grande.

Predicción meteorológica para el martes, día 10

Nuboso o intervalos nubosos, con nubosidad baja, que podrá reducir localmente la visibilidad, y formación de nubosidad de evolución diurna desde las horas centrales. No se descartan lluvias o chubascos ocasionales, generalmente débiles, que serán más probables a partir del mediodía. Cota de nieve en torno a unos 1500-1700 metros, aproximadamente. Temperaturas mínimas sin cambios o en ligero descenso, localmente moderado. Máximas en ligero o moderado ascenso. Heladas débiles o moderadas, que podrán ser localmente fuertes en cotas altas. Soplarán vientos flojos de dirección variable. En cotas altas y zonas expuestas soplará generalmente de componente sur, donde podrá ir acompañado de algún intervalo de moderado, sobre todo en Navarra y en la Jacaetania.

Datos en la atmósfera libre:

Altitud de la isoterma de 0 ºC: 2100 m
Altitud de la isoterma de -10 ºC: 3700 m

Viento a 1500 m: VRB 5 km/h
Viento a 3000 m: SE 10 km/h

AEMET. Se autoriza la reproducción de su contenido citando la fuente.

Evolución para el miércoles día 11

Nivel de peligro con pocos cambios.

(Información elaborada a partir de los datos recibidos de los refugios de Linza, Lizara, Panticosa, Góriz, Pineta, Estós, Angel Orús, Cap de Llauset y Belagua, de las estaciones de esquí de Formigal y Panticosa (lagos), de la estación de esquí de fondo de Llanos del Hospital y de Ordesa Pradera)

Escala europea de peligro de aludes

Débil | Limitado | Notable | Fuerte | Muy Fuerte

Problemas de aludes

Nieve reciente | Placas de viento | Capas débiles persistentes | Nieve húmeda | Deslizamientos basales | Sin problema evidente

Nota1: Se recuerda que, siempre que haya nieve, la ausencia total de peligro no existe. Hay que tener presente que en circunstancias desfavorables, con aludes de tamaño 1 (alud pequeño o colada) y tamaño 2 (alud mediano), se pueden sufrir severos daños personales.

Nota2: Los BPA se elaboran en base a información meteorológica así como al estado del manto nivoso a través de sondeos puntuales. Se advierte a los usuarios de la variabilidad de esta información al extrapolarla a zonas extensas de montaña. Por ello, AEMET no se hace responsable de su uso para la toma de decisiones que conciernen a la seguridad personal, ni de los riesgos físicos o materiales de ellas derivadas.

AEMET. Se autoriza la reproducción de su contenido citando la fuente.