ICGC Institut Cartogràfic i Geològic de Catalunya

Servei Meteorològic de Catalunya meteo.cat

Boletín de peligro de aludes para el Pirineo de Catalunya
Del 09/03/2026 al 10/03/2026

(Válido fuera pistas de esquí y zonas no controladas)

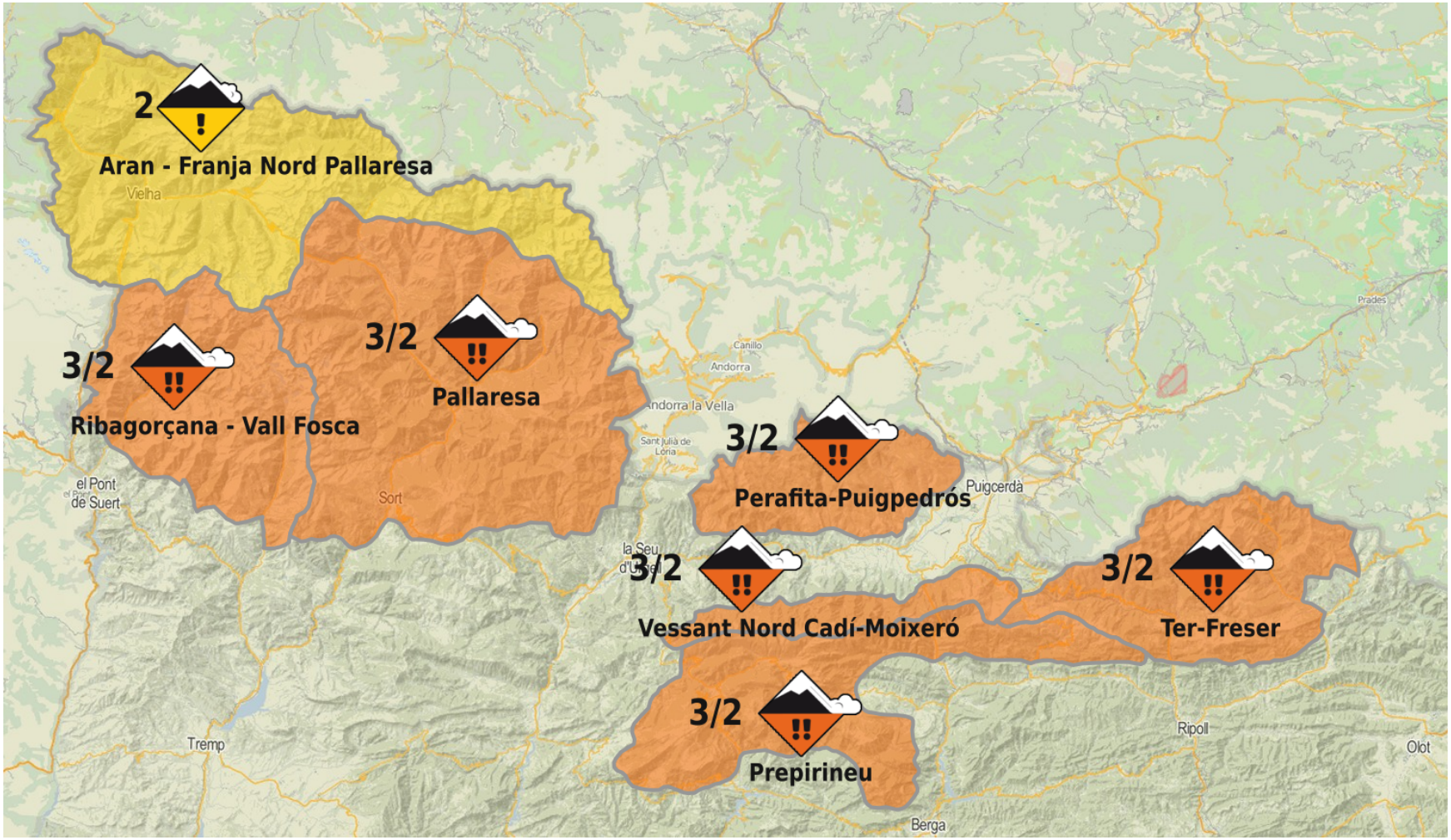

5 MUY FUERTE	4 FUERTE	3 NOTABLE	2 LIMITADO	1 DÉBIL

ICGC Institut Cartogràfic i Geològic de Catalunya

meteo.cat Servei Meteorològic de Catalunya

Boletín de peligro de aludes Aran - Franja Nord Pallaresa Del 09/03/2026 al 10/03/2026

(Válido fuera pistas de esquí y zonas no controladas)

LIMITADO (2)

Situación primaria

Nieve venteada

Distribución

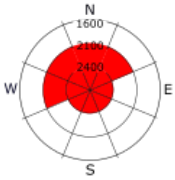

Tamaño

Origen

Tendencia

Situación secundaria

Nieve húmeda

Distribución

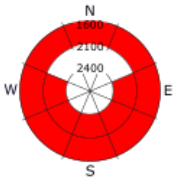

Tamaño

Origen

Tendencia

Estado del manto nivoso

Se mantienen las placas de viento, bajo collados y cordales por encima de 2300-2400 m que se formaron a finales de la semana pasada. Se encuentran por encima de los 2300 m, en orientaciones NW, N y NE, puntualmente en W. Los test de estabilidad, en cotas altas umbrías, muestran propagación de fracturas dentro de capas débiles. Se prevé que las placas antes indicadas puedan caer con facilidad al paso de una persona, en forma de placas blandas; por lo general de tamaño 2, medianao, suficiente para cubrir una persona. En cuanto al problema de nieve húmeda, se centra en las solanas por debajo de 2400 my de las umbrías más bajas, por debajo de los 2100 m. En momentos de claros y de insolación caerán aludes de nieve húmeda en las vertientes soleadas, en general serán de tamaño 1, pequeño, suficiente para hacernos caer y arrastrarnos. Todavía se espera algún deslizamiento basal en las vertientes típicamente herbosas, por lo general de tamaño 2, mediano.

Distribución del manto nivoso

Hay nieve por encima de unos 1.400-1-500 ma umbrías y 1.700 ma solanas. Los espesores a unos 2.200 m son superiores a los normales en la Franja Norte de la Pallaresa y en la mitad sur del Aran donde rondan los 180-220 cm. En la mitad norte de Arán hay unos 120-140 cm de grosor total.

Tendencia para las próximas 48-72h

Continuarán las caídas de nieve húmeda y posibilidad todavía de deslizamientos basales. Las placas de viento pueden aumentar progresivamente la fragilidad en cotas altas umbrías. Peligro ESTACIONARIO

El próximo boletín será emitido el día 2026-03-10

5 MUY FUERTE	4 FUERTE	3 NOTABLE	2 LIMITADO	1 DÉBIL

EAWS EUROPEAN AVALANCHE WARNING SERVICES

ICGC Institut Cartogràfic i Geològic de Catalunya

meteo.cat Servei Meteorològic de Catalunya

Boletín de peligro de aludes Ribagorçana - Vall Fosca Del 09/03/2026 al 10/03/2026

(Válido fuera pistas de esquí y zonas no controladas)

NOTABLE (3) por encima de 2.200 m. LIMITADO (2) por debajo.

Situación primaria

Nieve reciente

Distribución

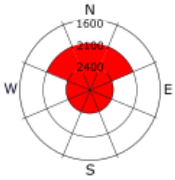

Tamaño

Origen

Tendencia

Situación secundaria

Nieve húmeda

Distribución

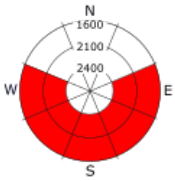

Tamaño

Origen

Tendencia

Estado del manto nivoso

Con las últimas nevadas hay un patrón de nieve seca en las umbrías y en las cotas más altas de solanas y de nieve húmeda por debajo de los 2400 m en las solanas. Se mantiene la probabilidad de caída de aludes de nieve reciente y de placas blandas, de forma natural en laderas de fuerte pendiente por encima de 2200 en umbrías y de 2400 m en solanas. Serán de tamaño 2, con capacidad de enterrar a una persona. En las cotas más altas, bajo collados y cordales hay placas de viento sobre todo en orientaciones norte y oeste, que caerán al paso de una persona; localmente de tamaño 3, grande en sobreacumulaciones. Por debajo de 2400 m en las solanas, pueden caer de forma natural aludes de nieve húmeda, de tamaño 1 en general, puntualmente de tamaño 2 en sectores sobreacumulados, sobre todo en momentos de claros.

Distribución del manto nivoso

Hay nieve en el suelo a 1.600 m en terreno umbrío, y por encima de unos 1.800 m en laderas soleadas. El manto es esquiable por encima de unos 1.700-1.800 ma umbrías. Los grosores alcanzan los 100-130 cm a unos 2.200 m. Estos valores son aún superiores a los normales para la época.

Tendencia para las próximas 48-72h

En el terreno pendiente soleado se mantendrá la probabilidad de caídas de aludes naturales de nieve húmeda. Peligro ESTACIONARIO o EN LEVE DESCENSO

El próximo boletín será emitido el día 2026-03-10

5 MUY FUERTE	4 FUERTE	3 NOTABLE	2 LIMITADO	1 DÉBIL

EAWS EUROPEAN AVALANCHE WARNING SERVICES

ICGC Institut Cartogràfic i Geològic de Catalunya

meteo.cat Servei Meteorològic de Catalunya

Boletín de peligro de aludes Pallaresa
Del 09/03/2026 al 10/03/2026

(Válido fuera pistas de esquí y zonas no controladas)

NOTABLE (3) por encima de 2.200 m. LIMITADO (2) por debajo.

Situación primaria

Nieve reciente

Distribución

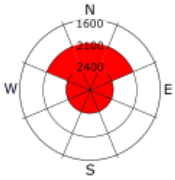

Tamaño

Origen

Tendencia

Situación secundaria

Nieve húmeda

Distribución

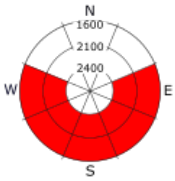

Tamaño

Origen

Tendencia

Estado del manto nivoso

Con las últimas nevadas hay un patrón de nieve seca en las umbrías y en las cotas más altas de solanas y de nieve húmeda por debajo de los 2400 m en las solanas. Se mantiene la probabilidad de caída de aludes de nieve reciente y de placas blandas, de forma natural en laderas de fuerte pendiente por encima de 2200 en umbrías y de 2400 m en solanas. Serán de tamaño 2, con capacidad de enterrar a una persona. En las cotas más altas, bajo collados y cordales hay placas de viento sobre todo en orientaciones norte y oeste, que caerán al paso de una persona; localmente de tamaño 3, grande en sobreacumulaciones. Por debajo de 2400 m en las solanas, pueden caer de forma natural aludes de nieve húmeda, de tamaño 1 en general, puntualmente de tamaño 2 en sectores sobreacumulados, sobre todo en momentos de claros.

Distribución del manto nivoso

Hay nieve en el suelo a 1.600 m en terreno umbrío, y por encima de unos 1.800 m en laderas soleadas. El manto es esquiable por encima de unos 1.700-1.800 ma umbrías. Los grosores alcanzan los 120-160 cm a unos 2.200 m.

Tendencia para las próximas 48-72h

En el terreno pendiente soleado se mantendrá la probabilidad de caídas de aludes naturales de nieve húmeda. Peligro ESTACIONARIO o EN LEVE DESCENSO

El próximo boletín será emitido el día 2026-03-10

5 MUY FUERTE	4 FUERTE	3 NOTABLE	2 LIMITADO	1 DÉBIL

EAWS EUROPEAN AVALANCHE WARNING SERVICES

ICGC Institut Cartogràfic i Geològic de Catalunya

meteo.cat Servei Meteorològic de Catalunya

Boletín de peligro de aludes Perafita-Puigpedrós Del 09/03/2026 al 10/03/2026

(Válido fuera pistas de esquí y zonas no controladas)

NOTABLE (3) por encima de 2.200 m. LIMITADO (2) por debajo.

Situación primaria

Nieve reciente

Distribución

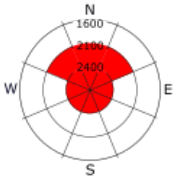

Tamaño

Origen

Tendencia

Situación secundaria

Nieve húmeda

Distribución

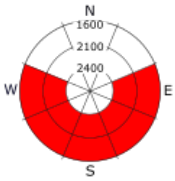

Tamaño

Origen

Tendencia

Estado del manto nivoso

Con las últimas nevadas hay un patrón de nieve seca en las umbrías y en las cotas más altas de solanas y de nieve húmeda por debajo de los 2400 m en las solanas. Se mantiene la probabilidad de caída de aludes de nieve reciente y de placas blandas, de forma natural en laderas de fuerte pendiente por encima de 2200 en umbrías y de 2400 m en solanas. Serán de tamaño 2, con capacidad de enterrar a una persona. En las cotas más altas, bajo collados y cordales hay placas de viento sobre todo en orientaciones norte y oeste, que caerán al paso de una persona; localmente de tamaño 3, grande en sobreacumulaciones. Por debajo de 2400 m en las solanas, pueden caer de forma natural aludes de nieve húmeda, de tamaño 1 en general, puntualmente de tamaño 2 en sectores sobreacumulados, sobre todo en momentos de claros.

Distribución del manto nivoso

Hay nieve en el suelo por encima de unos 1.600-1.700 m. El manto es esquiable por encima de unos 1.800 m. Los espesores, aunque irregulares, rondan los 80-100 cm a 2.200 m. Son grosores por encima de los habituales para la época.

Tendencia para las próximas 48-72h

En el terreno pendiente soleado se mantendrá la probabilidad de caídas de aludes naturales de nieve húmeda. Peligro ESTACIONARIO o EN LEVE DESCENSO

El próximo boletín será emitido el día 2026-03-10

5 MUY FUERTE	4 FUERTE	3 NOTABLE	2 LIMITADO	1 DÉBIL

EAWS EUROPEAN AVALANCHE WARNING SERVICES

ICGC Institut Cartogràfic i Geològic de Catalunya

meteo.cat Servei Meteorològic de Catalunya

Boletín de peligro de aludes
Vessant Nord Cadí-Moixeró
Del 09/03/2026 al 10/03/2026

(Válido fuera pistas de esquí y zonas no controladas)

NOTABLE (3) por encima de 2.200 m. LIMITADO (2) por debajo.

Situación primaria

Nieve reciente

Distribución

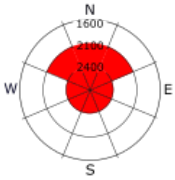

Tamaño

Origen

Tendencia

Situación secundaria

Nieve húmeda

Distribución

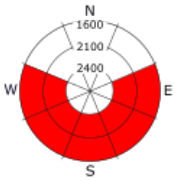

Tamaño

Origen

Tendencia

Estado del manto nivoso

Con las últimas nevadas hay patrón de nieve seca en las umbrías y en las cotas más altas de solanas y de nieve húmeda por debajo de los 2400 m en las solanas. Desde el viernes, ha habido bastante actividad de aludes de nieve reciente y de placa en cotas altas y de nieve húmeda por debajo en las solanas. Se mantiene la probabilidad de caída de aludes de nieve reciente y de placas blandas, de forma natural en laderas muy inclinadas por encima de 2200 m en umbrías y de 2400 en solanas. Serán de tamaño 2, capacidad de enterrar a una persona, incluso puntualmente de tamaño 3, con capacidad de enterrar a un grupo de personas en canales sobreacumuladas. En las cotas más altas, bajo collados y cordales hay placas sobretodo en orientaciones N y W que caerán al paso de una persona; localmente de tamaño 3. Por debajo de 2400 m en solanas pueden caer aludes de nieve húmeda naturales, de tamaño 1 en general, puntualmente de tamaño 2, en sectores sobreacumulados, sobre todo en momentos de claros.

Distribución del manto nivoso

En umbrías hay nieve por encima de 1.600 m, esquiable por encima de unos 1.700 m. En solanas la nieve está presente por encima de 1.800 m. Los grosores están alrededor de 160-180 cm a 2.200 m. Estos valores son muy excedentarios para la época del año.

Tendencia para las próximas 48-72h

En el terreno pendiente soleado se mantendrá la probabilidad de caídas de aludes naturales de nieve húmeda. Peligro ESTACIONARIO o EN LEVE DESCENSO.

El próximo boletín será emitido el día 2026-03-10

5 MUY FUERTE	4 FUERTE	3 NOTABLE	2 LIMITADO	1 DÉBIL

EAWS EUROPEAN AVALANCHE WARNING SERVICES

ICGC Institut Cartogràfic i Geològic de Catalunya

Servei Meteorològic de Catalunya

Boletín de peligro de aludes Prepirineu
Del 09/03/2026 al 10/03/2026

(Válido fuera pistas de esquí y zonas no controladas)

NOTABLE (3) por encima de 2.200 m. LIMITADO (2) por debajo.

Situación primaria

Nieve reciente

Distribución

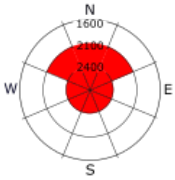

Tamaño

Origen

Tendencia

Situación secundaria

Nieve húmeda

Distribución

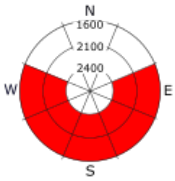

Tamaño

Origen

Tendencia

Estado del manto nivoso

Con las últimas nevadas hay un patrón de nieve seca en las umbrías y en las cotas más altas de solanas y de nieve húmeda por debajo de los 2400 m en las solanas. Se mantiene la probabilidad de caída de aludes de nieve reciente y de placas blandas, de forma natural en laderas de fuerte pendiente por encima de 2200 en umbrías y de 2400 m en solanas. Serán de tamaño 2, con capacidad de enterrar a una persona. En las cotas más altas, bajo collados y cordales hay placas de viento sobre todo en orientaciones norte y oeste, que caerán al paso de una persona; localmente de tamaño 3, grande, en zonas sobreacumuladas. Por debajo de 2400 m en las solanas, pueden caer de forma natural aludes de nieve húmeda, de tamaño 1 en general, puntualmente de tamaño 2 en sectores sobreacumulados, sobre todo en momentos de claros.

Distribución del manto nivoso

En umbrías hay nieve por encima de 1.600-1700 m. En solanas la nieve está presente por encima de 1.800-1.900 m. Los espesores, aunque irregulares, rondan los 60-80 cm en cotas medias.

Tendencia para las próximas 48-72h

En el terreno pendiente soleado se mantendrá la probabilidad de caídas de aludes naturales de nieve húmeda. Peligro ESTACIONARIO o EN LEVE DESCENSO

El próximo boletín será emitido el día 2026-03-10

5 MUY FUERTE	4 FUERTE	3 NOTABLE	2 LIMITADO	1 DÉBIL

EAWS EUROPEAN AVALANCHE WARNING SERVICES

ICGC Institut Cartogràfic i Geològic de Catalunya

meteo.cat Servei Meteorològic de Catalunya

Boletín de peligro de aludes Ter-Freser
Del 09/03/2026 al 10/03/2026

(Válido fuera pistas de esquí y zonas no controladas)

NOTABLE (3) por encima de 2200 m, LIMITADO (2) por debajo.

Situación primaria

Nieve reciente

Distribución

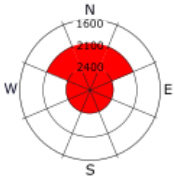

Tamaño

Origen

Tendencia

Situación secundaria

Nieve húmeda

Distribución

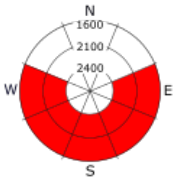

Tamaño

Origen

Tendencia

Estado del manto nivoso

Con las últimas nevadas hay patrón de nieve seca en las umbrías y en las cotas más altas de solanas y de nieve húmeda por debajo de los 2400 m en las solanas. Desde el viernes, ha habido bastante actividad de aludes de nieve reciente y de placa en cotas altas y de nieve húmeda por debajo en las solanas. Se mantiene la probabilidad de caída de aludes de nieve reciente y de placas blandas, de forma natural en laderas muy inclinadas por encima de 2200 m en umbrías y de 2400 en solanas. Serán de tamaño 2, capacidad de enterrar a una persona, incluso puntualmente de tamaño 3, con capacidad de enterrar a un grupo de personas en el sector del Costabona. En las cotas más altas, bajo collados y cordales hay placas sobretodo en orientaciones N y W que caerán al paso de una persona; localmente de tamaño 3. Por debajo de 2400 m en solanas pueden caer aludes naturales de nieve húmeda, de tamaño 1 en general, puntualmente de tamaño 2, en sectores sobreacumulados sobre todo en momentos de claros.

Distribución del manto nivoso

Hay nieve en el suelo por encima de 1.600-1.700 m. Es esquiable a partir de unos 1700 m. El manto nivoso presenta grosores muy excedentarios para la época del año. En lugares no afectados por el viento los grosores oscila entre 80-100 cm a unos 2.000 my más de 200 cm por encima de 2.400 m.

Tendencia para las próximas 48-72h

En el terreno pendiente soleado se mantendrá la probabilidad de caídas de aludes naturales de nieve húmeda. Peligro ESTACIONARIO o EN LEVE DESCENSO

El próximo boletín será emitido el día 2026-03-10

5 MUY FUERTE	4 FUERTE	3 NOTABLE	2 LIMITADO	1 DÉBIL

EAWS EUROPEAN AVALANCHE WARNING SERVICES