BUTLLETÍ DEL PERILL D'ALLAUS DEL PRINCIPAT D'ANDORRA

Servei meteorològic nacional
Principat d'Andorra

Elaborat el 09/03/2026 16:00
Propera actualització 10/03/2026 a les 16h

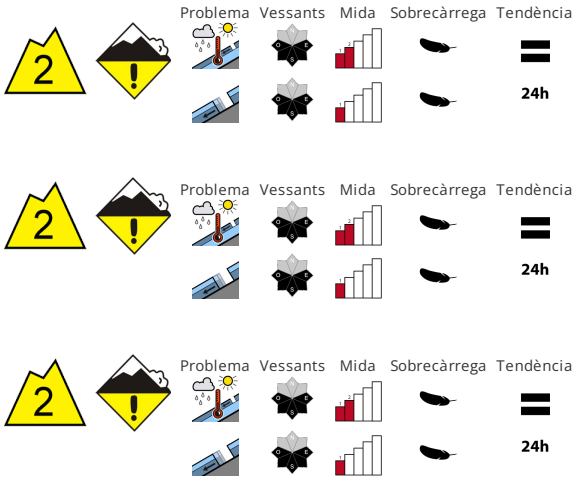

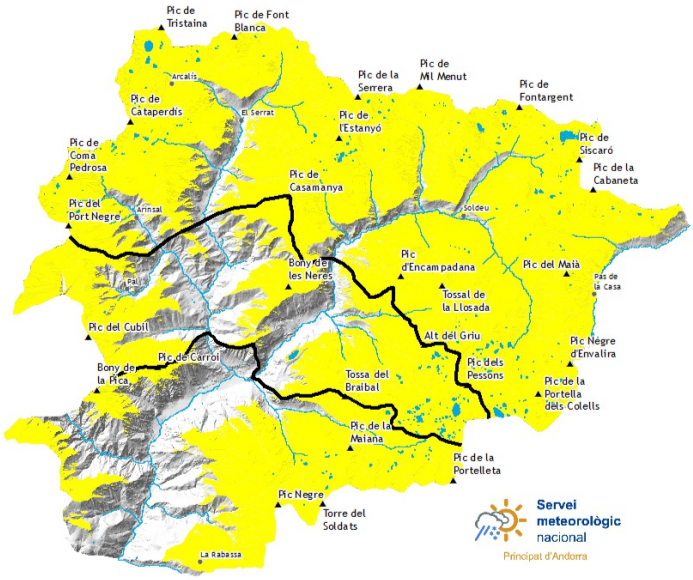

ESTABILITAT DEL MANTELL NIVAL

Amb la pujada de la temperatura i la radiació solar diürna, sobretot als vessants assolellats són possibles algunes allaus de neu humida de mida petita i mitjana. Aquestes poden desencadenar-se de manera natural. A més, són possibles allaus de lliscament basal en qualsevol moment. A cotes altes i als vessants obacs :. Les capes de neu a prop de la superfície poden ser desencadenades de manera aïllada i especialment amb sobrecàrregues fortes. El perill d'allaus romandrà invariable.

QUALITAT DE LA NEU

El temps serà parcialment assolellat. A cotes baixes :. La superfície del mantell de neu es regelarà per formar una crosta portant s'estovarà ja durant el matí. Evitar les zones amb esquerdes de lliscament basal. als vessants obacs i a cotes mitges i altes :. La part superior del mantell és seca, amb una superfície solta. Els gruixos de neu varien molt per sobre dels 2400 m aproximadament per la influència del vent.

GRUIXOS DEL MANTELL NIVAL FORA DE PISTA

Zona nord		Gruix neu		
Mantell Nival		1500m	2000m	2500m
N	1600 m	0 cm	150 cm	200 cm
S	1900 m	0 cm	100 cm	150 cm

Zona centre		Gruix neu		
Mantell Nival		1500m	2000m	2500m
N	1600 m	0 cm	150 cm	200 cm
S	1900 m	0 cm	100 cm	150 cm

Zona sud		Gruix neu		
Mantell Nival		1500m	2000m	2500m
N	1600 m	0 cm	120 cm	150 cm
S	1900 m	0 cm	60 cm	100 cm

Govern d'Andorra

EAWS EUROPEAN AVALANCHE WARNING SERVICES

Aquest butlletí ha estat elaborat seguint les normes i recomanacions de l'**European Avalanche Warning Services**, del qual el **Servei meteorològic Nacional** n'és membre

BUTLLETÍ DEL PERILL D'ALLAUS DEL PRINCIPAT D'ANDORRA

Servei meteorològic nacional
Principat d'Andorra

Informació detallada per espais naturals protegits

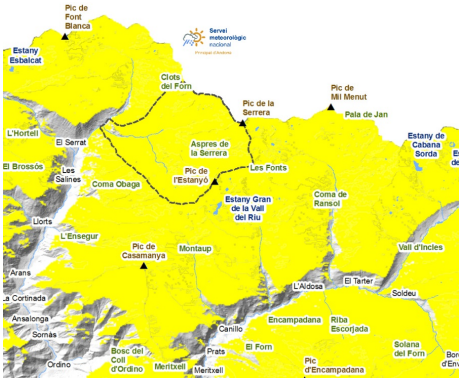

SORTENY

Les febles precipitacions no han modificat les condicions d´estabilitat del mantell de neu. En altura, el vent ha transportat la poca neu disponible i ha format petites acumulacions irregulars i, sobretot als vessants nord, hi ha neu molt agradable d´esquiar. A les part baixes i en vessants assolellats la neu és dura al matí, es recomana anar equipat amb material de punxes per circular-hi, però s´estovarà al llarg del dia.

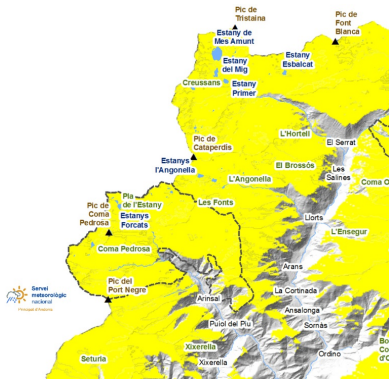

COMAPEDROSA

Cada vegada queda menys neu contínua a les cotes més baixes del Parc. A primeres hores haurem de vigilar a no relliscar a causa de la crosta de regel als vessants sud o a cotes baixes. A les parts altes del Parc, es poden fer nombroses excursions, sempre mantenint una elecció acurada de l´itinerari.

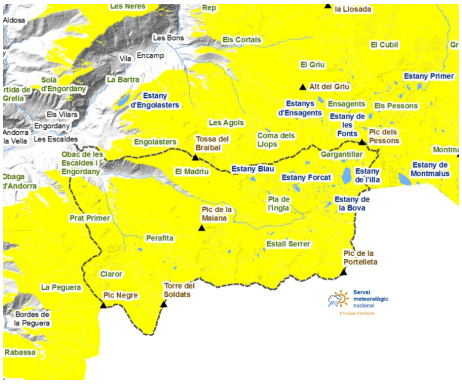

MADRIU-PERAFITA-CLAROR

El mantell és en general prim i irregular, amb millor continuïtat de neu als vessants nord i obacs. Ha estat el sector més afectat per les precipitacions, amb neu nova que és abundant per sobre del límit del bosc, tot i que en alguns indrets elevats el vent ha deixat la neu vella, al descobert.

Govern d'Andorra

EAWS
EUROPEAN AVALANCHE WARNING SERVICES

Aquest butlletí ha estat elaborat seguint les normes i recomanacions de l'**European Avalanche Warning Services**, del qual el **Servei meteorològic Nacional** n'és membre

BUTLLETÍ DEL PERILL D'ALLAUS DEL PRINCIPAT D'ANDORRA

Servei meteorològic nacional
Principat d'Andorra

Gruixos de neu nova dels darrers dies (de les últimes 24h mesurat a les 06:00h UTC)

	05/03/2026	06/03/2026	07/03/2026	08/03/2026
FEDA (Central)	0 cm	0 cm	0 cm	0 cm
Engolasters - FEDA	0 cm	0 cm	0 cm	0 cm
Bony de les Neres	0 cm	2 cm	0 cm	0 cm
Sorteny	10 cm	5 cm	2 cm	6 cm
Les Fonts d'Arinsal	10 cm	5 cm	0 cm	4 cm
Perafita	26 cm	3 cm	0 cm	3 cm
Tossa Espiolets	17 cm	5 cm	0 cm	2 cm
Grau Roig - FEDA	3 cm	5 cm	0 cm	4 cm
Fontverd	0 cm	1 cm	0 cm	1 cm
Ransol - FEDA	0 cm	0 cm	0 cm	0 cm
Caborreu	17 cm	12 cm	0 cm	2 cm
La Solana	10 cm	4 cm	1 cm	5 cm
Coll Pa	9 cm	9 cm	0 cm	0 cm
Envalira Antenes	1 cm	13 cm	0 cm	9 cm
Vall del Riu FEDA	9 cm	5 cm	3 cm	3 cm