Bulletin d'estimation du risque d'avalanche
(valable en dehors des pistes balisées et ouvertes)

MASSIF : Mercantour

Rédigé le lundi 9 mars 2026 à 15h

Estimation des risques pour le : MARDI 10 MARS

PETITES INSTABILITÉS SUPERFICIELLES DANS LA NEIGE FRAÎCHE

2

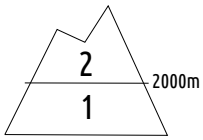

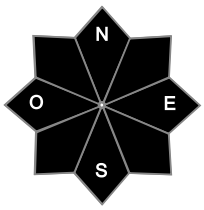

Au-dessus de 2000m indice de risque limité, plus bas indice faible.

Départs spontanés : de faible ampleur en neige fraîche / humide

Déclenchements provoqués : petites instabilités superficielles dans la neige fraîche

Indices de risque : 5 très fort - 4 fort - 3 marqué - 2 limité - 1 faible -- En noir : les pentes les plus dangereuses

Stabilité du manteau neigeux

Situation avalancheuse typique : neige fraîche

Déclenchements provoqués : instabilités temporaires et peu épaisses. Possibles en toute orientation au-dessus de 1900/2000 m, elles sont déclenchables par un seul skieur mais ne mobilisent que la dernière chute de neige. Taille 1 (petite) en général, taille 2 (moyenne) non exclue en cas de cumuls plus importants que prévus. Cette chute repose sur un manteau neigeux bien stabilisé, les instabilités superficielles ne semblent pas en mesure de réactiver les couches fragiles enfouies vers la base du manteau neigeux.

Départs spontanés : en neige fraîche pendant les chutes ou humidifiées par les éclaircies, taille 1, rarement 2.

Qualité de la neige

Enneigement plutôt excédentaire pour un début mars en général, notamment dans le Haut-Verdon.
Données observées : 132 cm à la nivôse de Millefonts à 2430 m.

Enneigement skiable : vers 1400/1500 m en ubacs, 1800/1900 m en adrets peu pentus.

État de la neige en surface : couche de neige fraîche peu ventée (10/20 cm, localement 25 cm) reposant sur un manteau neigeux dense, qui s'humidifie rapidement au soleil en journée. La neige ancienne est restée sèche en ubacs au-dessus de 2200/2300 m, mais bien cartonnée ou durcie par le vent.

Aperçu météo pour le mardi 10 mars

	nuit	matin	après-midi	soir

10/20 cm la nuit de lundi à mardi. 2 à 5 cm sous les averses l'après-midi.

Pluie-Neige	1 400 m	1 600 m	1 700 m	
Iso 0 °C	2 000 m	2 100 m	2 200 m	2 100 m
Vent 2000 m	↖ 20 km/h	↙ 10 km/h	↑ 15 km/h	→ 10 km/h
Vent 3000 m	↖ 40 km/h	← 45 km/h	↑ 15 km/h	→ 20 km/h

Épaisseur de neige hors-piste

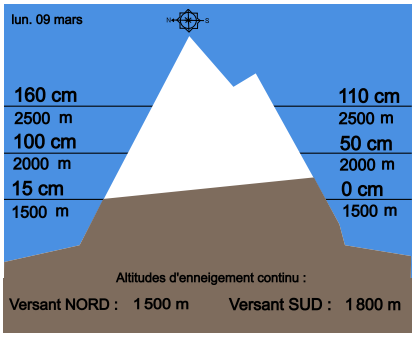

Précipitations à 1800 m

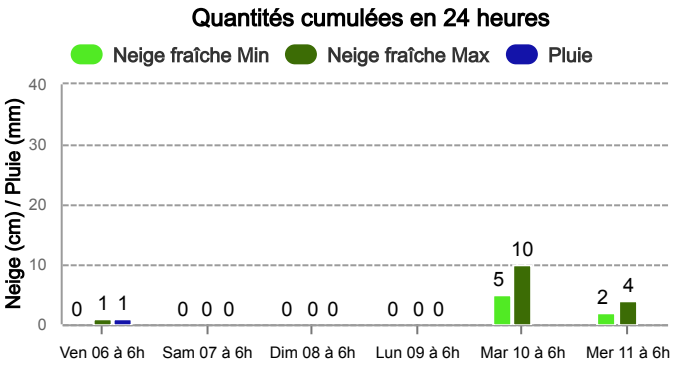

Tendance du mercredi 11 mars

2

Indice de risque limité

Bonne stabilisation su manteau neigeux en adrets. Maintien de quelques instabilités de surface en versants froids d'altitude. Risque limité

Pour consulter la vigilance en cours, veuillez vous rendre sur le site https://vigilance.meteofrance.fr/fr

Météo-France - 73 avenue de Paris, 94165 Saint-Mandé cedex - Contact : contact@meteo.fr

Rédigé par Météo-France avec la contribution des observateurs du réseau nivo-météorologiques. Partenariat : ANMSM (Maires de Stations de Montagne), DSF (Domaines Skiables de France), ADSP (Directeurs de Pistes et de la Sécurité des Stations de Sports d'Hiver) et autres acteurs de la montagne.

Bulletin neige & avalanches par téléphone au 0 892 68 10 20 Service 0,35 € / min + prix appel

RÉPUBLIQUE FRANÇAISE
Liberté Égalité Fraternité

METEO FRANCE
À VOS CÔTÉS, DANS UN CLIMAT QUI CHANGE

Bulletin d'estimation du risque d'avalanche
(valable en dehors des pistes balisées et ouvertes)

MASSIF : Mercantour

Rédigé le lundi 9 mars 2026 à 15h

Conditions nivo-météo des 7 derniers jours

	mar. 03/03				mer. 04/03				jeu. 05/03				ven. 06/03				sam. 07/03				dim. 08/03				lun. 09/03			
	03h	09h	15h	21h	03h	09h	15h	21h	03h	09h	15h	21h	03h	09h	15h	21h	03h	09h	15h	21h	03h	09h	15h	21h	03h	09h	15h	21h
Météo																												
Vent (km/h)	15	10	10	10	10	10	10	5	10	15	20	35	50	45	40	35	35	30	25	20	20	15	15	10	15	20	25	30
à 3000m																												
Vent (km/h)	10	10	15	10	10	10	10	10	15	20	25	35	30	30	30	30	30	25	20	15	20	15	15	10	15	15	15	15
à 2000m																												

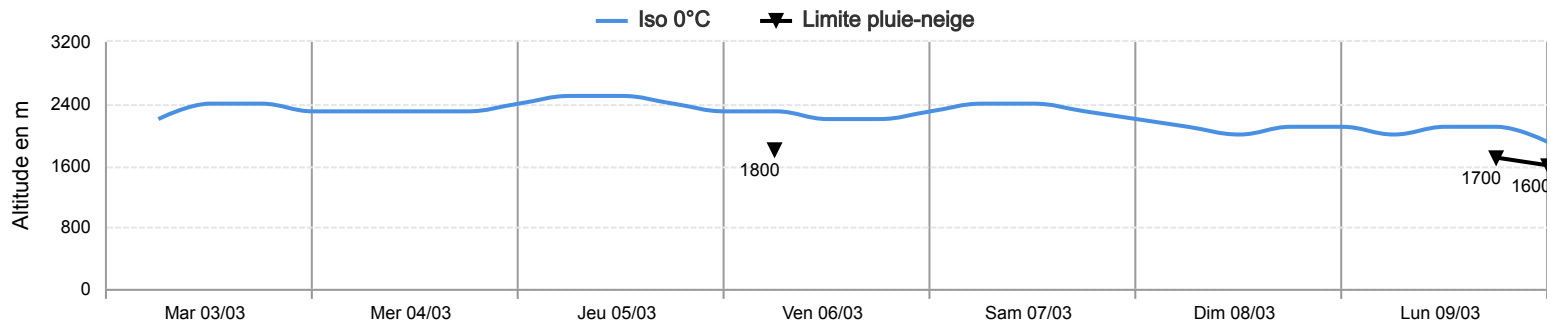

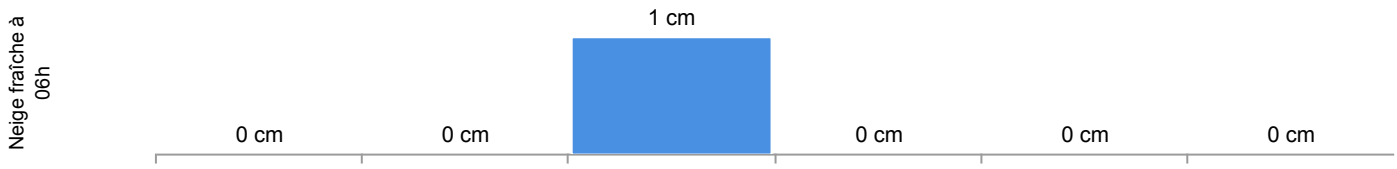

Risque d'avalanche	mar. 03/03	mer. 04/03	jeu. 05/03	ven. 06/03	sam. 07/03	dim. 08/03	lun. 09/03
	2	2	2	2	1	1	1

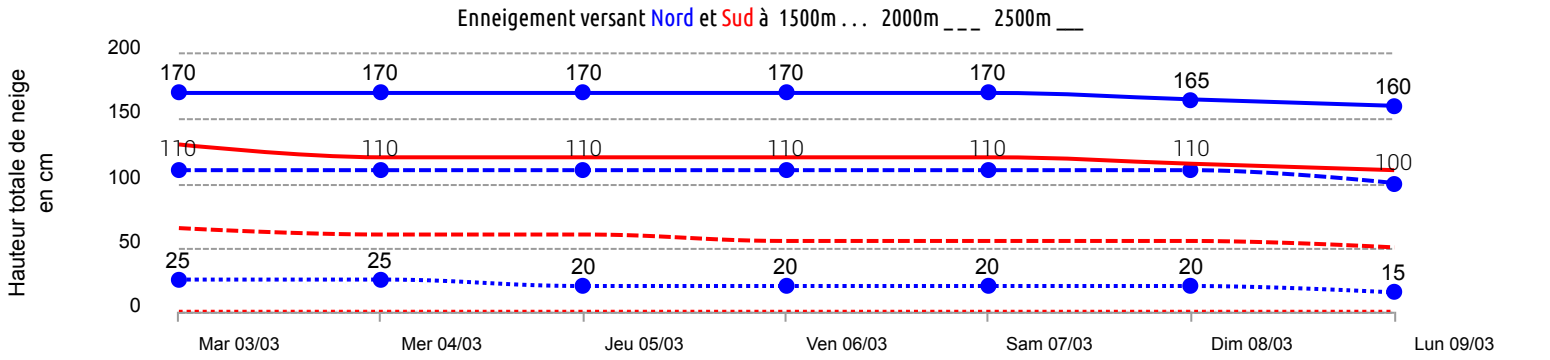

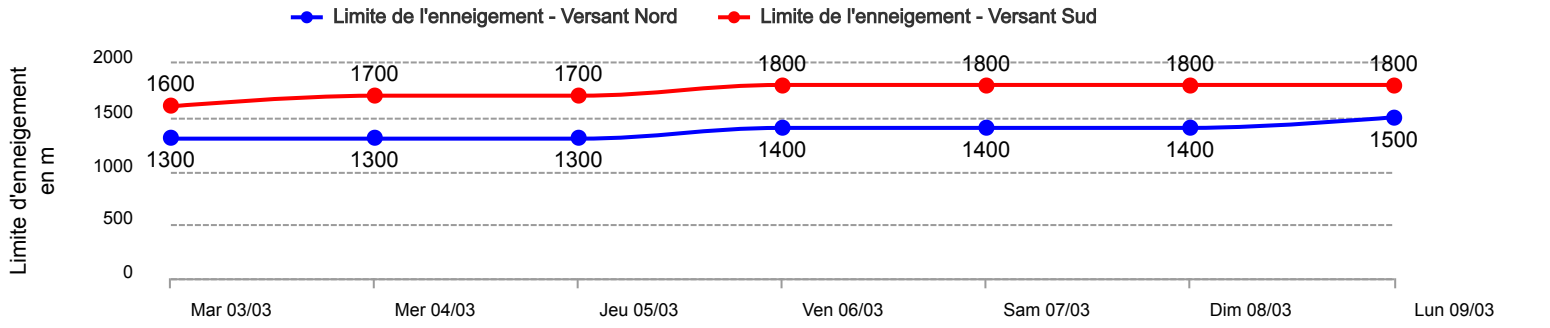

Pour consulter la vigilance en cours, veuillez vous rendre sur le site https://vigilance.meteofrance.fr/fr

Météo-France - 73 avenue de Paris, 94165 Saint-Mandé cedex - Contact : contact@meteo.fr

Rédigé par Météo-France avec la contribution des observateurs du réseau nivo-météorologiques. Partenariat : ANMSM (Maires de Stations de Montagne), DSF (Domaines Skiables de France), ADSP (Directeurs de Pistes et de la Sécurité des Stations de Sports d'Hiver) et autres acteurs de la montagne.

Bulletin neige & avalanches par téléphone au
0 892 68 10 20 Service 0,35 € / min + prix appel