Bulletin d'estimation du risque d'avalanche
(valable en dehors des pistes balisées et ouvertes)

MASSIF : Aravis

Rédigé le lundi 9 mars 2026 à 16h

Estimation des risques pour le : MARDI 10 MARS

MANTEAU NEIGEUX STABLE À BASSE ALTITUDE, ENCORE DE RARES INSTABILITÉS EN ALTITUDE.

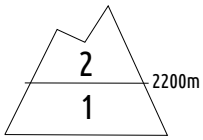

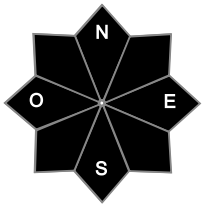

Au-dessus de 2200m indice de risque limité, plus bas indice faible.

Départs spontanés : plaques de fond

Déclenchements provoqués : très rares plaques difficiles à déclencher

Indices de risque : 5 très fort - 4 fort - 3 marqué - 2 limité - 1 faible -- En noir : les pentes les plus dangereuses

Stabilité du manteau neigeux

Situation avalancheuse typique : avalanches de fond

Départs spontanés :
* quelques **plaques de fond**, de jour comme de nuit, dans les pentes lisses et raides (zones herbeuses, dalles rocheuses). Présentes dans les versants **sud sous 2300 m** et dans les versants **nord sous 2000 m**. Taille 2 (moyenne).
* Une chute de grosse corniche est possible pouvant déclencher une plaque en contrebas.

Déclenchements provoqués :
* Au-dessus de 2200 m : très rares plaques dures sur sous-couche fragile persistante enfouie. Difficile à déclencher. Départ possible par chutes de corniches ou avalanches en cascade. Taille 2 (moyenne) avec d'épaisses cassures.

Qualité de la neige

Enneigement :
Pour la saison, l'enneigement est correct.
On peut chausser les skis vers 1200/1300 m en nord, est et ouest et 1400/1700 m en sud.
Grosses corniches encore présentes.
Faible dépôt de poussières désertiques en surface du manteau neigeux.

Qualité de la neige mardi :
* Dans les adrets et sous 1800/2200 m en ubacs : neige regelée. La neige s'humidifie légèrement au soleil en surface le matin.
* Au-dessus de 2100/2200 m en nord, nord-est, nord-ouest : neige froide, dense et dure. Dans de rares zones abritées du vent, il reste un peu de vieille poudreuse.

Aperçu météo pour le mardi 10 mars

nuit	matin	après-midi	soir

Voilé le matin puis de plus en plus couvert au fil des heures. Quelques flocons en fin de journée et début de soirée. Températures à 2000 m : -1à 4°C.

Pluie-Neige			1 600 m	1 500 m
Iso 0 °C	1 800 m	1 800 m	1 800 m	1 700 m
Vent 2000 m	↖ 10 km/h	↑ 10 km/h	↑ 15 km/h	↑ 15 km/h
Vent 2500 m	↑ 25 km/h	↑ 25 km/h	↑ 20 km/h	↗ 30 km/h

Épaisseur de neige hors-piste

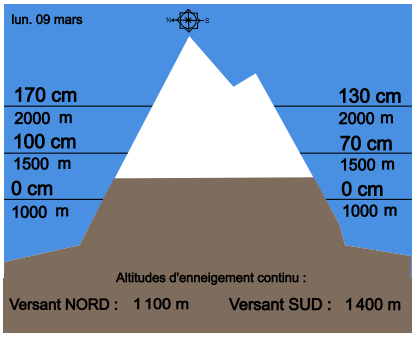

Précipitations à 1800 m

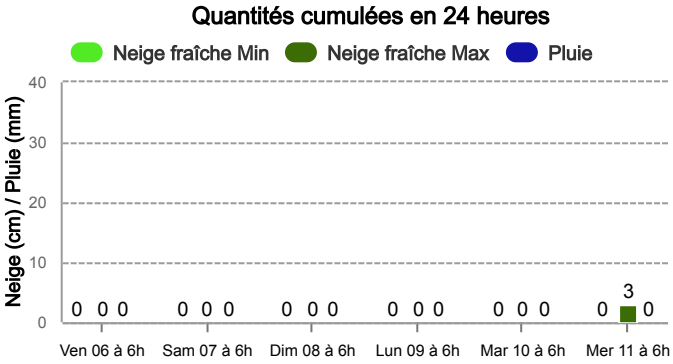

Tendance du mercredi 11 mars

Indice de risque limité

Plutôt beau en première partie de journée avant le retour progressif des nuages en journée. Risque stationnaire.

Pour consulter la vigilance en cours, veuillez vous rendre sur le site https://vigilance.meteofrance.fr/fr

Météo-France - 73 avenue de Paris, 94165 Saint-Mandé cedex - Contact : contact@meteo.fr

Rédigé par Météo-France avec la contribution des observateurs du réseau nivo-météorologiques. Partenariat : ANMSM (Maires de Stations de Montagne), DSF (Domaines Skiables de France), ADSP (Directeurs de Pistes et de la Sécurité des Stations de Sports d'Hiver) et autres acteurs de la montagne.

Bulletin neige & avalanches par téléphone au
0 892 68 10 20 Service 0,35 € / min + prix appel

RÉPUBLIQUE FRANÇAISE
Liberté Égalité Fraternité

METEO FRANCE
À VOS CÔTÉS, DANS UN CLIMAT QUI CHANGE

Bulletin d'estimation du risque d'avalanche
(valable en dehors des pistes balisées et ouvertes)

MASSIF : Aravis

Rédigé le lundi 9 mars 2026 à 16h

Conditions nivo-météo des 7 derniers jours

	mar. 03/03				mer. 04/03				jeu. 05/03				ven. 06/03				sam. 07/03				dim. 08/03				lun. 09/03			
	03h	09h	15h	21h	03h	09h	15h	21h	03h	09h	15h	21h	03h	09h	15h	21h	03h	09h	15h	21h	03h	09h	15h	21h	03h	09h	15h	21h
Météo																												
Vent (km/h)	15	10	10	10	10	10	10	15	15	20	25	25	30	20	20	30	20	10	15	10	20	10	15	15	15	15	20	25
à 2500m																												
Vent (km/h)	5	5	5	5	5	5	5	5	10	10	20	20	20	10	10	20	5	5	5	5	10	5	10	5	5	5	10	10
à 2000m																												

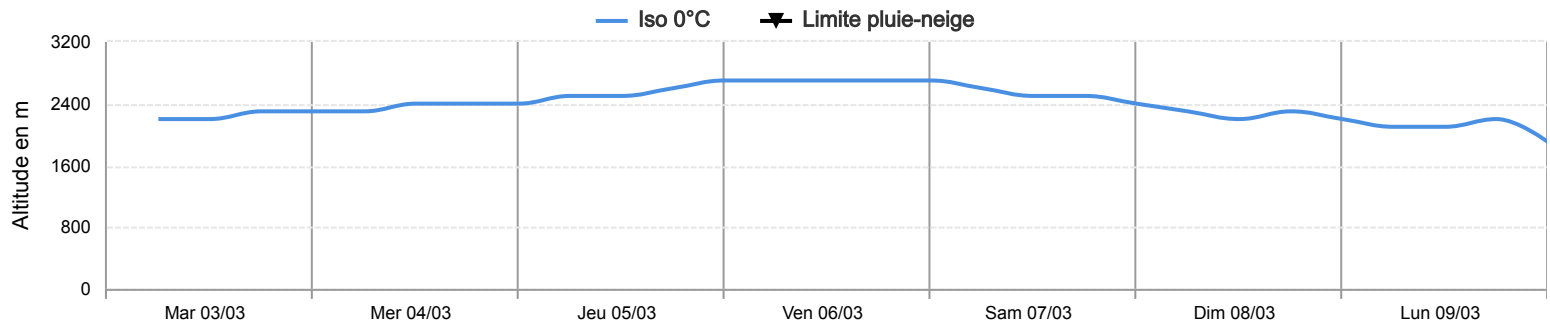

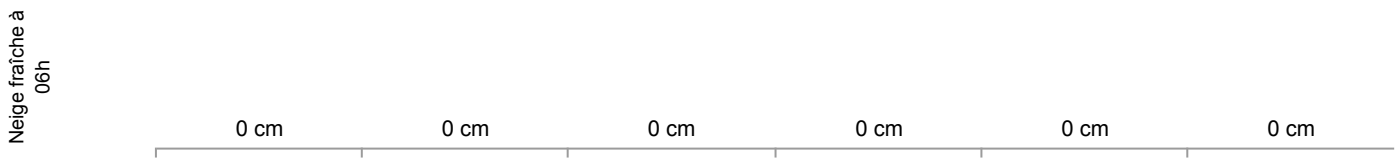

Risque d'avalanche	mar. 03/03	mer. 04/03	jeu. 05/03	ven. 06/03	sam. 07/03	dim. 08/03	lun. 09/03
	2	2	2	2	2	2	2

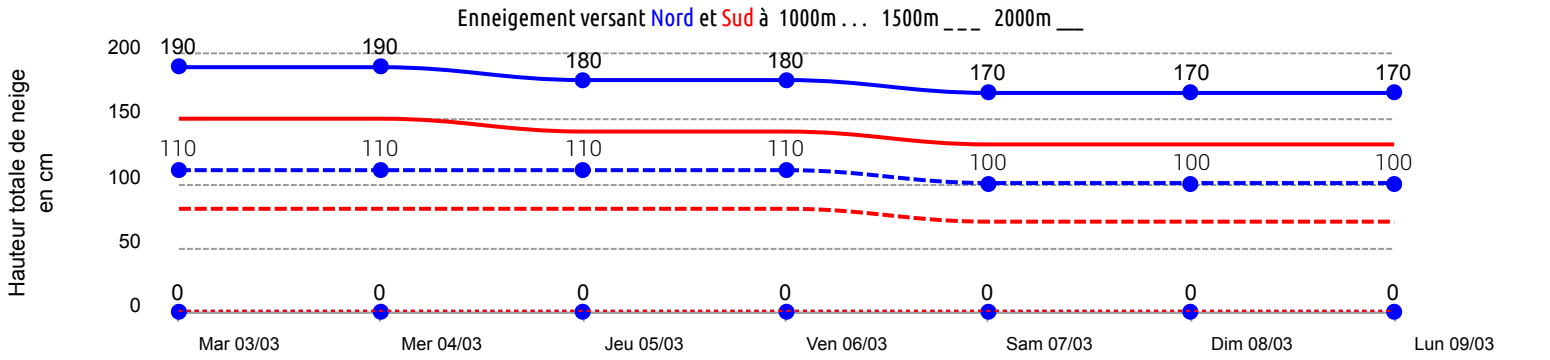

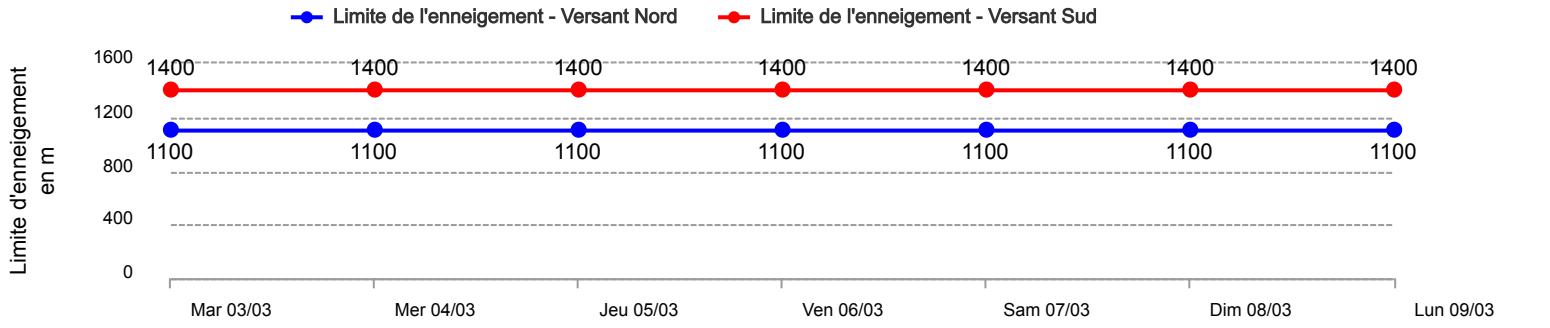

Pour consulter la vigilance en cours, veuillez vous rendre sur le site https://vigilance.meteofrance.fr/fr

Météo-France - 73 avenue de Paris, 94165 Saint-Mandé cedex - Contact : contact@meteo.fr

Rédigé par Météo-France avec la contribution des observateurs du réseau nivo-météorologiques. Partenariat : ANMSM (Maires de Stations de Montagne), DSF (Domaines Skiables de France), ADSP (Directeurs de Pistes et de la Sécurité des Stations de Sports d'Hiver) et autres acteurs de la montagne.

Bulletin neige & avalanches par téléphone au

0 892 68 10 20 Service 0,35 € / min + prix appel