Bulletin d'estimation du risque d'avalanche
(valable en dehors des pistes balisées et ouvertes)
MASSIF : Champsaur

Rédigé le lundi 9 mars 2026 à 16h

Estimation des risques pour le : MARDI 10 MARS

NOUVELLES PLAQUES SUPERFICIELLES EN FORMATION

2

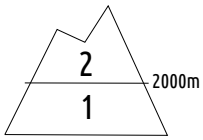

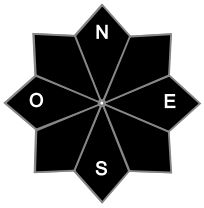

Au-dessus de 2000m indice de risque limité, plus bas indice faible.

Départs spontanés : quelques avalanches de neige récente en pentes raides. Rares avalanches de fond.

Déclenchements provoqués : quelques plaques en formation, plus nombreuses en coeur de massif. D'autres en place en altitude, difficiles à déclencher.

Indices de risque : 5 très fort - 4 fort - 3 marqué - 2 limité - 1 faible -- En noir : les pentes les plus dangereuses

Stabilité du manteau neigeux

Situation avalancheuse typique : neige ventée couche fragile persistante

Départs spontanés : - Quelques avalanches de neige récente lors des averses de neige ou éclaircies en journée de mardi. Elles se produisent en pentes raides à proximité des rochers et sont de petite taille uniquement (taille 1).
- Quelques avalanches de fond à toute heure du jour ou de la nuit, sur les secteurs avec un sol favorable (pentes herbeuses, dalles rocheuses). Départ en général sous 1800/2000 m en ubacs, sous 2400/2500 m en adrets. Avalanches souvent de taille moyenne (taille 2), avec un dépôt souvent épais.

Déclenchements provoqués : - Quelques plaques en formation dans la neige fraîche lors des faibles chutes de neige. Elles sont souvent difficiles à identifier, car d'aspect poudreux. Elles peuvent être faciles à déclencher puisqu'elles reposent parfois sur de la neige sans cohésion notamment en ubacs au-dessus de 2000/2200 m environ. Elles engendrent des avalanches de petite taille uniquement (taille 1).
- Quelques plaques reposant sur des couches fragiles persistantes sont encore en place dans le manteau neigeux, mais elles sont difficiles à solliciter. Déclenchement non exclu au passage d'un skieur ou suite à un premier départ superficiel, plutôt dans les ubacs au-dessus de 2200 m, dans les secteurs où les épaisseurs de neige sont moins importantes (près des croupes, bords des couloirs etc.). Cassure épaisse en cas de départ, emportant une grande partie du manteau neigeux.

Qualité de la neige

L'enneigement est encore excédentaire ou se rapproche des normales selon les secteurs. Les limites d'enneigement remontent dans les pentes bien exposées au soleil.
Hauteurs de neige observées : 40 cm au hameau des Portes dans le Valgaudemar à 1270 m, 129 cm à la Nivôse d'Orcières à 2280 m, et 172 cm au-dessus de Prapic à 2480 m.

Limite d'enneigement skiable : vers 1300 m en ubacs, 1600/1700 m en adrets pas trop raides.

État de la neige de surface : mardi matin, quelques cm de neige fraîche se sont déposés au cours des faibles chutes de neige dans la nuit. De nouvelles averses apportent quelques cm en cours de journée. Cette neige repose sur un manteau neigeux croûté dans les adrets, ainsi qu'en ubacs sous 2000/2200 m. Dans les pentes nord-ouest à nord-est au-dessus de 2200 m environ, neige encore froide, travaillée par les épisodes de vent passés, ou en neige ancienne meuble dans les secteurs abrités.

Aperçu météo pour le mardi 10 mars

	nuit	matin	après-midi	soir

Faibles chutes de neige dans la nuit de lundi à mardi. Averses en journée de mardi.

Pluie-Neige	1 400 m	1 400 m	1 600 m	1 400 m
Iso 0 °C	1 800 m	1 800 m	2 000 m	1 600 m
Vent 2000 m	← 20 km/h	← 15 km/h	↑ 15 km/h	↖ 5 km/h
Vent 3000 m	← 30 km/h	← 25 km/h	↑ 15 km/h	↖ 10 km/h

Épaisseur de neige hors-piste

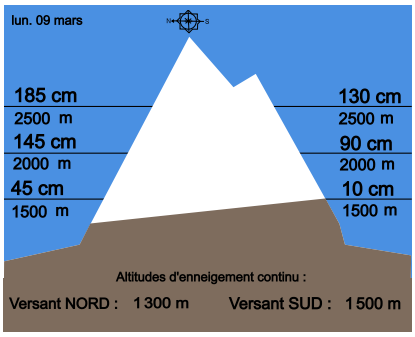

Précipitations à 1800 m

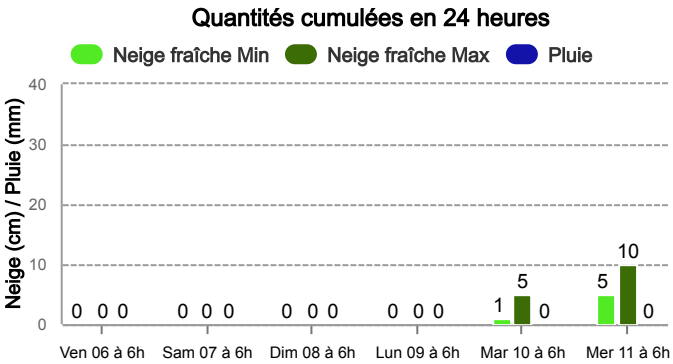

Tendance du mercredi 11 mars

2

Indice de risque limité

Maintien d'un risque limité. Retour à un temps calme en journée de mercredi avant de nouvelles chutes de neige dans la nuit de mercredi à jeudi.

Pour consulter la vigilance en cours, veuillez vous rendre sur le site https://vigilance.meteofrance.fr/fr

Météo-France - 73 avenue de Paris, 94165 Saint-Mandé cedex - Contact : contact@meteo.fr

Rédigé par Météo-France avec la contribution des observateurs du réseau nivo-météorologiques. Partenariat : ANMSM (Maires de Stations de Montagne), DSF (Domaines Skiables de France), ADSP (Directeurs de Pistes et de la Sécurité des Stations de Sports d'Hiver) et autres acteurs de la montagne.

Bulletin neige & avalanches par téléphone au **0 892 68 10 20** Service 0,35 € / min + prix appel

RÉPUBLIQUE FRANÇAISE
Liberté Égalité Fraternité

METEO FRANCE
À VOS CÔTÉS, DANS UN CLIMAT QUI CHANGE

Bulletin d'estimation du risque d'avalanche

(valable en dehors des pistes balisées et ouvertes)

MASSIF : Champsaur

Rédigé le lundi 9 mars 2026 à 16h

Conditions nivo-météo des 7 derniers jours

	mar. 03/03				mer. 04/03				jeu. 05/03				ven. 06/03				sam. 07/03				dim. 08/03				lun. 09/03			
	03h	09h	15h	21h	03h	09h	15h	21h	03h	09h	15h	21h	03h	09h	15h	21h	03h	09h	15h	21h	03h	09h	15h	21h	03h	09h	15h	21h
Météo																												
Vent (km/h)	15	10	10	10	10	5	10	10	15	20	30	30	35	40	30	35	35	20	30	30	30	20	25	30	20	25	30	40
à 3000m																												
Vent (km/h)	10	5	10	10	5	5	10	10	10	15	15	20	25	25	20	25	20	0	10	15	15	10	15	20	10	15	20	25
à 2000m																												

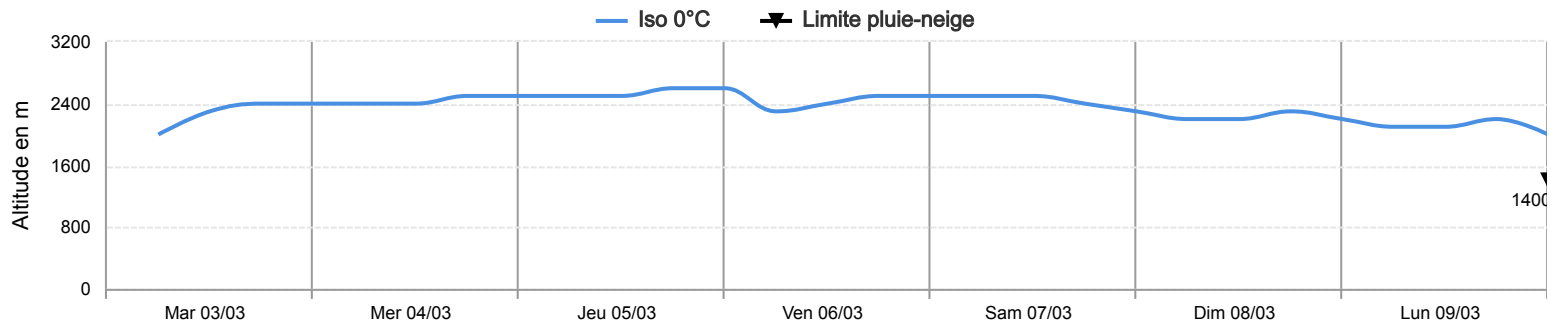

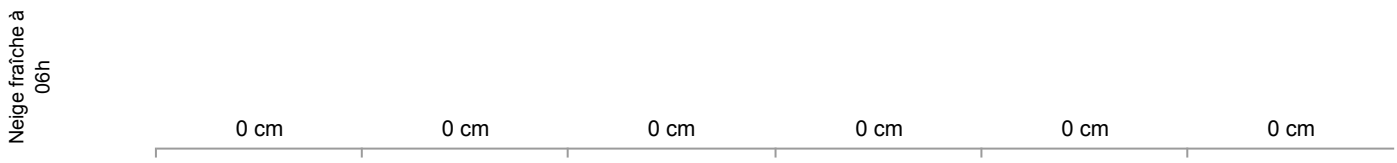

Risque d'avalanche	mar. 03/03	mer. 04/03	jeu. 05/03	ven. 06/03	sam. 07/03	dim. 08/03	lun. 09/03
	2	2	2	2	2	2	2

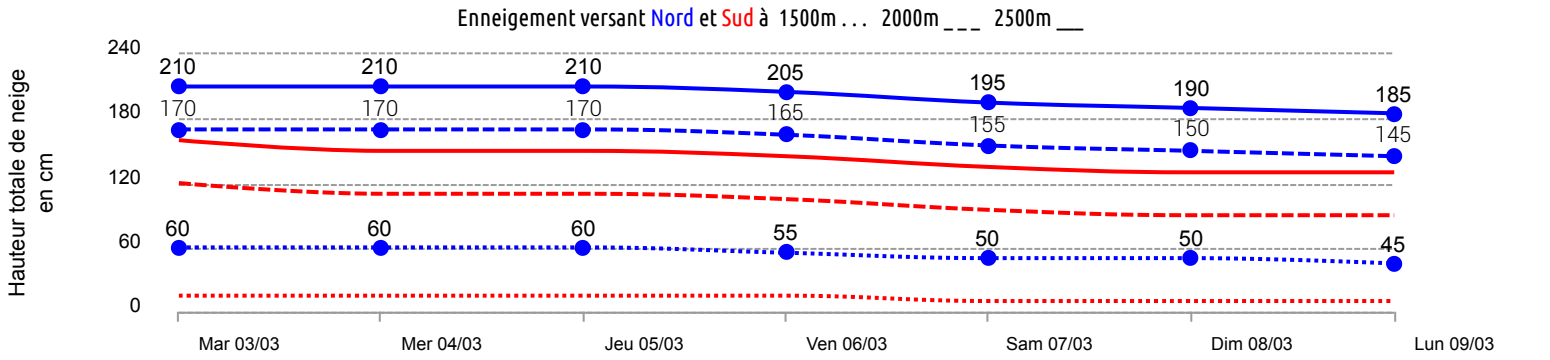

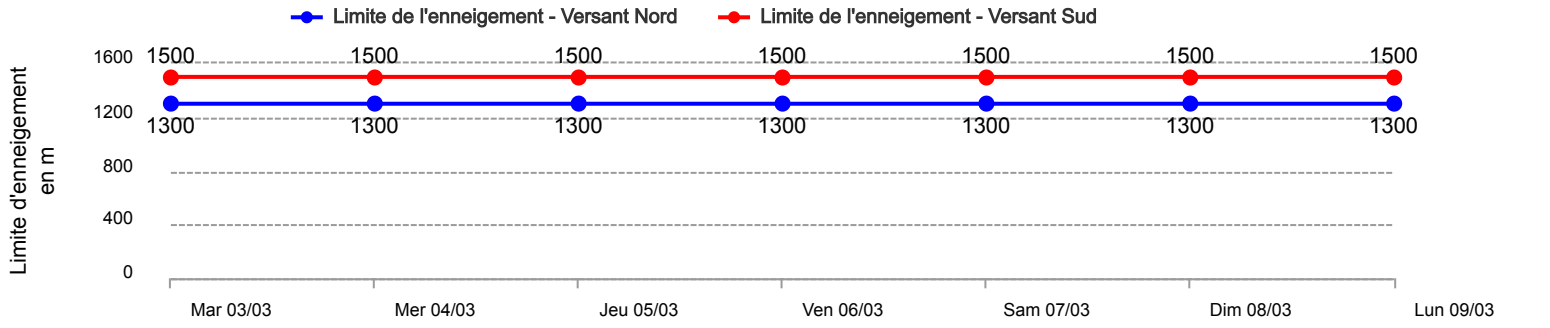

Pour consulter la vigilance en cours, veuillez vous rendre sur le site https://vigilance.meteofrance.fr/fr

Météo-France - 73 avenue de Paris, 94165 Saint-Mandé cedex - Contact : contact@meteo.fr

Rédigé par Météo-France avec la contribution des observateurs du réseau nivo-météorologiques. Partenariat : ANMSM (Maires de Stations de Montagne), DSF (Domaines Skiables de France), ADSP (Directeurs de Pistes et de la Sécurité des Stations de Sports d'Hiver) et autres acteurs de la montagne.

Bulletin neige & avalanches par téléphone au

0 892 68 10 20 Service 0,35 € / min + prix appel