Bulletin d'estimation du risque d'avalanche
(valable en dehors des pistes balisées et ouvertes)

MASSIF : Haute-Ariege

Rédigé le lundi 9 mars 2026 à 16h

Estimation des risques pour le : MARDI 10 MARS

ACTIVITÉ EN NEIGE HUMIDE AVEC D'ÉVENTUELLES ÉPAISSES AVALANCHES DE FOND EMPORTANT TOUT LE MANTEAU NEIGEUX

2

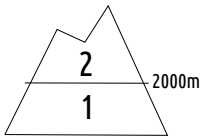

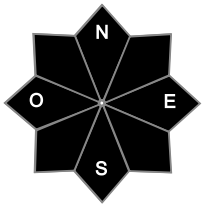

Au-dessus de 2000m indice de risque limité, plus bas indice faible.

Départs spontanés : Avalanches de neige humide, emportant parfois toute l'épaisseur du manteau neigeux

Déclenchements provoqués : Encore quelques structures de plaques en altitude

Indices de risque : 5 très fort - 4 fort - 3 marqué - 2 limité - 1 faible -- En noir : les pentes les plus dangereuses

Stabilité du manteau neigeux

Situation avalancheuse typique : avalanches de fond — neige humide

Départs spontanés :
Avalanches de fond, sur les pentes raides favorables (pentes herbeuses ou dalles rocheuses) possibles en toutes orientations, et jusqu'à 2400/2500 m sur les versants ensoleillés. Cassures souvent plus épaisses et conséquentes au-dessus de 2000m avec actuellement de nombreuses fissures ou gueules de baleines, signes précurseurs de telles avalanches, fréquemment observables dans les pentes concernées.
Activité en neige humide également avec des avalanches de taille souvent petites au fil de la journée dans les pentes raides des secteurs ensoleillés.

Déclenchements provoqués :
Avalanches de plaques possibles peu épaisses dans les secteurs restés froids au-dessus de 2000/2200 m dans la neige récente avec les fréquentes averses des derniers jours. Ces déclenchements sont généralement de petite taille au vu des faibles cumuls de neige. Des plaques plus épaisses peuvent encore être présentes localement en nord d'altitude, elles sont désormais déclenchables seulement par forte surcharge mais pourraient donner des avalanches de plus grande taille.
Sinon, une personne pourra toujours favoriser des départs superficiels en neige humide en traversant une pente raide déjà bien transformée.

Autre : Des ruptures de corniches parfois larges et épaisses sont toujours possibles à proximité des crêtes et sommets, même à basse altitude.

Qualité de la neige

Enneigement :
L'enneigement est excédentaire dès la moyenne montagne grâce aux perturbations neigeuses qui se sont succédé depuis le début de l'année. On peut souvent chausser les skis entre 1500 et 1600 mdans les secteurs orientés sud alors que certaines vallées bien ombragées sont encore enneigées dès 1400 m. On trouve ensuite des quantités de neige plus conséquentes à partir de 1800 m en toutes orientations.

Qualité de la neige :
Mardi matin, on devrait trouver un manteau bien regelé en surface après une nuit claire. Dès 1700/1900m, on pourra également trouver une fine couche de neige fraiche des averses récentes. En journée, la neige s'humidifie assez vite dès le matin dans les versants prenant le soleil puis poursuit son humidification en journée dans les nuages. Plus haut en altitude, on trouvera une neige fréquemment dense et compacte sous 2500 m avec quelques secteurs restant poudreux dans les combes abritées de haute montagne.

Aperçu météo pour le mardi 10 mars

Ciel plutôt bien dégagé le matin puis retour d'averses l'après-midi.

	nuit	matin	après-midi	soir
Pluie-Neige			1 800 m	
Iso 0 °C	2 100 m	2 100 m	2 400 m	2 300 m
Vent 2000 m	↑ 5 km/h	↙ 5 km/h	↓ 5 km/h	↑ 10 km/h
Vent 3000 m	↑ 15 km/h	↑ 10 km/h	↑ 10 km/h	↑ 15 km/h

Épaisseur de neige hors-piste

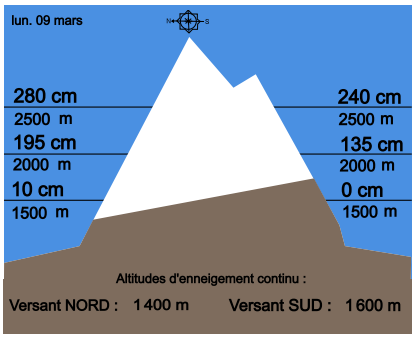

Précipitations à 1800 m

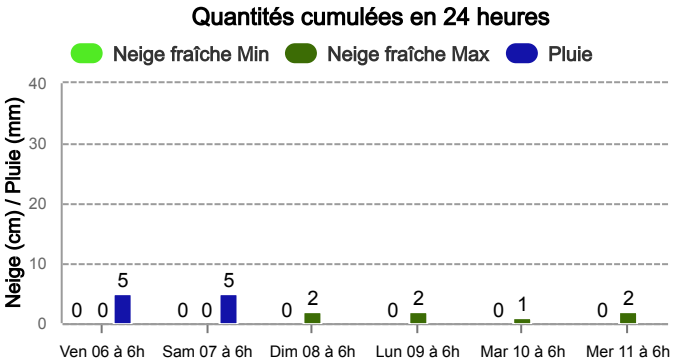

Tendance du mercredi 11 mars

2

Indice de risque limité

Peu d'évolution nivologique avant une perturbation attendue mercredi soir.

Pour consulter la vigilance en cours, veuillez vous rendre sur le site https://vigilance.meteofrance.fr/fr

Météo-France - 73 avenue de Paris, 94165 Saint-Mandé cedex - Contact : contact@meteo.fr

Rédigé par Météo-France avec la contribution des observateurs du réseau nivo-météorologiques. Partenariat : ANMSM (Maires de Stations de Montagne), DSF (Domaines Skiables de France), ADSP (Directeurs de Pistes et de la Sécurité des Stations de Sports d'Hiver) et autres acteurs de la montagne.

Bulletin neige & avalanches par téléphone au **0 892 68 10 20** Service 0,35 € / min + prix appel

Bulletin d'estimation du risque d'avalanche

(valable en dehors des pistes balisées et ouvertes)

MASSIF : Haute-Ariege

Rédigé le lundi 9 mars 2026 à 16h

Conditions nivo-météo des 7 derniers jours

	mar. 03/03				mer. 04/03				jeu. 05/03				ven. 06/03				sam. 07/03				dim. 08/03				lun. 09/03			
	03h	09h	15h	21h	03h	09h	15h	21h	03h	09h	15h	21h	03h	09h	15h	21h	03h	09h	15h	21h	03h	09h	15h	21h	03h	09h	15h	21h
Météo																												
Vent (km/h)	35	25	20	20	25	25	30	40	40	35	30	30	40	25	25	25	40	40	30	25	30	25	25	20	20	15	15	10
à 3000m																												
Vent (km/h)	35	25	20	15	20	20	25	30	35	30	20	20	25	15	20	20	25	30	20	15	20	20	15	10	10	10	10	5
à 2000m																												

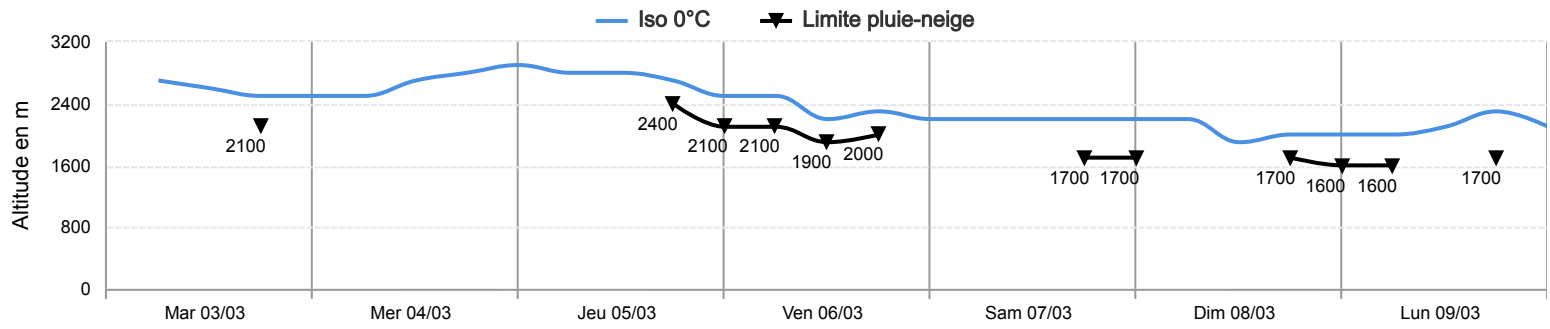

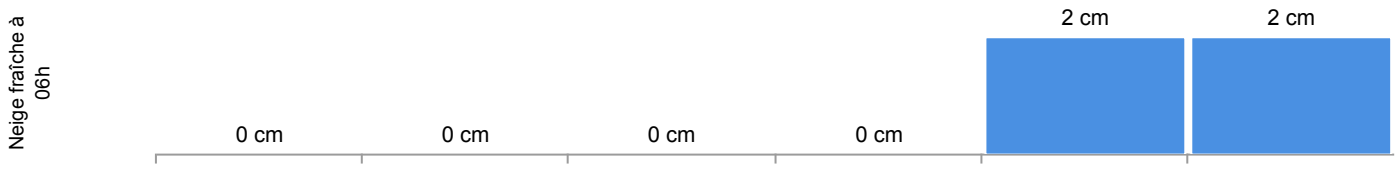

Risque d'avalanche	mar. 03/03	mer. 04/03	jeu. 05/03	ven. 06/03	sam. 07/03	dim. 08/03	lun. 09/03
	2	2	2	2	2	2	2

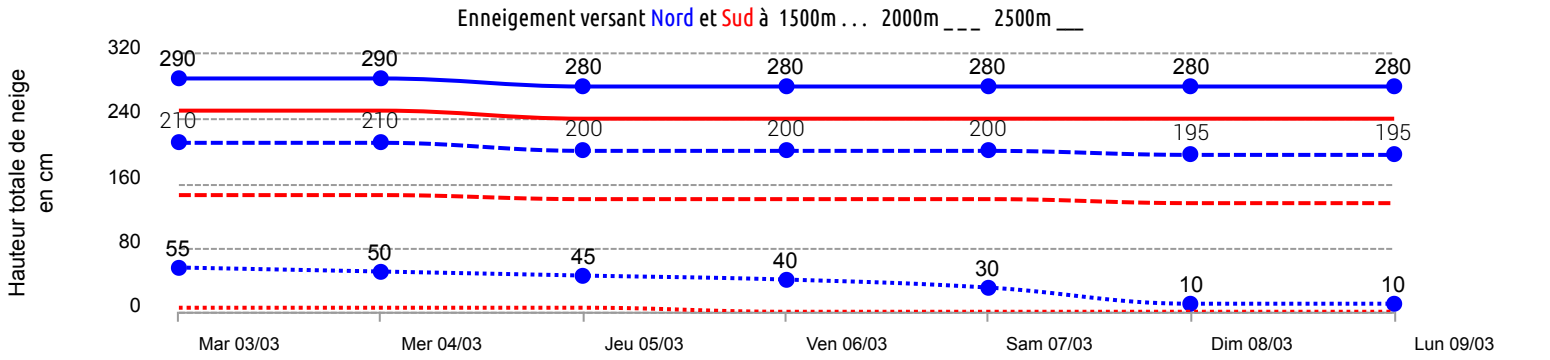

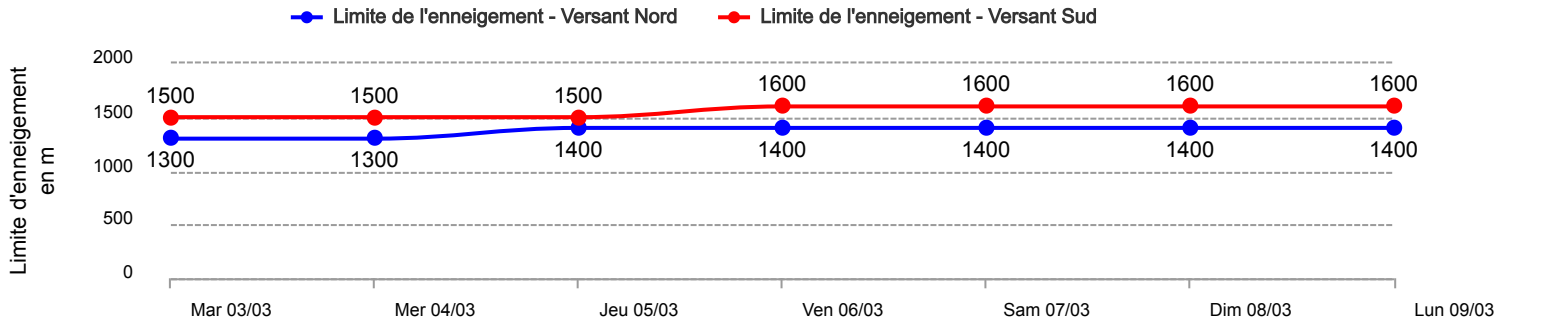

Pour consulter la vigilance en cours, veuillez vous rendre sur le site https://vigilance.meteofrance.fr/fr

Météo-France - 73 avenue de Paris, 94165 Saint-Mandé cedex - Contact : contact@meteo.fr

Rédigé par Météo-France avec la contribution des observateurs du réseau nivo-météorologiques. Partenariat : ANMSM (Maires de Stations de Montagne), DSF (Domaines Skiables de France), ADSP (Directeurs de Pistes et de la Sécurité des Stations de Sports d'Hiver) et autres acteurs de la montagne.

Bulletin neige & avalanches par téléphone au

0 892 68 10 20 Service 0,35 € / min + prix appel