Bulletin d'estimation du risque d'avalanche
(valable en dehors des pistes balisées et ouvertes)

MASSIF : Maurienne

Rédigé le lundi 9 mars 2026 à 16h

Estimation des risques pour le : MARDI 10 MARS

COUCHES FRAGILES ENFOUIES GÉNÉRALISÉES MAIS PEU RÉACTIVES : LE MANTEAU EST PLUTÔT BIEN STABILISÉ.

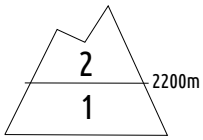

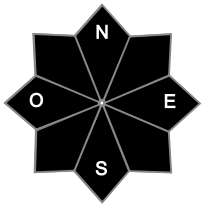

Au-dessus de 2200m indice de risque limité, plus bas indice faible.

Départs spontanés : peu probables.

Déclenchements provoqués : rares plaques sur couches fragiles persistantes, tous versants.

Indices de risque : 5 très fort - 4 fort - 3 marqué - 2 limité - 1 faible -- En noir : les pentes les plus dangereuses

Stabilité du manteau neigeux

Situation avalancheuse typique : couche fragile persistante

Déclenchements provoqués : des **couches fragiles persistantes** (grains anguleux) sont **enfouies de manière généralisée dans le manteau** (en tous versants, même en sud de haute altitude). Leur sollicitation est très peu probable la majorité du temps mais devient possible :
- en versants NO/N/NE, au-dessus de 2200 m (neige froide en surface), dans les zones moins enneigées (abords de crête, croupes dégarnis) où une rare plaque dure peut subsister. Taille 1 à 2 (petite à moyenne).
- en versants ensoleillés à haute altitude, en journée lorsque la neige ramollit en surface, ce qui facilite la sollicitation d'une couche fragile enfouie (scénario moins probable que les jours précédents grâce aux nuages). Taille 2, plus rarement 3 (grande).

Départs spontanés : peu probables. Exceptionnellement une avalanche de glissement sur terrain propice.

Qualité de la neige

Enneigement : en général légèrement excédentaire pour la saison, mais en train de devenir déficitaire en basse montagne et en versants sud.

Limite skiable : encore skiable dès 1100/1200 m dans les prairies orientées nord, plutôt 1600 m en sud pas trop raide.

Qualité de la neige : mauvais regel sous 2000/2200 m avec une neige pourrie voire (pire) finement croutée. Au-dessus :
- en nord suffisamment raide (ou haut), neige froide/sèche (pas de croûte). Beaucoup de secteurs sont travaillés par le vent mais il est possible de trouver localement de la vieille poudre agréable à skier (grains à face plane).
- dans les versants ensoleillés : neige dure le matin, qui ne ramollit que très difficilement en journée (les éclaircies sont minoritaires).

Aperçu météo pour le mardi 10 mars

Très nuageux à couvert. Faibles précipitations en journée, notamment en approchant du secteur Arves/Cerces/Thabor.

	nuit	matin	après-midi	soir
Pluie-Neige		1 600 m	1 600 m	
Iso 0 °C	2 100 m	2 000 m	2 000 m	2 000 m
Vent 2000 m	↖ 25 km/h	↖ 20 km/h	↗ 20 km/h	↑ 10 km/h
Vent 3000 m	↖ 25 km/h	↖ 30 km/h	↗ 30 km/h	↗ 20 km/h

Épaisseur de neige hors-piste

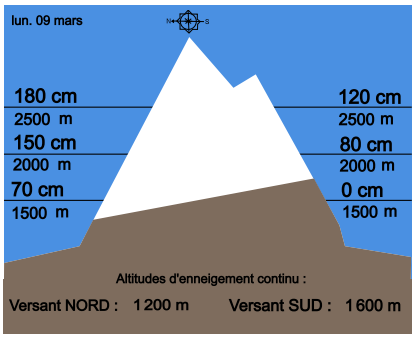

Précipitations à 1800 m

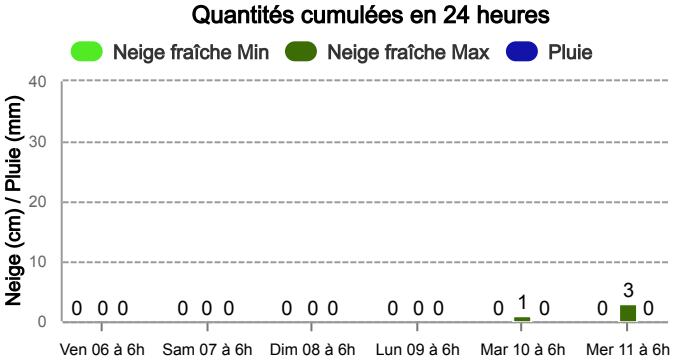

Tendance du mercredi 11 mars

Indice de risque limité

Ciel à nouveau très nuageux voire couvert, sans précipitation notable. Le risque est stationnaire.

Pour consulter la vigilance en cours, veuillez vous rendre sur le site https://vigilance.meteofrance.fr/fr

Météo-France - 73 avenue de Paris, 94165 Saint-Mandé cedex - Contact : contact@meteo.fr

Rédigé par Météo-France avec la contribution des observateurs du réseau nivo-météorologiques. Partenariat : ANMSM (Maires de Stations de Montagne), DSF (Domaines Skiables de France), ADSP (Directeurs de Pistes et de la Sécurité des Stations de Sports d'Hiver) et autres acteurs de la montagne.

Bulletin neige & avalanches par téléphone au **0 892 68 10 20** Service 0,35 € / min + prix appel

RÉPUBLIQUE FRANÇAISE
Liberté Égalité Fraternité

METEO FRANCE
À VOS CÔTÉS, DANS UN CLIMAT QUI CHANGE

Bulletin d'estimation du risque d'avalanche
(valable en dehors des pistes balisées et ouvertes)

MASSIF : Maurienne

Rédigé le lundi 9 mars 2026 à 16h

Conditions nivo-météo des 7 derniers jours

	mar. 03/03				mer. 04/03				jeu. 05/03				ven. 06/03				sam. 07/03				dim. 08/03				lun. 09/03			
	03h	09h	15h	21h	03h	09h	15h	21h	03h	09h	15h	21h	03h	09h	15h	21h	03h	09h	15h	21h	03h	09h	15h	21h	03h	09h	15h	21h
Météo																												
Vent (km/h)	15	15	15	15	10	10	10	10	20	25	25	30	40	45	40	30	20	30	30	30	20	20	20	15	20	20	20	20
à 3000m																												
Vent (km/h)	10	5	5	5	5	5	5	5	20	25	25	30	30	35	30	20	15	20	20	20	15	10	15	10	15	15	20	30
à 2000m																												

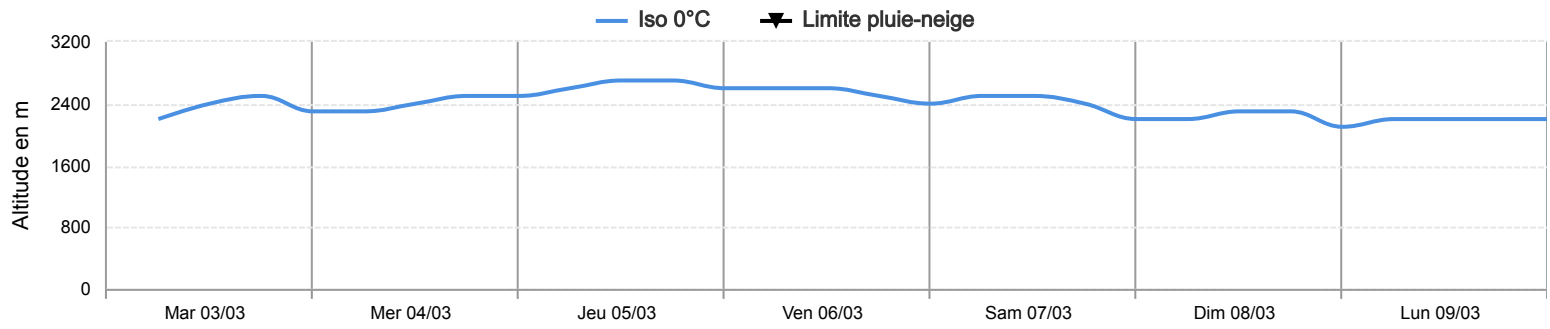

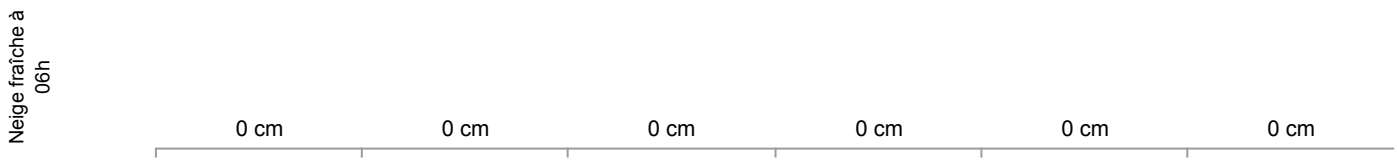

Risque d'avalanche	mar. 03/03	mer. 04/03	jeu. 05/03	ven. 06/03	sam. 07/03	dim. 08/03	lun. 09/03
	2	2	2	2	2	2	2

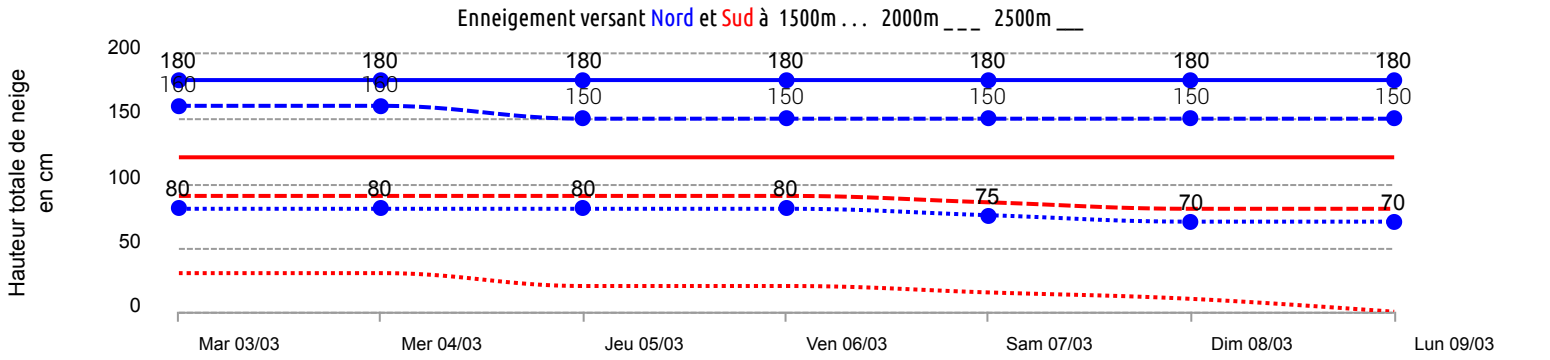

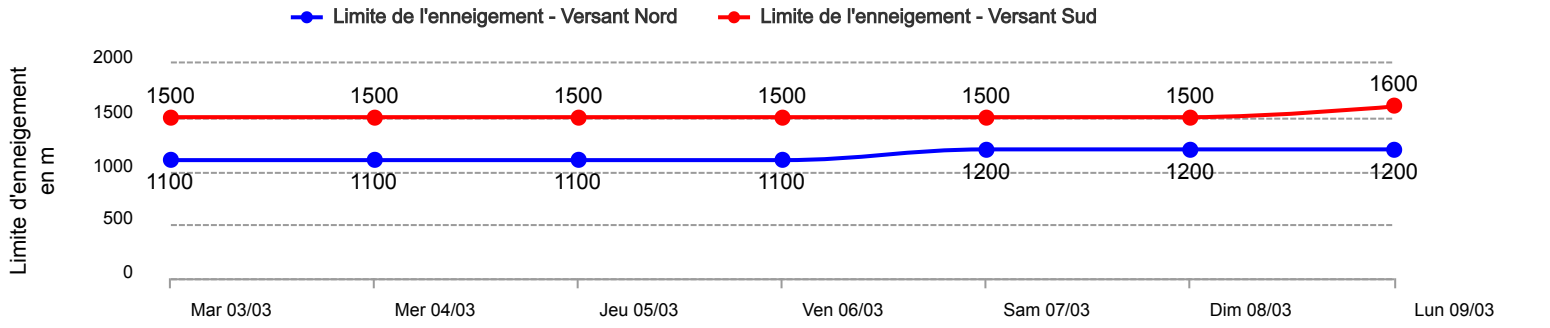

Pour consulter la vigilance en cours, veuillez vous rendre sur le site https://vigilance.meteofrance.fr/fr

Météo-France - 73 avenue de Paris, 94165 Saint-Mandé cedex - Contact : contact@meteo.fr

Rédigé par Météo-France avec la contribution des observateurs du réseau nivo-météorologiques. Partenariat : ANMSM (Maires de Stations de Montagne), DSF (Domaines Skiables de France), ADSP (Directeurs de Pistes et de la Sécurité des Stations de Sports d'Hiver) et autres acteurs de la montagne.

Bulletin neige & avalanches par téléphone au

0 892 68 10 20 Service 0,35 € / min + prix appel