Bulletin d'estimation du risque d'avalanche

(valable en dehors des pistes balisées et ouvertes)

MASSIF : Orlu St-Barthelemy

Rédigé le lundi 9 mars 2026 à 16h

Estimation des risques pour le : MARDI 10 MARS

ACTIVITÉ EN NEIGE HUMIDE AVEC DE POSSIBLES ÉPAISSES AVALANCHES DE FOND EMPORTANT TOUT LE MANTEAU NEIGEUX; QUELQUES STRUCTURES DE PLAQUES SUR ORLU ET LE DONNEZAN DÉSORMAIS DIFFICILEMENT DÉCLENCHABLES

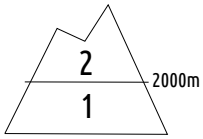

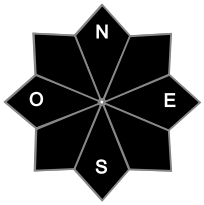

Au-dessus de 2000m indice de risque limité, plus bas indice faible.

Départs spontanés : Avalanches de neige humide, emportant parfois toute l'épaisseur du manteau neigeux

Déclenchements provoqués : Structures de plaques dans la neige récente désormais difficillement déclenchables

Indices de risque : 5 très fort - 4 fort - 3 marqué - 2 limité - 1 faible -- En noir : les pentes les plus dangereuses

Stabilité du manteau neigeux

Situation avalancheuse typique : neige humide avalanches de fond

Départs spontanés :
Avalanches de fond, sur les pentes raides favorables (pentes herbeuses ou dalles rocheuses) possibles en toutes orientations, et jusqu'à 2400/2500 m sur les versants ensoleillés. Cassures souvent plus épaisses et conséquentes au-dessus de 2000m avec actuellement de nombreuses fissures ou gueules de baleines, signes précurseurs de telles avalanches, fréquemment observables dans les pentes concernées.
Activité en neige humide également avec des avalanches de taille souvent petites à moyenne au fil de la journée dans les pentes raides des secteurs ensoleillés.

Déclenchements provoqués :
Structures de plaques désormais difficilement déclenchables au-dessus de 2000/2200 m, dans les secteurs Orlu et Donezan, plutôt en versants nord et ombragés. Les plaques formées en fin de semaine dernière devraient maintenant être bien stabilisées mais dans de rares configurations, il n'est pas exclu qu'elles puissent encore être sollicitées, avec une avalanche de taille moyenne, voire grande.
Sinon, une personne pourra toujours favoriser des départs superficiels en neige humide en traversant une pente raide déjà bien transformée.

Autre : Des ruptures de corniches parfois larges et épaisses sont toujours possibles à proximité des crêtes et sommets, même à basse altitude.

Qualité de la neige

Enneigement :
L'enneigement est encore excédentaire dès la moyenne montagne grâce aux perturbations neigeuses qui se sont succédé depuis le début de l'année, notamment dans le massif d'Orlu. La limite skiable se situe vers 1500/1600m plein sud alors que certaines vallées ombragées sont encore enneigées dès 1300/1400m.

Qualité de la neige :
Mardi matin, on devrait trouver un manteau dur et bien regelé en surface après une nuit claire. Dès 1700/1900m, on pourra également trouver une fine couche de neige fraiche des averses récentes. En journée, la neige s'humidifie assez vite dès le matin dans les versants prenant le soleil puis poursuit son humidification en journée dans les nuages. Plus haut en altitude, on trouvera une neige fréquemment dense et compacte sous 2500 m avec quelques secteurs restant poudreux dans les combes abritées sur le secteur d'Orlu.

Aperçu météo pour le mardi 10 mars

	nuit	matin	après-midi	soir
	Ciel bien dégagé le matin puis retour d'averses l'après-midi.			
Pluie-Neige			1 800 m	
Iso 0 °C	2 100 m	2 100 m	2 200 m	2 200 m
Vent 2000 m	↗ 5 km/h	↗ 5 km/h	↓ 10 km/h	↑ 10 km/h
Vent 3000 m	↑ 15 km/h	→ 20 km/h	→ 20 km/h	↗ 15 km/h

Épaisseur de neige hors-piste

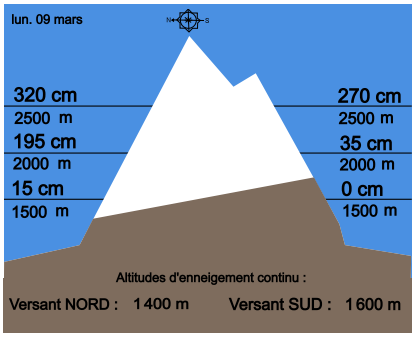

Précipitations à 1800 m

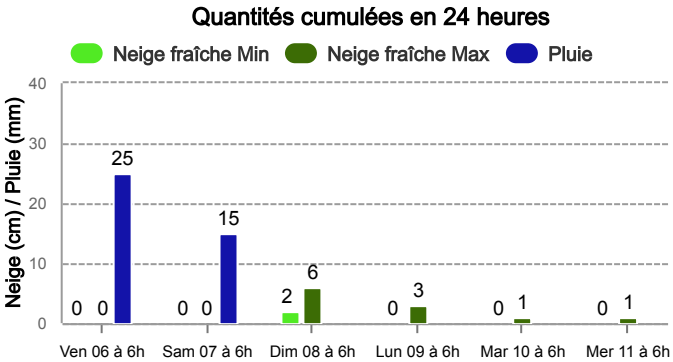

Tendance du mercredi 11 mars

Indice de risque limité

Peu d'évolution nivologique jusqu'à l'arrivée d'une perturbation mercredi soir.

Pour consulter la vigilance en cours, veuillez vous rendre sur le site https://vigilance.meteofrance.fr/fr

Météo-France - 73 avenue de Paris, 94165 Saint-Mandé cedex - Contact : contact@meteo.fr

Rédigé par Météo-France avec la contribution des observateurs du réseau nivo-météorologiques. Partenariat : ANMSM (Maires de Stations de Montagne), DSF (Domaines Skiables de France), ADSP (Directeurs de Pistes et de la Sécurité des Stations de Sports d'Hiver) et autres acteurs de la montagne.

Bulletin neige & avalanches par téléphone au **0 892 68 10 20** Service 0,35 € / min + prix appel

RÉPUBLIQUE FRANÇAISE
Liberté Égalité Fraternité

METEO FRANCE
À VOS CÔTÉS, DANS UN CLIMAT QUI CHANGE

Bulletin d'estimation du risque d'avalanche

(valable en dehors des pistes balisées et ouvertes)

MASSIF : Orlu St-Barthelemy

Rédigé le lundi 9 mars 2026 à 16h

Conditions nivo-météo des 7 derniers jours

	mar. 03/03				mer. 04/03				jeu. 05/03				ven. 06/03				sam. 07/03				dim. 08/03				lun. 09/03			
	03h	09h	15h	21h	03h	09h	15h	21h	03h	09h	15h	21h	03h	09h	15h	21h	03h	09h	15h	21h	03h	09h	15h	21h	03h	09h	15h	21h
Météo																												
Vent (km/h)	25	20	20	15	15	20	35	35	40	40	50	55	40	25	25	25	40	40	30	25	30	25	25	20	20	15	15	15
à 3000m																												
Vent (km/h)	25	20	20	15	25	20	20	25	30	30	35	30	25	15	20	20	25	30	20	15	20	20	15	10	10	10	10	5
à 2000m																												

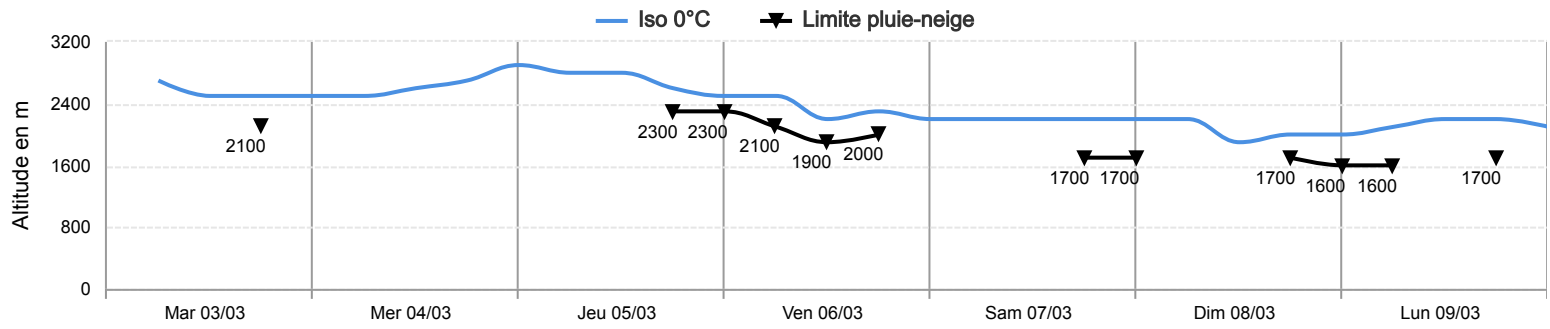

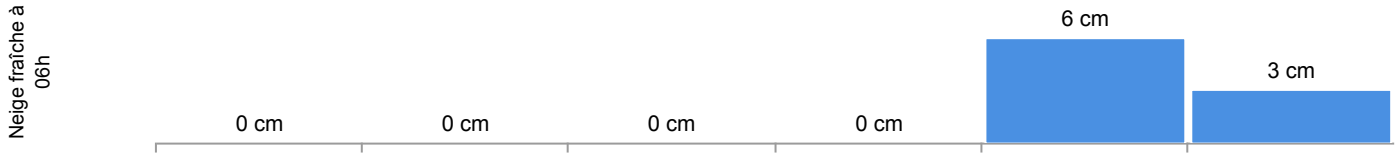

Risque d'avalanche	mar. 03/03	mer. 04/03	jeu. 05/03	ven. 06/03	sam. 07/03	dim. 08/03	lun. 09/03
	2	2	2	3	3	3	2

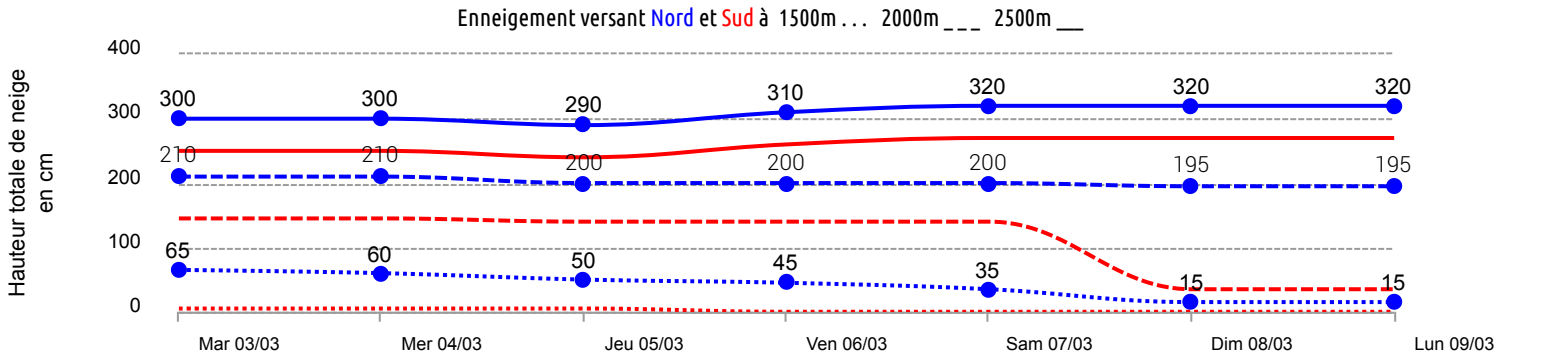

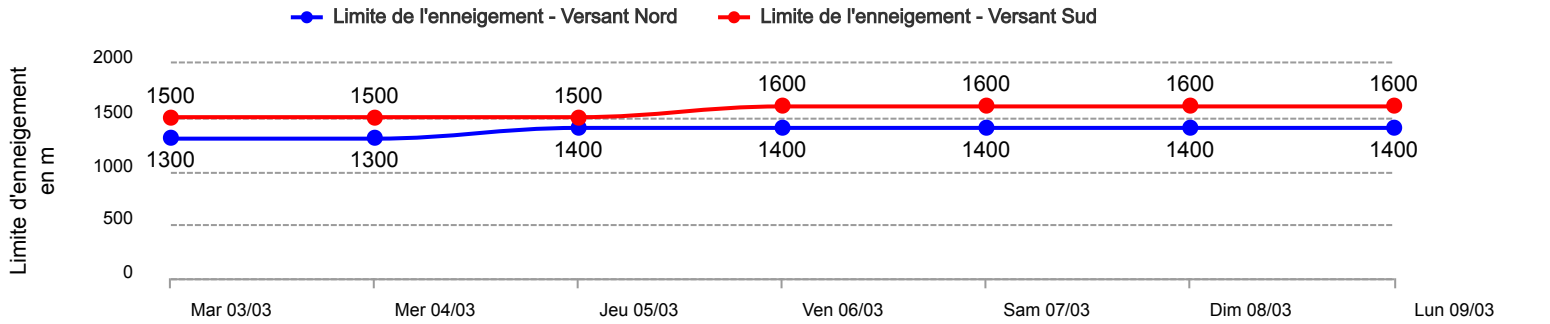

Pour consulter la vigilance en cours, veuillez vous rendre sur le site https://vigilance.meteofrance.fr/fr

Météo-France - 73 avenue de Paris, 94165 Saint-Mandé cedex - Contact : contact@meteo.fr

Bulletin neige & avalanches par téléphone au

0 892 68 10 20 Service 0,35 € / min + prix appel

Rédigé par Météo-France avec la contribution des observateurs du réseau nivo-météorologiques. Partenariat : ANMSM (Maires de Stations de Montagne), DSF (Domaines Skiables de France), ADSP (Directeurs de Pistes et de la Sécurité des Stations de Sports d'Hiver) et autres acteurs de la montagne.