GOBIERNO DE ESPAÑA
VICEPRESIDENCIA TERCERA DEL GOBIERNO
MINISTERIO PARA LA TRANSICIÓN ECOLÓGICA Y EL RETO DEMOGRÁFICO

Boletín de información nivológica y de peligro de aludes

Pirineo Catalán

aemet Agencia Estatal de Meteorología

martes, 10 de marzo de 2026

Pronóstico hasta las 24 horas del miércoles, día 11 de marzo

(Válido fuera de pistas de esquí balizadas y abiertas)

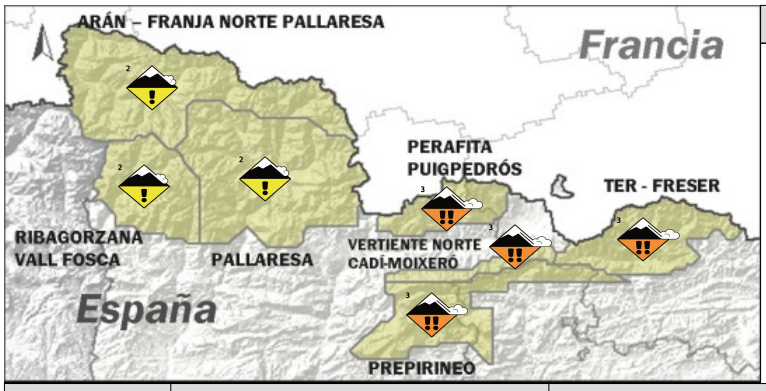

Problemas de aludes

Placas de viento

Nieve húmeda

Macizo	Peligro	Problemas de aludes, cota, orientación, tamaño	Innivación observada (m)
Arán - Franja norte Pallaresa	2 – 2 – **Limitado**	**Nieve húmeda** – 2300 – N O E S – 2 **Placas de viento** – 2200 – N O E S – 2	2026-03-10 N S – Cota más baja caras N
Ribagorzana - Vall Fosca	2 – 2 – **Limitado**	**Nieve húmeda** – 2300 – N O E S – 2 **Placas de viento** – 2200 – N O E S – 2	2026-03-10 N S – Cotas medias
Pallaresa	2 – 2 – **Limitado**	**Nieve húmeda** – 2300 – N O E S – 2 **Placas de viento** – 2200 – N O E S – 2	2026-03-10 N S – Cotas medias

AEMET. Se autoriza la reproducción de su contenido citando la fuente.

Boletín de información nivológica y de peligro de aludes

Pirineo Catalán

Perafita - Puigpedrós	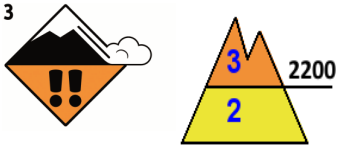 **Notable**	**Placas de viento**	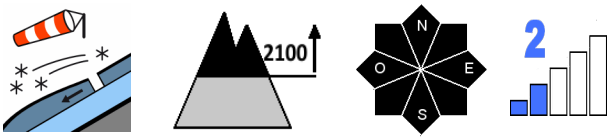	2026-03-10
		Nieve húmeda	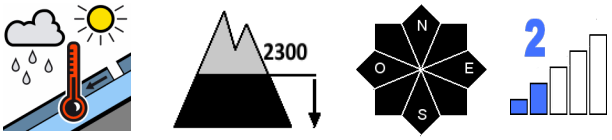	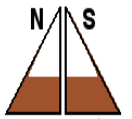 Cotas medias
Ter - Freser	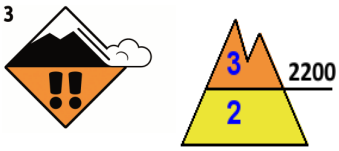 **Notable**	**Placas de viento**	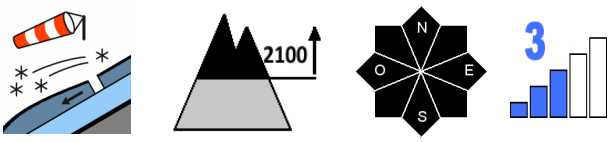	2026-03-10
		Nieve húmeda		Cotas medias
Vertiente norte Cadí - Moixeró	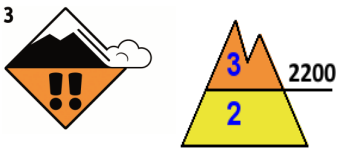 **Notable**	**Placas de viento**	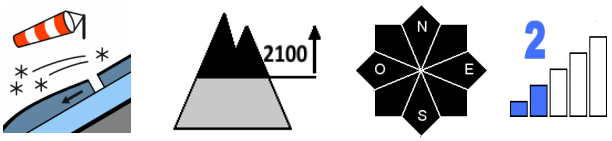	2026-03-10
		Nieve húmeda		Cotas medias
Prepirineo	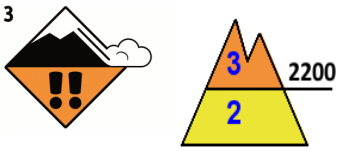 **Notable**	**Placas de viento**	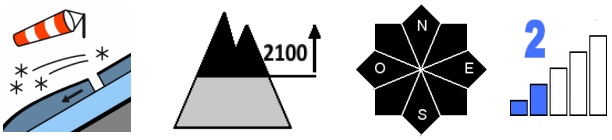	2026-03-10
		Nieve húmeda	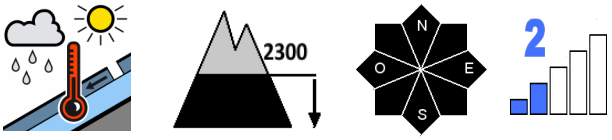	Cotas medias

Estado del manto y observaciones recientes

Ayer se registraron algunas nevadas débiles, con cota de nieve en torno a unos 1400-1600 metros, algo más frecuentes e intensas en los macizos orientales, pudiendo haber depositado del entorno de 5-15 cm en las cotas altas de estos. En la red de observación se han registrado pérdidas que han alcanzado los 5 cm en algunos enclaves. A pesar de ello, los espesores se encuentran por encima de lo que sería habitual a estas alturas de la temporada, más aún en los macizos orientales, donde las nevadas de días pasados depositaron cantidades importantes de nieve reciente en cotas altas, más modestas en el resto de macizos.

AEMET. Se autoriza la reproducción de su contenido citando la fuente.

El manto es continuo desde medianías en toda el área, aunque localmente, en enclaves menos soleados, la nieve sigue presente desde cotas bajas. Por encima de los 2100 metros, se superan los 120 a 200 cm.
En cotas medias y bajas, así como en solanas a mayor altitud, el manto presenta características primaverales, está humedecido en profundidad y las heladas tienden a encostrarlo durante las primeras horas. En altitudes superiores, la nieve se mantiene más seca, venteada y aún podríamos encontrar en umbrías de la alta montaña estratos débiles enterrados a gran profundidad, generalmente inactivos.

Evolución del manto y peligro de aludes para el miércoles, día 11

Problema de placas de viento en cotas altas. Problema de nieve reciente en umbrías de cotas altas. Problemas de nieve húmeda y deslizamientos basales en medianías y cotas bajas, así como en solanas a mayor altitud.

Durante la segunda mitad del día de mañana se esperan nuevas precipitaciones, que podrían sumar algunos nuevos centímetros de nieve reciente desde cotas medias, sin descartar que se puedan superar localmente los 5 cm en algunos enclaves de la alta montaña. Esto podría dar lugar a purgas de nieve reciente en zonas de acumulación suficientemente inclinadas de todas las orientaciones. Además, la nieve caída en días pasados continúa seca en umbrías de cotas altas, pudiendo todavía suceder aludes de nieve reciente en estos enclaves, de tamaño generalmente pequeño, aunque en los macizos orientales se podrían alcanzar dimensiones mayores. Estos se irán haciendo cada vez menos frecuentes y probables.

En la alta montaña, los vientos seguirán formando nuevas placas de viento en todas las orientaciones, preferentemente en las este y sur, que vendrán a sumarse a otras ya existentes que permanecen aún activas. Estas estructuras podrán fracturarse ante sobrecargas débiles, como es el paso de un esquiador, dando lugar a aludes de dimensiones pequeñas (1, capaz de desestabilizar a una persona) o medianas (2, capaz de enterrar a una persona) en los macizos occidentales, y pudiendo alcanzar el tamaño grande en los macizos orientales (3, capaz de enterrar a un grupo de personas). Tampoco se descarta que pueda reactivarse alguna capa débil persistente, especialmente en zonas de manto más delgado o erosionado, en cuyo caso también sería posible el desencadenamiento de aludes de tamaño localmente grande.

En cotas medias y bajas, así como en solanas a mayor altitud, el manto se encuentra muy húmedo hasta la base, por lo que serán muy probables los aludes de nieve húmeda, de tamaño pequeño o mediano. La formación de costras de rehielo podrá aportar al manto cierta estabilidad temporal, que desaparecerá con el calentamiento diurno. En superficies herbosas o de roca lisa serán probables los deslizamientos basales, capaces de arrastrar una gran cantidad de nieve y alcanzar el tamaño grande.

Predicción meteorológica para el miércoles, día 11

Nuboso o con intervalos nubosos. Periodos de visibilidad localmente reducida. Se esperan precipitaciones débiles o localmente moderadas, preferentemente durante la segunda mitad del día, en el Arán, en la franja norte de la Pallaresa y en el Ripollès, sin descartarse en el resto de macizos, de manera más dispersa y ocasional. Cota de nieve en ascenso en torno a unos 1500-1900 metros, alcanzando los valores máximos por la tarde y volviendo a descender a últimas horas. Temperaturas sin cambios o en ligero ascenso, localmente moderado en las

AEMET. Se autoriza la reproducción de su contenido citando la fuente.

máximas de algunas áreas. Heladas débiles, moderadas en cotas altas. Soplarán vientos flojos o moderados, con predominio de la componente oeste, girando a componente norte por la tarde a medida que se irán intensificando. No se descartan rachas fuertes.

Datos en la atmósfera libre:

Altitud de la isoterma de 0 ºC: 2300 m
Altitud de la isoterma de -10 ºC: 3800 m

Viento a 1500 m: VRB 5 km/h
Viento a 3000 m: W 25 km/h

Evolución para el jueves día 12

Nivel de peligro con pocos cambios.

Escala europea de peligro de aludes

Débil Limitado Notable Fuerte Muy Fuerte

Problemas de aludes

Nieve reciente Placas de viento Capas débiles persistentes Nieve húmeda Deslizamientos basales Sin problema evidente

Nota1: Se recuerda que, siempre que haya nieve, la ausencia total de peligro no existe. Hay que tener presente que en circunstancias desfavorables, con aludes de tamaño 1 (alud pequeño o colada) y tamaño 2 (alud mediano), se pueden sufrir severos daños personales.

Nota2: Los BPA se elaboran en base a información meteorológica así como al estado del manto nivoso a través de sondeos puntuales. Se advierte a los usuarios de la variabilidad de esta información al extrapolarla a zonas extensas de montaña. Por ello, AEMET no se hace responsable de su uso para la toma de decisiones que conciernen a la seguridad personal, ni de los riesgos físicos o materiales de ellas derivadas.

AEMET. Se autoriza la reproducción de su contenido citando la fuente.