GOBIERNO DE ESPAÑA
VICEPRESIDENCIA TERCERA DEL GOBIERNO
MINISTERIO PARA LA TRANSICIÓN ECOLÓGICA Y EL RETO DEMOGRÁFICO

Boletín de información nivológica y de peligro de aludes

Pirineo Navarro y Aragonés

aemet Agencia Estatal de Meteorología

martes, 10 de marzo de 2026

Pronóstico hasta las 24 horas del miércoles, día 11 de marzo

(Válido fuera de pistas de esquí balizadas y abiertas)

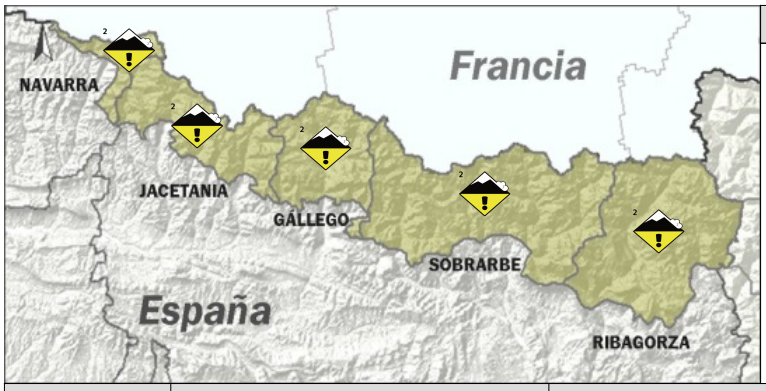

Problemas de aludes

Deslizamientos basales

Placas de viento

Macizo	Peligro	Problemas de aludes, cota, orientación, tamaño	Innivación observada (m)
Navarra	2 — Limitado	**Deslizamientos basales** 2300 N O E S 2 **Placas de viento** 2200 N O E S 2	2026-03-10 N S Cota más baja caras N
Jacetania	2 — Limitado	**Deslizamientos basales** 2300 N O E S 2 **Placas de viento** 2200 N O E S 2	2026-03-10 N S Cota más baja caras N
Gállego	2 — Limitado	**Deslizamientos basales** 2300 N O E S 2 **Placas de viento** 2200 N O E S 2	2026-03-10 N S Cota más baja caras N

AEMET. Se autoriza la reproducción de su contenido citando la fuente.

Boletín de información nivológica y de peligro de aludes

Pirineo Navarro y Aragonés

Sobrarbe	2 **Limitado**	**Deslizamientos basales** 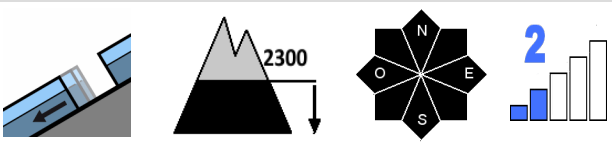 **Placas de viento** 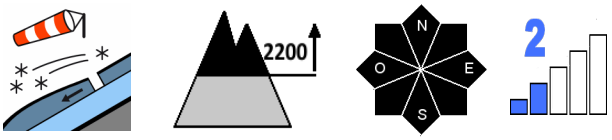	2026-03-10 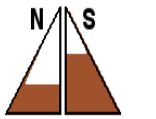 Cota más baja caras N
Ribagorza	2 **Limitado**	**Deslizamientos basales** 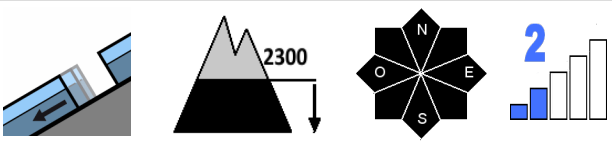 **Placas de viento** 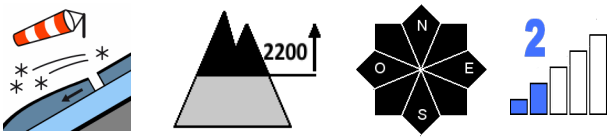	2026-03-10 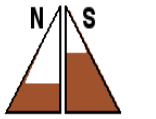 Cota más baja caras N

Estado del manto y observaciones recientes

Ayer se registraron algunas nevadas débiles puntuales, con cota de nieve en torno a unos 1400-1600 metros, que en todo caso han podido sumar del entorno de 1-2 cm en algunos enclaves localizados de cotas altas. En la red de observación se han registrado pérdidas de espesor que han alcanzado los 15 cm en algunos puntos. El manto es continuo desde los 1700-1600 metros en solanas y desde los 1500-1400 metros en umbrías. En medianías la nieve es abundante, con espesores que van incrementando conforme ascendemos, rondando los 120-160 cm a unos 1700-1800 metros y pudiendo superar los 200 cm a unos 2100 metros, cantidades que pueden ser notablemente mayores en ventisqueros, hoyas y otras zonas propensas a la acumulación, donde se pueden llegar a alcanzar los 4 metros.

El manto está humedecido hasta su base en cotas medias y bajas, por debajo de unos 2200-2300 metros aproximadamente, normalmente con una capa de nieve más reciente en superficie, depositada durante las últimas nevadas, que se está transformando rápidamente. En las solanas, el manto esta sometido a ciclo de fusión-rehielo diario. Es en la alta montaña donde la nieve se presenta generalmente más seca y está muy venteada, observándose la presencia de placas de viento que descansan sobre los estratos de polvo sahariano depositados durante el episodio de calima de días pasados, a la vez que aflora la nieve marrón en las zonas erosionadas por el viento. Se han identificado capas débiles superficiales acompañando a los estratos de polvo, que no muestran gran reactividad a los tests. Aún podemos encontrar en umbrías de la alta montaña estratos débiles ubicados a considerable profundidad, y que se encuentran, por lo general, inactivos. Cabe destacar que el proceso de humidificación del manto está siendo muy intenso, debido a la acción de las nieblas.

Hoy se ha reportado un deslizamiento basal y un alud de nieve húmeda, ambos naturales y de tamaño 2 (mediano).

AEMET. Se autoriza la reproducción de su contenido citando la fuente.

Evolución del manto y peligro de aludes para el miércoles, día 11

Problema de placas de viento en cotas altas. Problema de nieve reciente en umbrías de cotas altas. Problemas de deslizamientos basales y nieve húmeda en medianías y cotas bajas, así como en solanas a mayor altitud.

Durante la segunda mitad del día de mañana se esperan nuevas precipitaciones, que podrían sumar algunos nuevos centímetros de nieve reciente desde cotas medias, sin descartar que en los macizos occidentales se puedan alcanzar los 5-10 cm en algunos enclaves de cotas altas. Esto podría dar lugar a purgas de nieve reciente en zonas de acumulación suficientemente inclinadas. Además, la nieve caída en días pasados continúa seca en umbrías de cotas altas, pudiendo todavía suceder aludes de nieve reciente en estos enclaves, de tamaño generalmente pequeño, localmente mediano.

En la alta montaña, los vientos seguirán formando nuevas placas de viento en todas las orientaciones, preferentemente en las este y sur, que vendrán a sumarse a otras ya existentes que permanecen aún activas. Estas estructuras podrán fracturarse ante sobrecargas débiles, como es el paso de un esquiador, dando lugar a aludes de dimensiones pequeñas (1, capaz de desestabilizar a una persona) o medianas (2, capaz de enterrar a una persona), por lo que se recomienda tomar precauciones si se va a transitar por la zona. Tampoco se descarta que pueda reactivarse alguna capa débil persistente, especialmente en zonas de manto más delgado o erosionado, en cuyo caso sería posible el desencadenamiento de aludes de tamaño localmente grande (3, capaz de enterrar a un grupo de personas).

En cotas medias y bajas, así como en solanas a mayor altitud, el manto se encuentra muy húmedo hasta la base, por lo que serán muy probables los aludes de nieve húmeda, de tamaño pequeño o mediano. La formación de costras de rehielo podrá aportar al manto cierta estabilidad temporal, que desaparecerá con el calentamiento diurno. En superficies herbosas o de roca lisa serán probables los deslizamientos basales, capaces de arrastrar una gran cantidad de nieve y alcanzar el tamaño grande.

Predicción meteorológica para el miércoles, día 11

Pirineo navarro:
Intervalos nubosos de madrugada, tendiendo a muy nuboso o cubierto. Periodos de visibilidad localmente reducida. Se esperan precipitaciones débiles o localmente moderadas, preferentemente durante la segunda mitad del día. Cota de nieve en torno a unos 1600-1900 metros, alcanzando los valores máximos por la tarde. Temperaturas mínimas en ligero o moderado ascenso. Máximas con pocos cambios. Heladas débiles en cotas altas. Soplarán vientos flojos o moderados del sur y suroeste, girando a componente norte por la tarde, a medida que se irán intensificando. No se descartan rachas fuertes.

Pirineo aragonés:
Nuboso de madrugada, tendiendo a muy nuboso o cubierto. Periodos de visibilidad localmente reducida. Se esperan precipitaciones débiles o localmente moderadas, preferentemente durante la segunda mitad del día y en zonas próximas a la divisoria con Francia, más generalizadas en la Jacetania. Cota de nieve en torno a unos 1600-1900 metros, alcanzando los valores máximos por la tarde. Temperaturas sin cambios o en ligero ascenso, salvo las mínimas de los macizos occidentales, que ascenderán moderadamente. Heladas débiles o moderadas, localmente fuertes en cumbres. Soplarán vientos flojos o moderados de

AEMET. Se autoriza la reproducción de su contenido citando la fuente.

componentes oeste y sur, girando a componente norte por la tarde, a medida que se irán intensificando. En cotas altas soplará flojo del sudoeste girando a moderado del noroeste. Probables rachas de viento fuerte en cotas altas y zonas expuestas.

Datos en la atmósfera libre:

Altitud de la isoterma de 0 ºC: 2100 m
Altitud de la isoterma de -10 ºC: 3800 m

Viento a 1500 m: W 10 km/h
Viento a 3000 m: W 30 km/h

Evolución para el jueves día 12

Nivel de peligro con pocos cambios.

(Información elaborada a partir de los datos recibidos de los refugios de Linza, Lizara, Panticosa, Góriz, Pineta, Estós, Angel Orús, Cap de Llauset y Belagua, de las estaciones de esquí de Formigal y Panticosa (lagos), de la estación de esquí de fondo de Llanos del Hospital y de Ordesa Pradera)

Escala europea de peligro de aludes

Débil | Limitado | Notable | Fuerte | Muy Fuerte

Problemas de aludes

Nieve reciente | Placas de viento | Capas débiles persistentes | Nieve húmeda | Deslizamientos basales | Sin problema evidente

Nota1: Se recuerda que, siempre que haya nieve, la ausencia total de peligro no existe. Hay que tener presente que en circunstancias desfavorables, con aludes de tamaño 1 (alud pequeño o colada) y tamaño 2 (alud mediano), se pueden sufrir severos daños personales.

Nota2: Los BPA se elaboran en base a información meteorológica así como al estado del manto nivoso a través de sondeos puntuales. Se advierte a los usuarios de la variabilidad de esta información al extrapolarla a zonas extensas de montaña. Por ello, AEMET no se hace responsable de su uso para la toma de decisiones que conciernen a la seguridad personal, ni de los riesgos físicos o materiales de ellas derivadas.

AEMET. Se autoriza la reproducción de su contenido citando la fuente.