ICGC Institut Cartogràfic i Geològic de Catalunya

Servei Meteorològic de Catalunya meteo.cat

Boletín de peligro de aludes para el Pirineo de Catalunya
Del 10/03/2026 al 11/03/2026

(Válido fuera pistas de esquí y zonas no controladas)

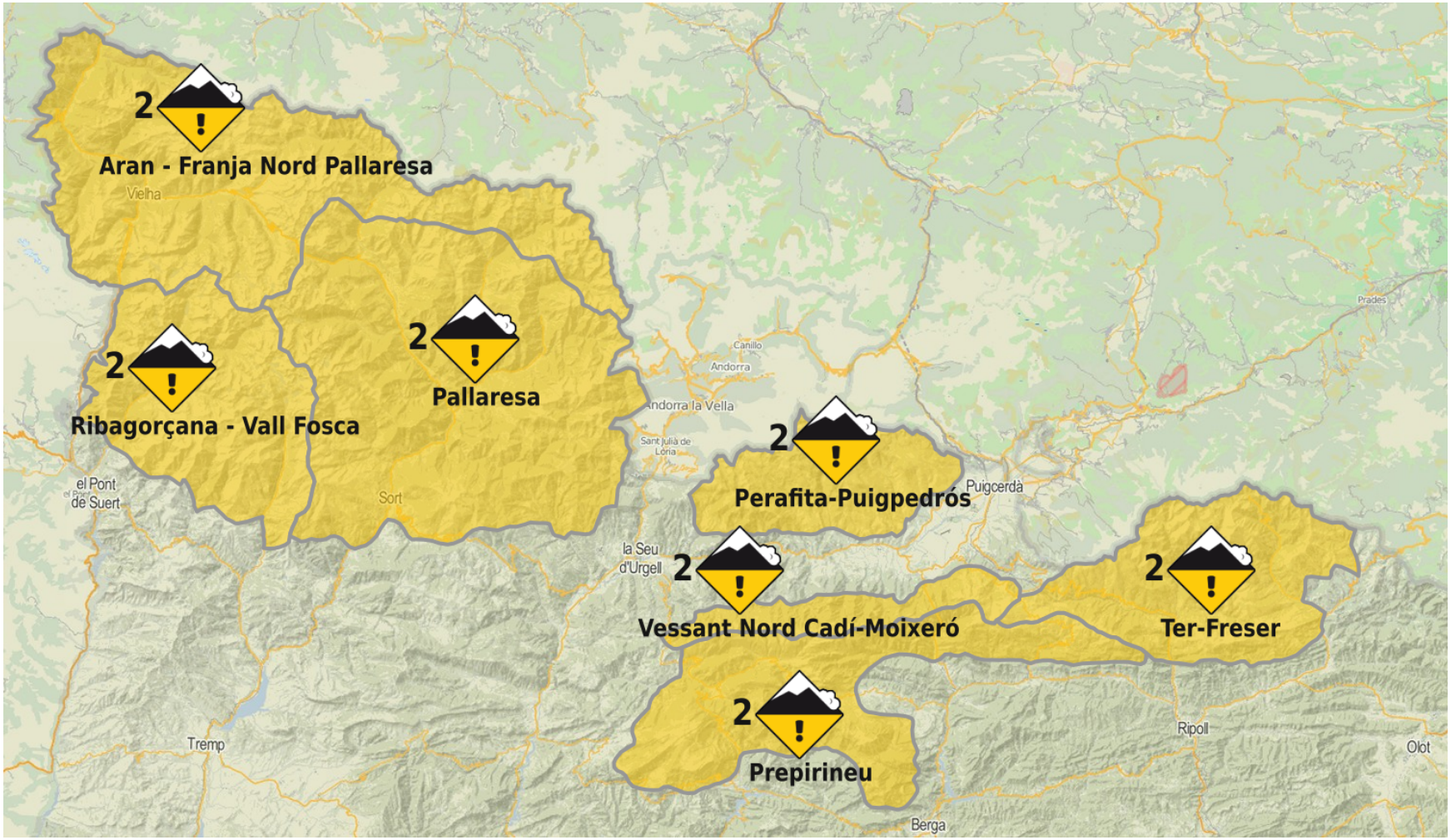

5 MUY FUERTE	4 FUERTE	3 NOTABLE	2 LIMITADO	1 DÉBIL

ICGC Institut Cartogràfic i Geològic de Catalunya

meteo.cat Servei Meteorològic de Catalunya

Boletín de peligro de aludes Aran - Franja Nord Pallaresa Del 10/03/2026 al 11/03/2026

(Válido fuera pistas de esquí y zonas no controladas)

LIMITADO (2)

Situación primaria

Nieve venteada

Distribución

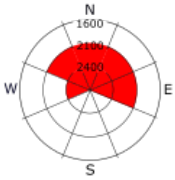

Tamaño

Origen

Tendencia

Situación secundaria

Nieve húmeda

Distribución

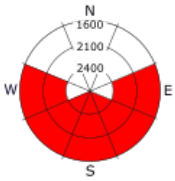

Tamaño

Origen

Tendencia

Estado del manto nivoso

Se ha observado caída de bolas y aludes pequeños de nieve húmeda en solanas. La nieve del último episodio sigue seca en umbrías de cota alta con niveles débiles internos, y se ha formado escarcha de superficie, mientras que en solanas el manto se va humedeciendo en las horas centrales del día y se rehiela por la noche y madrugada.
Las placas, blandas en general, localizadas principalmente en umbrías de cotas altas, podrán ceder por sobrecarga y desencadenar aludes que podrían alcanzar tamaño 2, medio, en general.
También son probables la caída de bolas y aludes de nieve húmeda naturales en orientaciones E, W y sobre todo S, en laderas de fuerte inclinación y más probables bajo árboles y resaltos rocosos, a partir de mediodía y especialmente en cota baja o media. Serán aludes de tamaño 1, pequeños, por lo general, puntualmente de tamaño 2, medio. No se descarta todavía la posibilidad de algún deslizamiento basal, principalmente en cotas bajas o medias.

Distribución del manto nivoso

Hay nieve por encima de unos 1.400-1-500 m en umbrías y 1.700 m en solanas. Los espesores a unos 2.200 m son superiores a los normales en la Franja Nord de la Pallaresa y en la mitad sur del Aran donde rondan los 180-220 cm. En la mitad norte de Arán hay unos 120-140 cm de grosor total.

Tendencia para las próximas 48-72h

Las débiles precipitaciones no variarán la estabilidad del manto. Peligro ESTACIONARIO.

El próximo boletín será emitido el día 2026-03-11

5 MUY FUERTE	4 FUERTE	3 NOTABLE	2 LIMITADO	1 DÉBIL

EAWS EUROPEAN AVALANCHE WARNING SERVICES

ICGC Institut Cartogràfic i Geològic de Catalunya

meteo.cat Servei Meteorològic de Catalunya

Boletín de peligro de aludes Ribagorçana - Vall Fosca Del 10/03/2026 al 11/03/2026

(Válido fuera pistas de esquí y zonas no controladas)

LIMITADO (2)

Situación primaria

Nieve venteada

Distribución

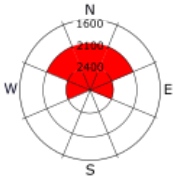

Tamaño

Origen

Tendencia

Situación secundaria

Nieve húmeda

Distribución

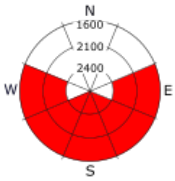

Tamaño

Origen

Tendencia

Estado del manto nivoso

Se ha observado actividad de aludes pequeños de nieve húmeda. Ayer se produjeron chubascos locales de nieve granulada. La nieve del último episodio sigue seca en umbrías de cota alta y se va asentando gradualmente, mientras que en solanas el manto se va humedeciendo en las horas centrales del día y se regela por la noche y madrugada.

Las placas, blandas en general, localizadas principalmente en umbrías de cotas altas, podrán ceder al paso de una persona y desencadenar aludes que podrían alcanzar tamaño 2, medio, localmente mayores.

También son probables caída de bolas y aludes de nieve húmeda naturales en orientaciones E, W y sobre todo S, en laderas de fuerte inclinación y más probables bajo árboles y resaltos rocosos, a partir de mediodía, cuando la costra superficial empiece a derretirse. Serán aludes de tamaño 1, pequeños, por lo general, puntualmente de tamaño 2, medio.

Distribución del manto nivoso

Hay nieve en el suelo a 1.600 m en terreno umbrío, y por encima de unos 1.800 m en laderas soleadas. El manto es esquiable por encima de unos 1.700-1.800 m en umbrías. Los grosores alcanzan los 100-130 cm a unos 2.200 m. Estos valores son superiores a los normales para la época.

Tendencia para las próximas 48-72h

Las placas se irán asentando y el humedecimiento del manto se podrá incrementar. Peligro ESTACIONARIO o en LEVE DESCENSO.

El próximo boletín será emitido el día 2026-03-11

5 MUY FUERTE	4 FUERTE	3 NOTABLE	2 LIMITADO	1 DÉBIL

EAWS EUROPEAN AVALANCHE WARNING SERVICES

ICGC Institut Cartogràfic i Geològic de Catalunya

Servei Meteorològic de Catalunya meteo.cat

Boletín de peligro de aludes Pallaresa
Del 10/03/2026 al 11/03/2026

(Válido fuera pistas de esquí y zonas no controladas)

LIMITADO (2)

Situación primaria

Nieve venteada

Distribución

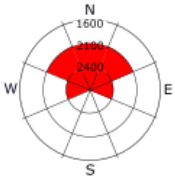

Tamaño

Origen

Tendencia

Situación secundaria

Nieve húmeda

Distribución

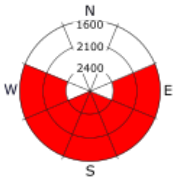

Tamaño

Origen

Tendencia

Estado del manto nivoso

Se han observado algunas purgas de nieve húmeda en el sector y caída de bolas. La nieve del último episodio sigue seca en umbrías de cota alta y se va asentando gradualmente, mientras que en solanas el manto se va humedeciendo en las horas centrales del día y se regela por la noche y madrugada.

Las placas, blandas en general, localizadas principalmente en umbrías de cotas altas, podrán ceder al paso de una persona y desencadenar aludes que podrían alcanzar tamaño 2, medio. No se descarta que en puntos de mayor sobreacumulación algún alud pudiera llegar a tamaño 3, grande.

También son probables caída de bolas y aludes de nieve húmeda naturales en orientaciones E, W y sobre todo S, en laderas de fuerte inclinación y más probables bajo árboles y resaltos rocosos, a partir de mediodía, cuando la costra superficial empiece a derretirse. Serán aludes de tamaño 1, pequeños, por lo general, puntualmente de tamaño 2, medio.

Distribución del manto nivoso

Hay nieve en el suelo a 1.600 m en terreno umbrío, y por encima de unos 1.800 m en laderas soleadas. El manto es esquiable por encima de unos 1.700-1.800 m en umbrías. Los espesores alcanzan los 120-160 cm en cotas medias.

Tendencia para las próximas 48-72h

Las placas se irán asentando y el humedecimiento del manto se podrá incrementar. Peligro ESTACIONARIO o en LEVE DESCENSO.

El próximo boletín será emitido el día 2026-03-11

5 MUY FUERTE	4 FUERTE	3 NOTABLE	2 LIMITADO	1 DÉBIL

EAWS EUROPEAN AVALANCHE WARNING SERVICES

ICGC Institut Cartogràfic i Geològic de Catalunya

meteo.cat Servei Meteorològic de Catalunya

Boletín de peligro de aludes Perafita-Puigpedrós Del 10/03/2026 al 11/03/2026

(Válido fuera pistas de esquí y zonas no controladas)

LIMITADO (2)

Situación primaria

Nieve venteada

Distribución

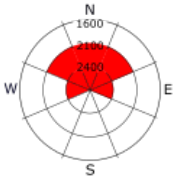

Tamaño

Origen

Tendencia

Situación secundaria

Nieve húmeda

Distribución

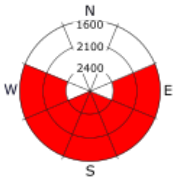

Tamaño

Origen

Tendencia

Estado del manto nivoso

La nieve del último episodio sigue seca en umbrías de cota alta y se va asentando gradualmente, mientras que en solanas el manto se va humedeciendo en las horas centrales del día.
Las placas, blandas en general, localizadas principalmente en umbrías de cotas altas, podrán ceder al paso de una persona y desencadenar aludes que podrían alcanzar tamaño 2, medio.
También son probables aludes de nieve húmeda naturales y caída de bolas en orientaciones E, W y sobre todo S, en laderas de fuerte inclinación y más probables bajo árboles y resaltes rocosos, durante las horas centrales del día. Serán aludes de tamaño 1, pequeños, por lo general, puntualmente de tamaño 2, medio.

Distribución del manto nivoso

Hay nieve en el suelo por encima de unos 1.600-1.700 m. El manto es esquiable por encima de unos 1.800 m. Los espesores, aunque irregulares, rondan los 80-100 cm en cotas medias. Son grosores por encima de los habituales para la época.

Tendencia para las próximas 48-72h

Las placas se irán asentando y el humedecimiento del manto se podrá incrementar. Peligro ESTACIONARIO o en LEVE DESCENSO.

El próximo boletín será emitido el día 2026-03-11

5 MUY FUERTE	4 FUERTE	3 NOTABLE	2 LIMITADO	1 DÉBIL

EAWS EUROPEAN AVALANCHE WARNING SERVICES

ICGC Institut Cartogràfic i Geològic de Catalunya

Servei Meteorològic de Catalunya meteo.cat

Boletín de peligro de aludes
Vessant Nord Cadí-Moixeró
Del 10/03/2026 al 11/03/2026

(Válido fuera pistas de esquí y zonas no controladas)

LIMITADO (2)

Situación primaria

Nieve venteada

Distribución

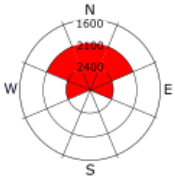

Tamaño

Origen

Tendencia

Situación secundaria

Nieve húmeda

Distribución

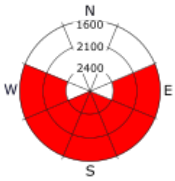

Tamaño

Origen

Tendencia

Estado del manto nivoso

La nieve del último episodio sigue seca en umbrías de cota alta y se va asentando gradualmente, mientras que en solanas el manto se va humedeciendo en las horas centrales del día.

Las placas, blandas en general, localizadas principalmente en umbrías de cotas altas, podrán ceder al paso de una persona y desencadenar aludes que podrían alcanzar tamaño 2, medio. En las canales con mayor sobreacumulación de nieve no se descarta que localmente por sobrecarga se pueda desencadenar algún alud que pueda alcanzar tamaño 3, grande.

También son probables aludes de nieve húmeda naturales en orientaciones E, W y sobre todo S, en laderas de fuerte inclinación y más probables bajo árboles y resaltes rocosos, durante las horas centrales del día. Serán aludes de tamaño 1, pequeños, por lo general, puntualmente de tamaño 2, medio.

Distribución del manto nivoso

En umbrías hay nieve por encima de 1.600 m, esquiable por encima de unos 1.700 m. En solanas la nieve está presente por encima de 1.800 m. Los grosores están alrededor de 160-180 cm a 2.200 m. Estos valores son muy excedentarios para la época del año.

Tendencia para las próximas 48-72h

Las placas se irán asentando y el humedecimiento del manto se podrá incrementar. Peligro ESTACIONARIO o en LEVE DESCENSO.

El próximo boletín será emitido el día 2026-03-11

5 MUY FUERTE	4 FUERTE	3 NOTABLE	2 LIMITADO	1 DÉBIL

EAWS EUROPEAN AVALANCHE WARNING SERVICES

ICGC Institut Cartogràfic i Geològic de Catalunya

meteo.cat Servei Meteorològic de Catalunya

Boletín de peligro de aludes Prepirineu
Del 10/03/2026 al 11/03/2026

(Válido fuera pistas de esquí y zonas no controladas)

LIMITADO (2)

Situación primaria

Nieve venteada

Distribución

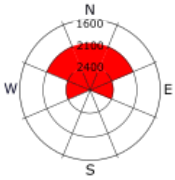

Tamaño

Origen

Tendencia

Situación secundaria

Nieve húmeda

Distribución

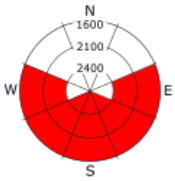

Tamaño

Origen

Tendencia

Estado del manto nivoso

La nieve del último episodio sigue seca en umbrías de cota alta y se va asentando gradualmente, mientras que en solanas el manto se va humedeciendo en las horas centrales del día.
Las placas, blandas en general, localizadas principalmente en umbrías de cotas altas, podrán ceder al paso de una persona y desencadenar aludes que podrían alcanzar tamaño 2, medio.
También son probables aludes de nieve húmeda naturales y caída de bolas en orientaciones E, W y sobre todo S, en laderas de fuerte inclinación y más probables bajo árboles y resaltes rocosos. Serán aludes de tamaño 1, pequeños, por lo general, puntualmente de tamaño 2, medio.

Distribución del manto nivoso

En umbrías hay nieve por encima de 1.600-1700 m. En solanas la nieve está presente por encima de 1.800-1.900 m. Los espesores, aunque irregulares, rondan los 60-80 cm en cotas medias.

Tendencia para las próximas 48-72h

Las placas se irán asentando y el humedecimiento del manto se podrá incrementar. Peligro ESTACIONARIO o en LEVE DESCENSO.

El próximo boletín será emitido el día 2026-03-11

5 MUY FUERTE	4 FUERTE	3 NOTABLE	2 LIMITADO	1 DÉBIL

EAWS EUROPEAN AVALANCHE WARNING SERVICES

ICGC Institut Cartogràfic i Geològic de Catalunya

Servei Meteorològic de Catalunya

Boletín de peligro de aludes Ter-Freser Del 10/03/2026 al 11/03/2026

(Válido fuera pistas de esquí y zonas no controladas)

LIMITADO (2)

Situación primaria

Nieve venteada

Distribución

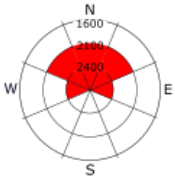

Tamaño

Origen

Tendencia

Situación secundaria

Nieve húmeda

Distribución

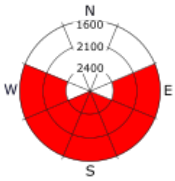

Tamaño

Origen

Tendencia

Estado del manto nivoso

Se han observado algunas purgas de nieve húmeda en el sector. La nieve del último episodio sigue seca en umbrías de cota alta y se va asentando gradualmente, mientras que en solanas el manto se va humedeciendo en las horas centrales del día. Las placas, blandas en general, localizadas principalmente en umbrías de cotas altas, podrán ceder al paso de una persona y desencadenar aludes que podrían alcanzar tamaño 2, medio. Localmente, en las cotas más altas, algún alud podría ser natural. En sectores muy puntuales y más favorables de acumulación no se descarta que algún alud pudiera llegar a tamaño 3, grande.

También son probables aludes de nieve húmeda naturales en orientaciones E, W y sobre todo S, en laderas de fuerte inclinación y más probables bajo árboles y resaltes rocosos, durante las horas centrales del día. Serán aludes de tamaño 1, pequeños, por lo general, puntualmente de tamaño 2, medio.

Distribución del manto nivoso

Hay nieve en el suelo por encima de 1.600-1.700 m. Es esquiable a partir de unos 1700 m. El manto nivoso presenta grosores muy excedentarios para la época del año. En lugares no afectados por el viento los grosores oscilan entre 80-100 cm a unos 2.000 m y más de 200 cm por encima de 2.400 m.

Tendencia para las próximas 48-72h

Las placas se irán asentando y el humedecimiento del manto se podrá incrementar. Peligro ESTACIONARIO o en LEVE DESCENSO.

El próximo boletín será emitido el día 2026-03-11

5 MUY FUERTE	4 FUERTE	3 NOTABLE	2 LIMITADO	1 DÉBIL

EAWS EUROPEAN AVALANCHE WARNING SERVICES