BUTLLETÍ DEL PERILL D'ALLAUS DEL PRINCIPAT D'ANDORRA

Servei meteorològic nacional
Principat d'Andorra

Elaborat el 10/03/2026 16:00
Propera actualització 11/03/2026 a les 16h

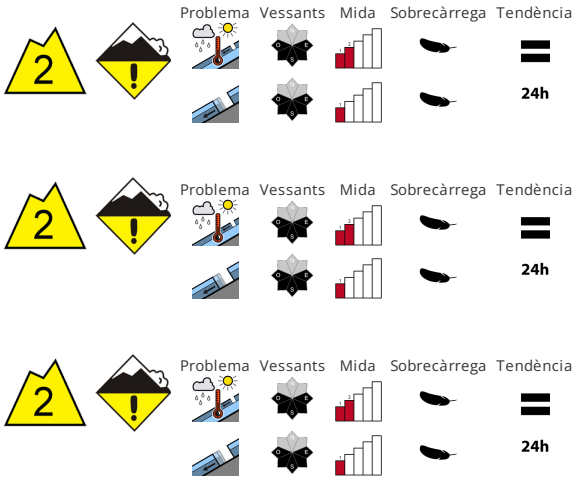

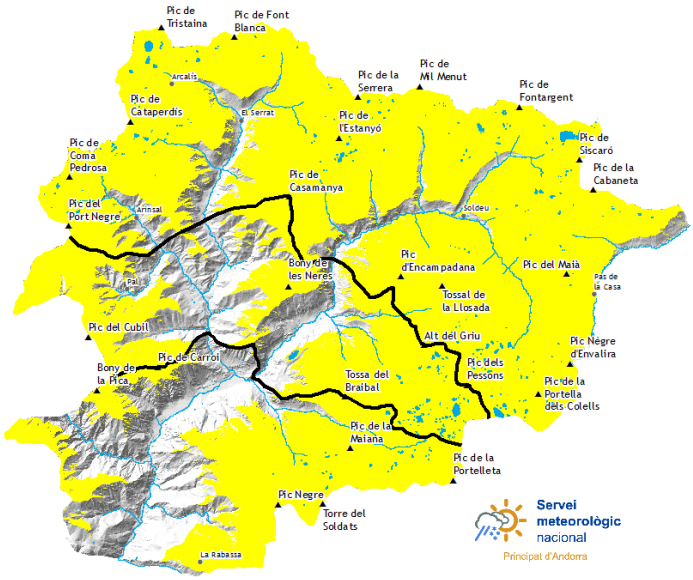

ESTABILITAT DEL MANTELL NIVAL

Amb la pujada de la temperatura i la radiació solar diürna, sobretot als vessants assolellats són possibles algunes allaus de neu humida de mida petita i mitjana. Aquestes poden desencadenar-se de manera natural. A més, són possibles allaus de lliscament basal en qualsevol moment. A cotes altes i als vessants obacs :. Les capes de neu a prop de la superfície poden ser desencadenades de manera aïllada i especialment amb sobrecàrregues fortes. El perill d'allaus romandrà invariable.

QUALITAT DE LA NEU

A cotes baixes :. La superfície del mantell de neu es regelarà per formar una crosta portant s'estovarà ja durant el matí. Evitar les zones amb esquerdes de lliscament basal. als vessants obacs i a cotes mitges i altes :. La part superior del mantell és seca, amb una superfície solta. Els gruixos de neu varien molt per sobre dels 2400 m aproximadament per la influència del vent. Les condicions són primaverals. Fins al divendres el temps serà parcialment assolellat. A partir de la tarda caurà neu per sobre dels 1200 m aproximadament sobretot als al nord.

GRUIXOS DEL MANTELL NIVAL FORA DE PISTA

Zona nord		Gruix neu		
Mantell Nival		1500m	2000m	2500m
N	1600 m	0 cm	150 cm	200 cm
S	1900 m	0 cm	100 cm	150 cm

Zona centre		Gruix neu		
Mantell Nival		1500m	2000m	2500m
N	1600 m	0 cm	150 cm	200 cm
S	1900 m	0 cm	100 cm	150 cm

Zona sud		Gruix neu		
Mantell Nival		1500m	2000m	2500m
N	1600 m	0 cm	120 cm	150 cm
S	1900 m	0 cm	60 cm	100 cm

Govern d'Andorra

EAWS EUROPEAN AVALANCHE WARNING SERVICES

Aquest butlletí ha estat elaborat seguint les normes i recomanacions de l'**European Avalanche Warning Services**, del qual el **Servei meteorològic Nacional** n'és membre

Informació detallada per espais naturals protegits

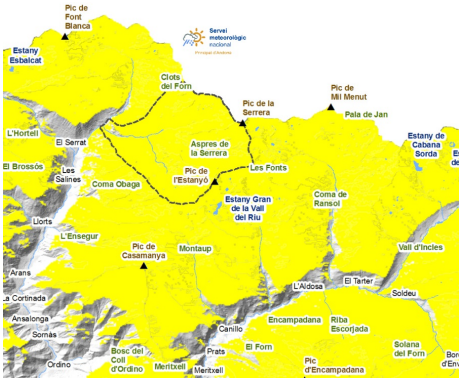

SORTENY

En altura, el vent ha transportat la poca neu disponible i ha format petites acumulacions irregulars i, sobretot als vessants nord, hi ha neu molt agradable d´esquiar. A les part baixes i en vessants assolellats la neu és dura al matí, es recomana anar equipat amb material de punxes per circular-hi, però s´estovarà al llarg del dia.

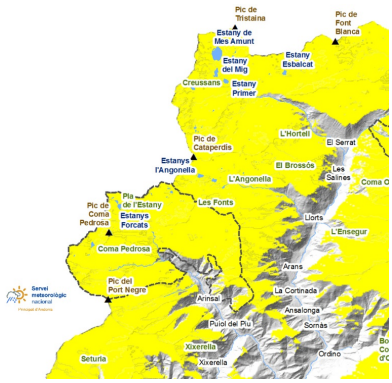

COMAPEDROSA

Cada vegada queda menys neu contínua a les cotes més baixes del Parc. A primeres hores haurem de vigilar a no relliscar a causa de la crosta de regel als vessants sud o a cotes baixes. A les parts altes del Parc, es poden fer nombroses excursions, sempre mantenint una elecció acurada de l´itinerari.

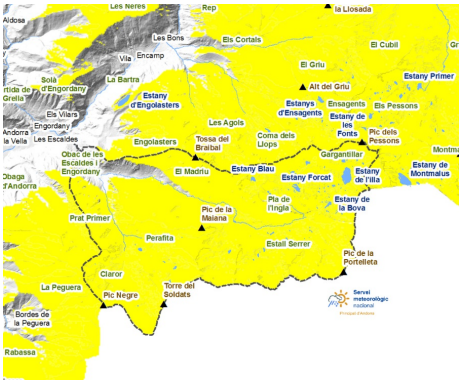

MADRIU-PERAFITA-CLAROR

El mantell és en general prim i irregular, amb millor continuïtat de neu als vessants nord i obacs. Ha estat el sector més afectat per les precipitacions, amb neu nova que és abundant per sobre del límit del bosc, tot i que en alguns indrets elevats el vent ha deixat la neu vella, al descobert.

BUTLLETÍ DEL PERILL D'ALLAUS DEL PRINCIPAT D'ANDORRA

Servei meteorològic nacional
Principat d'Andorra

Gruixos de neu nova dels darrers dies (de les últimes 24h mesurat a les 06:00h UTC)

	06/03/2026	07/03/2026	08/03/2026	09/03/2026
FEDA (Central)	0 cm	0 cm	0 cm	0 cm
Engolasters - FEDA	0 cm	0 cm	0 cm	0 cm
Bony de les Neres	2 cm	0 cm	0 cm	0 cm
Sorteny	5 cm	2 cm	6 cm	4 cm
Les Fonts d'Arinsal	5 cm	0 cm	4 cm	0 cm
Perafita	3 cm	0 cm	3 cm	0 cm
Tossa Espiolets	5 cm	0 cm	2 cm	0 cm
Grau Roig - FEDA	5 cm	0 cm	4 cm	1 cm
Fontverd	1 cm	0 cm	1 cm	0 cm
Ransol - FEDA	0 cm	0 cm	0 cm	0 cm
Caborreu	12 cm	0 cm	2 cm	0 cm
La Solana	4 cm	1 cm	5 cm	0 cm
Coll Pa	9 cm	0 cm	0 cm	0 cm
Envalira Antenes	13 cm	0 cm	9 cm	3 cm
Vall del Riu FEDA	5 cm	3 cm	3 cm	0 cm