BUTLLETÍ DEL PERILL D'ALLAUS DEL PRINCIPAT D'ANDORRA

Elaborado el 10/03/2026 16:00
Proxima actualización 11/03/2026 a las 16h

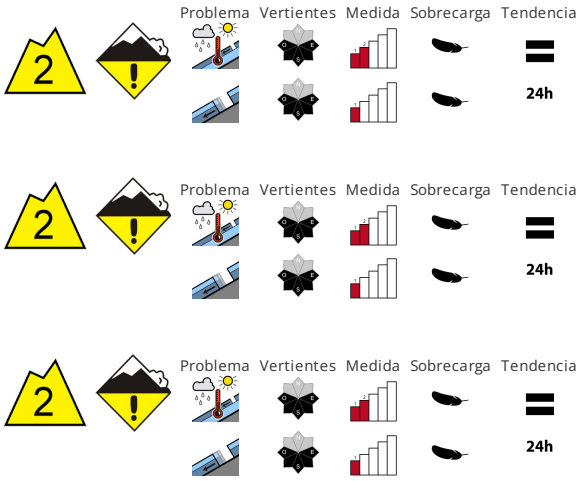

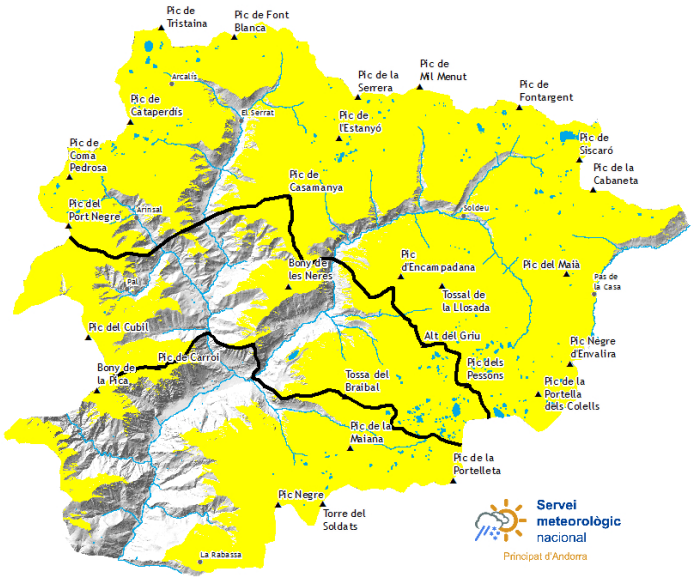

CALIDAD DE LA NIEVE

Con la subida de la temperatura y la radiación solar diurna, sobre todo en las laderas solanas son posibles algunas avalanchas de nieve húmeda de tamaño pequeño y mediano. Estos pueden desencadenarse de manera natural. Además son posibles aludes de deslizamiento basal en cualquier momento. En cotas altas y en las laderas umbrías :. Las capas de nieve cercanas a la superficie pueden ser desencadenadas de manera aislada y especialmente con sobrecargas fuertes. El peligro de aludes permanecerá invariable.

ESTABILIDAD DEL MANTO NIVOSO

En cotas bajas :. La superficie del manto de nieve se volverá a helar para formar una costra portante se ablandará ya durante la mañana. Evitar las zonas con grietas de deslizamiento basal. en las laderas umbrías y en cotas medias y altas :. La parte superior del manto es seca, con una superficie blanda. Los espesores de nieve varían mucho por encima de los 2400 m aproximadamente por la influencia del viento. Las condiciones son primaverales. Hasta el viernes el tiempo será parcialmente soleado. A partir de la tarde caerá nieve por encima de los 1200 m aproximadamente sobre todo en los norte.

ESPESORES DEL MANTO NIVOSO FUERA DE PISTA

Zona norte		Espesor nieve		
Manto Nival		1500m	2000m	2500m
N	1600 m	0 cm	150 cm	200 cm
S	1900 m	0 cm	100 cm	150 cm

zona centro		Espesor nieve		
Manto Nival		1500m	2000m	2500m
N	1600 m	0 cm	150 cm	200 cm
S	1900 m	0 cm	100 cm	150 cm

Zona sur		Espesor nieve		
Manto Nival		1500m	2000m	2500m
N	1600 m	0 cm	120 cm	150 cm
S	1900 m	0 cm	60 cm	100 cm

Govern d'Andorra

Aquest butlletí ha estat elaborat seguint les normes i recomanacions de l'**European Avalanche Warning Services**, del qual el **Servei meteorològic Nacional** n'és membre

BUTLLETÍ DEL PERILL D'ALLAUS DEL PRINCIPAT D'ANDORRA

Servei meteorològic nacional
Principat d'Andorra

Información detallada por espacios naturales protegidos

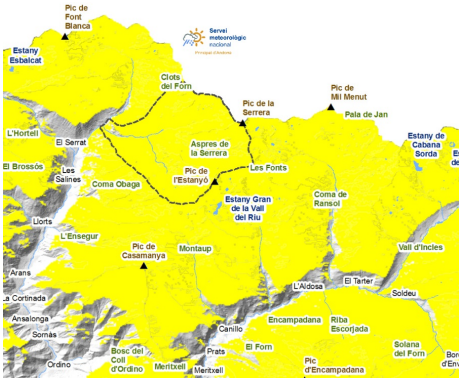

SORTENY

En altura, el viento ha transportado la poca nieve disponible y ha formado pequeñas acumulaciones irregulares y, sobre todo en las vertientes norte, hay nieve muy agradable de esquiar. En las partes bajas y en laderas soleadas la nieve es dura por la mañana, se recomienda ir equipado con material de pinchos para circular, pero se ablandará a lo largo del día.

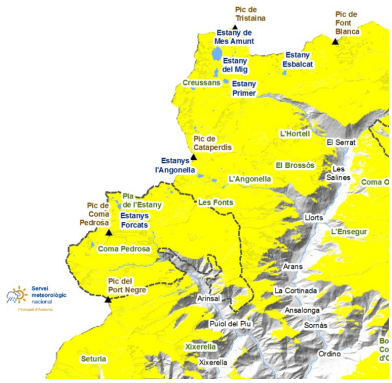

COMAPEDROSA

Cada vez queda menos nieve continua en las cotas más bajas del Parque. A primeras horas deberemos vigilar a no resbalar debido a la corteza de rehielo en las laderas sur o en cotas bajas. En las partes altas del Parque, se pueden realizar numerosas excursiones, siempre manteniendo una elección cuidadosa del itinerario.

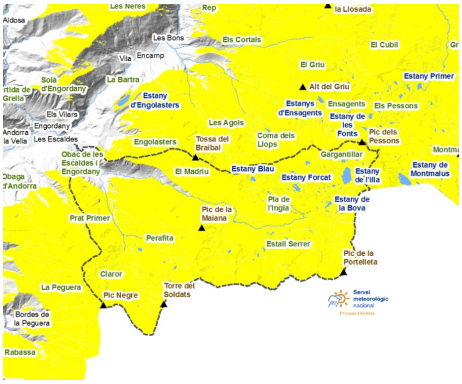

MADRIU-PERAFITA-CLAROR

El manto es en general delgado e irregular, con mejor continuidad de nieve en las vertientes norte y umbrías. Fue el sector más afectado por las precipitaciones, con nieve nueva que es abundante por encima del límite del bosque, aunque en algunos lugares elevados el viento dejó la nieve vieja, al descubierto.

Govern d'Andorra

EAWS
EUROPEAN AVALANCHE WARNING SERVICES

Aquest butlletí ha estat elaborat seguint les normes i recomanacions de l'**European Avalanche Warning Services**, del qual el **Servei meteorològic Nacional** n'és membre

BUTLLETÍ DEL PERILL D'ALLAUS DEL PRINCIPAT D'ANDORRA

Servei meteorològic nacional
Principat d'Andorra

Espesores de nieve nueva de los últimos días (de las ultimas 24h mesurado a las 06:00h UTC)

	06/03/2026	07/03/2026	08/03/2026	09/03/2026
FEDA (Central)	0 cm	0 cm	0 cm	0 cm
Engolasters - FEDA	0 cm	0 cm	0 cm	0 cm
Bony de les Neres	2 cm	0 cm	0 cm	0 cm
Sorteny	5 cm	2 cm	6 cm	4 cm
Les Fonts d'Arinsal	5 cm	0 cm	4 cm	0 cm
Perafita	3 cm	0 cm	3 cm	0 cm
Tossa Espiolets	5 cm	0 cm	2 cm	0 cm
Grau Roig - FEDA	5 cm	0 cm	4 cm	1 cm
Fontverd	1 cm	0 cm	1 cm	0 cm
Ransol - FEDA	0 cm	0 cm	0 cm	0 cm
Caborreu	12 cm	0 cm	2 cm	0 cm
La Solana	4 cm	1 cm	5 cm	0 cm
Coll Pa	9 cm	0 cm	0 cm	0 cm
Envalira Antenes	13 cm	0 cm	9 cm	3 cm
Vall del Riu FEDA	5 cm	3 cm	3 cm	0 cm