BUTLLETÍ DEL PERILL D'ALLAUS DEL PRINCIPAT D'ANDORRA

Préparé le 10/03/2026 16:00
Prochaine mise à jour le 11/03/2026 à 16h

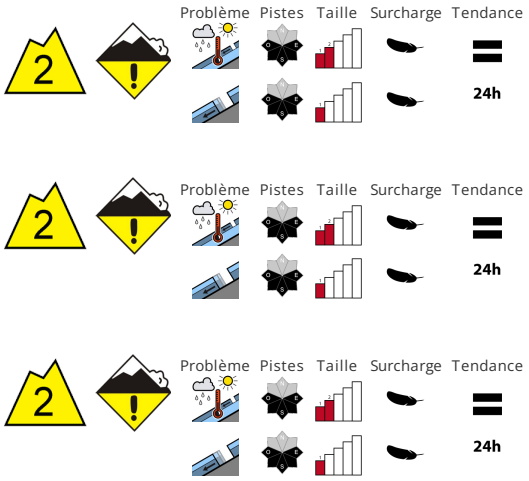

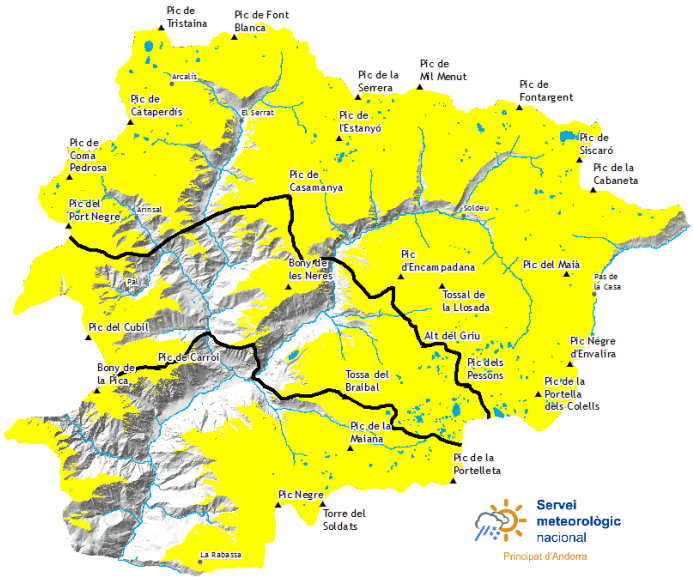

STABILITÉ DU MANTEAU NEIGEUX

Avec le réchauffement diurne et le rayonnement solaire de rares avalanches humides de petite et moyenne taille sont possibles surtout sur les pentes au soleil. Explication: celles-ci ne peut signifier que celles-ci avalanches peuvent se déclencher spontanément. En outre, des avalanches de glissement sont possibles à tout moment.. À haute altitude et sur les pentes à l'ombre (-):. Les couches de neige proches de la surface peuvent être déchaîné être déclenchées de manière isolée et généralement avec une surcharge importante. Le danger d'avalanches subsiste.

QUALITÈ DE LA NEIGE

À basse altitude (-):. La surface de la neige regèle et devient porteuse se ramollit dès la matinée.. Les zones présentant des fissures de glissement doivent être évitées.. sur les pentes à l'ombre et aux altitudes moyennes et élevées (-):. La zone supérieure du manteau neigeux est sèche , avec une surface meuble. On trouve suivant l'influence du vent des hauteurs de neiges très différentes au-dessus d'environ 2400 m. Les conditions sont printanières. Jusqu'à vendredi il fait un temps partiellement ensoleillé. À partir de l'après-midi il tombera de la neige au-dessus d'environ 1200 m surtout au nord.

EPAISSEUR DE NEIGE HORS PISTE

Zone nord		Epaisseur de neige		
Nival manteau		1500m	2000m	2500m
N	1600 m	0 cm	150 cm	200 cm
S	1900 m	0 cm	100 cm	150 cm

Zone centre		Epaisseur de neige		
Nival manteau		1500m	2000m	2500m
N	1600 m	0 cm	150 cm	200 cm
S	1900 m	0 cm	100 cm	150 cm

Zone sud		Epaisseur de neige		
Nival manteau		1500m	2000m	2500m
N	1600 m	0 cm	120 cm	150 cm
S	1900 m	0 cm	60 cm	100 cm

Govern d'Andorra

EAWS EUROPEAN AVALANCHE WARNING SERVICES

Aquest butlletí ha estat elaborat seguint les normes i recomanacions de l'**European Avalanche Warning Services**, del qual el **Servei meteorològic Nacional** n'és membre

BUTLLETÍ DEL PERILL D'ALLAUS DEL PRINCIPAT D'ANDORRA

Servei meteorològic nacional
Principat d'Andorra

Des informations détaillées par espace naturel protégé

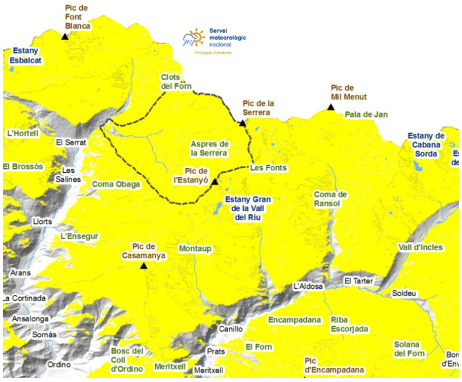

SORTENY

En altitude, le vent a transporté le peu de neige disponible et formé de petites accumulations irrégulières et, surtout sur le versant nord, la neige est très agréable pour skier. Dans les parties basses et sur les pentes ensoleillées, la neige est dure le matin, il est recommandé de s'équiper de matériel cramponné pour circuler, mais elle se ramollira au fil de la journée. , , ,

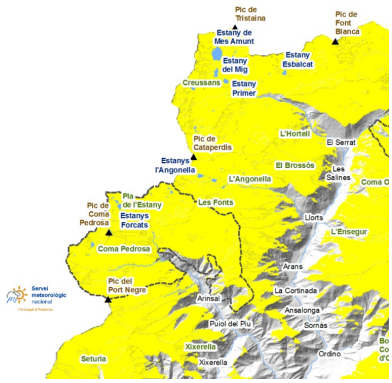

COMAPEDROSA

Il y a de moins en moins de neige continue aux basses altitudes du parc. Au petit matin, il faudra faire attention à ne pas glisser à cause de la croûte de glace sur les versants sud ou à basse altitude. Dans les parties supérieures du Parc, de nombreuses excursions peuvent être réalisées, en choisissant toujours avec soin l'itinéraire. , , , , ,

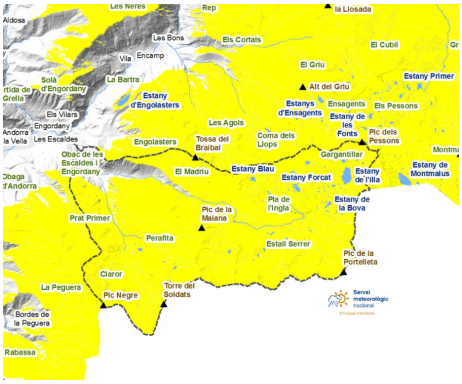

MADRIU-PERAFITA-CLAROR

Le manteau est généralement mince et irrégulier, avec une meilleure continuité neigeuse sur les versants nord et obscurs. C'est le secteur le plus touché par les précipitations, avec de la neige fraîche abondante au-dessus de la limite forestière, même si dans certains endroits élevés, le vent a laissé la vieille neige exposée. , , ,

Govern d'Andorra

EAWS
EUROPEAN AVALANCHE WARNING SERVICES

Aquest butlletí ha estat elaborat seguint les normes i recomanacions de l'**European Avalanche Warning Services**, del qual el **Servei meteorològic Nacional** n'és membre

BUTLLETÍ DEL PERILL D'ALLAUS DEL PRINCIPAT D'ANDORRA

Servei meteorològic nacional
Principat d'Andorra

Couche de neige fraiche des derniers jours (De 24 h mesurée à 06:00 h UTC)

	06/03/2026	07/03/2026	08/03/2026	09/03/2026
FEDA (Central)	0 cm	0 cm	0 cm	0 cm
Engolasters - FEDA	0 cm	0 cm	0 cm	0 cm
Bony de les Neres	2 cm	0 cm	0 cm	0 cm
Sorteny	5 cm	2 cm	6 cm	4 cm
Les Fonts d'Arinsal	5 cm	0 cm	4 cm	0 cm
Perafita	3 cm	0 cm	3 cm	0 cm
Tossa Espiolets	5 cm	0 cm	2 cm	0 cm
Grau Roig - FEDA	5 cm	0 cm	4 cm	1 cm
Fontverd	1 cm	0 cm	1 cm	0 cm
Ransol - FEDA	0 cm	0 cm	0 cm	0 cm
Caborreu	12 cm	0 cm	2 cm	0 cm
La Solana	4 cm	1 cm	5 cm	0 cm
Coll Pa	9 cm	0 cm	0 cm	0 cm
Envalira Antenes	13 cm	0 cm	9 cm	3 cm
Vall del Riu FEDA	5 cm	3 cm	3 cm	0 cm