ALPI GIULIE

Bollettino Valanghe N. 370/2026 del 10/03/2026 ore 14.00
Validità 48 ore prossima emissione 11/03/2026
A cura del Servizio METEOMONT dell'ARMA dei CARABINIERI
In collaborazione con Servizio Meteorologico dell'Aeronautica militare

SITUAZIONE alle 14:00 del 10/03/2026

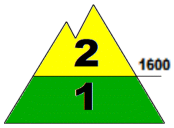

SITUAZIONE TIPO: passaggio da poca a molta neve.



SITUAZIONE TIPO: situazione primaverile.

Quota neve (mslm)	Nord	Sud
	900 - 1000	1300 - 1800

Altezza Neve (cm)	Neve al suolo	Neve Fresca	Quota (mslm)
	94	000	1750
	30	00	875

VALANGHE OSSERVATE: Nessuna valanga.

PREVISIONI 11/03/2026

GRADO DI PERICOLO: MODERATO 2

SITUAZIONE TIPO: passaggio da poca a molta neve.

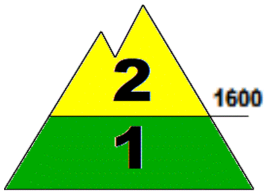

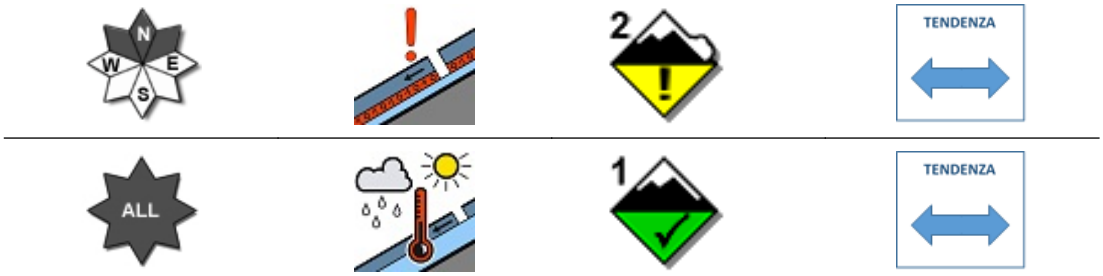

SITUAZIONE TIPO: situazione primaverile.

MANTO NEVOSO: La stabilità del manto nevoso è scarsa su alcuni punti (aree) per versanti settentrionali al di sopra di 1600 mslm, possibili valanghe di dimensioni medie.
La stabilità del manto nevoso è discreta su pochi punti (aree) per tutte le esposizioni al di sotto di 1600 mslm, possibili valanghe di dimensioni piccole.

AVVERTENZE

Il rialzo termico diurno richiede un'attenta valutazione temporale dell'escursione che eviti l'attraversamento di pendii ripidi nelle ore più calde della giornata.

SCALA EUROPEA DEL GRADO DI PERICOLO VALANGHE

LEGENDA PROBLEMA

Bollettino realizzato su scala sinottica-regionale (standard EAWS). La sua valutazione non può escludere in alcun modo la necessità di una seria e capace valutazione locale del pericolo (singolo pendio) che può essere anche sensibilmente diverso. Le previsioni meteorologiche sono relative all'orario UTC (per l'Italia +1 in inverno e +2 in estate).

ALPI GIULIE

PREVISIONE METEO

Quota		11/03/2026 h6:00	11/03/2026 h12:00	11/03/2026 h18:00
1000	Venti	02 Nodi da S-Ovest	02 Nodi da S-Ovest	02 Nodi da S-Ovest
	Temperature	+01 °C	+03 °C	+03 °C
	Temp.percepita	1 °C	3 °C	3 °C
2000	Venti	05 Nodi da S-Ovest	06 Nodi da S-Ovest	05 Nodi da S-Ovest
	Temperature	-02 °C	-01 °C	+00 °C
	Temp.percepita	-5 °C	-5 °C	-3 °C
3000	Venti	09 Nodi da Ovest	11 Nodi da Ovest	09 Nodi da Ovest
	Temperature	-06 °C	-06 °C	-06 °C
	Temp.percepita	-12 °C	-13 °C	-12 °C
Zero termico		1400-1600 m.	1700-1900 m.	1700-1900 m.
Fenomeno		—	—	—
Stato del cielo				

LEGENDA FENOMENI

— Assenza Fenomeni · Nebbia · Foschia · Pioggia debole · Pioggia moderata · Pioggia forte · Temporali

Nevicata debole · Nevicata moderata · Nevicata forte

STATO DEL CIELO

Sereno · Poco nuvoloso · Nuvoloso · Molto nuvoloso · Coperto

Parametri meteonivometrici registrati presso i campi di rilevamento il 10/03/2026.

Località	Comune	Quota (m.s.l.m.)	Altezza neve (cm)	Neve caduta nelle 24 ore (cm)	Temp. Min (°C)	Temp. Max (°C)	Condizioni del tempo
MALBORGHETTO - VAL SAISERA	Tarvisio (UD)	875	30	0	0	+14	Assenza di precipitazioni
PASSO PRAMOLLO	Pontebba (UD)	1530	93	0	-2	+9	Assenza di precipitazioni
MONTE LUSSARI	Tarvisio (UD)	1750	94	0	-1	+10	Assenza di precipitazioni
PASSO PREDIL	Tarvisio (UD)	1130	75	0	0	+9	Assenza di precipitazioni

(*) Rilievi fuori campo

L'INFORMAZIONE E' PREVENZIONE - LEGGI L'ATTUALE GRADO DI PERICOLO VALANGHE!

IL CAPO DEL CENTRO NAZIONALE METEOMONT
(Ten. Col. RFI Emanuela Gini)
FIRMA AUTOGRAFA OMESSA AI SENSI
DELL'ART.3 DEL D.LGS N.39/1993

Bollettino realizzato su scala sinottica-regionale (standard EAWS). La sua valutazione non può escludere in alcun modo la necessità di una seria e capace valutazione locale del pericolo (singolo pendio) che può essere anche sensibilmente diverso. Le previsioni meteorologiche sono relative all'orario UTC (per l'Italia +1 in inverno e +2 in estate).