MINISTERO DELLA DIFESA

meteomont
Servizio Nazionale di previsione neve e valanghe

EAWS EUROPEAN AVALANCHE WARNING SERVICES

CARABINIERI

## ALPI RETICHE

Bollettino Valanghe N. 371/2026 del 10/03/2026 ore 14.00
Validità 48 ore prossima emissione 11/03/2026

**A cura del Servizio METEOMONT dell'ARMA dei CARABINIERI**
**In collaborazione con Servizio Meteorologico dell'Aeronautica militare**

## SITUAZIONE alle 14:00 del 10/03/2026

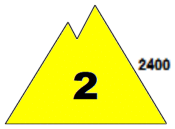


**SITUAZIONE TIPO: passaggio da poca a molta neve.**




**SITUAZIONE TIPO: situazione primaverile.**

| Quota neve (mslm) | Nord | Sud |
|---|---|---|
| | 1400 - 1500 | 1900 - 2500 |

| Altezza Neve (cm) | Neve al suolo | Neve Fresca | Quota (mslm) |
|---|---|---|---|
| | 60 | 0 | 2582 |
| | 43 | 0 | 1640 |

**VALANGHE OSSERVATE: Nessuna valanga.**

## PREVISIONI 11/03/2026

## GRADO DI PERICOLO: MODERATO 2

## SITUAZIONE TIPO: passaggio da poca a molta neve.

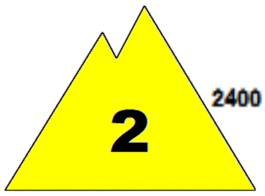


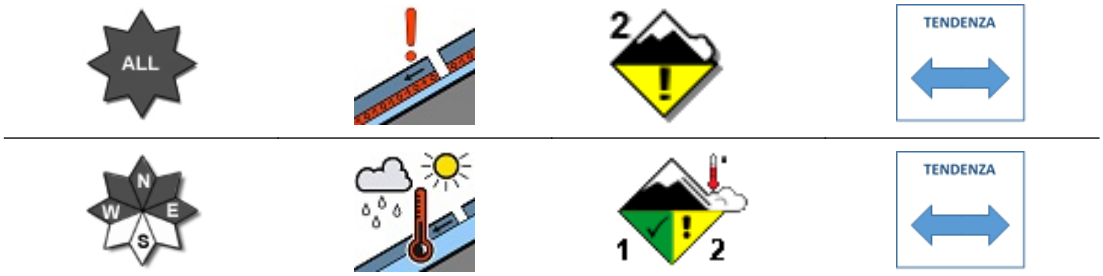


## SITUAZIONE TIPO: situazione primaverile.

**MANTO NEVOSO: La stabilità del manto nevoso è scarsa su alcuni punti (aree) per tutte le esposizioni al di sopra di 2400 mslm, possibili valanghe di dimensioni medie.**
**La stabilità del manto nevoso è scarsa su alcuni punti (aree) per versanti da ovest a est al di sotto di 2400 mslm, possibili valanghe di dimensioni medie.**

## AVVERTENZE

Viste le condizioni del manto nevoso, le attività al di fuori delle piste battute e segnalate richiedono ottime capacità di valutazione del pericolo locale.

## SCALA EUROPEA DEL GRADO DI PERICOLO VALANGHE

## LEGENDA PROBLEMA

**Bollettino realizzato su scala sinottica-regionale (standard EAWS). La sua valutazione non può escludere in alcun modo la necessità di una seria e capace valutazione locale del pericolo (singolo pendio) che può essere anche sensibilmente diverso. Le previsioni meteorologiche sono relative all'orario UTC (per l'Italia +1 in inverno e +2 in estate).**

MINISTERO DELLA DIFESA

meteomont
Servizio Nazionale di previsione neve e valanghe

EAWS EUROPEAN AVALANCHE WARNING SERVICES

CARABINIERI

# ALPI RETICHE

## PREVISIONE METEO

| Quota | | 11/03/2026 h6:00 | 11/03/2026 h12:00 | 11/03/2026 h18:00 |
|---|---|---|---|---|
| 1000 | Venti | *01 Nodi da N-Est* | *01 Nodi da S-Est* | *01 Nodi da Sud* |
| | Temperature | *-02 °C* | *-01 °C* | *-01 °C* |
| | Temp.percepita | *-2 °C* | *-1 °C* | *-1 °C* |
| 2000 | Venti | *01 Nodi da N-Est* | *01 Nodi da S-Est* | *01 Nodi da Sud* |
| | Temperature | *-02 °C* | *-01 °C* | *-01 °C* |
| | Temp.percepita | *-2 °C* | *-1 °C* | *-1 °C* |
| 3000 | Venti | *07 Nodi da S-Ovest* | *04 Nodi da S-Ovest* | *01 Nodi da Ovest* |
| | Temperature | *-08 °C* | *-07 °C* | *-07 °C* |
| | Temp.percepita | *-14 °C* | *-11 °C* | *-7 °C* |
| Zero termico | | *1600-1800 m.* | *1800-2000 m.* | *1800-2000 m.* |
| Fenomeno | | | — | — |
| Stato del cielo | | | | |

## LEGENDA FENOMENI

*Assenza Fenomeni* — *Nebbia* — *Foschia* — *Pioggia debole* — *Pioggia moderata* — *Pioggia forte* — *Temporali*

*Nevicata debole* — *Nevicata moderata* — *Nevicata forte*

## STATO DEL CIELO

*Sereno* — *Poco nuvoloso* — *Nuvoloso* — *Molto nuvoloso* — *Coperto*

## Parametri meteonivometrici registrati presso i campi di rilevamento il 10/03/2026.

| *Località* | *Comune* | *Quota (m.s.l.m.)* | *Altezza neve (cm)* | *Neve caduta nelle 24 ore (cm)* | *Temp. Min (°C)* | *Temp. Max (°C)* | *Condizioni del tempo* |
|---|---|---|---|---|---|---|---|
| **DOSSO DEL VALLONE** | Valfurva (SO) | 2582 | 60 | 2 | -7 | +4 | Assenza di precipitazioni |
| **SANTA APOLLONIA** | Vezza d'Oglio (BS) | 1599 | 9 | 0 | N.P. | N.P. | Assenza di precipitazioni |
| **ALPE PALU'** | Chiesa in Valmalenco (SO) | 2010 | 70 | 0 | -3 | +2 | Assenza di precipitazioni |
| **COLONIA VIGILI** | Ponte di Legno (BS) | 1640 | 43 | 0 | -2 | +7 | Assenza di precipitazioni |
| **RIFUGIO BOZZI *** | Ponte di Legno (BS) | 2671 | 44 | 0 | N.P. | N.P. | Nebbia con cielo non visibile |

**(*) Rilievi fuori campo**

**L'INFORMAZIONE E' PREVENZIONE - LEGGI L'ATTUALE GRADO DI PERICOLO VALANGHE!**

**IL CAPO DEL CENTRO NAZIONALE METEOMONT**
**(Ten. Col. RFI Emanuela Gini)**
**FIRMA AUTOGRAFA OMESSA AI SENSI**
**DELL'ART.3 DEL D.LGS N.39/1993**

**Bollettino realizzato su scala sinottica-regionale (standard EAWS). La sua valutazione non può escludere in alcun modo la necessità di una seria e capace valutazione locale del pericolo (singolo pendio) che può essere anche sensibilmente diverso. Le previsioni meteorologiche sono relative all'orario UTC (per l'Italia +1 in inverno e +2 in estate).**