MINISTERO DELLA DIFESA

meteomont Servizio Nazionale di previsione neve e valanghe

EAWS EUROPEAN AVALANCHE WARNING SERVICES

CARABINIERI

APPENNINO LIGURE

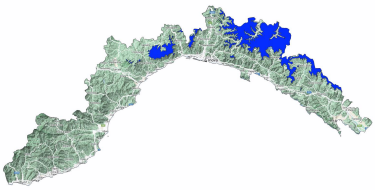

Bollettino Valanghe N. 246/2026 del 10/03/2026 ore 14.00
Validità 48 ore prossima emissione 11/03/2026

A cura del Servizio METEOMONT dell'ARMA dei CARABINIERI
In collaborazione con Servizio Meteorologico dell'Aeronautica militare

SITUAZIONE alle 14:00 del 10/03/2026

SITUAZIONE TIPO: neve pallottolare sepolta.

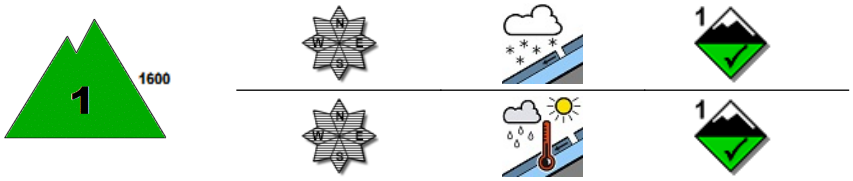

SITUAZIONE TIPO: pioggia su neve.

Quota neve (mslm)	Nord	Sud
	1400 - no neve	1600 - no neve

Altezza Neve (cm)	Neve al suolo	Neve Fresca	Quota (mslm)
	50	5	1700
	10	0	1500

VALANGHE OSSERVATE: Nessuna valanga.

PREVISIONI 11/03/2026

GRADO DI PERICOLO: DEBOLE 1

SITUAZIONE TIPO: neve pallottolare sepolta.



SITUAZIONE TIPO: pioggia su neve.

MANTO NEVOSO: La stabilità del manto nevoso è discreta su pochi punti (aree) per isolati pendii al di sopra di 1600 mslm, possibili valanghe di dimensioni piccole.
La stabilità del manto nevoso è discreta su pochissimi punti (aree) per isolati pendii al di sotto di 1600 mslm, possibili valanghe di dimensioni piccole.

AVVERTENZE

In considerazione delle avverse condizioni meteorologiche in atto, e della scarsa visibilità, risulterà difficoltosa l'individuazione dell'itinerario e della valutazione del singolo pendio.

SCALA EUROPEA DEL GRADO DI PERICOLO VALANGHE

LEGENDA PROBLEMA

Bollettino realizzato su scala sinottica-regionale (standard EAWS). La sua valutazione non può escludere in alcun modo la necessità di una seria e capace valutazione locale del pericolo (singolo pendio) che può essere anche sensibilmente diverso. Le previsioni meteorologiche sono relative all'orario UTC (per l'Italia +1 in inverno e +2 in estate).

APPENNINO LIGURE

PREVISIONE METEO

Quota		11/03/2026 h6:00	11/03/2026 h12:00	11/03/2026 h18:00
1000	Venti	03 Nodi da Sud	03 Nodi da S-Ovest	02 Nodi da Sud
	Temperature	+05 °C	+05 °C	+05 °C
	Temp.percepita	4 °C	4 °C	5 °C
2000	Venti	09 Nodi da S-Ovest	08 Nodi da S-Ovest	05 Nodi da S-Ovest
	Temperature	+00 °C	-01 °C	+00 °C
	Temp.percepita	-5 °C	-6 °C	-3 °C
3000	Venti	09 Nodi da S-Ovest	08 Nodi da Ovest	07 Nodi da Ovest
	Temperature	-06 °C	-06 °C	-06 °C
	Temp.percepita	-12 °C	-12 °C	-11 °C
Zero termico		1800-2000 m.	1800-2000 m.	1900-2100 m.
Fenomeno			—	
Stato del cielo				

LEGENDA FENOMENI

— Assenza Fenomeni · Nebbia · Foschia · Pioggia debole · Pioggia moderata · Pioggia forte · Temporali

Nevicata debole · Nevicata moderata · Nevicata forte

STATO DEL CIELO

Sereno · Poco nuvoloso · Nuvoloso · Molto nuvoloso · Coperto

Parametri meteonivometrici registrati presso i campi di rilevamento il 10/03/2026.

Località	Comune	Quota (m.s.l.m.)	Altezza neve (cm)	Neve caduta nelle 24 ore (cm)	Temp. Min (°C)	Temp. Max (°C)	Condizioni del tempo
CATOCCIA - VASCHE DI TIGLIETO	Rossiglione (GE)	722	0	0	N.P.	N.P.	Pioggia moderata
PRATO DEL PRINCIPE	Santo Stefano d'Aveto (GE)	1386	0	0	-3	+9	Assenza di precipitazioni
MONTE BUE *	Santo Stefano d'Aveto (GE)	1720	57	Tracce di neve	N.P.	N.P.	Rovescio a grandine o neve arrotondata

(*) Rilievi fuori campo

L'INFORMAZIONE E' PREVENZIONE - LEGGI L'ATTUALE GRADO DI PERICOLO VALANGHE!

IL CAPO DEL CENTRO NAZIONALE METEOMONT
(Ten. Col. RFI Emanuela Gini)
FIRMA AUTOGRAFA OMESSA AI SENSI
DELL'ART.3 DEL D.LGS N.39/1993