MINISTERO DELLA DIFESA

meteomont Servizio Nazionale di previsione neve e valanghe

EAWS EUROPEAN AVALANCHE WARNING SERVICES

CARABINIERI

AERONAUTICA MILITARE SERVIZIO METEOROLOGICO

P.N. ABRUZZO

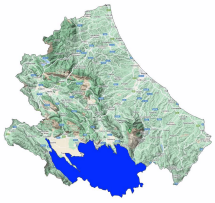

Bollettino Valanghe N. 324/2026 del 09/03/2026 ore 14.00
Validità 48 ore prossima emissione 10/03/2026

A cura del Servizio METEOMONT dell'ARMA dei CARABINIERI
In collaborazione con Servizio Meteorologico dell'Aeronautica militare

SITUAZIONE alle 14:00 del 09/03/2026

SITUAZIONE TIPO: situazione primaverile.

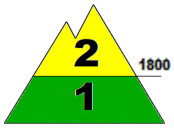

SITUAZIONE TIPO: pioggia su neve.

Quota neve (mslm)	Nord	Sud
	1700 - 1900	1900 - 2000

Altezza Neve (cm)	Neve al suolo	Neve Fresca	Quota (mslm)
	218	005	2275
	000	000	1520

VALANGHE OSSERVATE: Nessuna valanga.

PREVISIONI 10/03/2026

GRADO DI PERICOLO: MODERATO 2

SITUAZIONE TIPO: situazione primaverile.

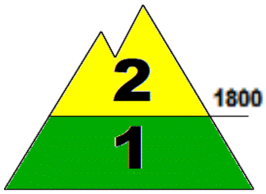



SITUAZIONE TIPO: pioggia su neve.

MANTO NEVOSO: La stabilità del manto nevoso è discreta su alcuni punti (aree) per versanti da nord a sud compresi al di sopra di 1800 mslm, possibili valanghe di dimensioni medie.
La stabilità del manto nevoso è discreta su alcuni punti (aree) per isolati pendii al di sotto di 1800 mslm, possibili valanghe di dimensioni piccole.

AVVERTENZE

In considerazione delle avverse condizioni meteorologiche previste , le attività al di fuori delle piste battute e segnalate sono sconsigliate.

SCALA EUROPEA DEL GRADO DI PERICOLO VALANGHE

LEGENDA PROBLEMA

Bollettino realizzato su scala sinottica-regionale (standard EAWS). La sua valutazione non può escludere in alcun modo la necessità di una seria e capace valutazione locale del pericolo (singolo pendio) che può essere anche sensibilmente diverso. Le previsioni meteorologiche sono relative all'orario UTC (per l'Italia +1 in inverno e +2 in estate).

MINISTERO DELLA DIFESA

meteomont
Servizio Nazionale di previsione neve e valanghe

EAWS EUROPEAN AVALANCHE WARNING SERVICES

CARABINIERI

P.N. ABRUZZO

PREVISIONE METEO

Quota		10/03/2026 h6:00	10/03/2026 h12:00	10/03/2026 h18:00
1000	Venti	02 Nodi da Nord	02 Nodi da S-Ovest	01 nodi da N-Ovest
	Temperature	+02 °C	+06 °C	+04 °C
	Temp.percepita	2 °C	6 °C	4 °C
2000	Venti	02 nodi da N-Ovest	01 nodi da N-Ovest	03 Nodi da Nord
	Temperature	+01 °C	+02 °C	+02 °C
	Temp.percepita	1 °C	2 °C	0 °C
3000	Venti	03 nodi da N-Ovest	04 nodi da N-Ovest	03 nodi da N-Ovest
	Temperature	-06 °C	-05 °C	-04 °C
	Temp.percepita	-9 °C	-8 °C	-6 °C
Zero termico		2000-2200 m.	2200-2400 m.	2200-2400 m.
Fenomeno		—		—
Stato del cielo				

LEGENDA FENOMENI

— Assenza Fenomeni · Nebbia · Foschia · Pioggia debole · Pioggia moderata · Pioggia forte · Temporali

Nevicata debole · Nevicata moderata · Nevicata forte

STATO DEL CIELO

Sereno · Poco nuvoloso · Nuvoloso · Molto nuvoloso · Coperto

Parametri meteonivometrici registrati presso i campi di rilevamento il 09/03/2026.

Località	Comune	Quota (m.s.l.m.)	Altezza neve (cm)	Neve caduta nelle 24 ore (cm)	Temp. Min (°C)	Temp. Max (°C)	Condizioni del tempo
FORCA D'ACERO	Pescasseroli (AQ)	1480	6	0	+1	+14	Assenza di precipitazioni
VALLE GELATA	Pescocostanzo (AQ)	1466	0	0	+2	+8	Assenza di precipitazioni
COPPO DELL'ORSO	Villetta Barrea (AQ)	1520	0	0	0	+3	Assenza di precipitazioni
LA PESCINA	Rivisondoli (AQ)	1470	0	0	0	+7	Assenza di precipitazioni
PIANO AREMOGNA	Roccaraso (AQ)	1456	0	0	+4	+9	Assenza di precipitazioni
MIMOLA	Scanno (AQ)	1495	0	0	+1	+16	Assenza di precipitazioni
MONTE GRECO (VERSANTE NORD OVEST) *	Barrea (AQ)	2275	218	6	N.P.	N.P.	Assenza di precipitazioni

(*) Rilievi fuori campo

L'INFORMAZIONE E' PREVENZIONE - LEGGI L'ATTUALE GRADO DI PERICOLO VALANGHE!

IL CAPO DEL CENTRO NAZIONALE METEOMONT
(Ten. Col. RFI Emanuela Gini)
FIRMA AUTOGRAFA OMESSA AI SENSI
DELL'ART.3 DEL D.LGS N.39/1993

Bollettino realizzato su scala sinottica-regionale (standard EAWS). La sua valutazione non può escludere in alcun modo la necessità di una seria e capace valutazione locale del pericolo (singolo pendio) che può essere anche sensibilmente diverso. Le previsioni meteorologiche sono relative all'orario UTC (per l'Italia +1 in inverno e +2 in estate).