Bulletin d'estimation du risque d'avalanche

(valable en dehors des pistes balisées et ouvertes)

MASSIF : Vercors

Rédigé le mardi 10 mars 2026 à 15h

Estimation des risques pour le : MERCREDI 11 MARS

MANTEAU NEIGEUX BIEN STABILISÉ.

1

1

N O E S

Indice de risque faible.

Départs spontanés : Rare plaque de fond.

Déclenchements provoqués : Rares.

Indices de risque : 5 très fort - 4 fort - 3 marqué - 2 limité - 1 faible -- En noir : les pentes les plus dangereuses

Stabilité du manteau neigeux

Situation avalancheuse typique : avalanches de fond

Les quelques cm de neige tombée sur la partie sommitale du massif ce mardi n'ont pas d'incidence sur la solidité du manteau neigeux.
Départs spontanés : peu probables mais on ne peut pas totalement exclure le risque qu'une fissure de reptation vienne à céder, emportant toute la neige en place jusqu'au sol (avalanche de taille 1 à 2).
Déclenchements provoqués : Peu probables.

Qualité de la neige

Qualification de l'enneigement : L'enneigement est très bon dans les versants ombragés au dessus de 1600 m

Limites skiables : vers 1300/1700 m.

Qualité de la neige mercredi : Manteau neigeux de type printanier recouvert d'une fine couche de neige fraîche au dessus de 1700 m environ, devenant collante avec les premiers rayons du soleil..

Aperçu météo pour le mercredi 11 mars

	nuit	matin	après-midi	soir
Pluie-Neige	1 600 m		1 700 m	1 600 m
Iso 0 °C	2 000 m	2 000 m	2 000 m	1 900 m
Vent 1500 m	↑ 20 km/h	↑ 25 km/h	↑ 30 km/h	↗ 15 km/h
Vent 2000 m	↑ 20 km/h	↗ 30 km/h	↗ 30 km/h	↗ 25 km/h

Épaisseur de neige hors-piste

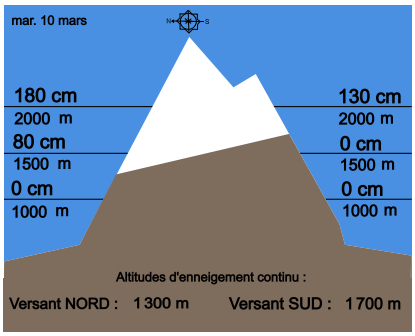

Précipitations à 1800 m

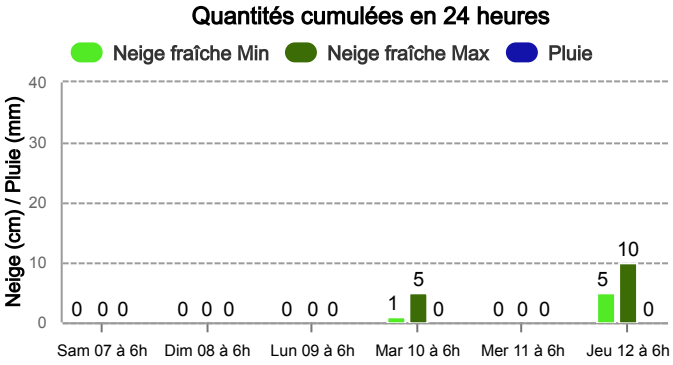

Tendance du jeudi 12 mars

1

Indice de risque faible

La petite couche de neige attendue en fin de journée/soirée de mercredi ne va pas modifier sensiblement la stabilité du manteau neigeux.

Pour consulter la vigilance en cours, veuillez vous rendre sur le site https://vigilance.meteofrance.fr/fr

Météo-France - 73 avenue de Paris, 94165 Saint-Mandé cedex - Contact : contact@meteo.fr

Rédigé par Météo-France avec la contribution des observateurs du réseau nivo-météorologiques. Partenariat : ANMSM (Maires de Stations de Montagne), DSF (Domaines Skiables de France), ADSP (Directeurs de Pistes et de la Sécurité des Stations de Sports d'Hiver) et autres acteurs de la montagne.

Bulletin neige & avalanches par téléphone au 0 892 68 10 20 Service 0,35 € / min + prix appel

RÉPUBLIQUE FRANÇAISE
Liberté Égalité Fraternité

METEO FRANCE
À VOS CÔTÉS, DANS UN CLIMAT QUI CHANGE

Bulletin d'estimation du risque d'avalanche

(valable en dehors des pistes balisées et ouvertes)

MASSIF : Vercors

Rédigé le mardi 10 mars 2026 à 15h

Conditions nivo-météo des 7 derniers jours

	mer. 04/03				jeu. 05/03				ven. 06/03				sam. 07/03				dim. 08/03				lun. 09/03				mar. 10/03			
	03h	09h	15h	21h	03h	09h	15h	21h	03h	09h	15h	21h	03h	09h	15h	21h	03h	09h	15h	21h	03h	09h	15h	21h	03h	09h	15h	21h
Météo																												
Vent (km/h)	10	15	15	10	15	25	20	15	25	20	20	15	20	5	10	10	10	20	20	15	25	35	35	35	35	25	25	15
à 2000m																												
Vent (km/h)	10	10	15	10	10	15	10	10	15	5	10	5	5	5	5	5	10	10	20	15	20	30	30	30	30	20	20	15
à 1500m																												

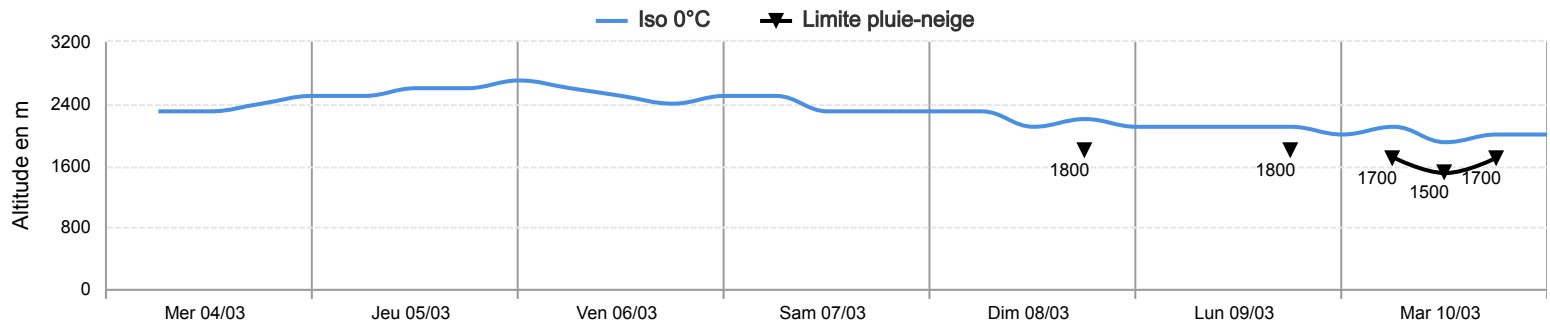

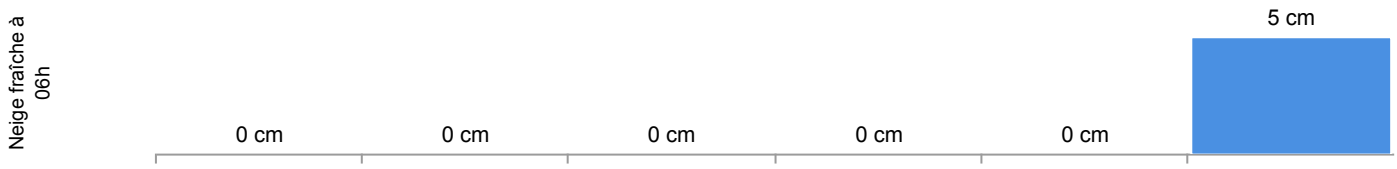

Risque d'avalanche	mer. 04/03	jeu. 05/03	ven. 06/03	sam. 07/03	dim. 08/03	lun. 09/03	mar. 10/03
	2	2	2	2	1	1	1

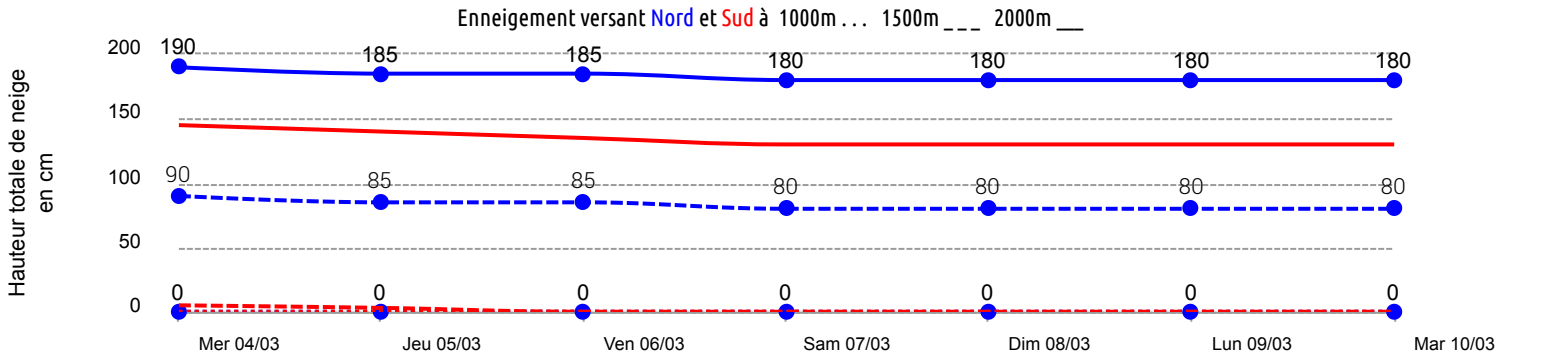

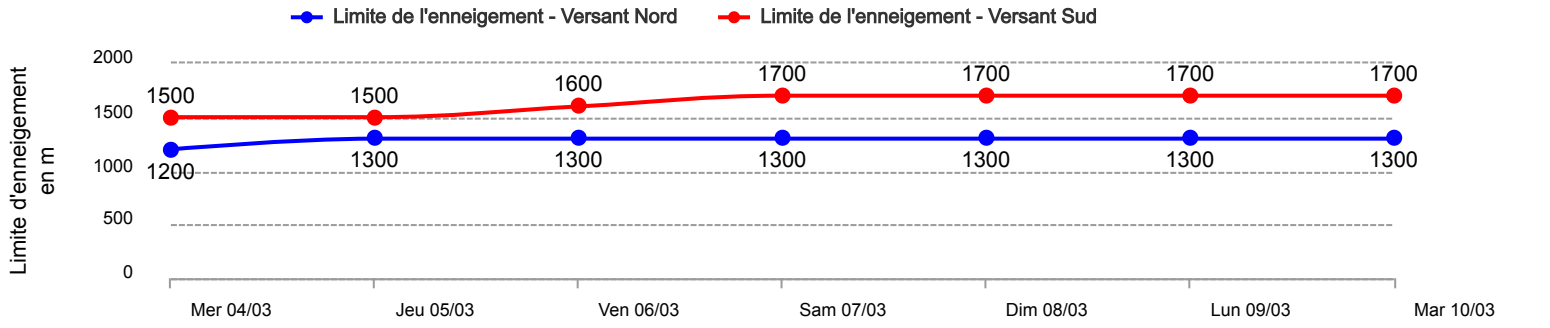

Pour consulter la vigilance en cours, veuillez vous rendre sur le site https://vigilance.meteofrance.fr/fr

Météo-France - 73 avenue de Paris, 94165 Saint-Mandé cedex - Contact : contact@meteo.fr

Rédigé par Météo-France avec la contribution des observateurs du réseau nivo-météorologiques. Partenariat : ANMSM (Maires de Stations de Montagne), DSF (Domaines Skiables de France), ADSP (Directeurs de Pistes et de la Sécurité des Stations de Sports d'Hiver) et autres acteurs de la montagne.

Bulletin neige & avalanches par téléphone au

0 892 68 10 20 Service 0,35 € / min + prix appel