Bulletin d'estimation du risque d'avalanche
(valable en dehors des pistes balisées et ouvertes)

MASSIF : Bauges

Rédigé le mardi 10 mars 2026 à 16h

Estimation des risques pour le : MERCREDI 11 MARS

MANTEAU NEIGEUX STABLE

1

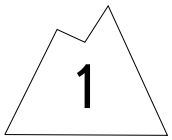

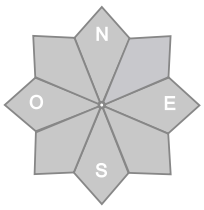

Indice de risque faible.

Départs spontanés : Rares plaques de fond

Déclenchements provoqués : Peu probables

Indices de risque : 5 très fort - 4 fort - 3 marqué - 2 limité - 1 faible -- En noir : les pentes les plus dangereuses

Stabilité du manteau neigeux

Situation avalancheuse typique : avalanches de fond

Départs spontanés :
* Rares **plaques de fond**, de jour comme de nuit, dans les pentes lisses et raides (zones herbeuses, dalles rocheuses). Présentes dans les versants **sud** et dans les versants **nord sous 2000 m**. Taille 1 à 2 (petite à moyenne).
* Une chute de grosse corniche est possible.

Déclenchements provoqués :
Peu probables.

Qualité de la neige

Enneigement :
Pour la saison, l'enneigement est correct.
On peut chausser les skis vers 1200/1300 m en nord, est et ouest et 1400/1700 m en sud.
Faible dépôt de poussières désertiques en surface du manteau neigeux.
Grosses corniches encore présentes.

Qualité de la neige mercredi :
* En versants Sud et Est : la neige s'humidifie légèrement au soleil en surface le matin.
* Ailleurs, la neige est croutée au-dessus de 1600 m, humide en dessous.

Aperçu météo pour le mercredi 11 mars

	nuit	matin	après-midi	soir

Belle matinée, le ciel se couvre progressivement, neige en soirée. De 0 à 8°C à 1500 m.

Pluie-Neige	1 600 m			1 500 m
Iso 0 °C	1 900 m	1 900 m	2 000 m	1 800 m
Vent 1500 m	↗ 20 km/h	↗ 20 km/h	↗ 30 km/h	↗ 30 km/h
Vent 2000 m	↗ 30 km/h	↗ 40 km/h	↗ 40 km/h	→ 40 km/h

Épaisseur de neige hors-piste

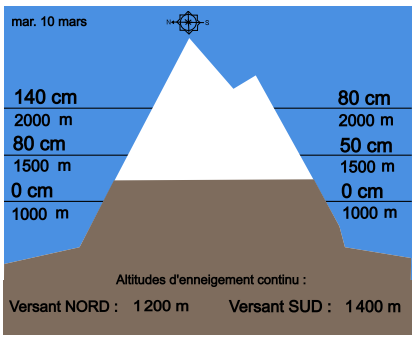

Précipitations à 1800 m

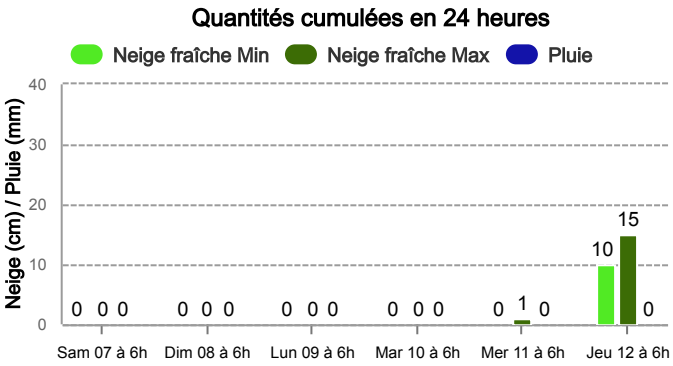

Tendance du jeudi 12 mars

Indice de risque limité

Risque en hausse. 10/15 cm de neige fraiche dans la nuit de mercredi à jeudi.

Pour consulter la vigilance en cours, veuillez vous rendre sur le site https://vigilance.meteofrance.fr/fr

Météo-France - 73 avenue de Paris, 94165 Saint-Mandé cedex - Contact : contact@meteo.fr

Rédigé par Météo-France avec la contribution des observateurs du réseau nivo-météorologiques. Partenariat : ANMSM (Maires de Stations de Montagne), DSF (Domaines Skiables de France), ADSP (Directeurs de Pistes et de la Sécurité des Stations de Sports d'Hiver) et autres acteurs de la montagne.

Bulletin neige & avalanches par téléphone au
0 892 68 10 20 Service 0,35 € / min + prix appel

Bulletin d'estimation du risque d'avalanche

(valable en dehors des pistes balisées et ouvertes)

MASSIF : Bauges

Rédigé le mardi 10 mars 2026 à 16h

Conditions nivo-météo des 7 derniers jours

	mer. 04/03				jeu. 05/03				ven. 06/03				sam. 07/03				dim. 08/03				lun. 09/03				mar. 10/03			
	03h	09h	15h	21h	03h	09h	15h	21h	03h	09h	15h	21h	03h	09h	15h	21h	03h	09h	15h	21h	03h	09h	15h	21h	03h	09h	15h	21h
Météo																												
Vent (km/h)	10	10	10	10	15	20	15	25	25	20	20	30	10	15	10	10	20	10	15	10	20	25	20	30	15	30	30	30
à 2000m																												
Vent (km/h)	5	5	5	5	10	15	10	20	15	10	10	25	5	10	5	10	10	5	10	5	5	20	15	25	10	20	20	20
à 1500m																												

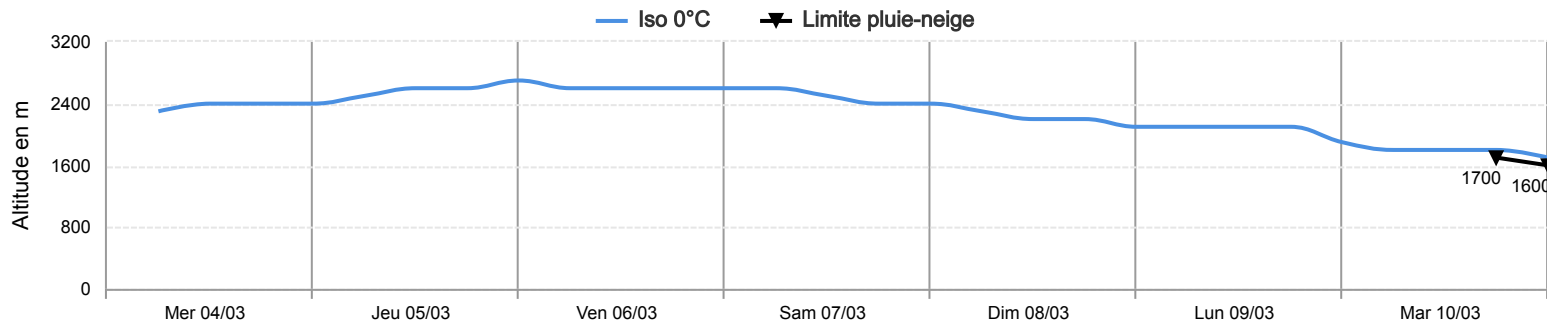

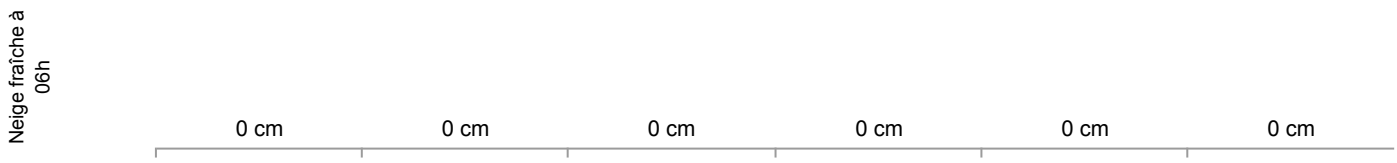

Risque d'avalanche	mer. 04/03	jeu. 05/03	ven. 06/03	sam. 07/03	dim. 08/03	lun. 09/03	mar. 10/03
	2	2	2	2	2	2	1

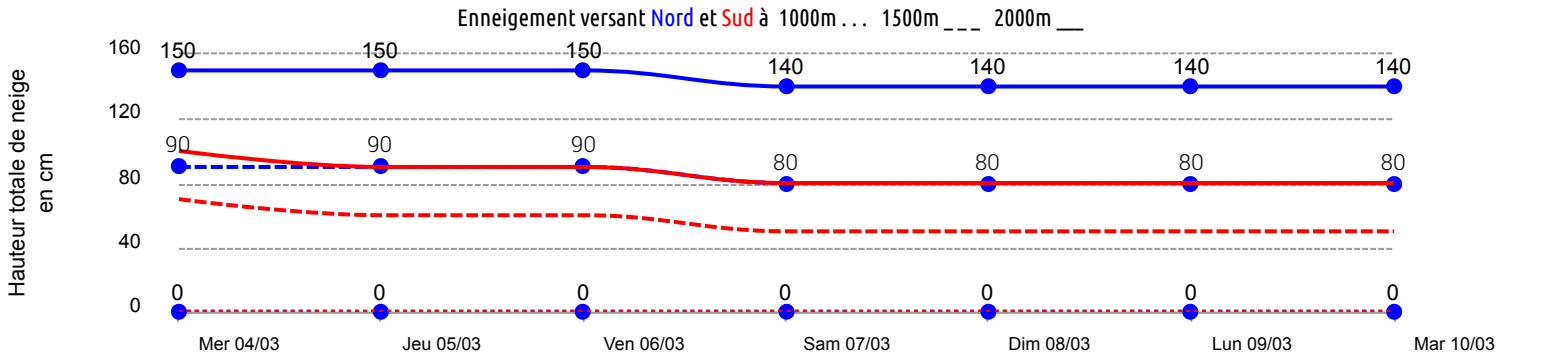

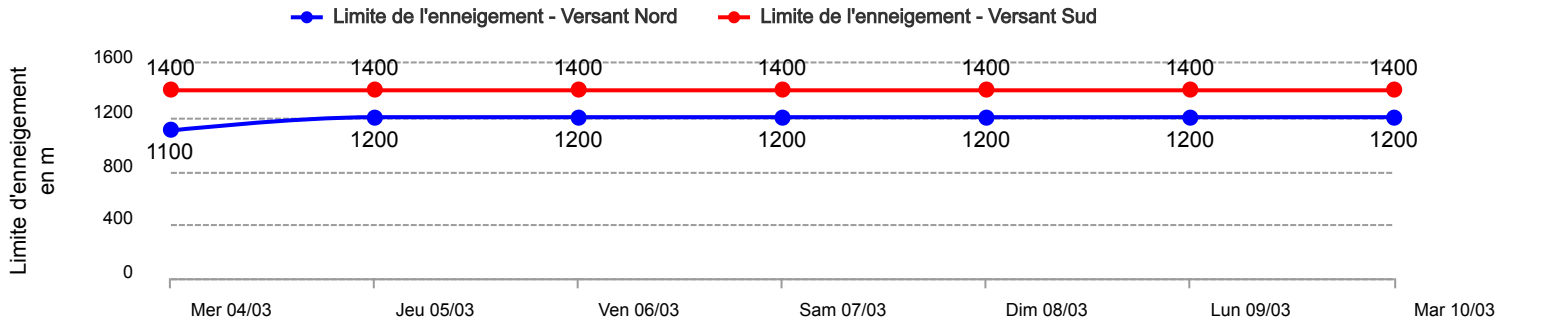

Pour consulter la vigilance en cours, veuillez vous rendre sur le site https://vigilance.meteofrance.fr/fr

Météo-France - 73 avenue de Paris, 94165 Saint-Mandé cedex - Contact : contact@meteo.fr

Bulletin neige & avalanches par téléphone au

0 892 68 10 20 Service 0,35 € / min + prix appel

Rédigé par Météo-France avec la contribution des observateurs du réseau nivo-météorologiques. Partenariat : ANMSM (Maires de Stations de Montagne), DSF (Domaines Skiables de France), ADSP (Directeurs de Pistes et de la Sécurité des Stations de Sports d'Hiver) et autres acteurs de la montagne.