Bulletin d'estimation du risque d'avalanche
(valable en dehors des pistes balisées et ouvertes)

MASSIF : Beaufortain

Rédigé le mardi 10 mars 2026 à 16h

Estimation des risques pour le : MERCREDI 11 MARS

SITUATION ASSEZ STABLE, RARES PLAQUES DURES EN SECTEURS FROIDS. RARES AVALANCHES DE GLISSEMENT.

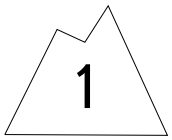

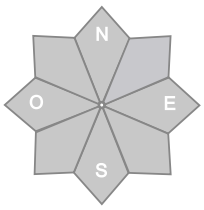

Indice de risque faible.

Départs spontanés : rares avalanches de glissement (plaques de fond).

Déclenchements provoqués : rares plaques dures.

Indices de risque : 5 très fort - 4 fort - 3 marqué - 2 limité - 1 faible -- En noir : les pentes les plus dangereuses

Stabilité du manteau neigeux

Situation avalancheuse typique : avalanches de fond

Déclenchement provoqués : rares plaques dures difficiles à déclencher dans les secteurs NE, Nord et NO d'altitude. On les trouve préférentiellement près des crêtes et des bosses soufflées dans la neige encore froide. Petite à moyenne avalanche.

Départs spontanés : rares avalanches de glissement, allant jusqu'à la taille moyenne car le manteau neigeux est épais. Plutôt sous les 2400m et sur terrains propices de type pentes herbeuses et dalles rocheuses.

Qualité de la neige

Enneigement : en général légèrement excédentaire pour la saison, mais en train de devenir déficitaire en basse montagne et en versants sud.

Limite skiable : encore skiable dès 1100/1200 m dans les prairies orientées nord, plutôt 1400/1500 m en sud pas trop raide.

Qualité de la neige : sous ~2000 m, neige de printemps avec regel incertain (croute potentiellement cassante le matin).
Plus haut, on trouve en nord une neige croutée sous 2500 m le matin (difficile à skier), encore froide au-dessus avec certains secteurs en vieille poudre agréable. En versants O/S/E, neige de printemps qui "décaille" lentement en journée à cause des nuages.

Aperçu météo pour le mercredi 11 mars

	nuit	matin	après-midi	soir

Le ciel se couvre en journée et une perturbation active arrive par l'ouest en fin d'après midi apportant de la neige dès la moyenne montagne.

Pluie-Neige	1 400 m		1 600 m	1 300 m
Iso 0 °C	1 900 m	2 000 m	1 900 m	1 600 m
Vent 2000 m	↑ 15 km/h	↗ 25 km/h	↗ 20 km/h	↗ 15 km/h
Vent 3000 m	↗ 35 km/h	↗ 45 km/h	↗ 40 km/h	→ 40 km/h

Épaisseur de neige hors-piste

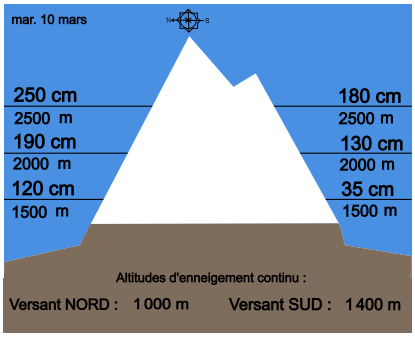

Précipitations à 1800 m

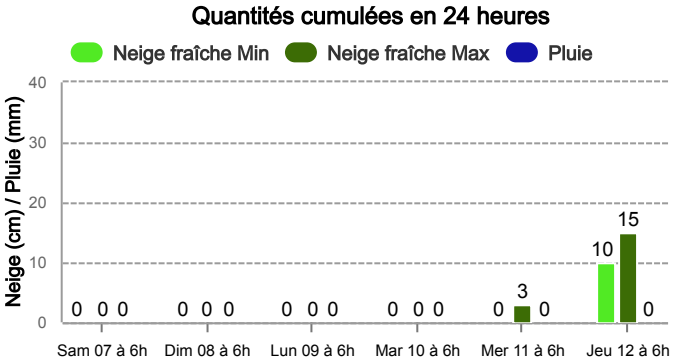

Tendance du jeudi 12 mars

Indice de risque limité

Chute de neige apportant 10/20 cm dans la nuit de mercredi à jeudi. Quelques petites instabilités temporaires dans la neige récente.

Pour consulter la vigilance en cours, veuillez vous rendre sur le site https://vigilance.meteofrance.fr/fr

Météo-France - 73 avenue de Paris, 94165 Saint-Mandé cedex - Contact : contact@meteo.fr

Rédigé par Météo-France avec la contribution des observateurs du réseau nivo-météorologiques. Partenariat : ANMSM (Maires de Stations de Montagne), DSF (Domaines Skiables de France), ADSP (Directeurs de Pistes et de la Sécurité des Stations de Sports d'Hiver) et autres acteurs de la montagne.

Bulletin neige & avalanches par téléphone au
0 892 68 10 20 Service 0,35 € / min + prix appel

RÉPUBLIQUE FRANÇAISE
Liberté Égalité Fraternité

METEO FRANCE
À VOS CÔTÉS, DANS UN CLIMAT QUI CHANGE

Bulletin d'estimation du risque d'avalanche
(valable en dehors des pistes balisées et ouvertes)

MASSIF : Beaufortain

Rédigé le mardi 10 mars 2026 à 16h

Conditions nivo-météo des 7 derniers jours

	mer. 04/03				jeu. 05/03				ven. 06/03				sam. 07/03				dim. 08/03				lun. 09/03				mar. 10/03			
	03h	09h	15h	21h	03h	09h	15h	21h	03h	09h	15h	21h	03h	09h	15h	21h	03h	09h	15h	21h	03h	09h	15h	21h	03h	09h	15h	21h
Météo																												
Vent (km/h)	15	15	20	20	20	25	30	30	30	30	25	20	20	25	25	15	20	20	20	20	20	20	30	30	25	25	20	30
à 3000m																												
Vent (km/h)	5	5	10	15	15	20	25	30	30	30	20	10	10	15	15	10	10	5	10	10	10	20	30	20	15	15	10	15
à 2000m																												

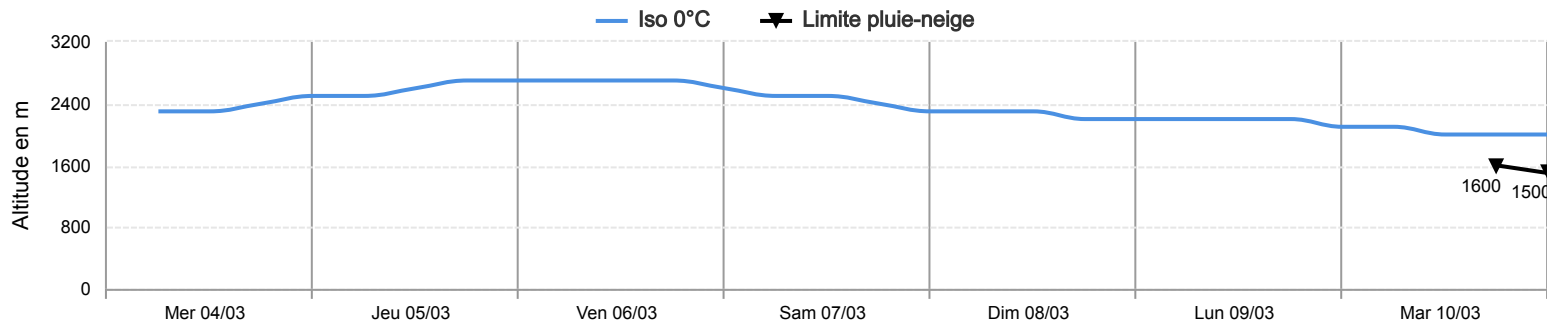

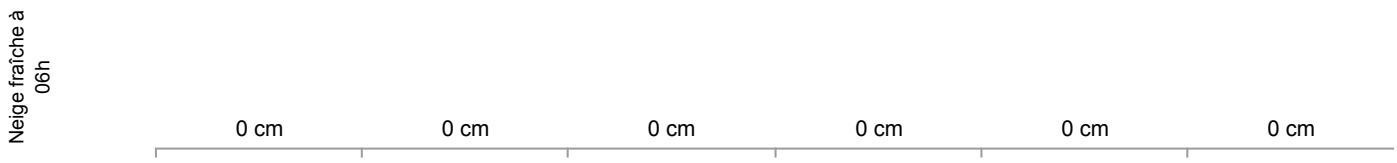

Risque d'avalanche	mer. 04/03	jeu. 05/03	ven. 06/03	sam. 07/03	dim. 08/03	lun. 09/03	mar. 10/03
	2	2	2	2	2	2	1

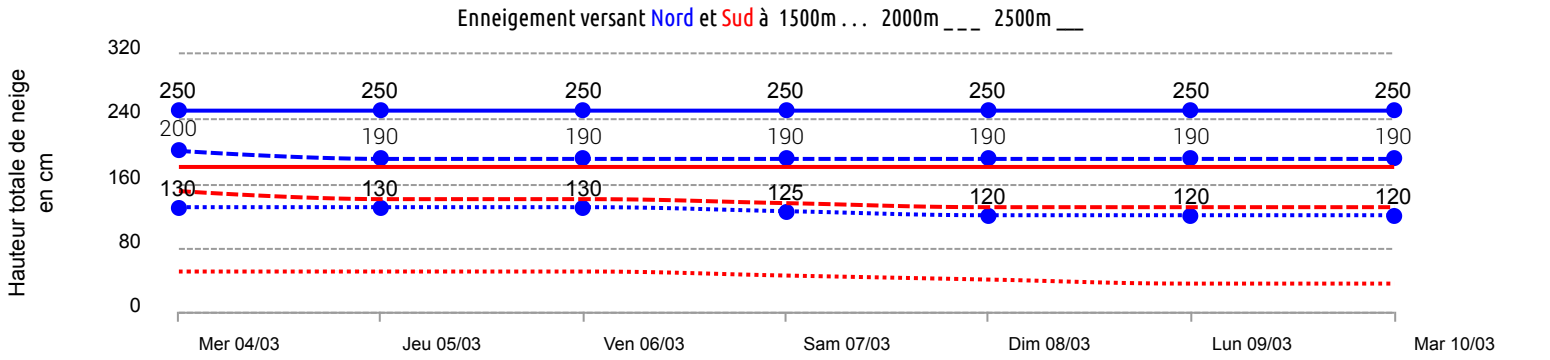

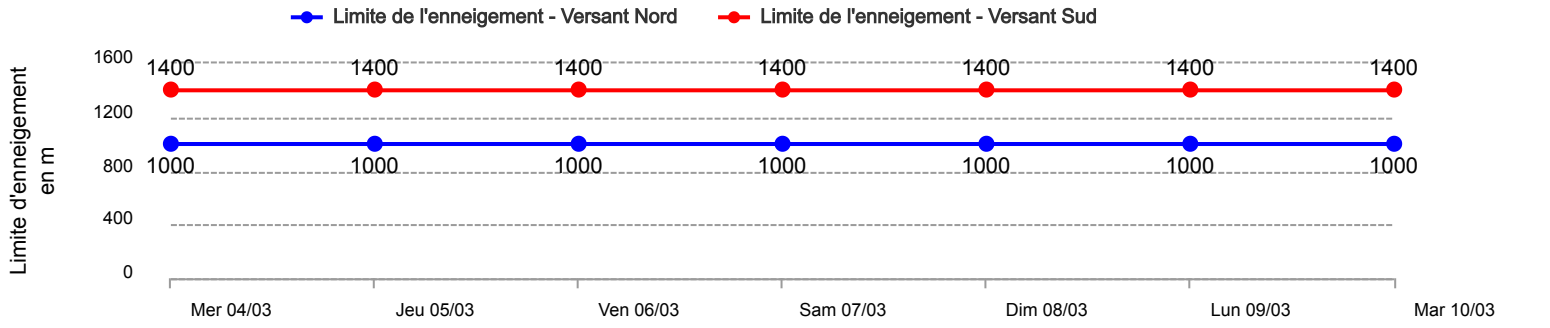

Pour consulter la vigilance en cours, veuillez vous rendre sur le site https://vigilance.meteofrance.fr/fr

Météo-France - 73 avenue de Paris, 94165 Saint-Mandé cedex - Contact : contact@meteo.fr

Rédigé par Météo-France avec la contribution des observateurs du réseau nivo-météorologiques. Partenariat : ANMSM (Maires de Stations de Montagne), DSF (Domaines Skiables de France), ADSP (Directeurs de Pistes et de la Sécurité des Stations de Sports d'Hiver) et autres acteurs de la montagne.

Bulletin neige & avalanches par téléphone au
0 892 68 10 20 Service 0,35 € / min + prix appel