Bulletin d'estimation du risque d'avalanche

(valable en dehors des pistes balisées et ouvertes)

MASSIF : Devoluy

Rédigé le mardi 10 mars 2026 à 16h

Estimation des risques pour le : MERCREDI 11 MARS

PLAQUES RÉSIDUELLES EN ALTITUDE, DIFFICILES À SOLLICITER - FAIBLE ACTIVITÉ NATURELLE

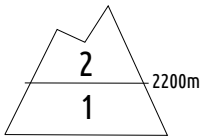

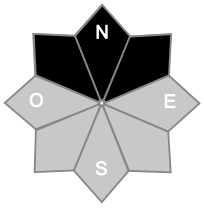

Au-dessus de 2200m indice de risque limité, plus bas indice faible.

Départs spontanés : rares avalanches de neige récente en pentes raides sous les éclaircies. Rares avalanches de fond.

Déclenchements provoqués : rares plaques superficielles. D'autres plus épaisses en altitude, difficiles à déclencher.

Indices de risque : 5 très fort - 4 fort - 3 marqué - 2 limité - 1 faible -- En noir : les pentes les plus dangereuses

Stabilité du manteau neigeux

Situation avalancheuse typique : neige humide pas de situation prédominante

Départs spontanés : - Rares avalanches de neige récente sous les éclaircies mercredi matin. Elles se produisent en pentes raides à proximité des rochers et sont de petite taille uniquement (taille 1). Activité limitée au vu de la couverture nuageuse s'épaississant rapidement dès la mi-journée.
- Une avalanche de fond n'est pas exclue sur les secteurs avec un sol favorable (pentes herbeuses, dalles rocheuses). Avalanches de taille moyenne (taille 2).

Déclenchements provoqués : - Plaques résiduelles dans la neige récente suite aux faibles chutes peu ventées de neige de mardi. Elles peuvent encore être faciles à déclencher dans les ubacs au-dessus de 2200 m environ, mais engendrent des avalanches de petite taille uniquement (taille 1). Des départs plus volumineux sont possibles en cas de sollicitation d'une couche fragile plus profondément enfouie.
- Un skieur peut éventuellement initier un départ superficiel de neige humide, dans une pente très raide suffisamment humidifiée.

Qualité de la neige

L'enneigement est encore excédentaire ou se rapproche des normales selon les secteurs. Les limites d'enneigement remontent dans les pentes bien exposées au soleil.

Limite d'enneigement skiable : vers 1300 m en ubacs, 1500/1600 m en adrets pas trop raides.

État de la neige de surface : mercredi matin, on retrouve quelques cm de neige récente déjà bien humidifiée jusqu'à 2000/2200 m. Elle peut rester froide et légère dans les ubacs au-dessus de 2200 m. Cette neige repose sur un manteau neigeux croûté dans les adrets, ainsi qu'en ubacs sous 2000/2200 m. Dans les pentes nord-ouest à nord-est au-dessus de 2200 m environ, neige encore froide, travaillée par les épisodes de vent passés, ou en neige ancienne meuble dans les secteurs abrités.

Aperçu météo pour le mercredi 11 mars

nuit	matin	après-midi	soir

Quelques éclaircies matinales puis le ciel se couvre rapidement. Passage perturbé en soirée avec un peu de neige au-dessus de 1500/1600 m.

Pluie-Neige				1 500 m
Iso 0 °C	1 800 m	1 800 m	2 000 m	1 800 m
Vent 2000 m	↑ 15 km/h	↑ 15 km/h	↗ 20 km/h	↘ 15 km/h
Vent 3000 m	↗ 15 km/h	→ 25 km/h	→ 30 km/h	→ 40 km/h

Épaisseur de neige hors-piste

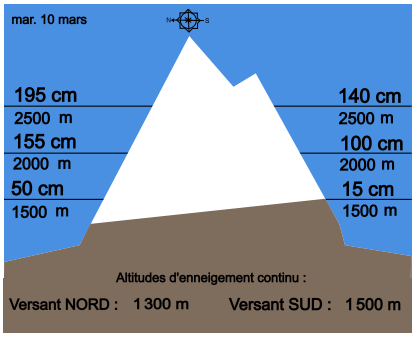

Précipitations à 1800 m

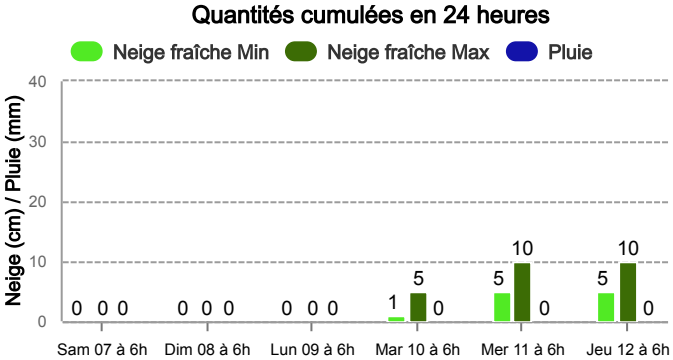

Tendance du jeudi 12 mars

Indice de risque limité

Maintien d'un risque limité. Les faibles chutes de neige prévues dans la nuit de mercredi à jeudi entrainent la formation de nouvelles plaques superficielles, mais cela ne justifie probablement pas une augmentation du risque.

Pour consulter la vigilance en cours, veuillez vous rendre sur le site https://vigilance.meteofrance.fr/fr

Météo-France - 73 avenue de Paris, 94165 Saint-Mandé cedex - Contact : contact@meteo.fr

Rédigé par Météo-France avec la contribution des observateurs du réseau nivo-météorologiques. Partenariat : ANMSM (Maires de Stations de Montagne), DSF (Domaines Skiables de France), ADSP (Directeurs de Pistes et de la Sécurité des Stations de Sports d'Hiver) et autres acteurs de la montagne.

Bulletin neige & avalanches par téléphone au 0 892 68 10 20 Service 0,35 € / min + prix appel

RÉPUBLIQUE FRANÇAISE
Liberté Égalité Fraternité

METEO FRANCE
À VOS CÔTÉS, DANS UN CLIMAT QUI CHANGE

Bulletin d'estimation du risque d'avalanche
(valable en dehors des pistes balisées et ouvertes)

MASSIF : Devoluy

Rédigé le mardi 10 mars 2026 à 16h

Conditions nivo-météo des 7 derniers jours

	mer. 04/03				jeu. 05/03				ven. 06/03				sam. 07/03				dim. 08/03				lun. 09/03				mar. 10/03			
	03h	09h	15h	21h	03h	09h	15h	21h	03h	09h	15h	21h	03h	09h	15h	21h	03h	09h	15h	21h	03h	09h	15h	21h	03h	09h	15h	21h
Météo																												
Vent (km/h)	5	0	5	15	15	25	20	25	45	55	45	40	35	20	30	30	30	25	25	30	25	30	40	50	40	25	15	15
à 3000m																												
Vent (km/h)	5	5	10	10	15	20	15	15	25	20	20	15	15	10	15	10	10	10	20	15	20	20	25	30	30	25	20	15
à 2000m																												

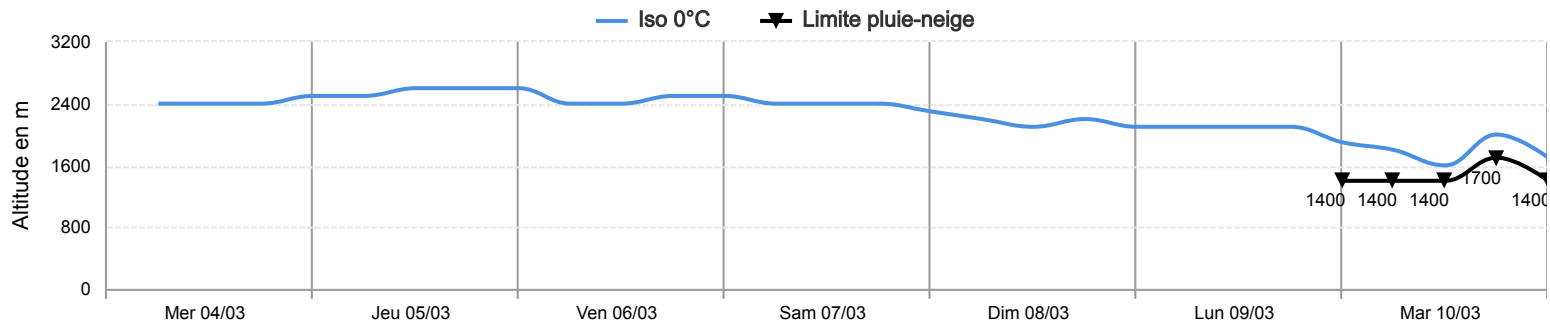

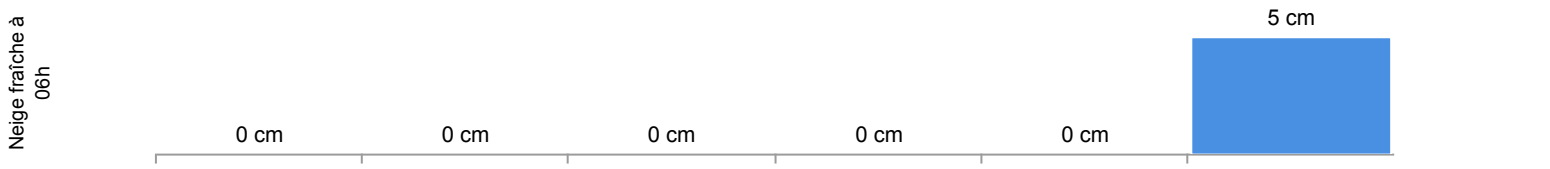

Risque d'avalanche	mer. 04/03	jeu. 05/03	ven. 06/03	sam. 07/03	dim. 08/03	lun. 09/03	mar. 10/03
	2	2	2	2	2	2	2

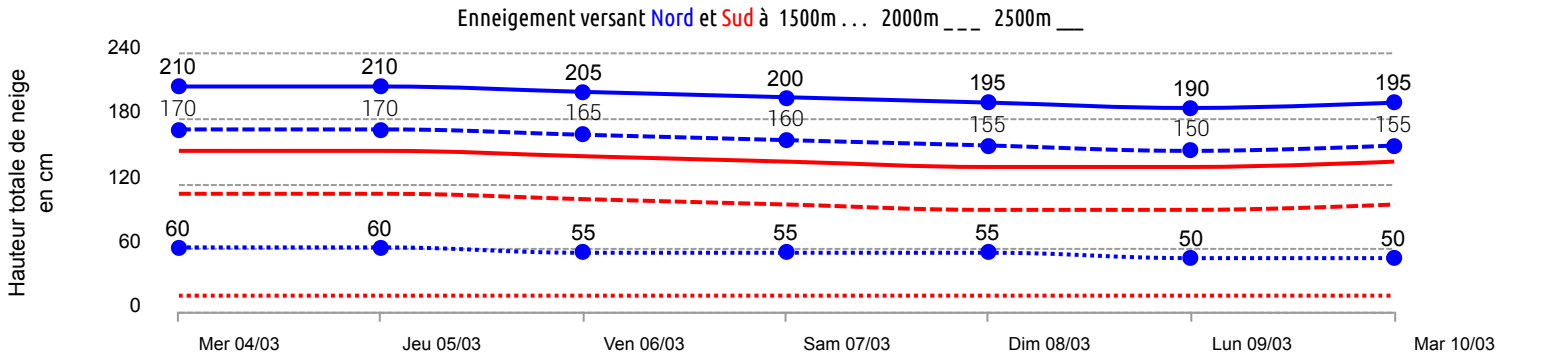

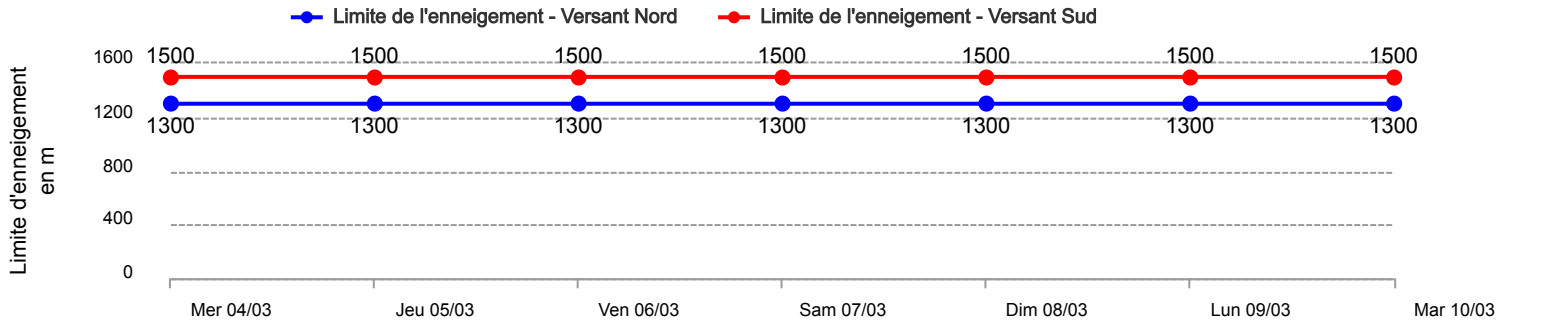

Pour consulter la vigilance en cours, veuillez vous rendre sur le site https://vigilance.meteofrance.fr/fr

Météo-France - 73 avenue de Paris, 94165 Saint-Mandé cedex - Contact : contact@meteo.fr

Rédigé par Météo-France avec la contribution des observateurs du réseau nivo-météorologiques. Partenariat : ANMSM (Maires de Stations de Montagne), DSF (Domaines Skiables de France), ADSP (Directeurs de Pistes et de la Sécurité des Stations de Sports d'Hiver) et autres acteurs de la montagne.

Bulletin neige & avalanches par téléphone au

0 892 68 10 20 Service 0,35 € / min + prix appel