Bulletin d'estimation du risque d'avalanche

(valable en dehors des pistes balisées et ouvertes)

MASSIF : Haut-Var Haut-Verdon

Rédigé le mardi 10 mars 2026 à 16h

Estimation des risques pour le : MERCREDI 11 MARS

QUELQUES INSTABILITÉS DANS LA NEIGE RÉCENTE, FAIBLE HUMIDIFICATION

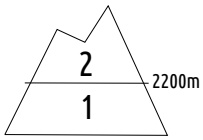

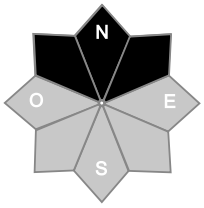

Au-dessus de 2200m indice de risque limité, plus bas indice faible.

Départs spontanés : rares départs superficiels de neige récente humidifiée.

Déclenchements provoqués : quelques plaques en place dans la neige récente.

Indices de risque : 5 très fort - 4 fort - 3 marqué - 2 limité - 1 faible -- En noir : les pentes les plus dangereuses

Stabilité du manteau neigeux

Situation avalancheuse typique : neige fraîche

Déclenchements provoqués :
- Quelques plaques sont possibles dans la neige récente : présentes principalement au dessus de 2200 m en versants nord-ouest à nord-est, elles sont le plus souvent d'aspect poudreux et peuvent être localement faciles à déclencher, elles sont de petite taille, ou parfois moyenne surtout dans le Haut-Var où les dernières chutes de neige ont étés un peu plus importantes.

Départs spontanés :
- rares départs ponctuels en neige récente humidifiée, possibles en pentes raides au fil de la course du soleil, généralement de petite taille, rarement moyenne.
- éventuellement une avalanche de glissement de taille moyenne, en pentes d'un large secteur sud, en terrain favorable (pentes herbeuses, dalles rocheuses).

Qualité de la neige

Enneigement plutôt excédentaire pour un début mars en général, notamment dans le Haut-Verdon.
Données observées : vers 2000 m, 170 cm en fond de vallon dans le Haut Verdon, 130 cm dans le Haut Var.

Enneigement skiable : vers 1400/1500 m en ubacs, 1800/1900 m en adrets peu pentus.

État de la neige en surface : petite couche de neige récente (autour de 15 cm, voire localement jusqu'à 25 cm dans le Haut-Var) restée sèche au dessus de 2200 m environ, voire plus haut en versants sud. En dessous, regel nocturne limité, avec reprise d'une humidification superficielle en cours de journée. Sur les crêtes, d'anciennes corniches épaisses côtoient des zones dégarnies.

Aperçu météo pour le mercredi 11 mars

	nuit	matin	après-midi	soir
Pluie-Neige				1 600 m
Iso 0 °C	2 100 m	2 200 m	2 200 m	2 100 m
Vent 2000 m	5 km/h	10 km/h	20 km/h	15 km/h
Vent 3000 m	15 km/h	30 km/h	40 km/h	40 km/h

Ciel souvent voilé le matin, devenant plus nuageux l'après-midi à l'avant d'un faible passage perturbé en début de nuit suivante.

Épaisseur de neige hors-piste

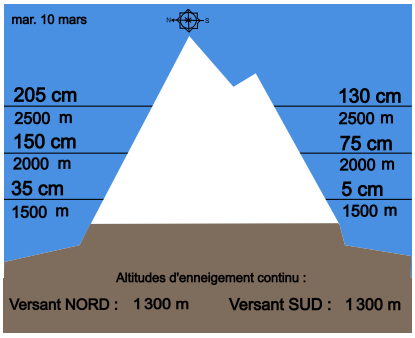

Précipitations à 1800 m

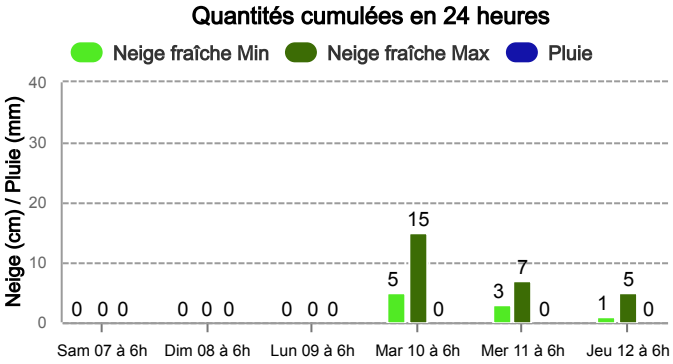

Tendance du jeudi 12 mars

Indice de risque limité

Risque restant limité, avec de nouvelles instabilités superficielles dans la neige fraîche après la perturbation de la nuit, et un peu d'humidification en journée.

Pour consulter la vigilance en cours, veuillez vous rendre sur le site https://vigilance.meteofrance.fr/fr

Météo-France - 73 avenue de Paris, 94165 Saint-Mandé cedex - Contact : contact@meteo.fr

Rédigé par Météo-France avec la contribution des observateurs du réseau nivo-météorologiques. Partenariat : ANMSM (Maires de Stations de Montagne), DSF (Domaines Skiables de France), ADSP (Directeurs de Pistes et de la Sécurité des Stations de Sports d'Hiver) et autres acteurs de la montagne.

Bulletin neige & avalanches par téléphone au 0 892 68 10 20 Service 0,35 € / min + prix appel

RÉPUBLIQUE FRANÇAISE
Liberté Égalité Fraternité

METEO FRANCE
À VOS CÔTÉS, DANS UN CLIMAT QUI CHANGE

Bulletin d'estimation du risque d'avalanche

(valable en dehors des pistes balisées et ouvertes)

MASSIF : Haut-Var Haut-Verdon

Rédigé le mardi 10 mars 2026 à 16h

Conditions nivo-météo des 7 derniers jours

	mer. 04/03				jeu. 05/03				ven. 06/03				sam. 07/03				dim. 08/03				lun. 09/03				mar. 10/03			
	03h	09h	15h	21h	03h	09h	15h	21h	03h	09h	15h	21h	03h	09h	15h	21h	03h	09h	15h	21h	03h	09h	15h	21h	03h	09h	15h	21h
Météo																												
Vent (km/h)	10	10	10	10	15	20	25	45	65	60	55	50	35	30	25	15	20	15	15	15	15	20	30	50	40	25	20	20
à 3000m	←	↖	↗	↘	←	↑	↖	←	←	←	↖	←	←	←	↖	←	↖	↖	↖	↖	↑	↑	↖	↖	↑	↑	↑	↗
Vent (km/h)	5	5	10	5	20	20	25	40	45	40	40	35	25	20	15	10	15	10	15	10	15	15	20	35	5	15	20	5
à 2000m	←	←	↗	↙	←	←	←	←	←	←	←	←	←	↖	←	←	←	↖	↖	←	←	↖	↖	←	↓	↑	↑	↑

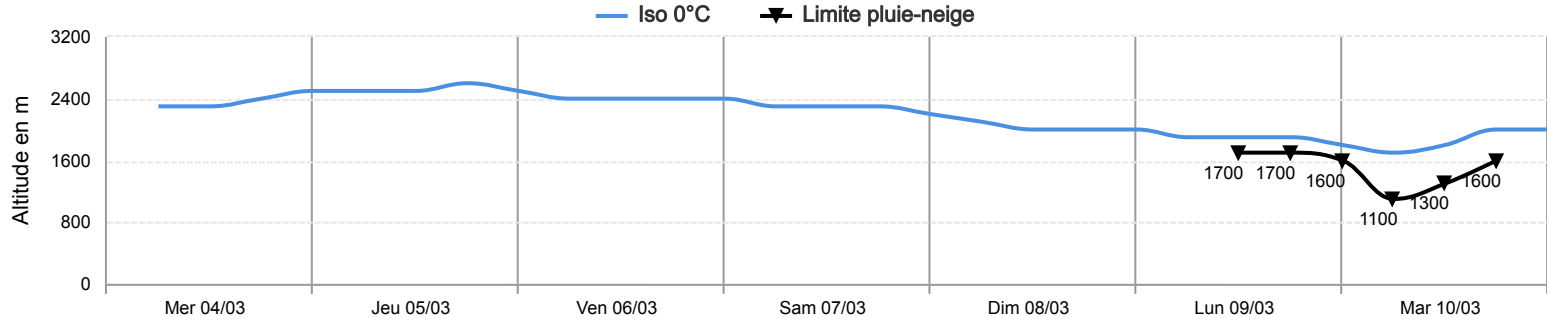

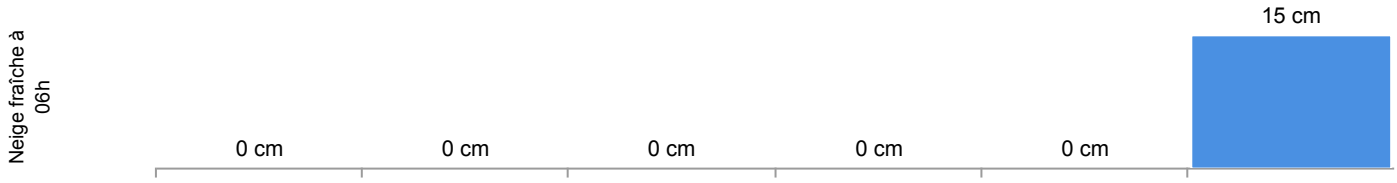

Risque d'avalanche	mer. 04/03	jeu. 05/03	ven. 06/03	sam. 07/03	dim. 08/03	lun. 09/03	mar. 10/03
	2	2	2	2	2	1	2

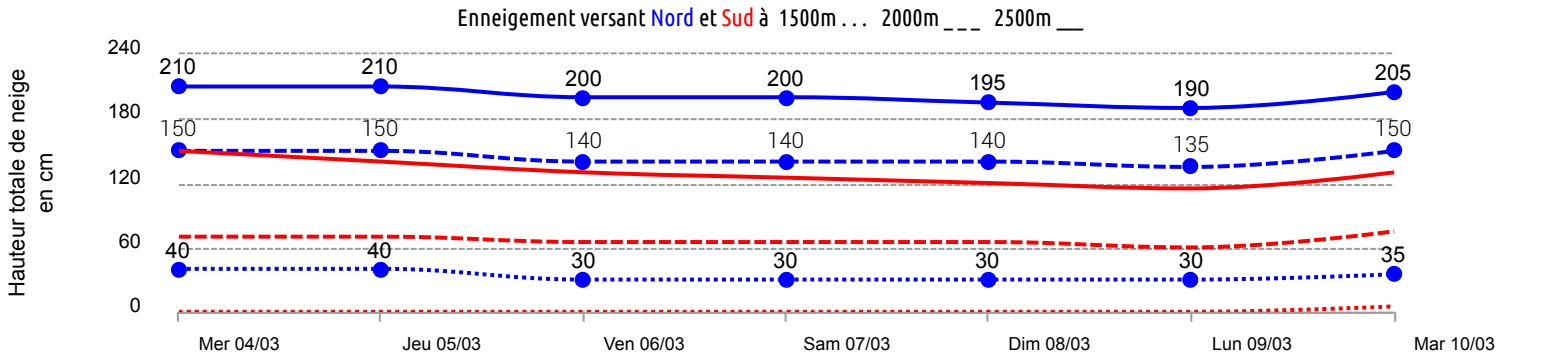

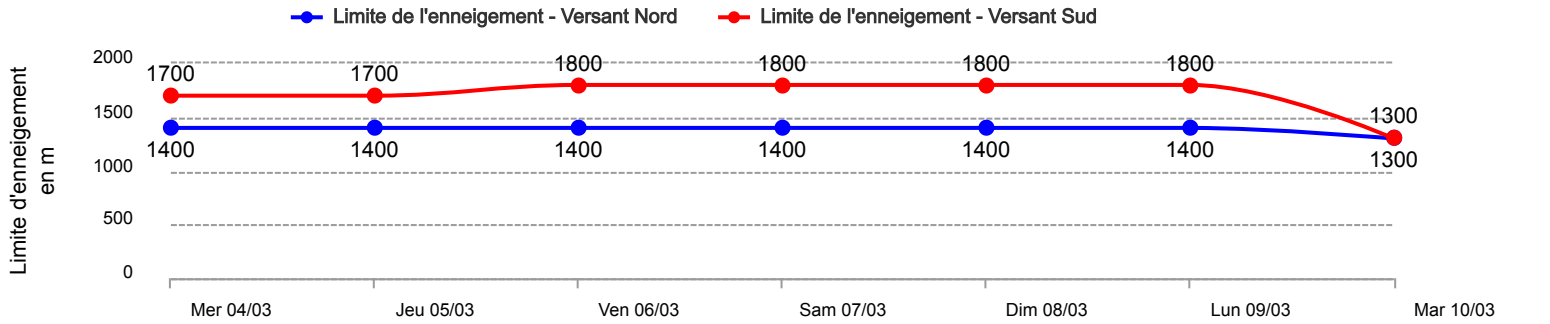

Pour consulter la vigilance en cours, veuillez vous rendre sur le site https://vigilance.meteofrance.fr/fr

Météo-France - 73 avenue de Paris, 94165 Saint-Mandé cedex - Contact : contact@meteo.fr

Rédigé par Météo-France avec la contribution des observateurs du réseau nivo-météorologiques. Partenariat : ANMSM (Maires de Stations de Montagne), DSF (Domaines Skiables de France), ADSP (Directeurs de Pistes et de la Sécurité des Stations de Sports d'Hiver) et autres acteurs de la montagne.

Bulletin neige & avalanches par téléphone au

0 892 68 10 20 Service 0,35 € / min + prix appel