Bulletin d'estimation du risque d'avalanche
(valable en dehors des pistes balisées et ouvertes)

MASSIF : Haute-Maurienne

Rédigé le mardi 10 mars 2026 à 16h

Estimation des risques pour le : MERCREDI 11 MARS

COUCHES FRAGILES ENFOUIES GÉNÉRALISÉES MAIS PEU RÉACTIVES : LE MANTEAU EST PLUTÔT BIEN STABILISÉ.

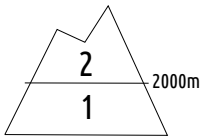

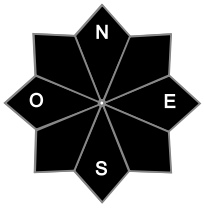

Au-dessus de 2000m indice de risque limité, plus bas indice faible.

Départs spontanés : peu probables.

Déclenchements provoqués : rares plaques sur couches fragiles persistantes, tous versants.

Indices de risque : 5 très fort - 4 fort - 3 marqué - 2 limité - 1 faible -- En noir : les pentes les plus dangereuses

Stabilité du manteau neigeux

Situation avalancheuse typique : couche fragile persistante

Déclenchements provoqués : des **couches fragiles persistantes** (grains anguleux) sont **enfouies de manière généralisée dans le manteau** (en tous versants, même en sud de haute altitude). Leur sollicitation est très peu probable la majorité du temps mais devient possible :
- en versants NO/N/NE, au-dessus de 2000 m, dans les zones moins enneigées (abords de crête, croupes dégarnies) où une rare plaque dure peut subsister. Taille 1 à 2 (petite à moyenne).
- en versants ensoleillés à haute altitude, en journée lorsque la neige ramollit en surface, ce qui facilite la sollicitation d'une couche fragile enfouie (scénario moins probable que les jours précédents grâce aux nuages). Taille 2, plus rarement 3 (grande).

Départs spontanés : peu probables. Exceptionnellement une avalanche de glissement sur terrain propice.

Qualité de la neige

Enneigement : légèrement excédentaire pour la saison en moyenne montagne, mais en train de devenir déficitaire en basse montagne et en versants sud. Et très déficitaire en haute montagne près de la crête frontalière, voire carrément absent de certains cols ou faces très exposées au vent.

Limite skiable : encore skiable dès 1100/1200 m dans les prairies orientées nord, plutôt 1500/1600 m en sud pas trop raide.

Qualité de la neige : il est tombé très localement, près de la frontière italienne, 5/10 cm de neige fraîche. Cette neige s'est déjà humidifiée en tous versants sous 2500 m, et sera croutée ce mercredi matin.
Dans les autres secteurs, on trouve une neige croutée en nord jusqu'à 2500 m, encore froide plus haut mais généralement travaillée par le vent (rares secteurs en vieille poudre agréable). En versants O/S/E, neige de printemps qui "décaille" lentement en journée à cause des nuages.

Aperçu météo pour le mercredi 11 mars

nuit	matin	après-midi	soir

Le ciel se couvre en journée et une légère dégradation arrive par l'ouest en soirée apportant quelques flocons dès la moyenne montagne.

Pluie-Neige				
Iso 0 °C	2 000 m	2 100 m	2 000 m	1 800 m
Vent 2500 m	10 km/h	10 km/h	30 km/h	25 km/h
Vent 3500 m	20 km/h	25 km/h	50 km/h	40 km/h

Épaisseur de neige hors-piste

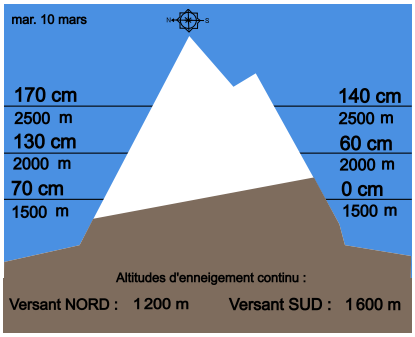

Précipitations à 1800 m

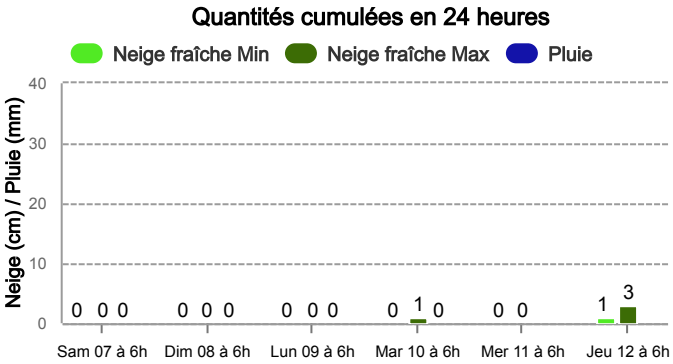

Tendance du jeudi 12 mars

Indice de risque limité

Temps sec avec des éclaircies de plus en plus larges au fil de la journée, le risque est stationnaire.

Pour consulter la vigilance en cours, veuillez vous rendre sur le site https://vigilance.meteofrance.fr/fr

Météo-France - 73 avenue de Paris, 94165 Saint-Mandé cedex - Contact : contact@meteo.fr

Rédigé par Météo-France avec la contribution des observateurs du réseau nivo-météorologiques. Partenariat : ANMSM (Maires de Stations de Montagne), DSF (Domaines Skiables de France), ADSP (Directeurs de Pistes et de la Sécurité des Stations de Sports d'Hiver) et autres acteurs de la montagne.

Bulletin neige & avalanches par téléphone au 0 892 68 10 20 Service 0,35 € / min + prix appel

RÉPUBLIQUE FRANÇAISE
Liberté Égalité Fraternité

METEO FRANCE
À VOS CÔTÉS, DANS UN CLIMAT QUI CHANGE

Bulletin d'estimation du risque d'avalanche
(valable en dehors des pistes balisées et ouvertes)
MASSIF : Haute-Maurienne

Rédigé le mardi 10 mars 2026 à 16h

Conditions nivo-météo des 7 derniers jours

	mer. 04/03				jeu. 05/03				ven. 06/03				sam. 07/03				dim. 08/03				lun. 09/03				mar. 10/03			
	03h	09h	15h	21h	03h	09h	15h	21h	03h	09h	15h	21h	03h	09h	15h	21h	03h	09h	15h	21h	03h	09h	15h	21h	03h	09h	15h	21h
Météo																												
Vent (km/h)	10	10	10	10	15	20	20	25	30	35	30	30	25	30	25	25	20	15	15	15	15	15	20	25	30	30	30	20
à 3500m																												
Vent (km/h)	5	5	5	5	15	20	20	25	30	30	25	25	20	25	20	15	20	15	15	15	15	15	20	30	25	20	15	10
à 2500m																												

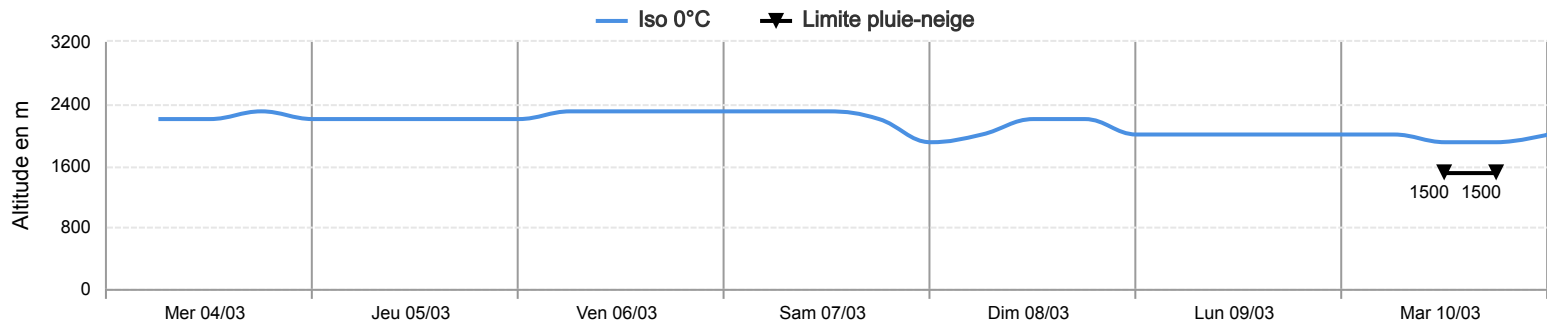

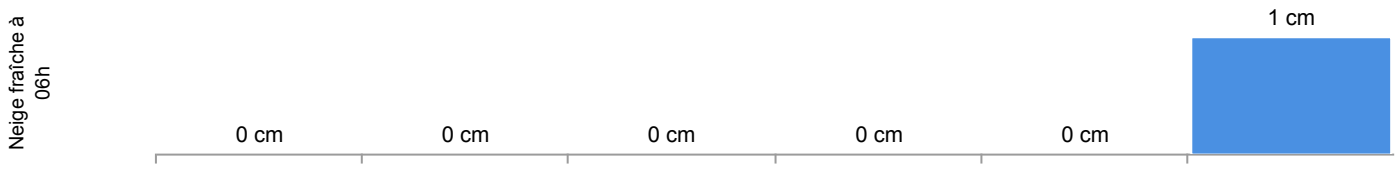

Risque d'avalanche	mer. 04/03	jeu. 05/03	ven. 06/03	sam. 07/03	dim. 08/03	lun. 09/03	mar. 10/03
	2	2	2	2	2	2	2

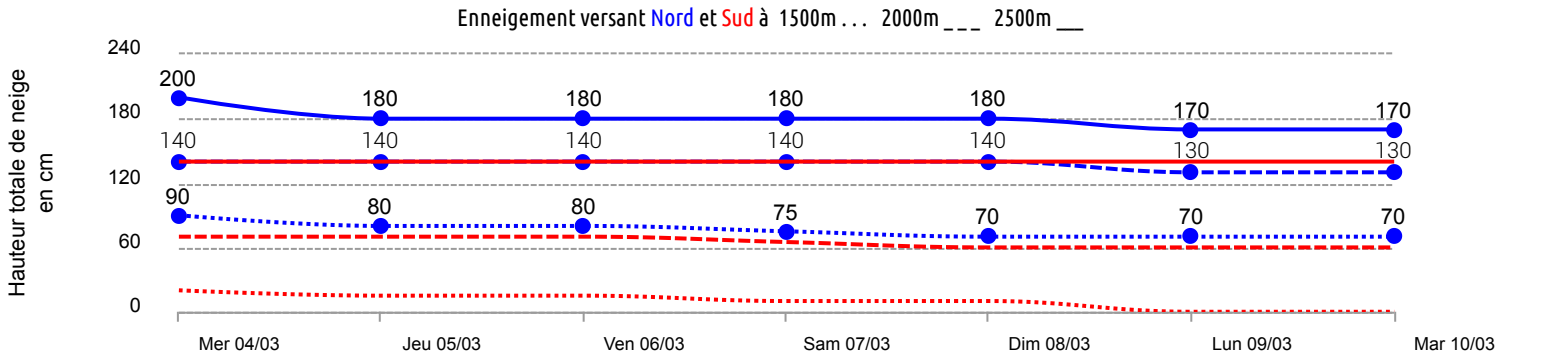

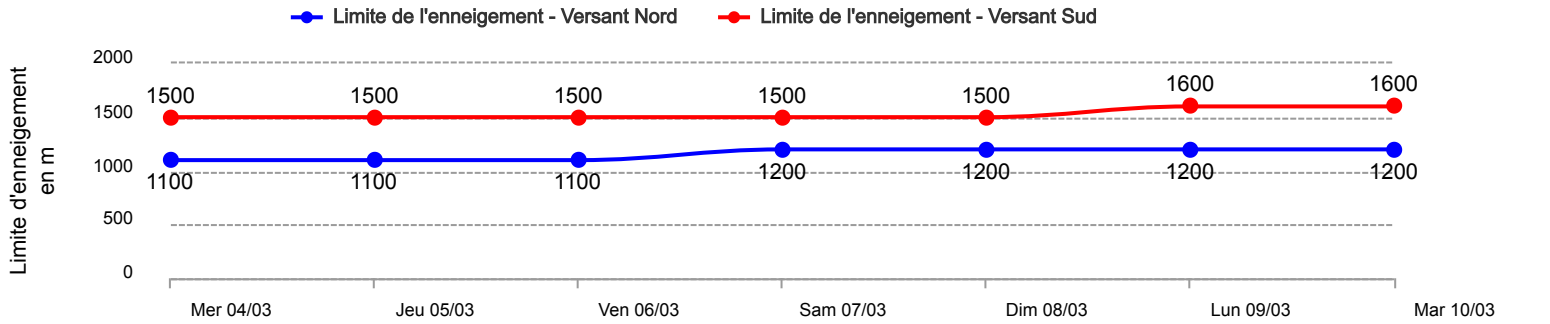

Pour consulter la vigilance en cours, veuillez vous rendre sur le site https://vigilance.meteofrance.fr/fr

Météo-France - 73 avenue de Paris, 94165 Saint-Mandé cedex - Contact : contact@meteo.fr

Rédigé par Météo-France avec la contribution des observateurs du réseau nivo-météorologiques. Partenariat : ANMSM (Maires de Stations de Montagne), DSF (Domaines Skiables de France), ADSP (Directeurs de Pistes et de la Sécurité des Stations de Sports d'Hiver) et autres acteurs de la montagne.

Bulletin neige & avalanches par téléphone au
0 892 68 10 20 Service 0,35 € / min + prix appel